# Bulletin d'estimation du risque d'avalanche
## (valable en dehors des pistes balisées et ouvertes)

# MASSIF : Oisans

Rédigé le dimanche 22 février 2026 à 16h

## Estimation des risques pour le : LUNDI 23 FÉVRIER

**PLAQUES DURES EN HAUT ET NEIGE LOURDE EN BAS.**

3

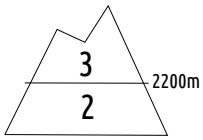


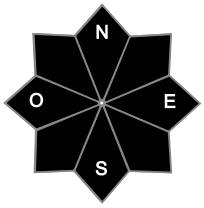


Au-dessus de 2200m indice de risque marqué, plus bas indice limité.

**Départs spontanés :** Avalanches de glissement sur les pentes herbeuses raides de moyenne montagne.

**Déclenchements provoqués :** Plaques dures en altitude.

Indices de risque : 5 très fort - 4 fort - 3 marqué - 2 limité - 1 faible -- En noir : les pentes les plus dangereuses

## Stabilité du manteau neigeux

**Situation avalancheuse typique :** neige ventée — avalanches de fond

Le soleil et le fort redoux ont humidifié et considérablement densifié le manteau neigeux dans la quasi totalité des pentes de moyenne montagne et dans les versants ensoleillés jusqu'à plus de 2400 m. Par contre, dans les versants ombragés de haute montagne, les conditions sont plus hivernales.
Déclenchements provoqués : le vent de nord de ces deux derniers jours a déplacé de grandes quantités de neige meuble et formé de grosses accumulations en altitude. Elles sont devenues plus difficiles à déclencher au passage d'un skieur, mais si une plaque dure vient à céder, les volumes de neige peuvent être importants avec des cassures de plus d'un mètre.
Départs spontanés : ils concernent surtout les reptations observées depuis deux jours, cédant de manière aléatoire en emportant toute la neige jusqu'au sol. Les versants au soleil en dessous de 2000/2200 m sont les plus propices pour ces avalanches dont l'ampleur ne devrait pas excéder.la taille 2.

## Qualité de la neige

**Qualification de l'enneigement :** l'enneigement est bon pour la saison dès 1200 m, puis abondant au dessus de 1500 m environ, notamment dans les combes d'altitude. Les crêtes sont parfois dégarnies ou parfois fortement cornichées.

**Limites skiables :** vers 1100/1300 m.

**Qualité de la neige lundi :** Neige lourde au moins jusqu'à 2000 m, croûtée en début de journée et s'humidifiant dans les versants ensoleillés. Dans les ubacs d'altitude, la neige est souvent soufflée. Dans les combes abritées du vent, on trouve de grosses quantités de neige profonde.

## Aperçu météo pour le lundi 23 février

| | nuit | matin | après-midi | soir |
|---|---|---|---|---|
| **Pluie-Neige** | | | | |
| **Iso 0 °C** | 3 000 m | 2 800 m | 2 900 m | 3 100 m |
| **Vent 2500 m** | 15 km/h | 20 km/h | 25 km/h | 20 km/h |
| **Vent 3500 m** | 35 km/h | 35 km/h | 35 km/h | 25 km/h |

## Épaisseur de neige hors-piste

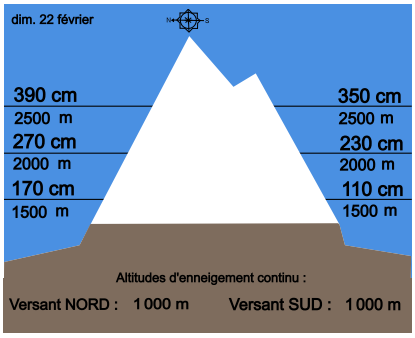


## Précipitations à 1800 m

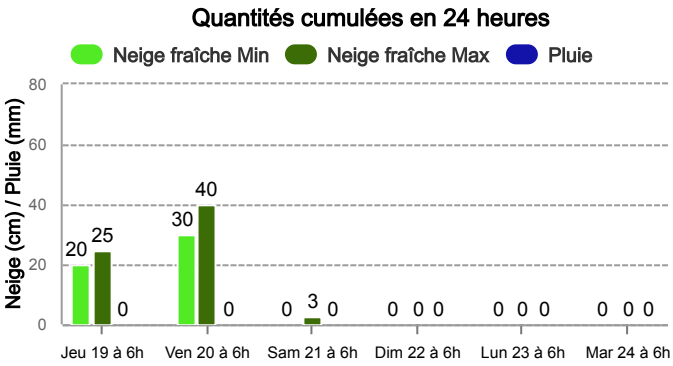


## Tendance du mardi 24 février

3

**Indice de risque marqué**

Mardi, temps ensoleillé et très doux, accélérant l'humidification du manteau neigeux dans les adrets. Dans les versants ombragés, toujours une problématique de plaque dure en haute montagne.

Pour consulter la vigilance en cours, veuillez vous rendre sur le site https://vigilance.meteofrance.fr/fr

Météo-France - 73 avenue de Paris, 94165 Saint-Mandé cedex - Contact : contact@meteo.fr

Rédigé par Météo-France avec la contribution des observateurs du réseau nivo-météorologiques. Partenariat : ANMSM (Maires de Stations de Montagne), DSF (Domaines Skiables de France), ADSP (Directeurs de Pistes et de la Sécurité des Stations de Sports d'Hiver) et autres acteurs de la montagne.

Bulletin neige & avalanches par téléphone au 0 892 68 10 20 Service 0,35 € / min + prix appel

RÉPUBLIQUE FRANÇAISE
*Liberté Égalité Fraternité*

METEO FRANCE
À VOS CÔTÉS, DANS UN CLIMAT QUI CHANGE

# Bulletin d'estimation du risque d'avalanche

## (valable en dehors des pistes balisées et ouvertes)

# MASSIF : Oisans

Rédigé le dimanche 22 février 2026 à 16h

## Conditions nivo-météo des 7 derniers jours

| | lun. 16/02 | | | | mar. 17/02 | | | | mer. 18/02 | | | | jeu. 19/02 | | | | ven. 20/02 | | | | sam. 21/02 | | | | dim. 22/02 | | | |
|---|---|---|---|---|---|---|---|---|---|---|---|---|---|---|---|---|---|---|---|---|---|---|---|---|---|---|---|---|
| | 03h | 09h | 15h | 21h | 03h | 09h | 15h | 21h | 03h | 09h | 15h | 21h | 03h | 09h | 15h | 21h | 03h | 09h | 15h | 21h | 03h | 09h | 15h | 21h | 03h | 09h | 15h | 21h |
| Météo | | | | | | | | | | | | | | | | | | | | | | | | | | | | |
| Vent (km/h) | 100 | 105 | 110 | 115 | 120 | 100 | 85 | 50 | 45 | 35 | 30 | 90 | 50 | 40 | 60 | 75 | 85 | 80 | 80 | 80 | 70 | 65 | 65 | 50 | 35 | 30 | 35 | 30 |
| à 3500m | | | | | | | | | | | | | | | | | | | | | | | | | | | | |
| Vent (km/h) | 65 | 70 | 80 | 85 | 85 | 75 | 50 | 35 | 30 | 15 | 20 | 65 | 35 | 25 | 35 | 45 | 70 | 70 | 70 | 75 | 55 | 45 | 40 | 35 | 20 | 15 | 15 | 15 |
| à 2500m | | | | | | | | | | | | | | | | | | | | | | | | | | | | |

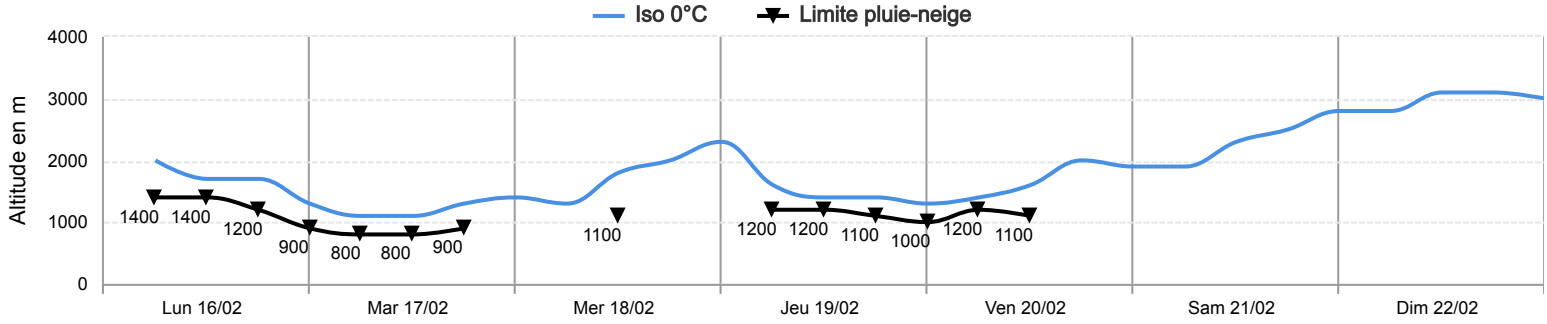


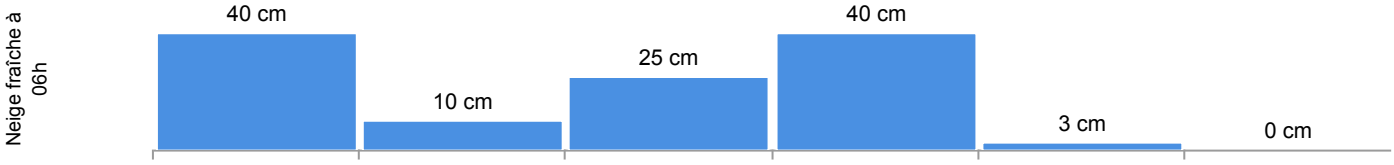


| Risque d'avalanche | lun. 16/02 | mar. 17/02 | mer. 18/02 | jeu. 19/02 | ven. 20/02 | sam. 21/02 | dim. 22/02 |
|---|---|---|---|---|---|---|---|
| | 4 | 4 | 4 | 5 | 5 | 4 | 3 |

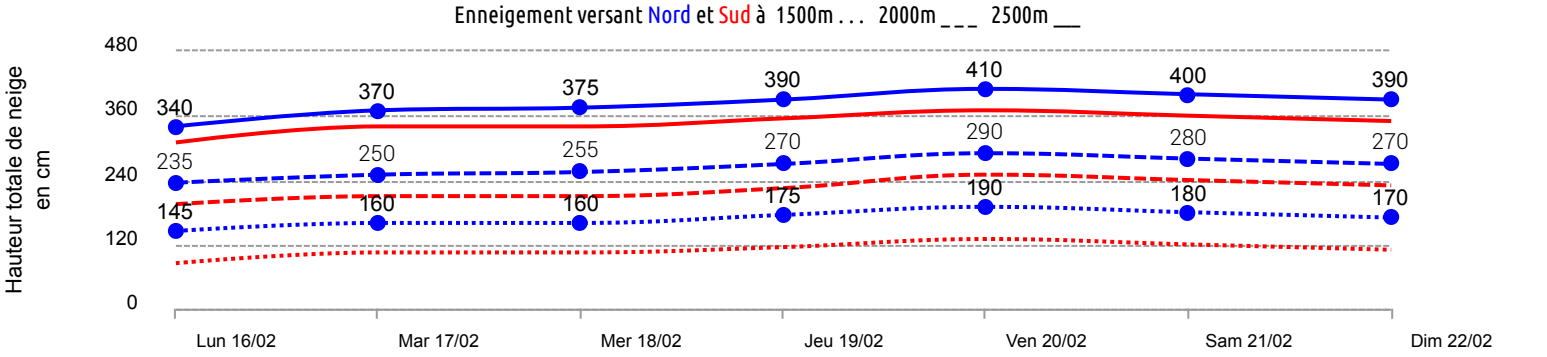


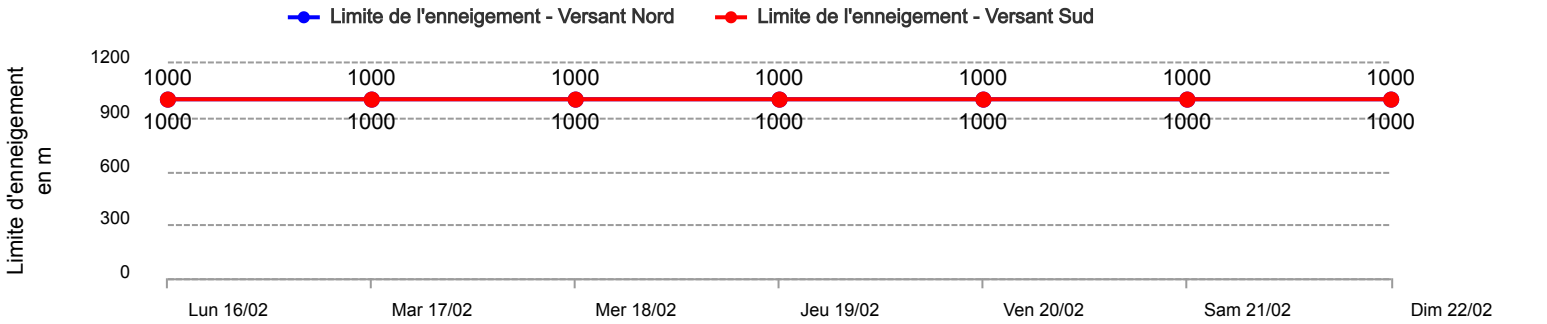


Pour consulter la vigilance en cours, veuillez vous rendre sur le site https://vigilance.meteofrance.fr/fr


Météo-France - 73 avenue de Paris, 94165 Saint-Mandé cedex - Contact : contact@meteo.fr


Rédigé par Météo-France avec la contribution des observateurs du réseau nivo-météorologiques. Partenariat : ANMSM (Maires de Stations de Montagne), DSF (Domaines Skiables de France), ADSP (Directeurs de Pistes et de la Sécurité des Stations de Sports d'Hiver) et autres acteurs de la montagne.

Bulletin neige & avalanches par téléphone au

0 892 68 10 20 Service 0,35 € / min + prix appel