RÉPUBLIQUE FRANÇAISE
Liberté Égalité Fraternité

METEO FRANCE
À VOS CÔTÉS, DANS UN CLIMAT QUI CHANGE

Bulletin d'estimation du risque d'avalanche
(valable en dehors des pistes balisées et ouvertes)
MASSIF : Pays-Basque

Rédigé le dimanche 22 février 2026 à 16h

Estimation des risques pour le : LUNDI 23 FÉVRIER

NEIGE VENTÉE DANS LES SECTEUR OMBRAGÉS AU PLUS HAUT DU MASSIF, S'HUMIDIFIANT PROGRESSIVEMENT, HUMIDIFICATION AILLEURS.

2

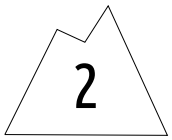

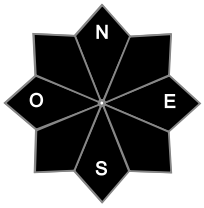

Indice de risque limité.

Départs spontanés : Dans la neige humide, avalanches de fond possibles.

Déclenchements provoqués : Plaques à vent au plus haut du massif.

Indices de risque : 5 très fort - 4 fort - 3 marqué - 2 limité - 1 faible -- En noir : les pentes les plus dangereuses

Stabilité du manteau neigeux

Situation avalancheuse typique : neige ventée neige humide

Déclenchements provoqués : **Au plus haut du massif,** des plaques à vent peuvent encore persister surtout dans les pentes raides des secteurs où la neige est restée froide (pentes ombragées). Elles restent facilement déclenchables par un simple skieur et leur déclenchement peut engendrer des cassures linéaires moyennes à plus rarement grandes. Ces plaques tendent à s'humidifier progressivement au fil de la journée avec la douceur ambiante.
Partout ailleurs, un simple skieur peut déclencher une petite avalanche, parfois une avalanche moyenne dans la neige humide.

Départs spontanés : Des avalanches petites à moyennes sont attendues dans la neige humide, concernant d'abord les pentes raides Est à Sud-Est dans la matinée, puis rapidement tous les versants au fil de la journée et de l'ensoleillement.
Au plus haut du massif, de petites avalanches ou des moyennes sont possibles, plus rarement des grandes, par déclenchement des plaques décrites ci-dessus.
Des avalanches moyennes à parfois grandes peuvent aussi se produire en partant des accumulations entre **1600 et 2100m**: avalanches de fond lorsque l'humidification du manteau neigeux se fait en profondeur, ou bien chute d'une corniche fragilisée au soleil entraînant la neige en contrebas.

Autres : quelques **reptations possibles** et **apparition de quelques fissures** au **pied des pentes raides** ou proche des **ruptures de pentes**. Corniches en place fragilisées par l'humidification.

Qualité de la neige

Enneigement : en retrait progressif ce lundi avec la douceur ambiante poursuivant celle du week-end et le soleil qui est bien installé. Il débute vers 1300m en Nord, 1400m en Sud. Crêtes, cols et sommets pelés en expositions Ouest, en neige dure à très dure partout ailleurs.
Limites skiables : à partir de 1300 à 1400m au petit matin suivant les versants, car sans sous-couche en dessous. La neige fond progressivement en versants ensoleillés, la limite remonte vers 1500/1600m dans la journée. Fonte plus lente à l'ombre.
État de la neige : Au petit matin, neige travaillée par le vent dans les versants ombragés au plus haut du massif, la neige est dure et regelée partout ailleurs. La neige regelée ramollit au soleil et s'humidifie progressivement. La neige reste le plus souvent en l'état au plus haut du massif dans les secteurs ombragés, très travaillée par le vent.

Aperçu météo pour le lundi 23 février

nuit	matin	après-midi	soir

Temps sec sous un ciel voilé le matin, bien dégagé ensuite. Vent faible.

Pluie-Neige				
Iso 0 °C	3 200 m	3 300 m	3 400 m	3 300 m
Vent 1000 m	← 5 km/h	← 5 km/h	↘ 10 km/h	↑ 10 km/h
Vent 2000 m	↗ 15 km/h	← 15 km/h	↑ 15 km/h	↑ 25 km/h

Épaisseur de neige hors-piste

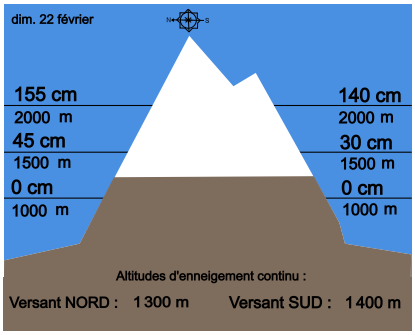

Précipitations à 1800 m

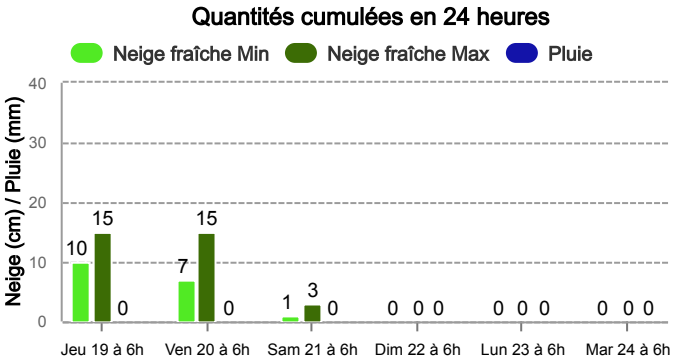

Tendance du mardi 24 février

2

Indice de risque limité

Risque stationnaire. Plaques dans les secteurs ombragés au plus haut du massif s'humidifiant progressivement. Poursuite de l'humidification ailleurs.

Pour consulter la vigilance en cours, veuillez vous rendre sur le site https://vigilance.meteofrance.fr/fr

Météo-France - 73 avenue de Paris, 94165 Saint-Mandé cedex - Contact : contact@meteo.fr

Rédigé par Météo-France avec la contribution des observateurs du réseau nivo-météorologiques. Partenariat : ANMSM (Maires de Stations de Montagne), DSF (Domaines Skiables de France), ADSP (Directeurs de Pistes et de la Sécurité des Stations de Sports d'Hiver) et autres acteurs de la montagne.

Bulletin neige & avalanches par téléphone au
0 892 68 10 20 Service 0,35 € / min + prix appel

RÉPUBLIQUE FRANÇAISE
Liberté Égalité Fraternité

METEO FRANCE
À VOS CÔTÉS, DANS UN CLIMAT QUI CHANGE

Bulletin d'estimation du risque d'avalanche
(valable en dehors des pistes balisées et ouvertes)
MASSIF : Pays-Basque

Rédigé le dimanche 22 février 2026 à 16h

Conditions nivo-météo des 7 derniers jours

	lun. 16/02				mar. 17/02				mer. 18/02				jeu. 19/02				ven. 20/02				sam. 21/02				dim. 22/02			
	03h	09h	15h	21h	03h	09h	15h	21h	03h	09h	15h	21h	03h	09h	15h	21h	03h	09h	15h	21h	03h	09h	15h	21h	03h	09h	15h	21h
Météo																												
Vent (km/h)	80	80	70	75	85	50	60	40	45	95	110	90	95	80	55	40	30	20	25	20	20	10	15	20	25	25	25	25
à 2000m	↘	↘	↘	↘	↘	→	↗	↗	↑	↑	↗	→	↘	↘	→	→	↘	↓	↓	↓	←	↻	↘	↗	↑	↑	↗	→
Vent (km/h)	35	35	30	35	25	15	20	10	15	40	70	50	55	40	25	15	15	10	15	10	5	2	10	10	15	15	10	5
à 1000m	↗	→	↘	↓	↘	↘	↓	↑	↑	↑	↑	→	↘	↘	↘	↓	↘	↓	↓	↙	↙	↻	↻	↑	↑	↗	↓	↓

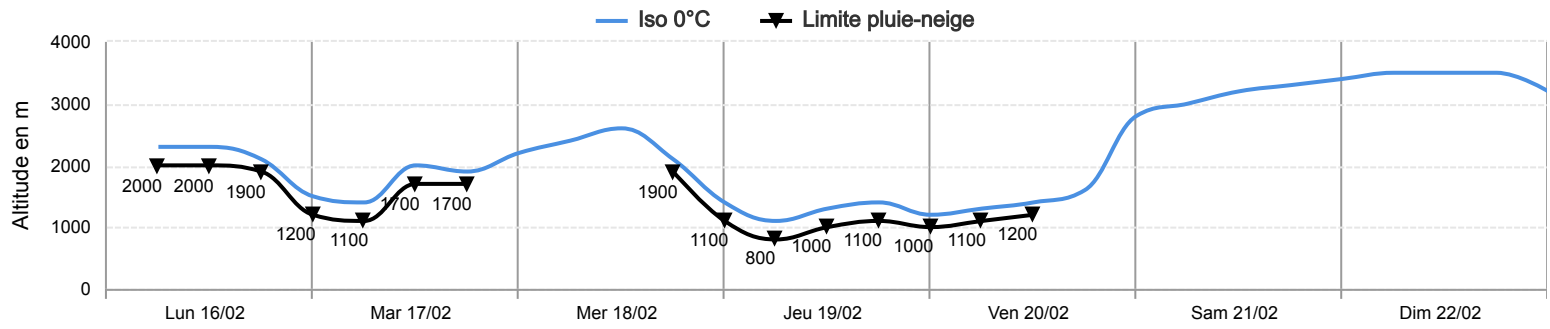

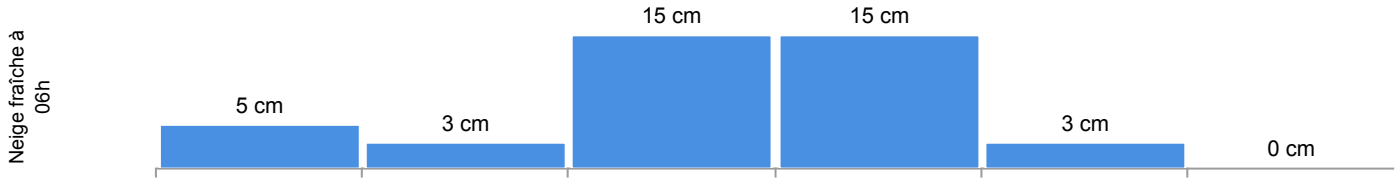

Risque d'avalanche	lun. 16/02	mar. 17/02	mer. 18/02	jeu. 19/02	ven. 20/02	sam. 21/02	dim. 22/02
	3	3	2	3	3	3	2

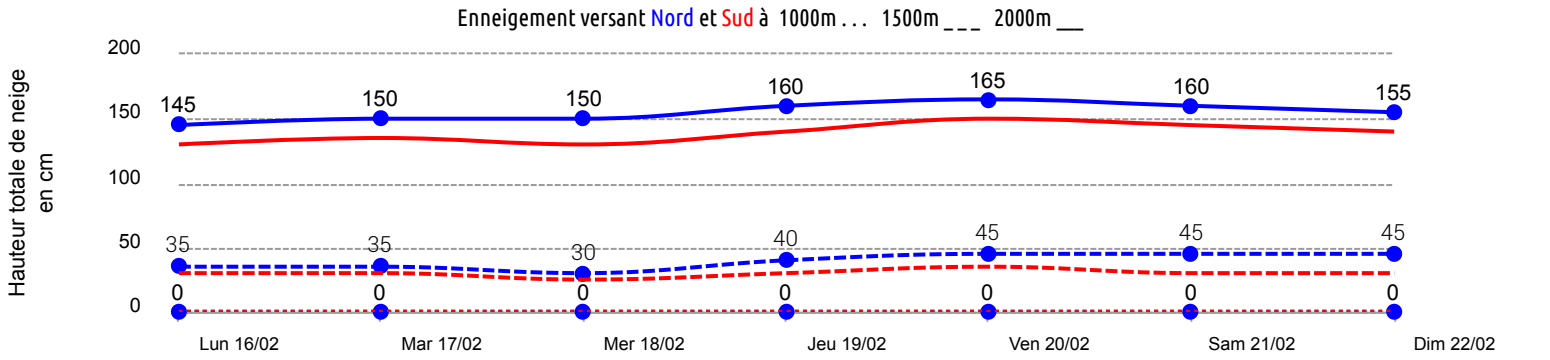

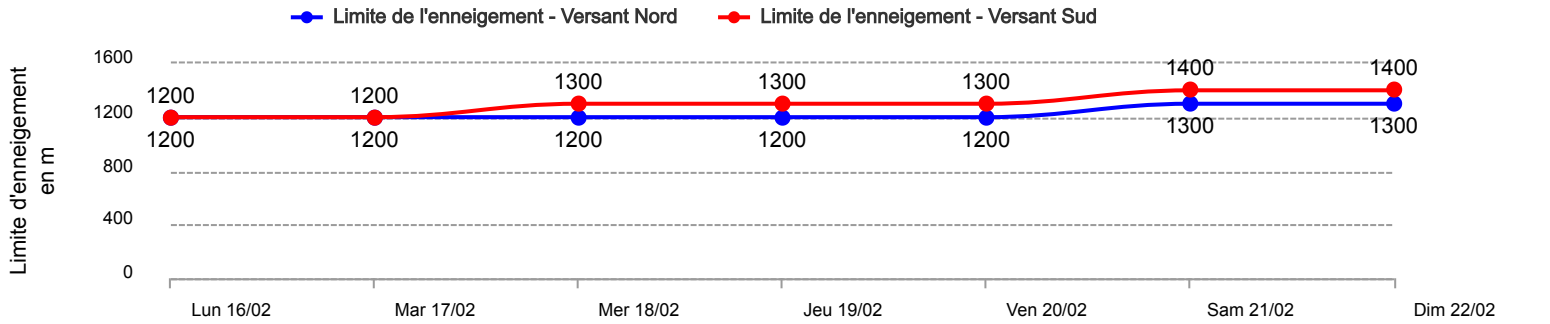

Pour consulter la vigilance en cours, veuillez vous rendre sur le site https://vigilance.meteofrance.fr/fr

Météo-France - 73 avenue de Paris, 94165 Saint-Mandé cedex - Contact : contact@meteo.fr

Rédigé par Météo-France avec la contribution des observateurs du réseau nivo-météorologiques. Partenariat : ANMSM (Maires de Stations de Montagne), DSF (Domaines Skiables de France), ADSP (Directeurs de Pistes et de la Sécurité des Stations de Sports d'Hiver) et autres acteurs de la montagne.

Bulletin neige & avalanches par téléphone au
0 892 68 10 20 Service 0,35 € / min + prix appel