RÉPUBLIQUE FRANÇAISE
Liberté Égalité Fraternité

METEO FRANCE
À VOS CÔTÉS, DANS UN CLIMAT QUI CHANGE

Bulletin d'estimation du risque d'avalanche

(valable en dehors des pistes balisées et ouvertes)

MASSIF : Ubaye

Rédigé le dimanche 22 février 2026 à 16h

Estimation des risques pour le : LUNDI 23 FÉVRIER

PLAQUES DANS LA NEIGE RÉCENTE, DÉPARTS NATURELS EN NEIGE HUMIDE

3

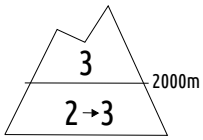

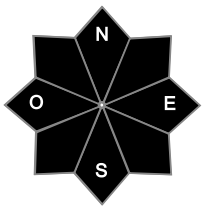

Au-dessus de 2000m indice de risque marqué, plus bas indice limité évoluant en marqué.

Départs spontanés : départs de neige humide devenant nombreux au soleil au fil de la journée

Déclenchements provoqués : instabilités dans la neige récente en altitude.

Indices de risque : 5 très fort - 4 fort - 3 marqué - 2 limité - 1 faible -- En noir : les pentes les plus dangereuses

Stabilité du manteau neigeux

Situation avalancheuse typique : couche fragile persistante neige humide

Déclenchements provoqués :
- instabilités dans la neige récente ventée, plus fréquentes en versants nord-ouest à sud-est au-dessus de 2000 m. Plaques d'aspect variable : en neige durcie par le vent proche des crêtes, parfois friables dans les zones plus abritées, voir même en neige humide en surface en versants ensoleillés d'altitude. Encore faciles à déclencher au passage d'un seul skieur, elles engendrent des avalanches de taille petite à moyenne (taille 1 à 2), rarement grande dans les zones de forte accumulation.

- en orientations ouest, nord et est d'altitude supérieure à 2000/2200 m environ, une rare grande voire très grande avalanche (taille 3 à 4) est possible, par sollicitation d'une couche fragile persistante enfouie à la base du manteau neigeux. Déclenchement difficile au passage d'un skieur, mais possible là où le manteau neigeux est moins épais (croupes, bords de couloirs), ou en cascade après un premier départ en surface.

- des départs sous les skis de neige fortement humidifiée sont possibles en versant raides ensoleillés en cours de journée. Avalanches de taille petite à moyenne (taille 1 à 2)

Départs spontanés :
- départs ponctuels par humidification du manteau neigeux : peu probables en début de journée, puis devenant fréquents en cours de journée, en pentes raides ensoleillées à toutes altitudes, notamment près des rochers. Avalanches de taille petite à moyenne (taille 1 à 2), rarement grande (taille 3), notamment en dessous de 2200/2400 m où le manteau est humidifié en profondeur.

- rares avalanches possibles à la suite d'une rupture de corniches ou de reptations en cours d'ouverture. Taille moyenne à grande (taille 2 à 3).

Qualité de la neige

Enneigement excédentaire pour un mois de février, en particulier dans la tranche entre 1400 et 2200 m. Il faut remonter à 2018 pour trouver un enneigement encore plus abondant à cette période de l'année.
Données observées : 114 cm au-dessus de Larche à 2270 m en adret, et 110/130 cm à 2000 m en ubacs.

Enneigement skiable dès 1300/1500 m en terrains favorables, 1600/1800 m en adrets.

État de la neige en surface : neige croutée le matin avec un regel moyen, s'humidifiant rapidement en journée au fil de l'ensoleillement. On retrouve de la neige encore poudreuse en Ubacs au-dessus de 1600/1800 m environ, souvent travaillée/durcie par le vent de nord. Zones dégarnies proches des crêtes, alternant avec des corniches parfois épaisses.

Aperçu météo pour le lundi 23 février

	nuit	matin	après-midi	soir
Temps sec et doux, soleil voilé.				
Pluie-Neige				
Iso 0 °C	2 900 m	2 800 m	3 100 m	3 400 m
Vent 2000 m	→ 20 km/h	↘ 20 km/h	↘ 15 km/h	↻ 15 km/h
Vent 3000 m	↘ 40 km/h	↘ 35 km/h	↘ 35 km/h	↘ 30 km/h

Pour consulter la vigilance en cours, veuillez vous rendre sur le site https://vigilance.meteofrance.fr/fr

Météo-France - 73 avenue de Paris, 94165 Saint-Mandé cedex - Contact : contact@meteo.fr

Rédigé par Météo-France avec la contribution des observateurs du réseau nivo-météorologiques. Partenariat : ANMSM (Maires de Stations de Montagne), DSF (Domaines Skiables de France), ADSP (Directeurs de Pistes et de la Sécurité des Stations de Sports d'Hiver) et autres acteurs de la montagne.

Bulletin neige & avalanches par téléphone au
0 892 68 10 20 Service 0,35 € / min + prix appel

Bulletin d'estimation du risque d'avalanche

(valable en dehors des pistes balisées et ouvertes)

MASSIF : Ubaye

Rédigé le dimanche 22 février 2026 à 16h

Épaisseur de neige hors-piste

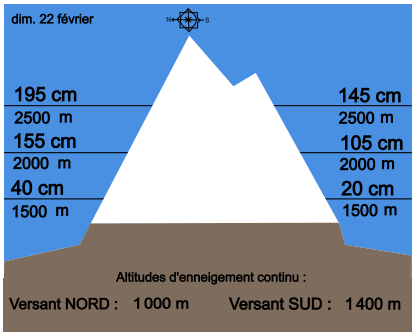

Précipitations à 1800 m

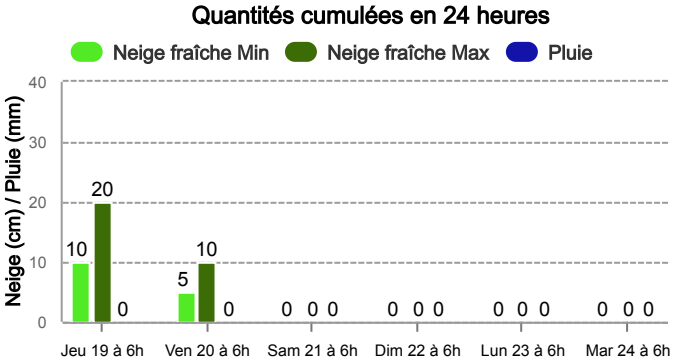

Tendance du mardi 24 février

Indice de risque marqué

Maintien d'un risque marqué en journée avec la poursuite de l'humidification de manteau neigeux dans les versants ensoleillé. Départs spontanés localement volumineux.

Pour consulter la vigilance en cours, veuillez vous rendre sur le site https://vigilance.meteofrance.fr/fr

Météo-France - 73 avenue de Paris, 94165 Saint-Mandé cedex - Contact : contact@meteo.fr

Rédigé par Météo-France avec la contribution des observateurs du réseau nivo-météorologiques. Partenariat : ANMSM (Maires de Stations de Montagne), DSF (Domaines Skiables de France), ADSP (Directeurs de Pistes et de la Sécurité des Stations de Sports d'Hiver) et autres acteurs de la montagne.

Bulletin neige & avalanches par téléphone au

0 892 68 10 20 Service 0,35 € / min + prix appel

RÉPUBLIQUE FRANÇAISE
Liberté Égalité Fraternité

METEO FRANCE
À VOS CÔTÉS, DANS UN CLIMAT QUI CHANGE

Bulletin d'estimation du risque d'avalanche

(valable en dehors des pistes balisées et ouvertes)

MASSIF : Ubaye

Rédigé le dimanche 22 février 2026 à 16h

Conditions nivo-météo des 7 derniers jours

	lun. 16/02				mar. 17/02				mer. 18/02				jeu. 19/02				ven. 20/02				sam. 21/02				dim. 22/02			
	03h	09h	15h	21h	03h	09h	15h	21h	03h	09h	15h	21h	03h	09h	15h	21h	03h	09h	15h	21h	03h	09h	15h	21h	03h	09h	15h	21h
Météo																												
Vent (km/h)	60	85	110	90	80	65	55	50	50	40	35	70	45	50	75	80	75	65	45	40	55	60	50	35	35	35	40	45
à 3000m																												
Vent (km/h)	30	50	70	50	35	35	25	20	15	15	20	30	30	30	40	35	30	30	25	20	20	25	25	20	15	15	20	15
à 2000m																												

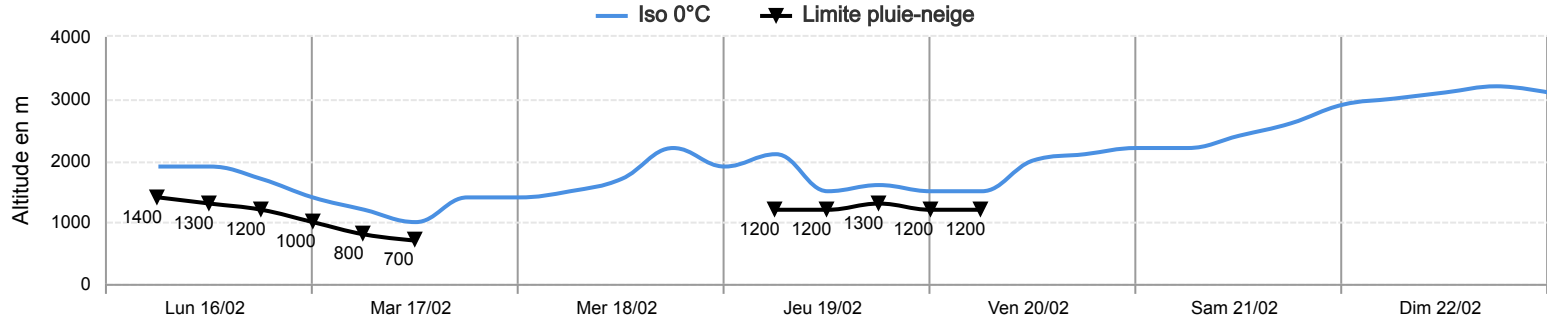

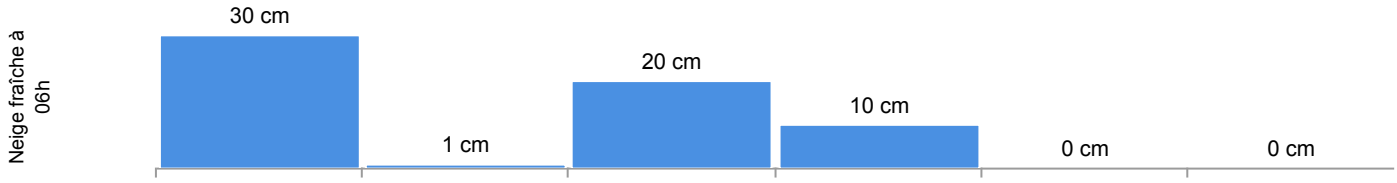

Risque d'avalanche	lun. 16/02	mar. 17/02	mer. 18/02	jeu. 19/02	ven. 20/02	sam. 21/02	dim. 22/02
	3	3	3	4	3	3	3

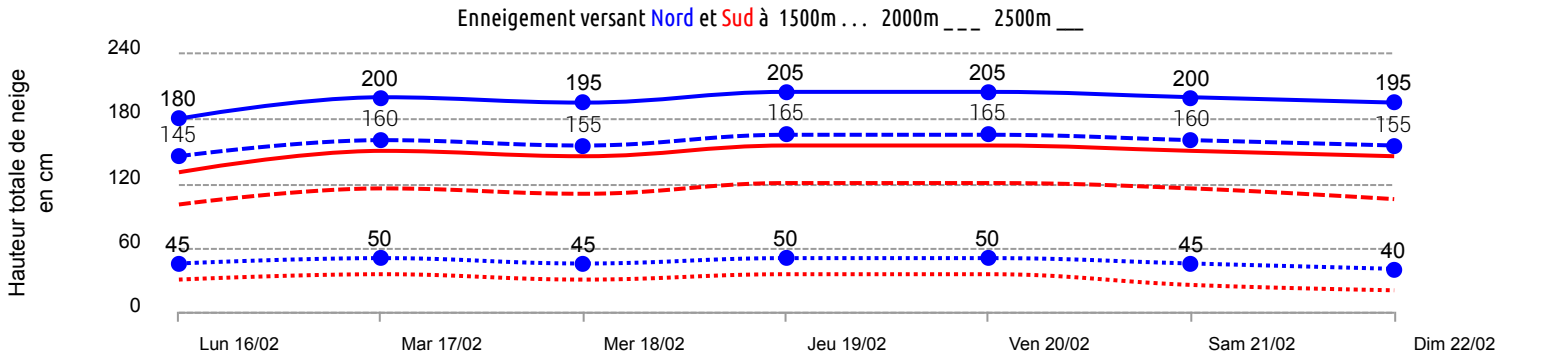

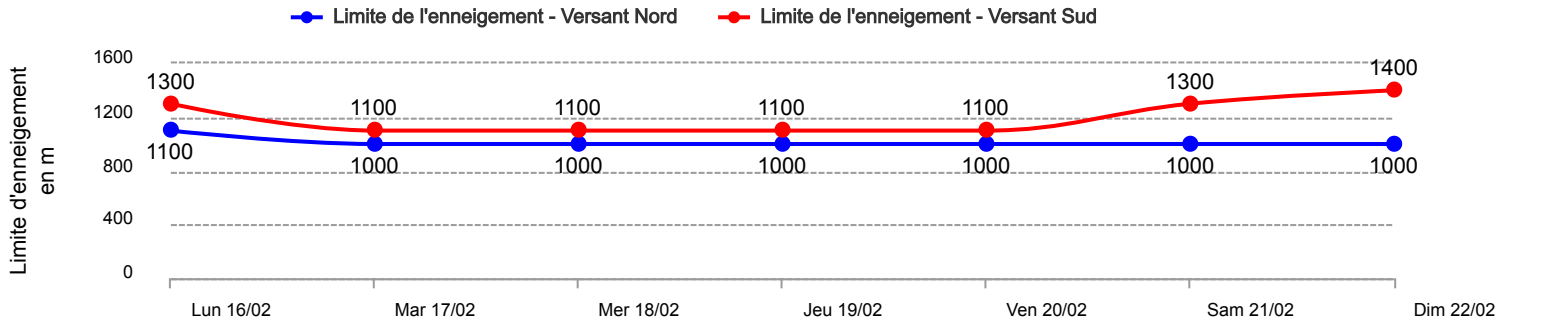

Pour consulter la vigilance en cours, veuillez vous rendre sur le site https://vigilance.meteofrance.fr/fr

Météo-France - 73 avenue de Paris, 94165 Saint-Mandé cedex - Contact : contact@meteo.fr

Rédigé par Météo-France avec la contribution des observateurs du réseau nivo-météorologiques. Partenariat : ANMSM (Maires de Stations de Montagne), DSF (Domaines Skiables de France), ADSP (Directeurs de Pistes et de la Sécurité des Stations de Sports d'Hiver) et autres acteurs de la montagne.

Bulletin neige & avalanches par téléphone au

0 892 68 10 20 Service 0,35 € / min + prix appel