Danger d'avalanche

actualisé le 22.2.2026, 17:00

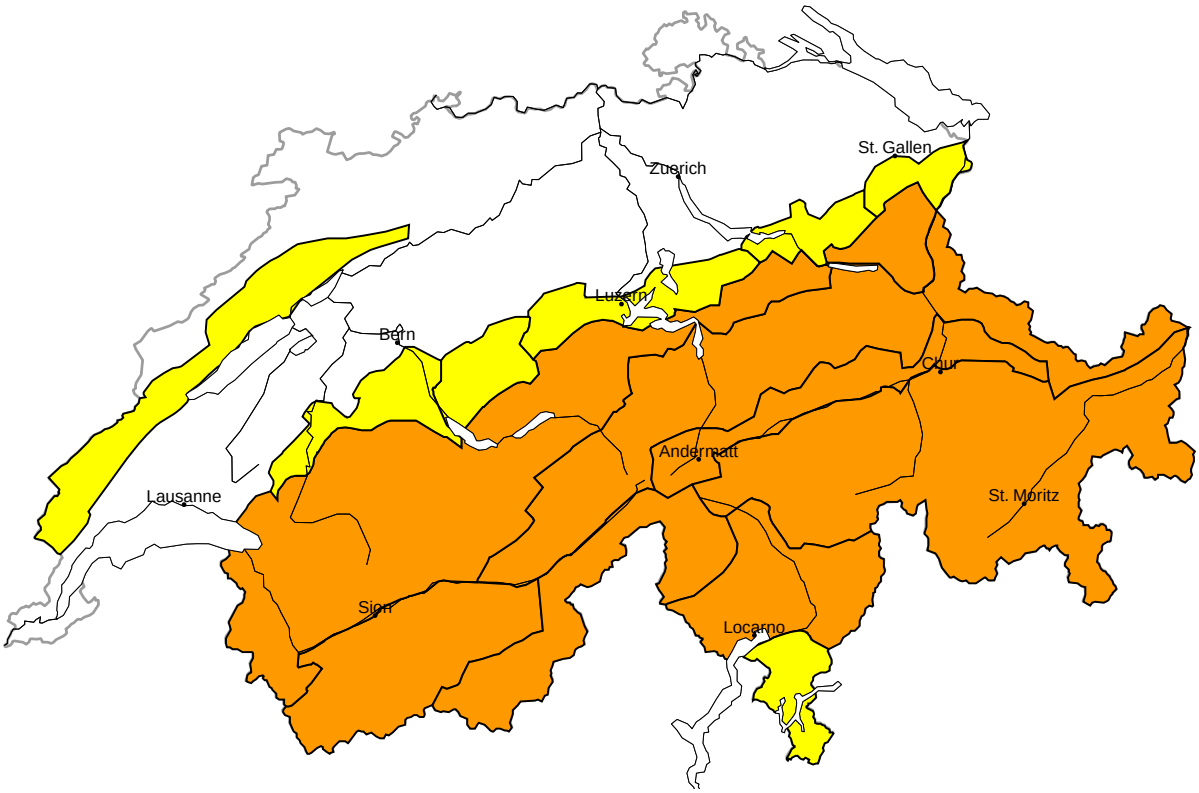

région A

Marqué (3+)

Neige fraîche, Couche fragile persistante

Endroits dangereux

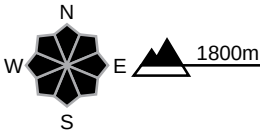

Description des dangers
La neige fraîche abondante et la neige soufflée des derniers jours sont fragiles. Des amateurs de sports d'hiver même seuls peuvent facilement déclencher des avalanches. Celles-ci peuvent atteindre une très grande taille de manière isolée.
Pour des randonnées et descentes hors-piste en dehors des pistes sécurisées les conditions sont critiques.

Limité (2)

Neige glissante

Endroits dangereux

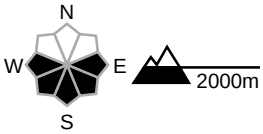

Description des dangers
Sur les pentes raides herbeuses des avalanches de glissement sont à attendre. Celles-ci peuvent aussi atteindre une grande taille. Des glissements sur les talus sont possibles.

Degrés de danger 1 faible 2 limité 3 marqué 4 fort 5 très fort

région B

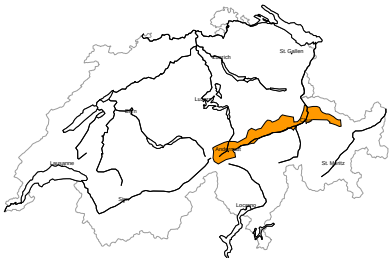

Marqué (3+)

Neige fraîche, Couche fragile persistante

Endroits dangereux

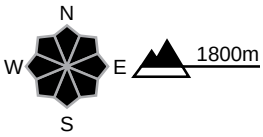

Description des dangers
La neige fraîche et la neige soufflée reposent sur une couche fragile de neige ancienne. Des avalanches peuvent en de nombreux endroits être déclenchées facilement. Elles peuvent se déclencher dans les couches proches du sol et atteindre une grande taille. Des bruits sourds ainsi que des avalanches récentes attirent l'attention sur le danger. Des déclenchements à distance sont à attendre.
Pour des randonnées et descentes hors-piste en dehors des pistes sécurisées les conditions sont très critiques.

Limité (2)

Neige glissante

Endroits dangereux

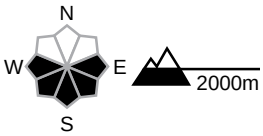

Description des dangers
Sur les pentes raides herbeuses des avalanches de glissement sont à attendre. Celles-ci peuvent aussi atteindre une grande taille. Des glissements sur les talus sont possibles.

région C

Marqué (3+)

Neige fraîche, Couche fragile persistante

Endroits dangereux

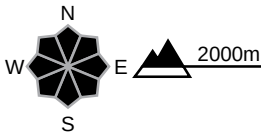

Description des dangers
La neige fraîche et la neige soufflée des derniers jours reposent sur une couche fragile de neige ancienne. Des amateurs de sports d'hiver même seuls peuvent facilement déclencher des avalanches. Celles-ci peuvent se déclencher dans les couches profondes du manteau neigeux et atteindre une grande taille. Prudence dans les endroits plutôt faiblement enneigés comme aux transitions entre les endroits peu enneigés et les endroits très enneigés. Des déclenchements à distance sont possibles.
Les randonnées et descentes hors-piste demandent de l' expérience dans l'évaluation du danger d'avalanche et de la retenue.

Limité (2)

Neige glissante

Endroits dangereux

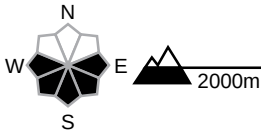

Description des dangers
Sur les pentes raides herbeuses des avalanches de glissement sont à attendre. Celles-ci peuvent aussi atteindre une grande taille. Des glissements sur les talus sont possibles.

région D

Marqué (3+)

Neige fraîche, Couche fragile persistante

Endroits dangereux

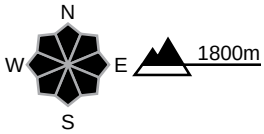

Description des dangers
La neige fraîche et la neige soufflée reposent sur une couche fragile de neige ancienne. Des avalanches peuvent en de nombreux endroits être déclenchées facilement. Elles peuvent se déclencher dans les couches proches du sol et atteindre une grande taille. Des bruits sourds ainsi que des avalanches récentes attirent l'attention sur le danger. Des déclenchements à distance sont à attendre.
Pour des randonnées et descentes hors-piste en dehors des pistes sécurisées les conditions sont très critiques.

région E

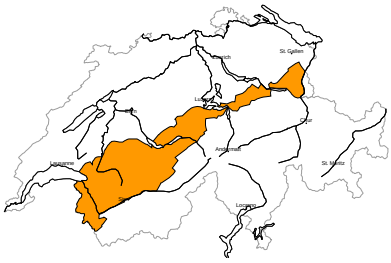

Marqué (3=)

Neige fraîche

Endroits dangereux

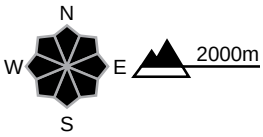

Description des dangers
La neige fraîche abondante et la neige soufflée sont partiellement encore fragiles. Des amateurs de sports d'hiver même seuls peuvent déclencher des avalanches. Prudence dans les endroits plutôt faiblement enneigés comme aux transitions entre les endroits peu enneigés et les endroits très enneigés. Des avalanches peuvent entraîner avec elles les couches profondes du manteau neigeux et atteindre une taille dangereuse.
Les randonnées et descentes hors-piste demandent beaucoup d'expérience dans l'évaluation du danger d'avalanche.

Limité (2)

Neige glissante

Endroits dangereux

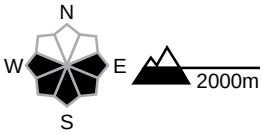

Description des dangers
Sur les pentes raides herbeuses des avalanches de glissement sont à attendre. Celles-ci peuvent aussi atteindre une grande taille. Des glissements sur les talus sont possibles.

région F

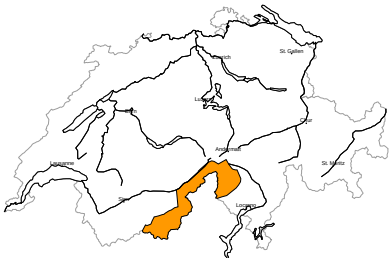

Marqué (3=)

Neige soufflée, Couche fragile persistante

Endroits dangereux

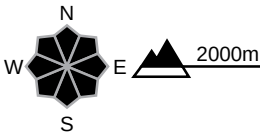

Description des dangers
Les accumulations déjà plus anciennes de neige soufflée reposent sur une couche fragile de neige ancienne. Des avalanches peuvent être déclenchées facilement. Elles peuvent aussi se déclencher dans les couches profondes du manteau neigeux et atteindre une grande taille. Des bruits sourds peuvent attirer l'attention sur le danger.
Les randonnées et descentes hors-piste demandent une expérience dans l'évaluation du danger d'avalanche.

Limité (2)

Neige glissante

Endroits dangereux

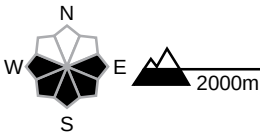

Description des dangers
Sur les pentes raides herbeuses des avalanches de glissement sont à attendre. Celles-ci peuvent aussi atteindre une grande taille. Des glissements sur les talus sont possibles.

région G

Marqué (3=)

Neige soufflée, Couche fragile persistante

Endroits dangereux

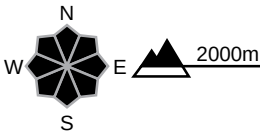

Description des dangers
Les accumulations déjà plus anciennes de neige soufflée reposent sur une couche fragile de neige ancienne. Des avalanches peuvent être déclenchées facilement. Elles peuvent aussi se déclencher dans les couches profondes du manteau neigeux et atteindre une grande taille. Des bruits sourds peuvent attirer l'attention sur le danger.
Les randonnées et descentes hors-piste demandent une expérience dans l'évaluation du danger d'avalanche.

région H

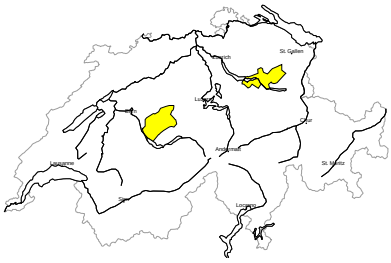

Limité (2+)

Neige fraîche

Endroits dangereux

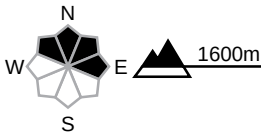

Description des dangers
La neige fraîche des derniers jours et les accumulations de neige soufflée sont partiellement encore fragiles en altitude. Des amateurs de sports d'hiver peuvent par endroits déclencher des avalanches, pouvant atteindre une taille moyenne.
Un choix prudent des itinéraires est nécessaire.

Limité (2)

Neige glissante

Endroits dangereux

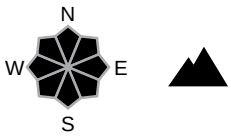

Description des dangers
Sur les pentes raides herbeuses des avalanches de glissement sont à attendre, surtout de taille moyenne. Des glissements sur les talus sont possibles.

région I

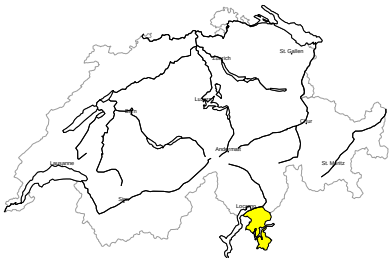

Limité (2=)

Neige soufflée, Couche fragile persistante

Endroits dangereux

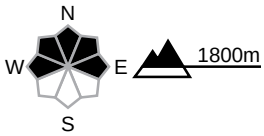

Description des dangers
Les accumulations de neige soufflée des derniers jours devraient être évaluées avec prudence en terrain raide. Des avalanches peuvent se rompre jusque dans les couches profondes de manière isolée et atteindre une taille moyenne. Un choix prudent des itinéraires est recommandé.

région J

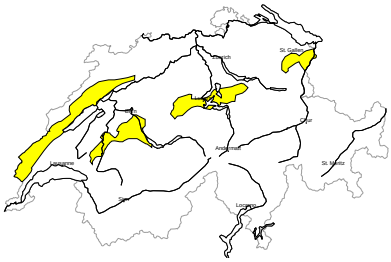

Limité (2)

Neige glissante

Endroits dangereux

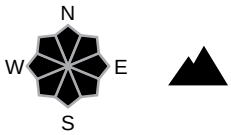

Description des dangers
Sur les pentes raides herbeuses des avalanches de glissement sont à attendre, surtout de taille moyenne. Des glissements sur les talus sont possibles.

Manteau neigeux et météo

actualisé le 22.2.2026, 17:00

Manteau neigeux

Les grandes quantités de neige fraîche et de neige soufflée de ces derniers jours et semaines restent fragiles en de nombreux endroits.
Au nord d'une ligne Rhône-Rhin et dans la partie la plus occidentale du Bas-Valais, de 2 à 3,5 m de neige sont tombés au cours des 2 dernières semaines. Les couches fragiles du manteau de neige ancienne sont ainsi recouvertes d'une épaisse couche et leur décrochement ne peut pratiquement plus être provoqué par des personnes. Les avalanches peuvent cependant localement encore entraîner avec elles des couches plus profondes et, dans ce cas, atteindre une très grande ampleur.
Au sud d'une ligne Rhône-Rhin, le problème de la neige ancienne reste marqué. C'est dans les Grisons que la neige ancienne fragile est la plus susceptible de se décrocher. Les endroits dangereux y sont toujours aussi fréquents, même déjà dans la limite de la forêt. Des bruits sourds et des déclenchements à distance sont typiques. Dans le sud du Valais, les couches fragiles marquées dans la partie inférieure du manteau neigeux sont généralement recouvertes d'une couche un peu plus épaisse. Les endroits dangereux où des avalanches peuvent être déclenchées dans la neige ancienne fragile sont donc un peu plus rares et se situent surtout dans les zones plutôt faiblement enneigées.
Avec les températures douces, il faut s'attendre à des avalanches de glissement de taille moyenne ou grande sur les pentes herbeuses raides en dessous de 2000 m environ.

Rétrospective météo de ce dimanche

Dans la nuit de samedi à dimanche, les précipitations ont pris fin, en dernier lieu dans l'est. La limite pluie-neige se situait à 1500 m à la fin des précipitations. La journée était assez ensoleillée.

Neige fraîche
Depuis samedi après-midi jusqu'à dimanche matin, au-dessus de 2000 m environ :
- Est du versant nord des Alpes, nord des Grisons, Basse-Engadine : de 15 à 25 cm
- Centre du versant nord des Alpes, nord du Haut-Valais, reste des Grisons : de 5 à 15 cm

Depuis le début de cette période de précipitations vendredi soir, il est ainsi tombé au-dessus de 2000 m :
- Est du versant nord des Alpes, Prättigau, Silvretta, Samnaun : de 40 à 60 cm
- Reste du versant nord des Alpes, nord du Haut-Valais, vallée de Conches, reste du nord des Grisons, reste de la Basse-Engadine : de 20 à 40 cm
- Ailleurs : souvent de 10 à 20 cm; dans le sud, temps sec

Température
À la mi-journée à 2000 m, entre +2 °C dans le nord et +5 °C dans le sud

Vent
- Pendant la nuit, vent de secteur ouest à nord-ouest, modéré à fort, et parfois tempétueux sur la crête principale des Alpes.
- En journée, vent du sud-ouest, modéré dans le nord et faible dans le sud

Prévisions météorologiques jusqu’à lundi

Pendant la nuit et la matinée, quelques précipitations tomberont sur une grande partie du territoire. Il y aura des éclaircies en cours de journée. Dans le sud, le temps sera sec et la journée généralement ensoleillée. La limite pluie-neige se situera dans le nord entre 1600 et 1800 m, tandis que dans le sud du Valais, elle pourra monter jusqu'à environ 2000 m.

Neige fraîche
Entre dimanche soir et lundi après-midi, au-dessus de 2200 m :
- Crête nord des Alpes: de 5 à 10 cm
- Reste du versant nord des Alpes, reste du Valais, reste du nord des Grisons, nord de la Basse-Engadine : quelques centimètres

Température
À la mi-journée à 2000 m, entre 0 °C dans le nord et +4 °C dans le sud

Vent
De secteur ouest à nord-ouest, modéré sur une grande partie du territoire, mais fort en altitude

Tendance jusqu’à mercredi

Mardi, il neigera au-dessus de 1800 m sur le versant nord des Alpes et dans le nord des Grisons. En altitude, il faut s'attendre à 10 à 20 cm de neige fraîche. Les quantités sont toutefois encore incertaines. Dans l'ouest et le sud, le temps sera ensoleillé et très doux. Le vent du nord-ouest sera parfois fort pendant la nuit de lundi à mardi, puis il s'atténuera. Jeudi, le temps sera ensoleillé, faiblement venteux et très doux avec une isotherme zéro degré à 3000 m.
Le danger d'avalanches sèches n'évoluera pas de manière significative mardi dans les régions avec de la neige fraîche, tandis qu’il diminuera ailleurs, mais seulement très lentement dans le sud du Valais, dans le Tessin et dans les Grisons, en raison de la présence de couches fragiles marquées. Il faudra s’attendre à des avalanches de glissement, y compris de grande ampleur dans l'ouest et le nord.