Pericolo valanghe

aggiornato al 22.2.2026, 17:00

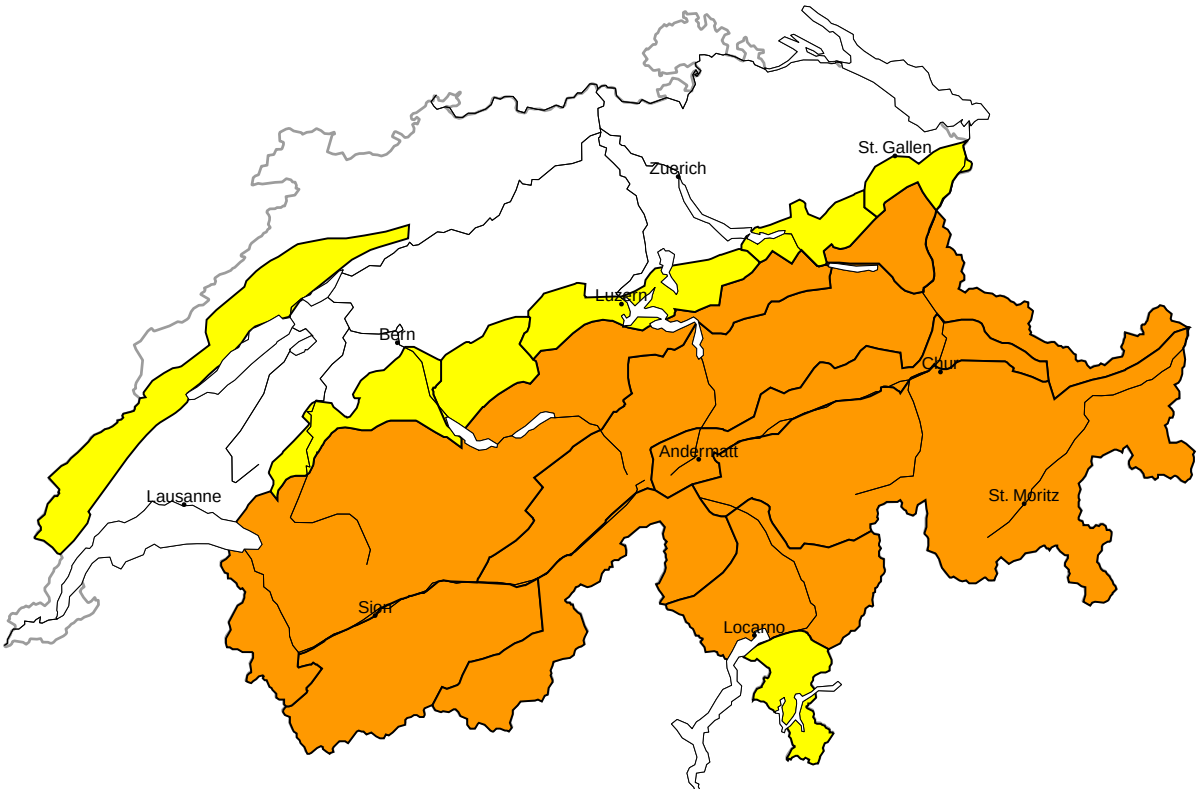

regione A

Marcato (3+)

Neve fresca, Strati deboli persistenti

Punti pericolosi

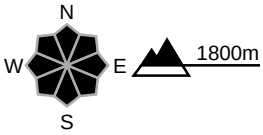

Descrizione del pericolo
Le grandi quantità di neve fresca e neve ventata degli ultimi giorni sono instabili. Già un singolo appassionato di sport invernali può facilmente provocare il distacco di valanghe. Queste possono raggiungere dimensioni molto grandi a livello isolato.
Per le escursioni e le discese fuori pista al di fuori delle piste assicurate, le condizioni sono critiche.

Moderato (2)

Valanghe di slittamento

Punti pericolosi

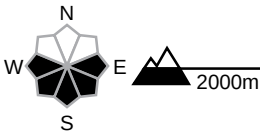

Descrizione del pericolo
Sui pendii erbosi ripidi, sono previste valanghe per scivolamento di neve. Queste possono anche raggiungere grandi dimensioni. Sono possibili colate dalle scarpate.

Scala del pericolo 1 debole | 2 moderato | 3 marcato | 4 forte | 5 molto forte

regione B

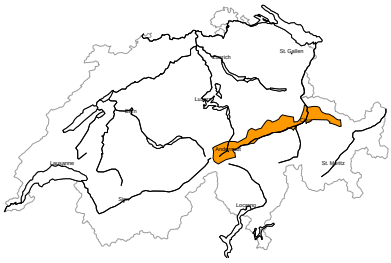

Marcato (3+)

Neve fresca, Strati deboli persistenti

Punti pericolosi

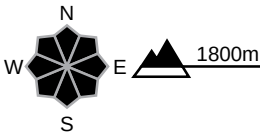

Descrizione del pericolo
La neve fresca e la neve ventata ricoprono un debole manto di neve vecchia. Le valanghe possono in molti punti distaccarsi facilmente. Esse possono staccarsi negli strati basali del manto e raggiungere grandi dimensioni. I rumori di "whum" così come nuove valanghe sono segnali da ricondurre a questo pericolo. Si prevedono distacchi a distanza.
Per le escursioni e le discese fuori pista al di fuori delle piste assicurate, le condizioni sono molto critiche.

Moderato (2)

Valanghe di slittamento

Punti pericolosi

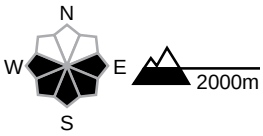

Descrizione del pericolo
Sui pendii erbosi ripidi, sono previste valanghe per scivolamento di neve. Queste possono anche raggiungere grandi dimensioni. Sono possibili colate dalle scarpate.

regione C

Marcato (3+)

Neve fresca, Strati deboli persistenti

Punti pericolosi

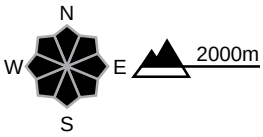

Descrizione del pericolo
La neve fresca e la neve ventata degli ultimi giorni ricoprono un debole manto di neve vecchia. Già un singolo appassionato di sport invernali può facilmente provocare il distacco di valanghe. Queste possono distaccarsi negli strati più profondi e raggiungere grandi dimensioni. Attenzione nelle zone scarsamente innevate, come pure nelle zone di passaggio da poca a molta neve. Sono possibili distacchi a distanza.
Le escursioni e le discese fuori pista richiedono esperienza nella valutazione del pericolo di valanghe e attenzione.

Moderato (2)

Valanghe di slittamento

Punti pericolosi

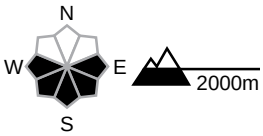

Descrizione del pericolo
Sui pendii erbosi ripidi, sono previste valanghe per scivolamento di neve. Queste possono anche raggiungere grandi dimensioni. Sono possibili colate dalle scarpate.

regione D

Marcato (3+)

Neve fresca, Strati deboli persistenti

Punti pericolosi

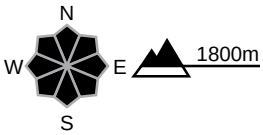

Descrizione del pericolo
La neve fresca e la neve ventata ricoprono un debole manto di neve vecchia. Le valanghe possono in molti punti distaccarsi facilmente. Esse possono staccarsi negli strati basali del manto e raggiungere grandi dimensioni. I rumori di "whum" così come nuove valanghe sono segnali da ricondurre a questo pericolo. Si prevedono distacchi a distanza.
Per le escursioni e le discese fuori pista al di fuori delle piste assicurate, le condizioni sono molto critiche.

regione E

Marcato (3=)

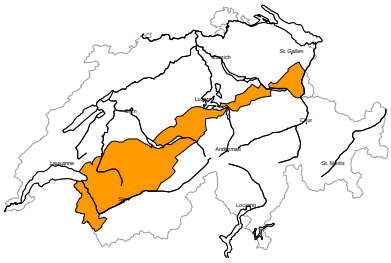

Neve fresca

Punti pericolosi

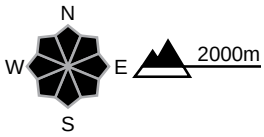

Descrizione del pericolo
Le grandi quantità di neve fresca e neve ventata sono in parte ancora instabili. Già un singolo appassionato di sport invernali può provocare il distacco di valanghe. Attenzione nelle zone scarsamente innevate, come pure nelle zone di passaggio da poca a molta neve. Le valanghe possono trascinare gli strati più profondi del manto nevoso e raggiungere dimensioni pericolosamente grandi.
Le escursioni e le discese fuori pista richiedono molta esperienza nella valutazione del pericolo di valanghe.

Moderato (2)

Valanghe di slittamento

Punti pericolosi

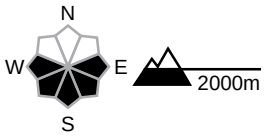

Descrizione del pericolo
Sui pendii erbosi ripidi, sono previste valanghe per scivolamento di neve. Queste possono anche raggiungere grandi dimensioni. Sono possibili colate dalle scarpate.

regione F

Marcato (3=)

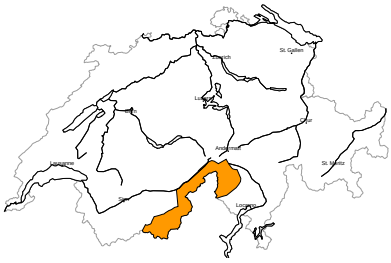

Lastroni da vento, Strati deboli persistenti

Punti pericolosi

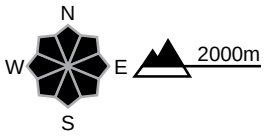

Descrizione del pericolo
Gli accumuli di neve ventata meno recenti ricoprono un debole manto di neve vecchia. Le valanghe possono distaccarsi facilmente. Esse possono anche distaccarsi negli strati più profondi e raggiungere grandi dimensioni. I rumori di "whum" sono possibili segnali di pericolo.
Le escursioni e le discese fuori pista richiedono esperienza nella valutazione del pericolo di valanghe.

Moderato (2)

Valanghe di slittamento

Punti pericolosi

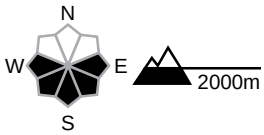

Descrizione del pericolo
Sui pendii erbosi ripidi, sono previste valanghe per scivolamento di neve. Queste possono anche raggiungere grandi dimensioni. Sono possibili colate dalle scarpate.

regione G — Marcato (3=)

Lastroni da vento, Strati deboli persistenti

Punti pericolosi

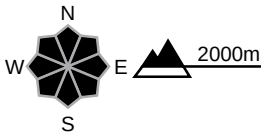

Descrizione del pericolo
Gli accumuli di neve ventata meno recenti ricoprono un debole manto di neve vecchia. Le valanghe possono distaccarsi facilmente. Esse possono anche distaccarsi negli strati più profondi e raggiungere grandi dimensioni. I rumori di "whum" sono possibili segnali di pericolo.
Le escursioni e le discese fuori pista richiedono esperienza nella valutazione del pericolo di valanghe.

regione H — Moderato (2+)

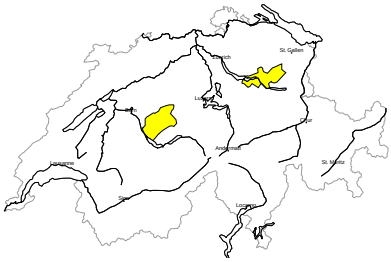

Neve fresca

Punti pericolosi

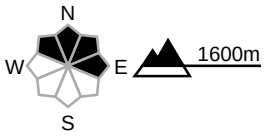

Descrizione del pericolo
La neve fresca degli ultimi giorni e gli accumuli di neve ventata sono in parte ancora instabili in quota. Un appassionato di sport invernali può in alcuni punti provocare il distacco di valanghe, anche di medie dimensioni.
È necessaria una prudente scelta dell'itinerario.

Moderato (2)

Valanghe di slittamento

Punti pericolosi

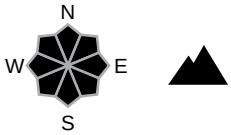

Descrizione del pericolo
Sui pendii erbosi ripidi, sono previste valanghe per scivolamento di neve, soprattutto di medie dimensioni. Sono possibili colate dalle scarpate.

regione I — Moderato (2=)

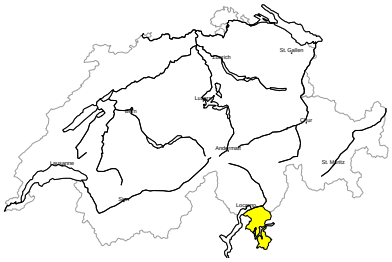

Lastroni da vento, Strati deboli persistenti

Punti pericolosi

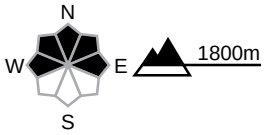

Descrizione del pericolo
Gli accumuli di neve ventata degli ultimi giorni dovrebbero essere valutati con attenzione sui pendii ripidi. A livello isolato le valanghe possono coinvolgere gli strati più profondi e raggiungere dimensioni medie.
Si raccomanda una prudente scelta dell'itinerario.

Bollettino valanghe sino a lunedì, 23. febbraio 2026

regione J — Moderato (2)

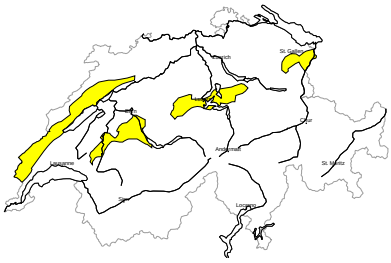

Valanghe di slittamento

Punti pericolosi

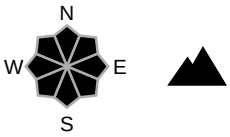

Descrizione del pericolo
Sui pendii erbosi ripidi, sono previste valanghe per scivolamento di neve, soprattutto di medie dimensioni. Sono possibili colate dalle scarpate.

Manto nevoso e meteo

aggiornato al 22.2.2026, 17:00

Manto nevoso

In molte regioni le abbondanti quantità di neve fresca e ventata degli ultimi giorni e settimane rimangono ancora instabili. Nelle ultime due settimane, a nord di una linea Rodano-Reno e nel Basso Vallese occidentale estremo sono caduti dai 2 ai 3,5 m di neve. Gli strati fragili presenti nel manto di neve vecchia sono stati così abbondantemente ricoperti e non possono praticamente più subire un distacco in seguito al passaggio di persone. A livello isolato sono tuttavia ancora possibili valanghe che coinvolgono gli strati profondi e che possono quindi raggiungere dimensioni molto grandi.
A sud di una linea Rodano-Reno, il problema di neve vecchia è ancora pronunciato. La maggiore instabilità del debole manto di neve vecchia si registra nei Grigioni, dove i punti pericolosi sono ancora frequenti, anche già nella zona del limite del bosco. I rumori di assestamento e i distacchi a distanza sono segnali tipici. Nel sud del Vallese i pronunciati strati fragili nella parte basale del manto nevoso sono generalmente ricoperti da una quantità di neve un po' più abbondante. I punti pericolosi in cui le valanghe possono subire un distacco nel debole manto di neve vecchia sono pertanto un po' più rari e si trovano soprattutto nelle zone scarsamente innevate.
Con le temperature miti, sui pendii ripidi erbosi situati al di sotto dei 2000 m circa si prevedono valanghe per scivolamento di neve di medie e grandi dimensioni.

Retrospettiva meteo fino a domenica

Le precipitazioni sono cessate nella notte fra sabato e domenica, esaurendosi per ultimo nelle regioni orientali. Al termine delle precipitazioni il limite delle nevicate era collocato intorno ai 1500 m. Nel corso della giornata il cielo è stato piuttosto soleggiato.

Neve fresca
Da sabato pomeriggio a domenica mattina, al di sopra dei 2000 m:
- Versante nordalpino orientale, nord dei Grigioni, Bassa Engadina: dai 15 ai 25 cm
- Versante nordalpino centrale, parte settentrionale dell'Alto Vallese, restanti Grigioni: dai 5 ai 15 cm

Da venerdì sera, quando è iniziato questo periodo di precipitazioni, al di sopra dei 2000 m sono così cadute complessivamente le seguenti quantità di neve:
- Versante nordalpino orientale, Prettigovia, gruppo del Silvretta, Samnaun: dai 40 ai 60 cm
- Restante versante nordalpino, parte settentrionale dell'Alto Vallese, valle di Goms, restante nord dei Grigioni, restante Bassa Engadina: dai 20 ai 40 cm
- In molte altre regioni: dai 10 ai 20 cm. Regioni meridionali: tempo asciutto

Temperatura
Sul mezzogiorno a 2000 m compresa tra +2 °C nelle regioni settentrionali e +5 °C in quelle meridionali

Vento
- Durante la notte da moderato a forte, sulla cresta principale delle Alpi a tratti tempestoso, proveniente da ovest a nord ovest
- Durante il giorno nelle regioni settentrionali moderato, in quelle meridionali debole, proveniente da sud ovest

Previsioni meteo fino a lunedì

Durante la notte e in mattinata si prevedono deboli precipitazioni in molte regioni. Poi nel corso della giornata ci saranno schiarite. Nelle regioni meridionali il tempo sarà asciutto e durante il giorno per lo più soleggiato. Nelle regioni settentrionali il limite delle nevicate si collocherà tra i 1600 e i 1800 m, nel sud del Vallese potrà salire fino ai 2000 m circa.

Neve fresca
Da domenica sera a lunedì pomeriggio, al di sopra dei 2200 m:
- Cresta settentrionale delle Alpi: dai 5 ai 10 cm
- Restante versante nordalpino, restante Vallese, restante nord dei Grigioni, parte settentrionale della Bassa Engadina: pochi centimetri

Temperatura
Sul mezzogiorno a 2000 m compresa tra 0 °C nelle regioni settentrionali e +4 °C in quelle meridionali

Vento
Proveniente da ovest a nord ovest: in molte regioni moderato, in quota forte

Tendenza fino a mercoledì

Martedì sul versante nordalpino orientale e nel nord dei Grigioni nevicherà al di sopra dei 1800 m. In quota si prevedono dai 10 ai 20 cm di neve fresca. Le quantità sono però ancora incerte. Nelle regioni occidentali e meridionali il tempo sarà soleggiato e molto mite. Nella notte fra lunedì e martedì il vento proveniente da nord ovest sarà a tratti forte, poi si attenuerà. Mercoledì il tempo sarà soleggiato, con vento debole e molto mite grazie a una soglia dello zero termico collocata intorno ai 3000 m.
Martedì il pericolo di valanghe asciutte non subirà variazioni degne di nota nelle regioni con neve fresca, mentre altrove diminuirà, ma nel sud del Vallese, in Ticino e nei Grigioni solo molto lentamente a causa dei pronunciati strati deboli. Si prevedono valanghe per scivolamento di neve, che nelle regioni occidentali e settentrionali potranno raggiungere anche grandi dimensioni.