GOBIERNO DE ESPAÑA
VICEPRESIDENCIA TERCERA DEL GOBIERNO
MINISTERIO PARA LA TRANSICIÓN ECOLÓGICA Y EL RETO DEMOGRÁFICO

Boletín de información nivológica y de peligro de aludes

Pirineo Catalán

aemet Agencia Estatal de Meteorología

lunes, 23 de febrero de 2026

Pronóstico hasta las 24 horas del martes, día 24 de febrero

(Válido fuera de pistas de esquí balizadas y abiertas)

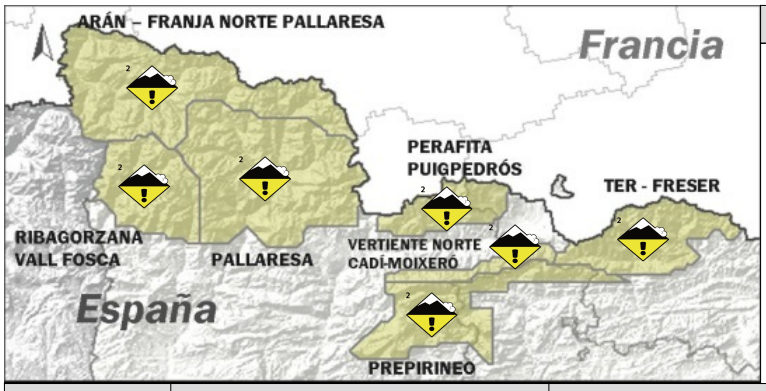

Problemas de aludes

Placas de viento

Nieve húmeda

Macizo	Peligro	Problemas de aludes, cota, orientación, tamaño	Innivación observada (m)
Arán - Franja norte Pallaresa	2 / 2 1→2 2200 Durante el día / Limitado	Placas de viento: 2200 ↑, N E, 2 Nieve húmeda: O E S, 2	2026-02-23 N S Cotas bajas
Ribagorzana - Vall Fosca	2 / 2 1→2 2200 Durante el día / Limitado	Placas de viento: 2400 ↑, N E, 2 Nieve húmeda: O E S, 2	2026-02-23 N S Cotas bajas
Pallaresa	2 / 2 1→2 2200 Durante el día / Limitado	Placas de viento: 2400 ↑, N E, 2 Nieve húmeda: O E S, 2	2026-02-23 N S Cotas bajas

AEMET. Se autoriza la reproducción de su contenido citando la fuente.

Boletín de información nivológica y de peligro de aludes

Pirineo Catalán

Perafita - Puigpedrós	2 Horas centrales **Limitado**	**Placas de viento** 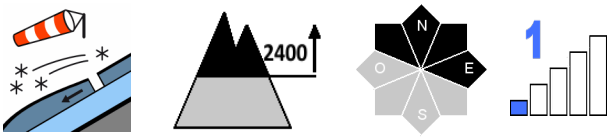 **Nieve húmeda** 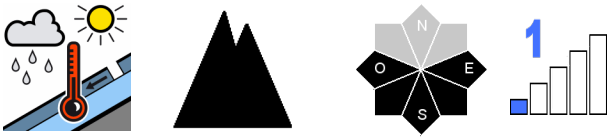	2026-02-23 Cotas bajas
Ter - Freser	2 Horas centrales **Limitado**	**Placas de viento** 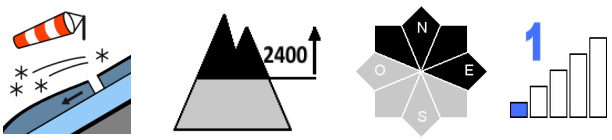 **Nieve húmeda** 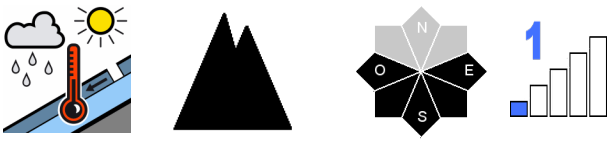	2026-02-23 Cotas bajas
Vertiente norte Cadí - Moixeró	2 Horas centrales **Limitado**	**Placas de viento** 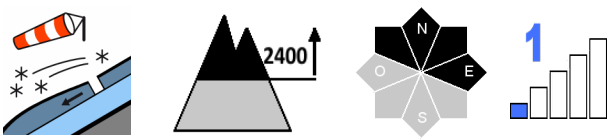 **Nieve húmeda** 	2026-02-23 Cotas bajas
Prepirineo	2 Horas centrales **Limitado**	**Placas de viento** **Nieve húmeda** 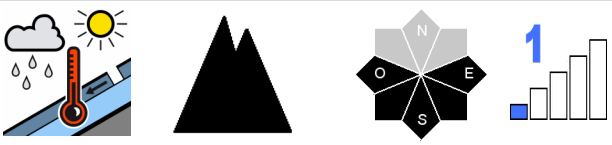	2026-02-23 Cotas bajas

Estado del manto y observaciones recientes

Durante el fin de semana, el ambiente templado con temperaturas anormalmente altas y la abundante insolación han propiciado la humidificación y compactación del manto, a razón de algunos centímetros cada día, procesos que van a continuar durante las próximas jornadas. Con todo, el manto es continuo desde cotas bajas, y presenta espesores muy por encima de lo que sería habitual a estas alturas de la temporada. Por encima de unos 2200 metros se superan los 150-200 cm en muchas zonas, aún más en ventisqueros, hoyas y otras zonas propensas a la acumulación.

AEMET. Se autoriza la reproducción de su contenido citando la fuente.

En cotas medias y bajas el manto se ha humidificado significativamente, y por lo general amanece encostrado, también en solanas a mayor altitud, aunque el calentamiento diurno y la intensa radiación van ablandando las costras durante la mañana. En cotas altas aún podemos encontrar placas de viento que no se han estabilizado por completo, sobre todo en umbrías. Además, no se descarta que persista alguna capa débil enterrada que pueda seguir latente.

Evolución del manto y peligro de aludes para el martes, día 24

Problema de nieve húmeda. Problema de placas de viento en cotas altas.

Mañana, martes, se espera que el rehielo nocturno sea menos efectivo que en días previos, si bien todavía se formarán costras que sustenten el manto a primeras horas. No obstante, en el trascurso de la mañana, el calentamiento diurno y la insolación irán debilitándolas, perdiendo así estabilidad el manto. Con estas condiciones, serán frecuentes los aludes de nieve húmeda en las laderas suficientemente inclinadas, con mayor probabilidad en las solanas y en las proximidades de rocas o elementos oscuros, así como algunos deslizamientos basales, sobre todo en terreno herboso o de roca lisa. Tanto unos como otros serán por lo general de tamaño 1 (pequeño, riesgo de caída) o 2 (mediano, capaz de enterrar a una persona), aunque sin descartar alguno grande (capaz de destruir un vehículo).

En cotas altas, por encima de 2200 metros, aún podemos encontrar placas de viento, principalmente en umbrías, que aunque tienden a estabilizarse, todavía podrían colapsar ante una sobrecarga, ocasionando aludes de dimensión 1 o 2. Además, no se descarta que se pueda fracturar alguna capa débil persistente en profundidad, que en el peor de los casos podría provocar un alud de mayores dimensiones.

Conviene recordar que las superficies heladas pueden provocar resbalones y caídas con graves consecuencias.

Predicción meteorológica para el martes, día 24

Poco nuboso o despejado, con intervalos de nubes altas. Temperaturas mínimas en ascenso. Máximas con pocos cambios, salvo ascensos ligeros en el Arán y Ripollés. Heladas débiles en cotas altas, así como en algún fondo de valle. Viento de componentes oeste y sur, flojo con algún intervalo moderado.

Datos en la atmósfera libre:

Altitud de la isoterma de 0 ºC: 3400 m
Altitud de la isoterma de -10 ºC: 4800 m

Viento a 1500 m: SW 20 km/h
Viento a 3000 m: W 20 km/h

Evolución para el miércoles día 25

Las placas de viento tenderán a estabilizarse. Se mantendrá el problema de nieve húmeda.

AEMET. Se autoriza la reproducción de su contenido citando la fuente.

Boletín de información nivológica y de peligro de aludes

Pirineo Catalán

Escala europea de peligro de aludes

Débil | Limitado | Notable | Fuerte | Muy Fuerte

Problemas de aludes

Nieve reciente | Placas de viento | Capas débiles persistentes | Nieve húmeda | Deslizamientos basales | Sin problema evidente

Nota1: Se recuerda que, siempre que haya nieve, la ausencia total de peligro no existe. Hay que tener presente que en circunstancias desfavorables, con aludes de tamaño 1 (alud pequeño o colada) y tamaño 2 (alud mediano), se pueden sufrir severos daños personales.

Nota2: Los BPA se elaboran en base a información meteorológica así como al estado del manto nivoso a través de sondeos puntuales. Se advierte a los usuarios de la variabilidad de esta información al extrapolarla a zonas extensas de montaña. Por ello, AEMET no se hace responsable de su uso para la toma de decisiones que conciernen a la seguridad personal, ni de los riesgos físicos o materiales de ellas derivadas.

AEMET. Se autoriza la reproducción de su contenido citando la fuente.