Dienstag 24.02.2026

Veröffentlicht am 23.02.2026 um 17:00

Vormittag

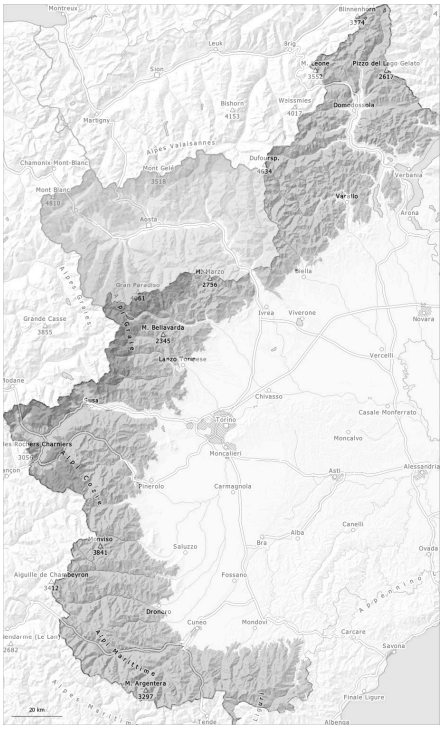

Nachmittag

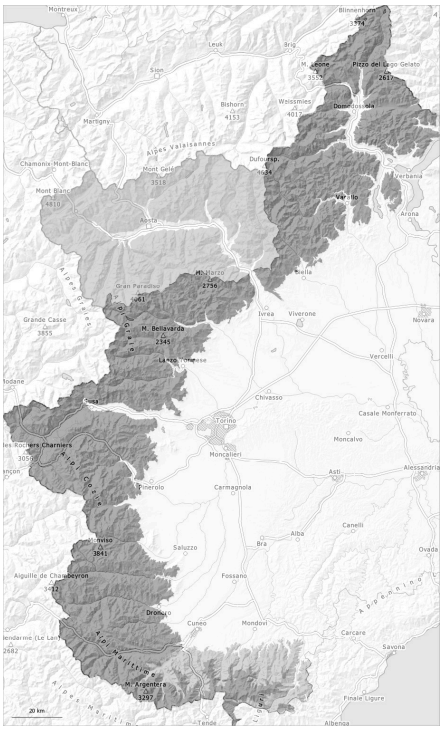

1	2	3	4	5
gering	mäßig	erheblich	groß	sehr groß

Gefahrenstufe 3 - Erheblich

AM:

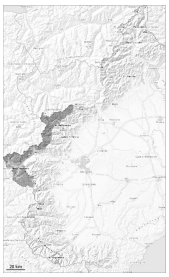

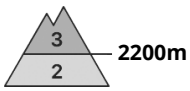

Tendenz: Lawinengefahr bleibt gleich
am Mittwoch, den 25.02.2026

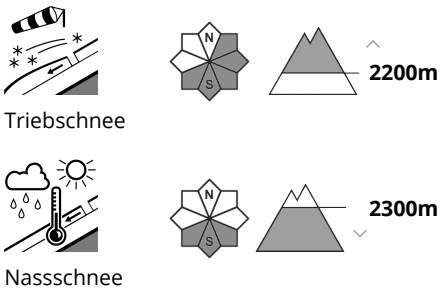

PM:

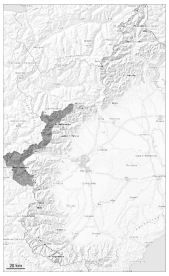

Tendenz: Lawinengefahr bleibt gleich
am Mittwoch, den 25.02.2026

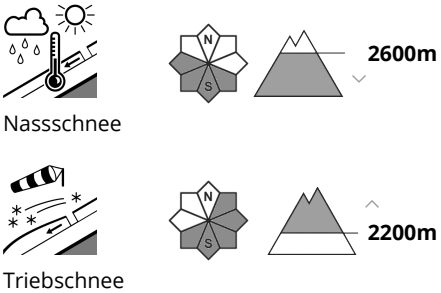

Die Gefahrenstellen für trockene Lawinen liegen vor allem im extremen Steilgelände. Allmählicher Anstieg der Gefahr von trockenen und feuchten Lawinen mit der tageszeitlichen Erwärmung und der Sonneneinstrahlung.

Es ist mild. Vor allem steile Sonnenhänge und Felswandfüße: In tiefen und mittleren Lagen sind mit der Anfeuchtung mittlere und große feuchte und nasse Lawinen möglich. Feuchte Lawinen können unterhalb von rund 2600 m bis in tiefe Schichten durchreißen.

Die frischen und älteren Triebschneeansammlungen können noch ausgelöst werden. Die Lawinen sind meist mittelgroß und vereinzelt von einzelnen Wintersportlern auslösbar.
Entlang der Grenze zu Frankreich sind die Gefahrenstellen weiter verbreitet und die Gefahr höher.

Schneedecke

Gefahrenmuster gm.10: frühjahrssituation | gm.6: lockerer schnee und wind

Bis am Samstag entstanden vor allem an Ost-, Süd- und Südwesthängen teils dicke Triebschneeansammlungen. In Gipfellagen liegen je nach Windeinfluss sehr unterschiedliche Schneehöhen. Der starke Wind hat Neu- und Altschnee verfrachtet.

In windgeschützten Lagen in allen Höhenlagen liegt für die Jahreszeit viel Schnee.

Sonne und Wärme führen ab dem Morgen vor allem an Sonnenhängen zu einer zunehmenden Anfeuchtung der Schneedecke.

Seit Freitag war es sehr mild. Vor allem unterhalb der Waldgrenze: Die Schneeoberfläche gefriert kaum und ist schon am Morgen aufgeweicht.

Tendenz

Es ist sehr mild. Die hohe Luftfeuchtigkeit führt im Tagesverlauf vor allem in tiefen und mittleren Lagen zu einer zunehmenden Anfeuchtung der Schneedecke. Anstieg der Gefahr von feuchten und nassen Lawinen mit der Anfeuchtung. Grundlawinen sind vor allem am Nachmittag möglich.

Gefahrenstufe 3 - Erheblich

AM:

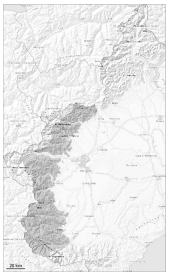

Tendenz: Lawinengefahr bleibt gleich
am Mittwoch, den 25.02.2026

PM:

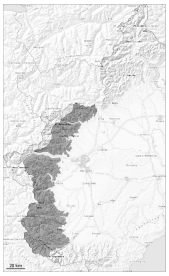

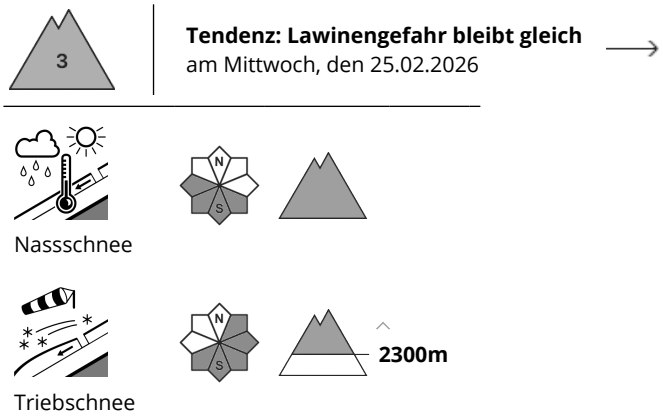

Tendenz: Lawinengefahr bleibt gleich
am Mittwoch, den 25.02.2026

Markanter Anstieg der Gefahr von feuchten und nassen Lawinen mit der tageszeitlichen Erwärmung und der Sonneneinstrahlung. Grundlawinen in tiefen und mittleren Lagen.

Es ist sehr warm. An sehr steilen Sonnenhängen und in tiefen Lagen sind mit der Anfeuchtung mittlere und vereinzelt große feuchte und nasse Lawinen möglich. Feuchte Lawinen können unterhalb von rund 2600 m bis in tiefe Schichten durchreißen und recht groß werden.

Die frischen und älteren Triebschneeansammlungen können noch ausgelöst werden. Die Lawinen sind meist mittelgroß aber vereinzelt von einzelnen Wintersportlern auslösbar, Vorsicht vor allem an Übergängen von wenig zu viel Schnee sowie an Felswandfüßen und hinter Geländekanten.

Schneedecke

Gefahrenmuster gm.10: frühjahrssituation | gm.6: lockerer schnee und wind

Mit Schneefall und starkem Nordwestwind entstanden in den letzten Tagen Triebschneeansammlungen, besonders an kammnahen Ost-, Süd- und Südwesthängen sowie an Felswandfüßen und hinter Geländekanten. In Gipfellagen liegen je nach Windeinfluss sehr unterschiedliche Schneehöhen.

In diesen Gebieten oberhalb von rund 1300 m liegt für die Jahreszeit viel Schnee.

Die frühlingshaften Wetterbedingungen führen ab dem Morgen vor allem an Sonnenhängen unterhalb von rund 2600 m zu einer zunehmenden Anfeuchtung der Schneedecke. Die Schneeoberfläche weicht schneller

auf als am Vortag.
In den letzten zwei Tagen wurden vereinzelt mittlere Schneebrettlawinen von Personen ausgelöst.

Tendenz

Es ist sehr warm. Die hohe Luftfeuchtigkeit führt im Tagesverlauf vor allem in tiefen und mittleren Lagen zu einer zunehmenden Anfeuchtung der Schneedecke. Anstieg der Gefahr von feuchten und nassen Lawinen mit der Anfeuchtung. Grundlawinen sind vor allem am Nachmittag möglich.

Gefahrenstufe 3 - Erheblich

AM:

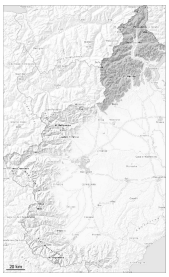

Tendenz: Lawinengefahr bleibt gleich
am Mittwoch, den 25.02.2026

Triebschnee

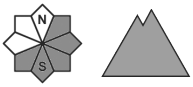

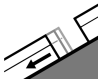

Gleitschnee

PM:

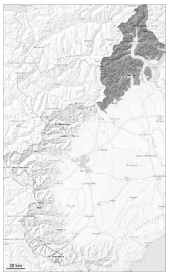

Tendenz: Lawinengefahr bleibt gleich
am Mittwoch, den 25.02.2026

Nassschnee

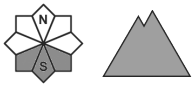

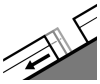

Gleitschnee

Triebschnee

Es ist warm. Die Gefahr von Nass- und Gleitschneelawinen steigt bereits am Vormittag an.

An Sonnenhängen und in tiefen und mittleren Lagen sind mit der Erwärmung mittlere und vereinzelt große feuchte und nasse Lawinen möglich. Feuchte Lawinen können vor allem unterhalb von rund 2600 m bis in tiefe Schichten durchreißen und recht groß werden.

An steilen Grashängen sind Gleitschneelawinen und feuchte Rutsche möglich.

Die Wetterbedingungen begünstigten eine allmähliche Stabilisierung der Triebschneeansammlungen. Die Lawinen sind meist mittelgroß aber teilweise von einzelnen Wintersportlern auslösbar, Vorsicht vor allem an Übergängen von wenig zu viel Schnee.

Schneedecke

Gefahrenmuster gm.10: frühjahrssituation | gm.2: gleitschnee

Mit Schneefall und teils stürmischem Nordwestwind entstanden in den letzten Tagen Triebschneeansammlungen, besonders an kammnahen Nordost-, Süd- und Südwesthängen sowie an Felswandfüßen und hinter Geländekanten.
In Gipfellagen liegen je nach Windeinfluss sehr unterschiedliche Schneehöhen.

Verschiedene Triebschneeschichten liegen stellenweise auf grobkörnigem Altschnee.
Tagesverlauf: Die frühlingshaften Wetterbedingungen führen ab dem Morgen vor allem an Sonnenhängen unterhalb von rund 2600 m zu einer deutlichen Anfeuchtung der Schneedecke. Die Schneeoberfläche weicht schneller auf als am Vortag.

Tendenz

Es ist sehr warm. Die hohe Luftfeuchtigkeit führt im Tagesverlauf vor allem in tiefen und mittleren Lagen zu einer zunehmenden Anfeuchtung der Schneedecke. Anstieg der Gefahr von feuchten und nassen Lawinen mit der Anfeuchtung. Feuchte Lawinen können teilweise die nasse Schneedecke mitreißen und vor allem an sehr steilen Sonnenhängen groß werden.

Gefahrenstufe 3 - Erheblich

AM:

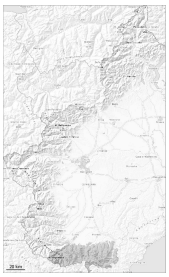

Tendenz: Lawinengefahr bleibt gleich
am Mittwoch, den 25.02.2026

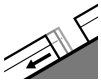

Gleitschnee

Nassschnee

PM:

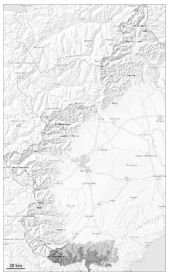

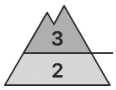

1800m

Tendenz: Lawinengefahr bleibt gleich
am Mittwoch, den 25.02.2026

Nassschnee

1800m

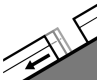

Gleitschnee

Gleitschneelawinen und feuchte Rutsche beachten. Mit der Erwärmung steigt die Auslösebereitschaft von feuchten und nassen Lawinen vor allem an Sonnenhängen an.

Vor allem steile Sonnenhänge und Felswandfüße: Mit der Erwärmung sind mittlere und vereinzelt große trockene und feuchte Lawinen möglich. Touren sollten sehr früh gestartet und rechtzeitig beendet werden.

Die älteren Triebschneeansammlungen können in mittleren und hohen Lagen noch ausgelöst werden. Diese können stellenweise durch Personen ausgelöst werden und mittlere Größe erreichen.
An steilen Grashängen sind Gleitschneelawinen und feuchte Rutsche möglich. Zonen mit Gleitschneerissen sollten gemieden werden.

Schneedecke

Gefahrenmuster gm.10: frühjahrssituation gm.2: gleitschnee

Bis am Samstag entstanden vor allem an Ost-, Süd- und Südwesthängen teils dicke Triebschneeansammlungen. Der starke Wind hat Neu- und Altschnee verfrachtet.
V.a. in Gipfellagen liegen je nach Windeinfluss sehr unterschiedliche Schneehöhen.

Sonne und Wärme führen ab dem Morgen vor allem an Sonnenhängen zu einer zunehmenden Anfeuchtung der Schneedecke.
Seit Freitag war es sehr mild. Vor allem unterhalb der Waldgrenze: Die Schneeoberfläche gefriert kaum und ist schon am Morgen aufgeweicht.

Tendenz

Es ist sehr mild. Die hohe Luftfeuchtigkeit führt im Tagesverlauf vor allem in tiefen und mittleren Lagen zu einer zunehmenden Anfeuchtung der Schneedecke. Anstieg der Gefahr von feuchten und nassen Lawinen mit der Anfeuchtung. Feuchte Lawinen können teilweise die nasse Schneedecke mitreißen und vor allem an sehr steilen Sonnenhängen groß werden.