Dienstag 24.02.2026

Veröffentlicht am 23.02.2026 um 17:00

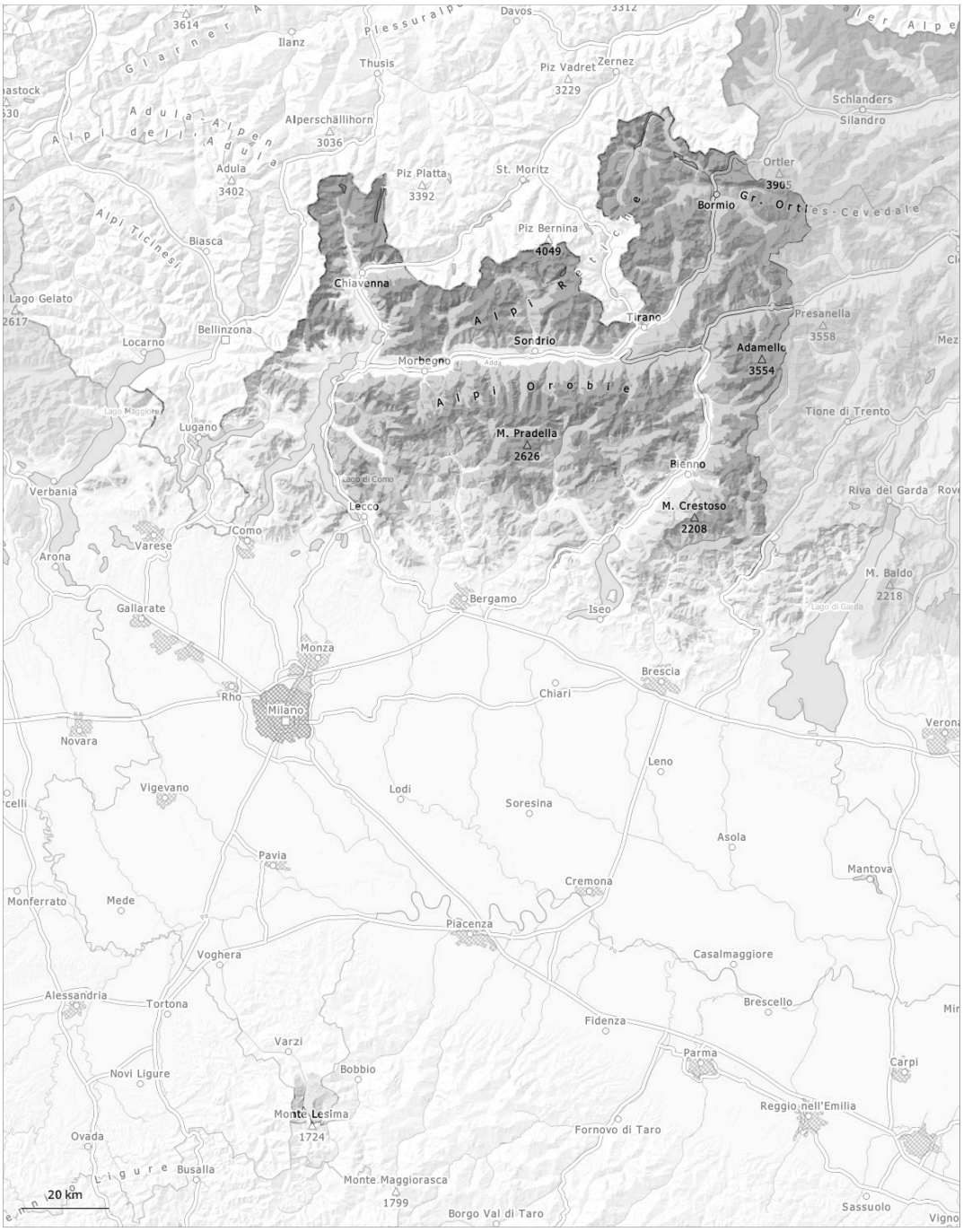

1	2	3	4	5
gering	mäßig	erheblich	groß	sehr groß

Gefahrenstufe 3 - Erheblich

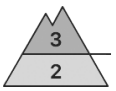

Waldgrenze

Tendenz: Lawinengefahr bleibt gleich
am Mittwoch, den 25.02.2026

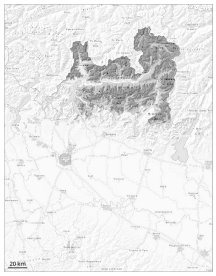

Triebschnee

Waldgrenze

Altschnee

Waldgrenze

Nassschnee

2000m

Die Schneedecke ist oberhalb von rund 1800 m störanfällig. Triebschnee und schwacher Altschnee sind die Hauptgefahr. Schwachschichten im Altschnee erfordern eine defensive Routenwahl.
Mit der tageszeitlichen Erwärmung steigt die Auslösebereitschaft von feuchten Lawinen an Südhängen unterhalb von rund 2000 m an.

Lawinen können leicht ausgelöst werden. Vorsicht vor Triebschnee. Schwachschichten im Altschnee können schon von einzelnen Wintersportlern leicht ausgelöst werden, besonders an steilen West-, Nord- und Osthängen oberhalb der Waldgrenze sowie im Bereich der Waldgrenze. Lawinen können bis auf den Boden durchreißen und sehr groß werden. Die Gefahrenstellen sind zahlreich schwer zu erkennen. Wummgeräusche und Risse beim Betreten der Schneedecke sind Alarmzeichen und weisen auf die Gefahr hin.
Mit der tageszeitlichen Erwärmung steigt die Auslösebereitschaft von feuchten und nassen Lawinen an Südhängen unterhalb von rund 2000 m an.

Schneedecke

Gefahrenmuster gm.6: lockerer schnee und wind | gm.1: bodennahe schwachschicht

Neu- und Triebschnee liegen vor allem an windgeschützten Schattenhängen auf Oberflächenreif. Der untere Teil der Schneedecke ist kantig aufgebaut und schwach. Lawinen können sehr leicht in tieferen Schichten ausgelöst werden.
Zudem sind die frischen Triebschneeansammlungen in Kammlagen, Rinnen und Mulden leicht auslösbar. An Triebschneehängen sind große spontane Lawinen möglich.

Tendenz

> Mit der tageszeitlichen Erwärmung nimmt die Anzahl der Gefahrenstellen im Tagesverlauf zu.

Gefahrenstufe 2 - Mäßig

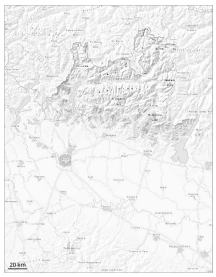

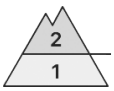

Tendenz: Lawinengefahr bleibt gleich
am Mittwoch, den 25.02.2026

Triebschnee

Nassschnee

Die Triebschneeansammlungen können vor allem an steilen Schattenhängen leicht ausgelöst werden oder vereinzelt spontan abgleiten. Schwachschichten im Altschnee erfordern Vorsicht und Zurückhaltung. Mit der Erwärmung sind kleine und mittlere feuchte Lawinen zu erwarten.

Trockene Lawinen können auch in tieferen Schichten ausgelöst werden.
Erklärung: "Er" darf nur für "der Neuschnee" stehen und insbesondere die teils großen Triebschneeansammlungen können von einzelnen Wintersportlern ausgelöst werden.
Mit der tageszeitlichen Erwärmung steigt die Auslösebereitschaft von feuchten und nassen Lawinen an Südhängen unterhalb von rund 2000 m an.

Schneedecke

Gefahrenmuster gm.6: lockerer schnee und wind | gm.10: frühjahrssituation

In der Altschneedecke sind vor allem an steilen Nordwest-, Nord- und Nordosthängen heikle Schwachschichten vorhanden.

Tendenz

Mit der tageszeitlichen Erwärmung nimmt die Anzahl der Gefahrenstellen im Tagesverlauf zu.

Gefahrenstufe 1 - Gering

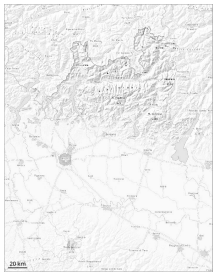

Tendenz: Lawinengefahr bleibt gleich
am Mittwoch, den 25.02.2026

Nassschnee

Mit der Erwärmung steigt die Auslösebereitschaft von feuchten und nassen Lawinen vor allem an steilen Südhängen in tiefen und mittleren Lagen allmählich an.

Mit der Erwärmung steigt die Auslösebereitschaft von feuchten Lawinen an steilen Südhängen in tiefen und mittleren Lagen allmählich an.
Einzelne Tourengeher können stellenweise Lawinen auslösen, auch solche mittlerer Größe.

Schneedecke

Gefahrenmuster gm.10: frühjahrssituation

Tendenz

Mit milden Temperaturen verfestigt sich die Schneedecke.