Dienstag 24.02.2026

Veröffentlicht am 23.02.2026 um 17:00

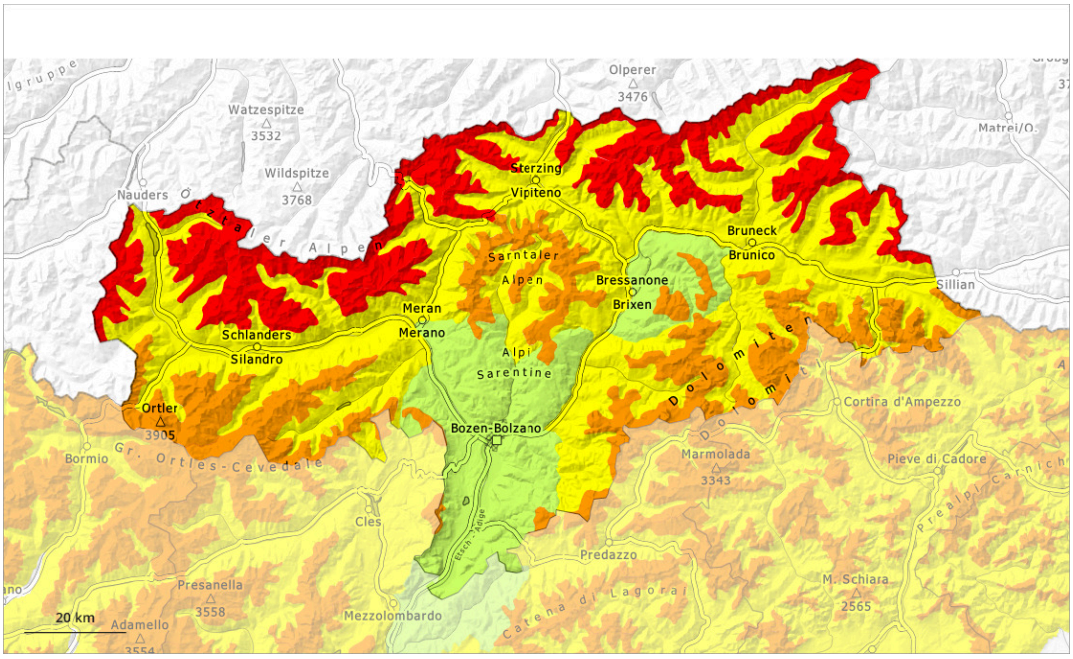

1	2	3	4	5
gering	mäßig	erheblich	groß	sehr groß

Gefahrenstufe 4 - Groß

Waldgrenze

Tendenz: Lawinengefahr bleibt gleich
am Mittwoch, den 25.02.2026

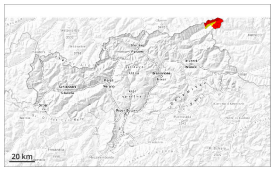

Altschnee

Waldgrenze

Triebschnee

Waldgrenze

Nassschnee

1800m

Im selten befahrenen Gelände gefährliche Lawinensituation.

Mit Neuschnee und starkem bis stürmischem Nordwestwind entstehen in Rinnen, Mulden und hinter Geländekanten sowie oberhalb der Waldgrenze weitere Triebschneeansammlungen. Neu- und Triebschnee der letzten Tage überlagern eine schwache Altschneedecke. Wintersportler können leicht Lawinen auslösen. Lawinen können in tiefe Schichten durchreißen und groß werden. Dies an West-, Nord- und Osthängen. Die Gefahrenstellen sind zahlreich, besonders im Bereich der Waldgrenze sowie oberhalb der Waldgrenze. Spontane Lawinen sind immer noch möglich.

Zudem sind einige Nass- und Gleitschneelawinen möglich. Dies besonders an Böschungen und Grashängen unterhalb von rund 1800 m.

Schneedecke

Gefahrenmuster gm.1: bodennahe schwachschicht | gm.6: lockerer schnee und wind

Am Dienstag fallen 15 bis 30 cm Schnee, lokal auch mehr. Der Wind bläst teils stark bis stürmisch. Der Wind verfrachtet den Neuschnee. Es entstehen weitere Triebschneeansammlungen.

Die Schneedecke ist verbreitet störanfällig. Neu- und Triebschnee überlagern eine schwache Altschneedecke. Im unteren Teil der Altschneedecke sind ausgeprägte Schwachschichten vorhanden. Dies vor allem an West-, Nord- und Osthängen oberhalb der Waldgrenze.

Der Regen führt im Tagesverlauf in tiefen Lagen zu einer allmählichen Durchnässung der Schneedecke.

Tendenz

Kaum Rückgang der Lawinengefahr. Allmählicher Anstieg der Gefahr von nassen Lawinen mit der

Erwärmung.

Gefahrenstufe 4 - Groß

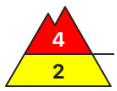

Waldgrenze

Tendenz: Lawinengefahr nimmt ab
am Mittwoch, den 25.02.2026

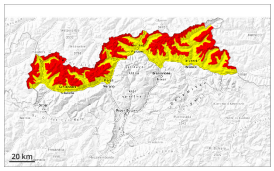

Altschnee

Waldgrenze

Triebschnee

Waldgrenze

Nassschnee

2200m

Abseits gesicherter Pisten gefährliche Lawinensituation.

Triebschneeansammlungen bleiben störanfällig. Vorsicht vor allem an West-, Nord- und Osthängen im Bereich der Waldgrenze sowie oberhalb der Waldgrenze. Einzelne Gefahrenstellen liegen auch an Südost-, Süd- und Südwesthängen oberhalb von rund 2400 m. Lawinen können in oberflächennahen Schichten der Schneedecke ausgelöst werden.
Zudem können Lawinen auch in bodennahe Schichten der Schneedecke durchreißen und an West-, Nord- und Osthängen groß werden. Wummgeräusche und Risse beim Betreten der Schneedecke sowie frische Lawinen sind Alarmzeichen und weisen auf die Gefahr hin. Fernauslösungen sind möglich.

Mit der tageszeitlichen Erwärmung und der Sonneneinstrahlung sind nasse Lockerschneelawinen möglich. Dies besonders an sehr steilen Sonnenhängen unterhalb von rund 2200 m.

Schneedecke

Gefahrenmuster gm.1: bodennahe schwachschicht | gm.10: frühjahrssituation

Es fallen 5 bis 10 cm Schnee, lokal auch mehr. Der teilweise stürmische Wind verfrachtet den Schnee. Es entstehen weitere Triebschneeansammlungen.

Die Schneedecke ist verbreitet störanfällig. Neu- und Triebschnee liegen auf einer günstigen Altschneeoberfläche. Im unteren Teil der Altschneedecke sind ausgeprägte Schwachschichten vorhanden. Dies vor allem an West-, Nord- und Osthängen oberhalb der Waldgrenze.

Die Wetterbedingungen führen im Tagesverlauf zu einer Durchnässung der Schneedecke. Dies besonders an sehr steilen Sonnenhängen.

Tendenz

Kaum Rückgang der Lawinengefahr. Allmählicher Anstieg der Gefahr von nassen Lawinen mit der Erwärmung.

Gefahrenstufe 3 - Erheblich

Waldgrenze

Tendenz: Lawinengefahr bleibt gleich
am Mittwoch, den 25.02.2026

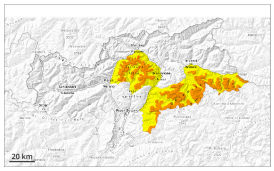

Altschnee

Waldgrenze

Nassschnee

2200m

Schattenhänge: Vorsicht vor schwachem Altschnee. Sehr steile Sonnenhänge: Anstieg der Gefahr von nassen Lawinen mit der Erwärmung.

Lawinen können im Altschnee ausgelöst werden und an West-, Nord- und Osthängen vereinzelt groß werden. Dies durch einzelne Wintersportler. Die Gefahrenstellen liegen vor allem oberhalb der Waldgrenze. In der Sturzbahn können Lawinen den nassen Schnee mitreißen. Dies verlängert die Auslaufstrecken der Lawinen.

Mit der tageszeitlichen Erwärmung und der Sonneneinstrahlung sind kleine und mittlere nasse Lawinen möglich. Dies vor allem an sehr steilen Sonnenhängen unterhalb von rund 2200 m. Die Auslaufbereiche sollten beachtet werden.

Schneedecke

Gefahrenmuster gm.1: bodennahe schwachschicht | gm.10: frühjahrssituation

In der Altschneedecke sind vor allem an West-, Nord- und Osthängen ausgeprägte Schwachschichten vorhanden.

Die nächtliche Abstrahlung ist zeitweise reduziert. Die Wetterbedingungen führen im Tagesverlauf zu einer Durchnässung der Schneedecke. Dies an sehr steilen Sonnenhängen unterhalb von rund 2200 m.

Tendenz

Die Aktivität von nassen Lawinen nimmt zu.

Gefahrenstufe 3 - Erheblich

Waldgrenze

Tendenz: Lawinengefahr bleibt gleich
am Mittwoch, den 25.02.2026

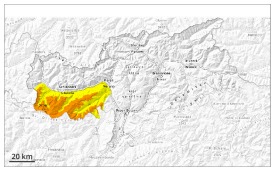

Altschnee

Waldgrenze

Triebschnee

2000m

Nassschnee

2200m

Schattenhänge: Vorsicht vor schwachem Altschnee. Sehr steile Sonnenhänge: Anstieg der Gefahr von nassen Lawinen mit der Erwärmung.

Lawinen können im Altschnee ausgelöst werden und an West-, Nord- und Osthängen vereinzelt groß werden. Dies durch einzelne Wintersportler. Die Gefahrenstellen liegen vor allem oberhalb der Waldgrenze. In der Sturzbahn können Lawinen den nassen Schnee mitreißen. Dies verlängert die Auslaufstrecken der Lawinen.

Triebschneeansammlungen bleiben störanfällig. Vorsicht vor allem an West-, Nord- und Osthängen oberhalb der Waldgrenze sowie in Rinnen, Mulden und hinter Geländekanten.

Mit der tageszeitlichen Erwärmung und der Sonneneinstrahlung sind kleine und mittlere nasse Lawinen möglich. Dies vor allem an sehr steilen Sonnenhängen unterhalb von rund 2200 m. Auch die Auslaufbereiche sollten beachtet werden.

Schneedecke

Gefahrenmuster gm.1: bodennahe schwachschicht | gm.10: frühjahrssituation

Der teilweise stürmische Wind verfrachtet den Schnee. Es entstehen weitere Triebschneeansammlungen. In der Altschneedecke sind vor allem an West-, Nord- und Osthängen ausgeprägte Schwachschichten vorhanden.

Die nächtliche Abstrahlung ist zeitweise reduziert. Die Wetterbedingungen führen im Tagesverlauf zu einer Durchnässung der Schneedecke. Dies an sehr steilen Sonnenhängen unterhalb von rund 2200 m.

Tendenz

Kaum Rückgang der Lawinengefahr. Die Aktivität von nassen Lawinen nimmt allmählich zu.

Gefahrenstufe 3 - Erheblich

Waldgrenze

Tendenz: Lawinengefahr bleibt gleich
am Mittwoch, den 25.02.2026

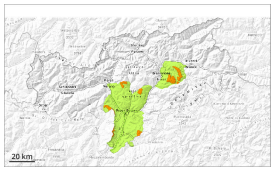

Altschnee

Waldgrenze

Nassschnee

2200m

Frischen Triebschnee kritisch beurteilen. Schwachschichten im Altschnee können vereinzelt ausgelöst werden.

Lawinen können vereinzelt im Altschnee ausgelöst werden und an West-, Nord- und Osthängen mittlere Größe erreichen. Dies durch einzelne Wintersportler. In der Sturzbahn können Lawinen den nassen Schnee mitreißen. Dies verlängert die Auslaufstrecken der Lawinen.

Mit der tageszeitlichen Erwärmung und der Sonneneinstrahlung sind kleine und mittlere nasse Lawinen möglich. Dies vor allem an sehr steilen Sonnenhängen unterhalb von rund 2200 m.

Schneedecke

Gefahrenmuster gm.1: bodennahe schwachschicht | gm.8: eingeschneiter oberflächenreif

In der Altschneedecke sind vor allem an West-, Nord- und Osthängen ausgeprägte Schwachschichten vorhanden.

Die nächtliche Abstrahlung ist zeitweise reduziert. Die Wetterbedingungen führen im Tagesverlauf zu einer Durchnässung der Schneedecke. Dies an sehr steilen Sonnenhängen unterhalb von rund 2200 m.

Tendenz

Die Aktivität von nassen Lawinen nimmt allmählich zu.