Mardi 24.02.2026

Publié 23 02 2026, 17:00

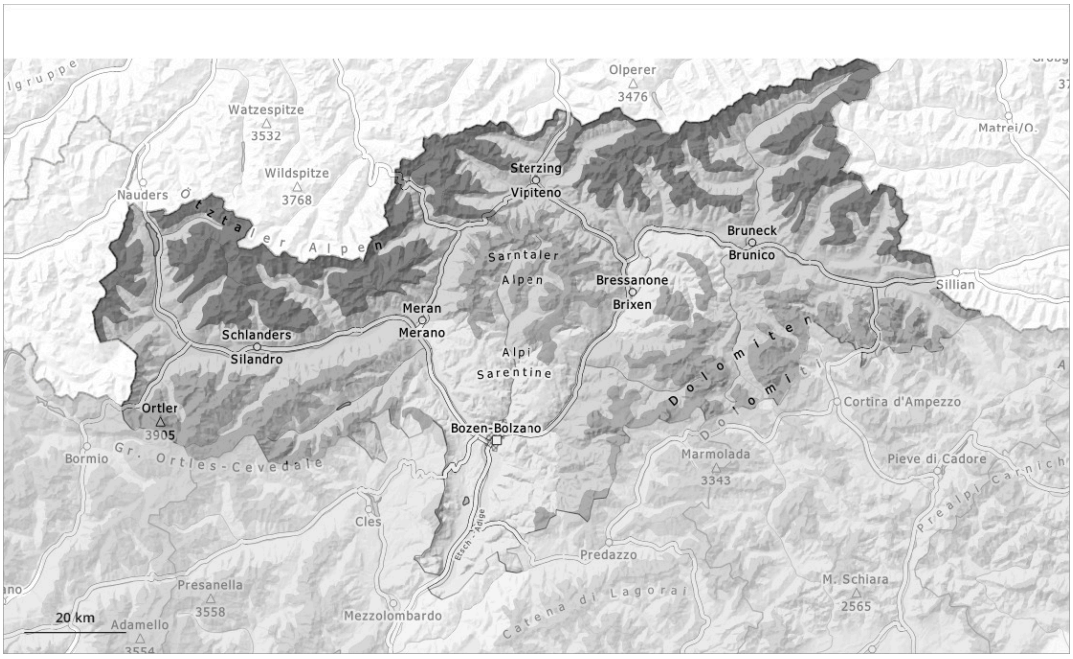

1	2	3	4	5
faible	limité	marqué	fort	très fort

Degré de danger 4 - Fort

Limite de la forêt

Tendance: danger d'avalanche constant
leMercredi 25 02 2026

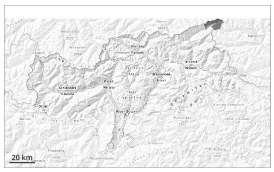

Neige ancienne (Sous-couche fragile persistante)

Limite de la forêt

Neige soufflée (Neige ventée)

Limite de la forêt

Avalanches mouillées (Neige humide)

1800m

Sur les terrains rarement fréquentés situation avalancheuse dangereuse.

Des accumulations de neige soufflée supplémentaires se forment avec la neige fraîche et le vent de nord-ouest fort à tempétueux dans les combes, couloirs et derrière les ruptures de terrain ainsi qu'au-dessus de la limite de la forêt. La neige fraîche et la neige soufflée des derniers jours reposent sur une couche fragile de neige ancienne. Des amateurs de sports d'hiver peuvent facilement déclencher des avalanches. Des avalanches peuvent entraîner avec elles les couches plus profondes du manteau neigeux et atteindre une grande taille. Ceci sur les pentes exposées à l'ouest, au nord et à l'est. Les endroits dangereux sont nombreux, notamment dans la zone de la limite de la forêt comme au-dessus de la limite de la forêt. Des avalanches spontanées sont encore toujours possibles.

En outre, quelques avalanches de neige mouillée et de glissement sont possibles. Ceci particulièrement sur les talus et pentes herbeuses en dessous d'environ 1800 m.

Manteau neigeux

Modèles de danger md.1: sous-couche fragile persistante | md.6: froid, neige légère et vent

Mardi il tombera de 15 à 30 cm de neige, localement plus. Le vent souffle partiellement fortement à tempétueusement. Le vent transporte la neige fraîche. Des accumulations de neige soufflée supplémentaires se forment.

En général le manteau neigeux est fragile. La neige fraîche et la neige soufflée reposent sur une couche fragile de neige ancienne. Dans la partie inférieure du manteau neigeux ancien des couches fragiles importantes sont présentes. Ceci surtout sur les pentes exposées à l'ouest, au nord et à l'est au-dessus de la limite de la forêt.

La pluie entraîne en cours de journée à basse altitude une saturation d'eau progressive du manteau neigeux.

Tendance

Diminution à peine marquée du danger d'avalanches. Augmentation progressive du danger d'avalanches mouillées avec le réchauffement.

Degré de danger 4 - Fort

Limite de la forêt

Tendance: Diminution du danger d'avalanche
leMercredi 25 02 2026

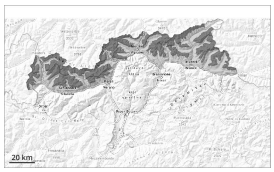

Neige ancienne (Sous-couche fragile persistante)

Limite de la forêt

Neige soufflée (Neige ventée)

Limite de la forêt

Avalanches mouillées (Neige humide)

2200m

En dehors des pistes sécurisées situation avalancheuse dangereuse.

Des accumulations de neige soufflée restent fragiles. Prudence surtout sur les pentes exposées à l'ouest, au nord et à l'est dans la zone de la limite de la forêt comme au-dessus de la limite de la forêt. Quelques endroits dangereux se situent aussi sur les pentes exposées au sud-est, au sud et au sud-ouest au-dessus d'environ 2400 m. Des avalanches peuvent être déclenchées dans les couches du manteau neigeux proches de la surface.
En outre, des avalanches peuvent aussi se déclencher dans les couches du manteau neigeux proches du sol et sur les pentes exposées à l'ouest, au nord et à l'est atteindre une grande taille. Des bruits sourds et des fissures lors du passage sur le manteau neigeux ainsi que des avalanches récentes sont des signes d'alarme qui attirent l'attention sur le danger. Des déclenchements à distance sont possibles.

Des avalanches de neige meuble mouillée sont possibles avec le réchauffement diurne et le rayonnement solaire. Ceci particulièrement sur les pentes très raides ensoleillées en dessous d'environ 2200 m.

Manteau neigeux

Modèles de danger md.1: sous-couche fragile persistante md.10: situation de printemps

Il tombe de 5 à 10 cm de neige, localement plus. Le vent parfois tempétueux transporte la neige. Des accumulations de neige soufflée supplémentaires se forment.

En général le manteau neigeux est fragile. La neige fraîche et la neige soufflée reposent sur une surface de neige ancienne favorable. Dans la partie inférieure du manteau neigeux ancien des couches fragiles importantes sont présentes. Ceci surtout sur les pentes exposées à l'ouest, au nord et à l'est au-dessus de la limite de la forêt.

Les conditions météorologiques entraînent en cours de journée une saturation d'eau du manteau neigeux. Ceci particulièrement sur les pentes très raides ensoleillées.

Tendance

Diminution à peine marquée du danger d'avalanches. Augmentation progressive du danger d'avalanches mouillées avec le réchauffement.

Degré de danger 3 - Marqué

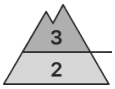

Limite de la forêt

Tendance: danger d'avalanche constant
leMercredi 25 02 2026

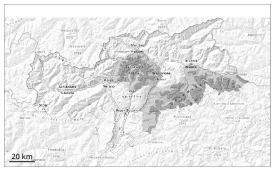

Neige ancienne (Sous-couche fragile persistante)

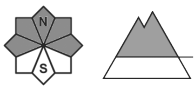

Limite de la forêt

Avalanches mouillées (Neige humide)

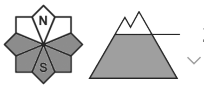

2200m

Sur les pentes à l'ombre: Attention à la neige ancienne fragile. Sur les pentes très raides ensoleillées: Augmentation du danger d'avalanches mouillées avec le réchauffement.

Des avalanches peuvent être déclenchées dans la neige ancienne et sur les pentes exposées à l'ouest, au nord et à l'est atteindre une grande taille de manière isolée. Ceci par un seul adepte des sports d'hiver. Les endroits dangereux se situent surtout au-dessus de la limite de la forêt. Dans leurs parcours, les avalanches peuvent entraîner la neige mouillée. Ceci prolonge les distances d'arrêt des avalanches.

Des avalanches mouillées de petite et moyenne taille sont possibles avec le réchauffement diurne et le rayonnement solaire. Ceci surtout sur les pentes très raides ensoleillées en dessous d'environ 2200 m. Les zones de dépôt doivent être prises en considération.

Manteau neigeux

Modèles de danger md.1: sous-couche fragile persistante md.10: situation de printemps

Dans le manteau neigeux ancien des couches fragiles importantes sont présentes, surtout sur les pentes exposées à l'ouest, au nord et à l'est.

Le rayonnement nocturne est parfois réduit. Les conditions météorologiques entraînent en cours de journée une saturation d'eau du manteau neigeux. Ceci sur les pentes très raides ensoleillées en dessous d'environ 2200 m.

Tendance

> L'activité des avalanches humides augmente.

Degré de danger 3 - Marqué

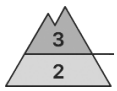

Limite de la forêt

Tendance: danger d'avalanche constant
leMercredi 25 02 2026

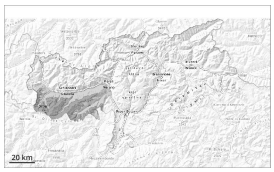

Neige ancienne (Sous-couche fragile persistante)

Limite de la forêt

Neige soufflée (Neige ventée)

2000m

Avalanches mouillées (Neige humide)

2200m

Sur les pentes à l'ombre: Attention à la neige ancienne fragile. Sur les pentes très raides ensoleillées: Augmentation du danger d'avalanches mouillées avec le réchauffement.

Des avalanches peuvent être déclenchées dans la neige ancienne et sur les pentes exposées à l'ouest, au nord et à l'est atteindre une grande taille de manière isolée. Ceci par un seul adepte des sports d'hiver. Les endroits dangereux se situent surtout au-dessus de la limite de la forêt. Dans leurs parcours, les avalanches peuvent entraîner la neige mouillée. Ceci prolonge les distances d'arrêt des avalanches.

Des accumulations de neige soufflée restent fragiles. Prudence surtout sur les pentes exposées à l'ouest, au nord et à l'est au-dessus de la limite de la forêt comme dans les combes, couloirs et derrière les ruptures de terrain.

Des avalanches mouillées de petite et moyenne taille sont possibles avec le réchauffement diurne et le rayonnement solaire. Ceci surtout sur les pentes très raides ensoleillées en dessous d'environ 2200 m. Aussi les zones de dépôt doivent être prises en considération.

Manteau neigeux

Modèles de danger md.1: sous-couche fragile persistante | md.10: situation de printemps

Le vent parfois tempétueux transporte la neige. Des accumulations de neige soufflée supplémentaires se forment.
Dans le manteau neigeux ancien des couches fragiles importantes sont présentes, surtout sur les pentes exposées à l'ouest, au nord et à l'est.

Le rayonnement nocturne est parfois réduit. Les conditions météorologiques entraînent en cours de journée une saturation d'eau du manteau neigeux. Ceci sur les pentes très raides ensoleillées en dessous d'environ 2200 m.

Tendance

Diminution à peine marquée du danger d'avalanches. L'activité des avalanches humides augmente progressivement.

Degré de danger 3 - Marqué

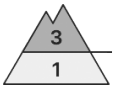

Limite de la forêt

Tendance: danger d'avalanche constant
leMercredi 25 02 2026

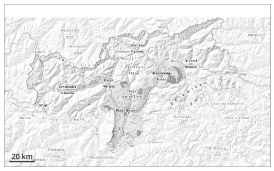

Neige ancienne (Sous-couche fragile persistante)

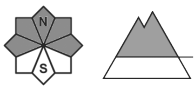

Limite de la forêt

Avalanches mouillées (Neige humide)

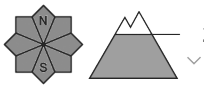

2200m

Neige récemment soufflée à évaluer de manière critique. Des couches fragiles dans la neige ancienne peuvent être déclenchées de manière isolée.

Des avalanches peuvent de manière isolée être déclenchées dans la neige ancienne et sur les pentes exposées à l'ouest, au nord et à l'est atteindre une taille moyenne. Ceci par un seul adepte des sports d'hiver. Dans leurs parcours, les avalanches peuvent entraîner la neige mouillée. Ceci prolonge les distances d'arrêt des avalanches.

Des avalanches mouillées de petite et moyenne taille sont possibles avec le réchauffement diurne et le rayonnement solaire. Ceci surtout sur les pentes très raides ensoleillées en dessous d'environ 2200 m.

Manteau neigeux

Modèles de danger md.1: sous-couche fragile persistante md.8: givre de surface enneigé

Dans le manteau neigeux ancien des couches fragiles importantes sont présentes, surtout sur les pentes exposées à l'ouest, au nord et à l'est.

Le rayonnement nocturne est parfois réduit. Les conditions météorologiques entraînent en cours de journée une saturation d'eau du manteau neigeux. Ceci sur les pentes très raides ensoleillées en dessous d'environ 2200 m.

Tendance

L'activité des avalanches humides augmente progressivement.