Martedì 24.02.2026

Pubblicato il 23.02.2026 alle ore 17:00

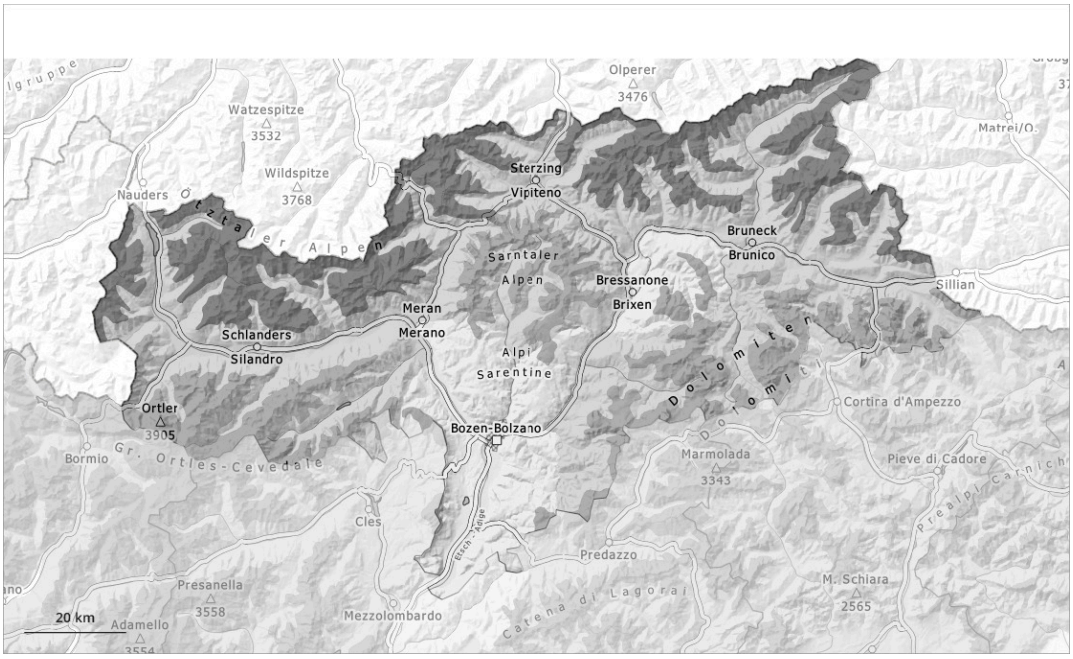

1	2	3	4	5
debole	moderato	marcato	forte	molto forte

Grado di pericolo 4 - Forte

Limite del bosco

Tendenza: pericolo valanghe stabile
per Mercoledì il 25.02.2026

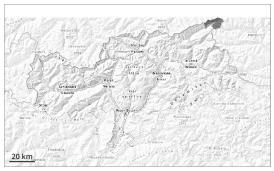

Strati deboli persistenti

Limite del bosco

Lastrone da vento

Limite del bosco

Neve bagnata

1800m

Nelle zone poco frequentate, la situazione valanghiva è pericolosa.

Con neve fresca e vento da forte a tempestoso proveniente da nord ovest nelle conche, nei canaloni e dietro ai cambi di pendenza così come al di sopra del limite del bosco si formeranno ulteriori accumuli di neve ventata. La neve fresca e la neve ventata degli ultimi giorni ricoprono un debole manto di neve vecchia. Un appassionato di sport invernali può facilmente provocare il distacco di valanghe. Le valanghe possono coinvolgere gli strati più profondi e raggiungere grandi dimensioni. Ciò sui pendii esposti a ovest, nord ed est. I punti pericolosi sono numerosi, soprattutto in prossimità del limite del bosco, come pure al di sopra del limite del bosco. Tuttora sono possibili valanghe spontanee.

Inoltre sono possibili alcune valanghe bagnate e di slittamento. Ciò specialmente sulle scarpate e sui pendii erbosi al di sotto dei 1800 m circa.

Manto nevoso

Situazione tipo st.1: strato debole persistente basale | st.6: neve a debole coesione e vento

Martedì cadranno da 15 a 30 cm di neve, localmente anche di più. Il vento sarà in parte da forte a tempestoso. Il vento causerà il trasporto della neve fresca. Si formeranno ulteriori accumuli di neve ventata.

Il manto nevoso è instabile in molti punti. La neve fresca e la neve ventata ricoprono un debole manto di neve vecchia. Nella parte basale del manto di neve vecchia si trovano pronunciati strati fragili. Ciò soprattutto sui pendii esposti a ovest, nord ed est al di sopra del limite del bosco.

Nel corso della giornata la pioggia causerà a bassa quota un graduale impregnamento del manto nevoso.

Tendenza

Scarso calo del pericolo di valanghe. Con il rialzo termico, progressivo aumento del pericolo di valanghe di neve bagnata.

Grado di pericolo 4 - Forte

Limite del bosco

Tendenza: pericolo valanghe in diminuzione
per Mercoledì il 25.02.2026

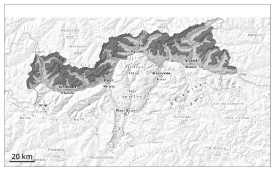

Strati deboli persistenti

Limite del bosco

Lastrone da vento

Limite del bosco

Neve bagnata

2200m

Al di fuori delle piste assicurate, la situazione valanghiva è pericolosa.

Gli accumuli di neve ventata rimangono instabili. Attenzione soprattutto sui pendii esposti a ovest, nord ed est in prossimità del limite del bosco, come pure al di sopra del limite del bosco. Isolati punti pericolosi si trovano anche sui pendii esposti a sud est, sud e sud ovest al di sopra dei 2400 m circa. Le valanghe possono distaccarsi coinvolgendo gli strati superficiali del manto.
Inoltre, le valanghe possono anche distaccarsi coinvolgendo gli strati basali del manto e, sui pendii esposti a ovest, nord ed est, raggiungere grandi dimensioni. I rumori di "whum" e la formazione di fessure quando si calpesta la coltre di neve così come nuove valanghe sono campanelli di allarme che rimandano a questo pericolo. Sono possibili distacchi a distanza.

Con il rialzo termico e l'irradiazione solare diurni, sono possibili valanghe di neve bagnata a debole coesione. Ciò specialmente sui pendii soleggiati molto ripidi al di sotto dei 2200 m circa.

Manto nevoso

Situazione tipo st.1: strato debole persistente basale | st.10: situazione primaverile

Cadranno da 5 a 10 cm di neve, localmente anche di più. Il vento a tratti tempestoso causerà il trasporto della neve. Si formeranno ulteriori accumuli di neve ventata.

Il manto nevoso è instabile in molti punti. La neve fresca e la neve ventata poggiano su una superficie del manto di neve vecchia per lo più favorevole. Nella parte basale del manto di neve vecchia si trovano pronunciati strati fragili. Ciò soprattutto sui pendii esposti a ovest, nord ed est al di sopra del limite del bosco.

Nel corso della giornata le condizioni meteo causeranno un impregnamento del manto nevoso. Ciò specialmente sui pendii soleggiati molto ripidi.

Tendenza

Scarso calo del pericolo di valanghe. Con il rialzo termico, progressivo aumento del pericolo di valanghe di neve bagnata.

Grado di pericolo 3 - Marcato

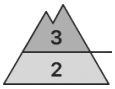

Limite del bosco

Tendenza: pericolo valanghe stabile
per Mercoledì il 25.02.2026

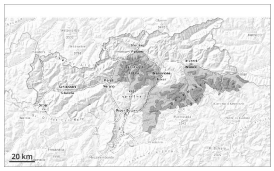

Strati deboli persistenti

Limite del bosco

Neve bagnata

2200m

Sui pendii ombreggiati: Attenzione alla neve vecchia con strati deboli persistenti. Sui pendii molto ripidi esposti al sole: Con il rialzo termico, aumento del pericolo di valanghe di neve bagnata.

Le valanghe possono subire un distacco nella neve vecchia e, sui pendii esposti a ovest, nord ed est, raggiungere grandi dimensioni a livello isolato. Ciò da parte di un singolo appassionato di sport invernali. I punti pericolosi si trovano soprattutto al di sopra del limite del bosco. Nella zona di scorrimento le valanghe possono trascinare la neve bagnata. Ciò aumenta la distanza d'arresto delle valanghe.

Con il rialzo termico e l'irradiazione solare diurni, sono possibili valanghe di neve bagnata di piccole e medie dimensioni. Ciò soprattutto sui pendii soleggiati molto ripidi al di sotto dei 2200 m circa. Fare attenzione alle zone di deposito.

Manto nevoso

Situazione tipo st.1: strato debole persistente basale | st.10: situazione primaverile

Soprattutto sui pendii esposti a ovest, nord ed est, all'interno del manto di neve vecchia si trovano pronunciati strati fragili.

L'irraggiamento notturno sarà temporaneamente ridotto. Nel corso della giornata le condizioni meteo causeranno un impregnamento del manto nevoso. Ciò sui pendii soleggiati molto ripidi al di sotto dei 2200 m circa.

Tendenza

L'attività di valanghe di neve bagnata aumenterà.

Grado di pericolo 3 - Marcato

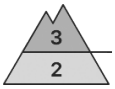

Limite del bosco

Tendenza: pericolo valanghe stabile
per Mercoledì il 25.02.2026

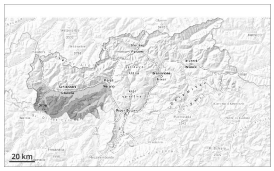

Strati deboli persistenti

Limite del bosco

Lastrone da vento

2000m

Neve bagnata

2200m

Sui pendii ombreggiati: Attenzione alla neve vecchia con strati deboli persistenti. Sui pendii molto ripidi esposti al sole: Con il rialzo termico, aumento del pericolo di valanghe di neve bagnata.

Le valanghe possono subire un distacco nella neve vecchia e, sui pendii esposti a ovest, nord ed est, raggiungere grandi dimensioni a livello isolato. Ciò da parte di un singolo appassionato di sport invernali. I punti pericolosi si trovano soprattutto al di sopra del limite del bosco. Nella zona di scorrimento le valanghe possono trascinare la neve bagnata. Ciò aumenta la distanza d'arresto delle valanghe.

Gli accumuli di neve ventata rimangono instabili. Attenzione soprattutto sui pendii esposti a ovest, nord ed est al di sopra del limite del bosco, come pure nelle conche, nei canaloni e dietro ai cambi di pendenza.

Con il rialzo termico e l'irradiazione solare diurni, sono possibili valanghe di neve bagnata di piccole e medie dimensioni. Ciò soprattutto sui pendii soleggiati molto ripidi al di sotto dei 2200 m circa. Fare attenzione anche alle zone di deposito.

Manto nevoso

Situazione tipo st.1: strato debole persistente basale | st.10: situazione primaverile

Il vento a tratti tempestoso causerà il trasporto della neve. Si formeranno ulteriori accumuli di neve ventata.
Soprattutto sui pendii esposti a ovest, nord ed est, all'interno del manto di neve vecchia si trovano pronunciati strati fragili.

L'irraggiamento notturno sarà temporaneamente ridotto. Nel corso della giornata le condizioni meteo causeranno un impregnamento del manto nevoso. Ciò sui pendii soleggiati molto ripidi al di sotto dei 2200 m circa.

Tendenza

Scarso calo del pericolo di valanghe. L'attività di valanghe di neve bagnata aumenterà progressivamente.

Grado di pericolo 3 - Marcato

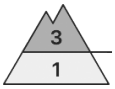

Limite del bosco

Tendenza: pericolo valanghe stabile
per Mercoledì il 25.02.2026

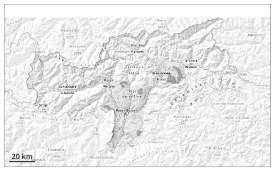

Strati deboli persistenti

Limite del bosco

Neve bagnata

2200m

La neve ventata recente deve essere valutata con spirito critico. Gli strati deboli presenti nella neve vecchia possono distaccarsi a livello isolato.

Le valanghe possono a livello isolato subire un distacco nella neve vecchia e, sui pendii esposti a ovest, nord ed est, raggiungere dimensioni medie. Ciò da parte di un singolo appassionato di sport invernali. Nella zona di scorrimento le valanghe possono trascinare la neve bagnata. Ciò aumenta la distanza d'arresto delle valanghe.

Con il rialzo termico e l'irradiazione solare diurni, sono possibili valanghe di neve bagnata di piccole e medie dimensioni. Ciò soprattutto sui pendii soleggiati molto ripidi al di sotto dei 2200 m circa.

Manto nevoso

Situazione tipo st.1: strato debole persistente basale | st.8: brina di superficie sepolta

Soprattutto sui pendii esposti a ovest, nord ed est, all'interno del manto di neve vecchia si trovano pronunciati strati fragili.

L'irraggiamento notturno sarà temporaneamente ridotto. Nel corso della giornata le condizioni meteo causeranno un impregnamento del manto nevoso. Ciò sui pendii soleggiati molto ripidi al di sotto dei 2200 m circa.

Tendenza

L'attività di valanghe di neve bagnata aumenterà progressivamente.