# Dienstag 24.02.2026

Veröffentlicht am 23.02.2026 um 17:00

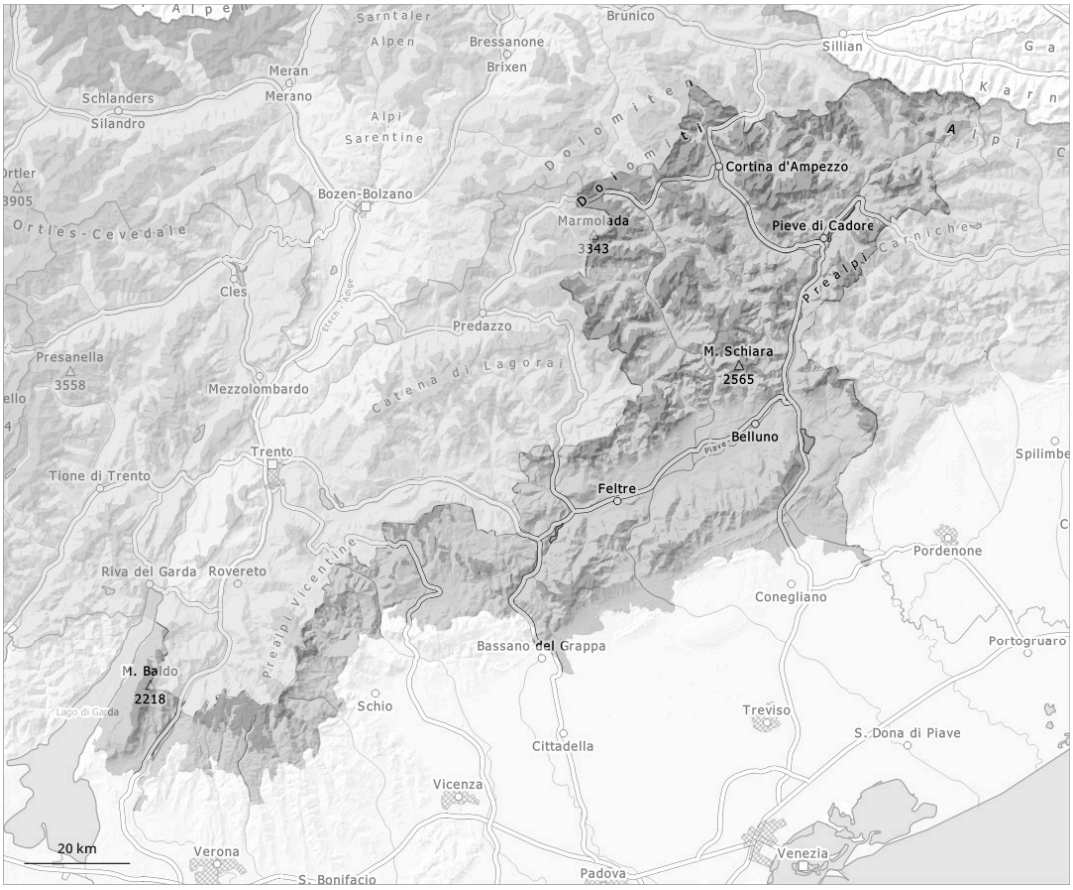


| 1 | 2 | 3 | 4 | 5 |
|---|---|---|---|---|
| gering | mäßig | erheblich | groß | sehr groß |

## Gefahrenstufe 3 - Erheblich

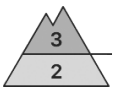


**Waldgrenze**

**Tendenz: Lawinengefahr bleibt gleich**
am Mittwoch, den 25.02.2026

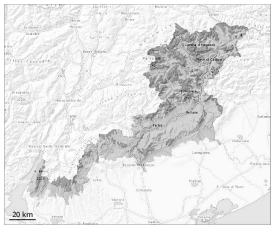

Triebschnee

**Waldgrenze**

Altschnee

**Waldgrenze**

Nassschnee

**2300m**

## Vorsicht vor Triebschnee und schwachem Altschnee. Nasse Lawinen im Tagesverlauf.

Besonders in Kammlagen, Rinnen und Mulden entstanden flächige Triebschneeansammlungen. Die Gefahrenstellen liegen vor allem an Triebschneehängen aller Expositionen oberhalb von rund 1900 m sowie an Übergängen von wenig zu viel Schnee.
Die Lawinen können an steilen Schattenhängen in tiefen Schichten ausgelöst werden und recht groß werden. Dies durch einzelne Wintersportler. In der Sturzbahn können Lawinen den nassen Schnee mitreißen.
Mit der tageszeitlichen Erwärmung steigt die Gefahr von feuchten und nassen Lawinen im Tagesverlauf an. Touren sollten rechtzeitig beendet werden.

## Schneedecke

**Gefahrenmuster** gm.1: bodennahe schwachschicht | gm.10: frühjahrssituation

Der Wind bläst lokal mäßig bis stark. Vor allem oberhalb von rund 1900 m entstanden gut sichtbare Triebschneeansammlungen.
In der Altschneedecke sind vor allem an steilen Nord-, Ost- und Westhängen Schwachschichten vorhanden. Die nächtliche Abstrahlung ist zeitweise reduziert. Sonne und Wärme führen im Tagesverlauf vor allem an sehr steilen Sonnenhängen unterhalb von rund 2300 m zu einer raschen Anfeuchtung der Schneedecke.

## Tendenz

Die Gefahr von feuchten und nassen Lawinen steigt an.