Mardi 24.02.2026

Publié 23 02 2026, 17:00

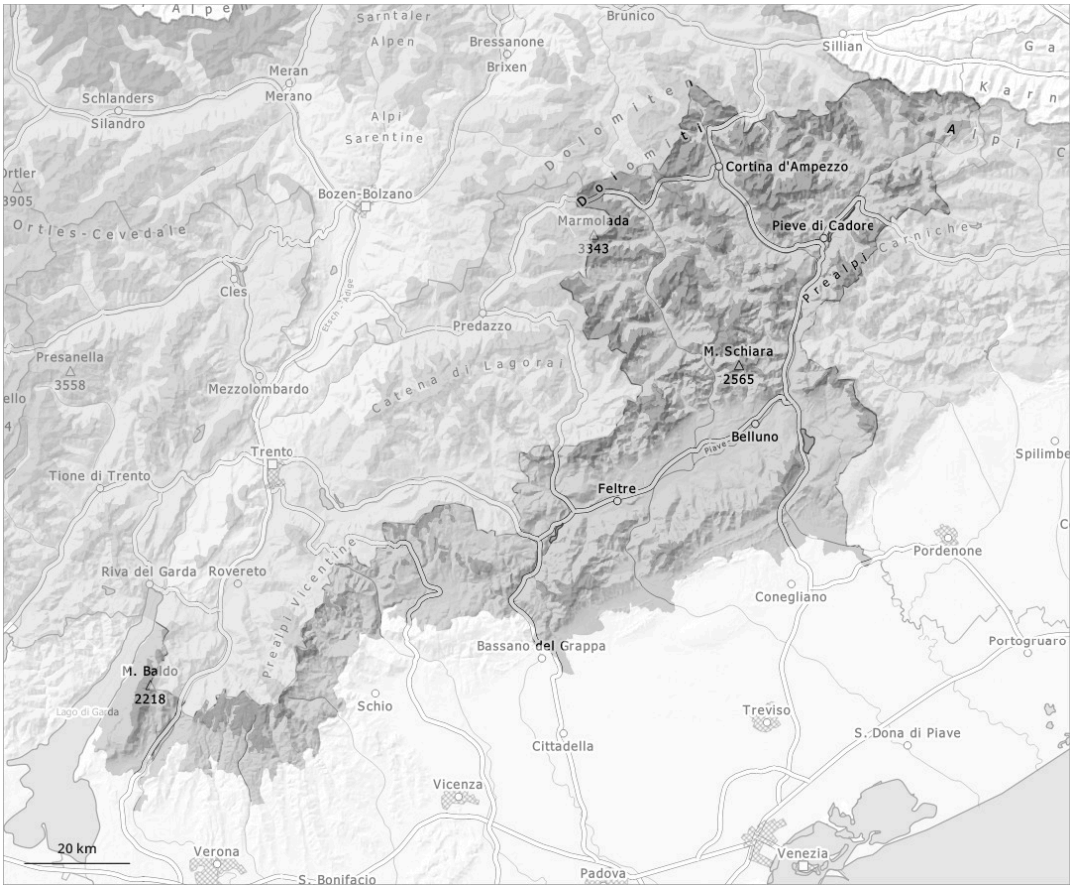

1	2	3	4	5
faible	limité	marqué	fort	très fort

Degré de danger 3 - Marqué

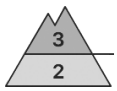

Limite de la forêt

Tendance: danger d'avalanche constant
leMercredi 25 02 2026

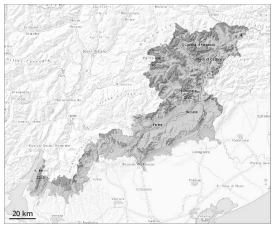

Neige soufflée
(Neige ventée)

Limite de la forêt

Neige
ancienne
(Sous-couche
fragile
persistante)

Limite de la forêt

Avalanches
mouillées
(Neige
humide)

2300m

Attention à la neige soufflée et neige ancienne fragile. Avalanches mouillées en cours de journée.

Des accumulations de neige soufflée étendues se sont formées spécialement à proximité des crêtes, dans les combes et couloirs. Les endroits dangereux se trouvent Surtout sur les pentes où s'est accumulée la neige soufflée à toutes les expositions au-dessus d'environ 1900 m ainsi qu'aux transitions entre les endroits faiblement et fortement enneigés.
Les avalanches peuvent être déclenchées dans les couches profondes sur les pentes raides à l'ombre et atteindre une taille assez importante. Ceci par un seul adepte des sports d'hiver. Dans leurs parcours, les avalanches peuvent entraîner la neige mouillée.
Avec le réchauffement diurne le danger d'avalanches humides et mouillées augmente en cours de journée. Les randonnées devraient être terminées à temps.

Manteau neigeux

Modèles de danger md.1: sous-couche fragile persistante md.10: situation de printemps

Le vent souffle modérément à fortement localement. Des accumulations de neige soufflée bien visibles se sont formées surtout au-dessus d'environ 1900 m.
Dans le manteau neigeux ancien des couches fragiles sont présentes, surtout sur les pentes raides exposées au nord, à l'est et à l'ouest.
Le rayonnement nocturne est parfois réduit. Le soleil et la chaleur entraînent en cours de journée surtout

sur les pentes très raides au soleil en dessous d'environ 2300 m une humidification rapide du manteau neigeux.

Tendance

Le danger d'avalanches humides et mouillées augmente.