Martedì 24.02.2026

Pubblicato il 23.02.2026 alle ore 17:00

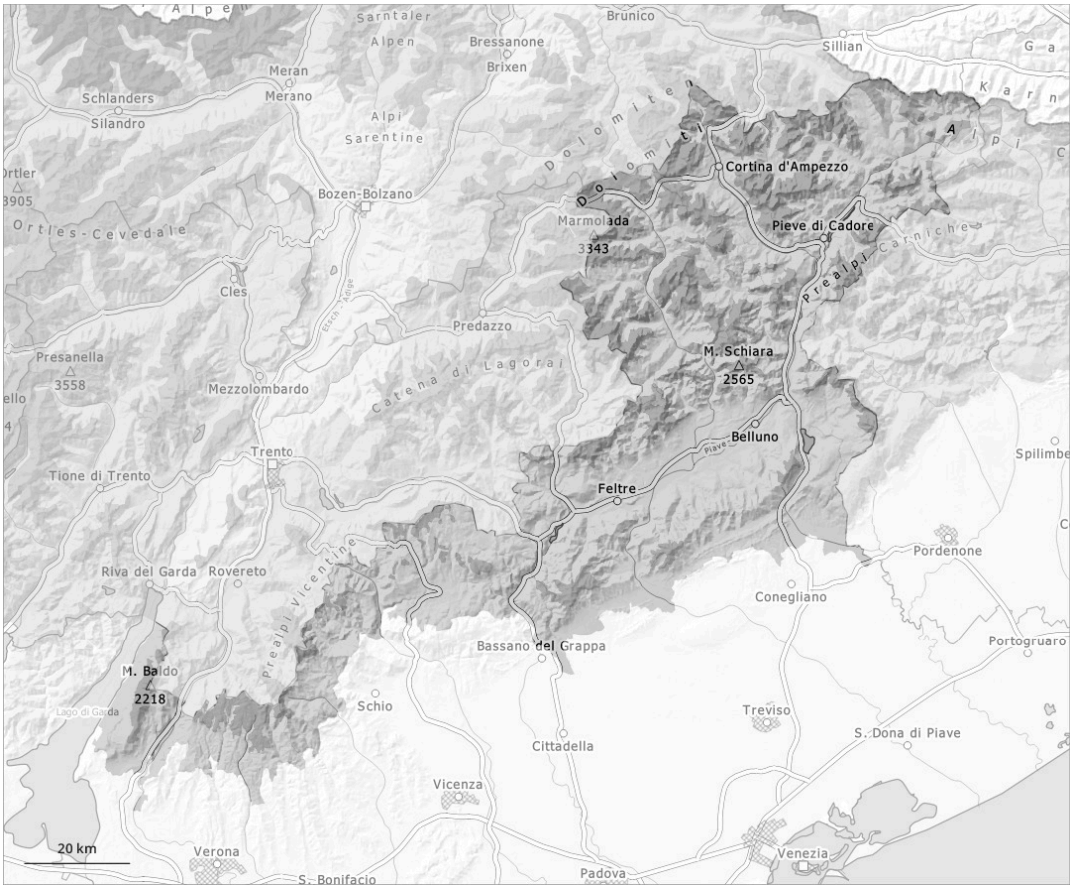

1	2	3	4	5
debole	moderato	marcato	forte	molto forte

Grado di pericolo 3 - Marcato

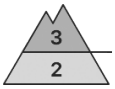

Limite del bosco

Tendenza: pericolo valanghe stabile
per Mercoledì il 25.02.2026

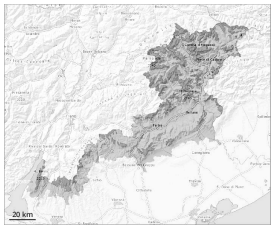

Lastrone da vento

Limite del bosco

Strati deboli persistenti

Limite del bosco

Neve bagnata

2300m

Attenzione alla neve ventata e alla neve vecchia a debole coesione. Valanghe bagnate durante la giornata.

Principalmente nelle zone in prossimità delle creste, nelle conche e nei canaloni si sono formati estesi accumuli di neve ventata. I punti pericolosi si trovano soprattutto sui pendii carichi di neve soffiata esposti in tutte le direzioni al di sopra dei 1900 m circa come pure nelle zone di passaggio da poca a molta neve. Sui pendii ombreggiati ripidi le valanghe possono subire un distacco negli strati più profondi del manto nevoso e raggiungere dimensioni piuttosto grandi. Ciò da parte di un singolo appassionato di sport invernali. Nella zona di scorrimento le valanghe possono trascinare la neve bagnata.
Con il rialzo termico diurno, nel corso della giornata il pericolo di valanghe umide e bagnate aumenterà. Le escursioni dovrebbero terminare in tempo.

Manto nevoso

Situazione tipo st.1: strato debole persistente basale | st.10: situazione primaverile

A livello locale, il vento sarà da moderato a forte. Soprattutto al di sopra dei 1900 m circa si sono formati accumuli di neve ventata ben visibili.
Soprattutto sui pendii ripidi esposti a nord, est e ovest, all'interno del manto di neve vecchia si trovano strati fragili.
L'irraggiamento notturno sarà temporaneamente ridotto. Il sole e il calore causeranno nel corso della giornata soprattutto sui pendii soleggiati molto ripidi al di sotto dei 2300 m circa un rapido inumidimento del manto nevoso.

Tendenza

> Il pericolo di valanghe umide e bagnate aumenterà.