ICGC Institut Cartogràfic i Geològic de Catalunya

Servei Meteorològic de Catalunya meteo.cat

Boletín de peligro de aludes para el Pirineo de Catalunya
Del 23/02/2026 al 24/02/2026

(Válido fuera pistas de esquí y zonas no controladas)

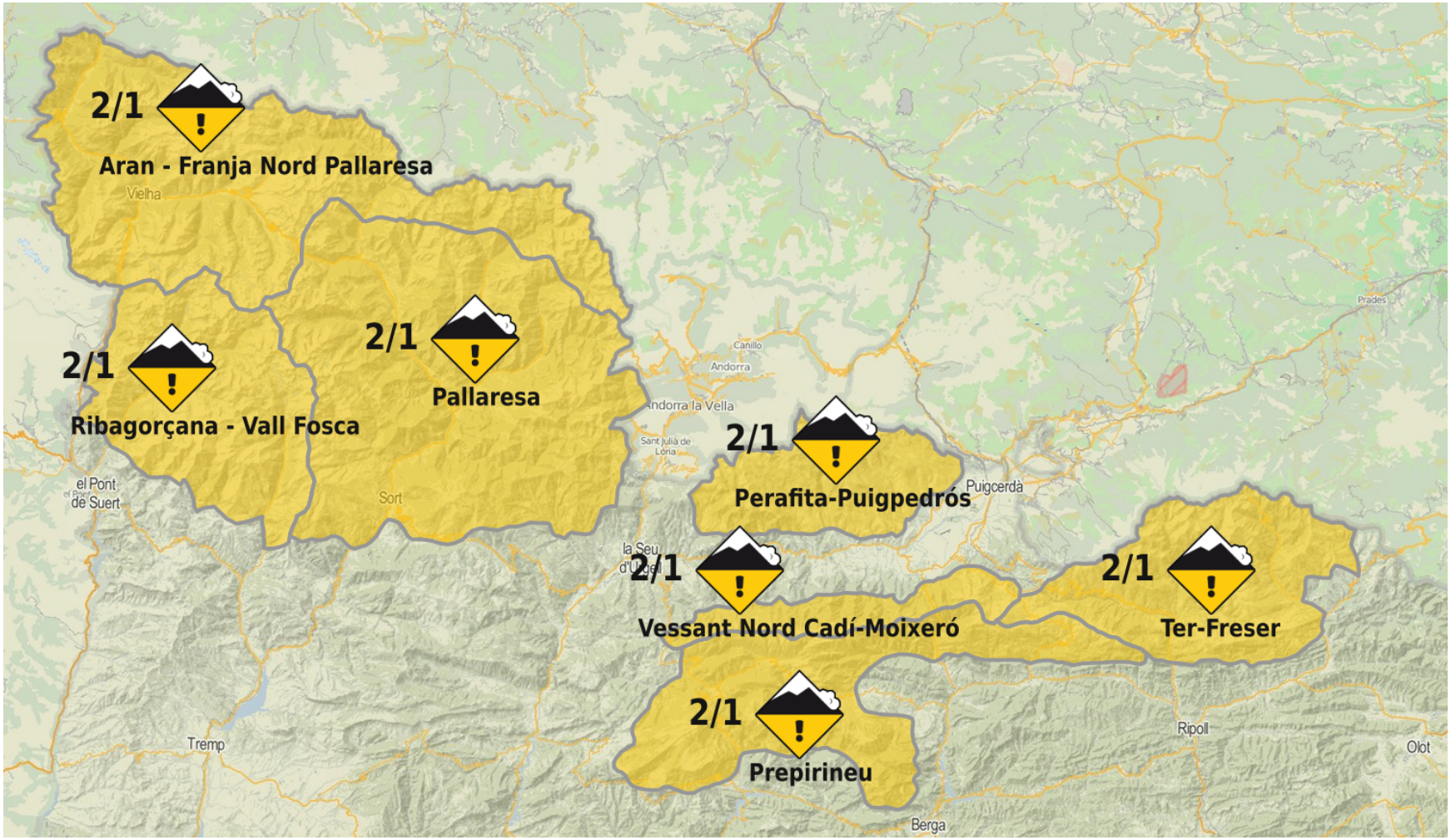

5 MUY FUERTE	4 FUERTE	3 NOTABLE	2 LIMITADO	1 DÉBIL

ICGC Institut Cartogràfic i Geològic de Catalunya

meteo.cat Servei Meteorològic de Catalunya

Boletín de peligro de aludes Aran - Franja Nord Pallaresa Del 23/02/2026 al 24/02/2026

(Válido fuera pistas de esquí y zonas no controladas)

LIMITADO (2) por encima del límite de bosque, DÉBIL (1) por debajo, hasta mediodía.

Situación primaria

Nieve húmeda

Distribución

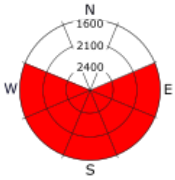

Tamaño

Origen

Tendencia

Situación secundaria

Nieve venteada

Distribución

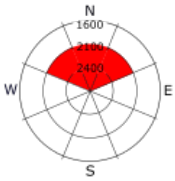

Tamaño

Origen

Tendencia

Estado del manto nivoso

La actividad de deslizamientos basales y aludes de nieve húmeda ha continuado. La elevada temperatura e insolación diurnas humedecen el manto, especialmente a partir de mediodía y en solanas. A primeras horas de la mañana podemos encontrar el manto encostrado en estas orientaciones.

Continuará la actividad de aludes de nieve húmeda, especialmente en orientaciones S, E y W, y del mediodía hasta la tarde. Se esperan caída de bolas, purgas y aludes de tamaño pequeño o medio, que pueden producirse hasta cota alta, en laderas soleadas de fuerte pendiente preferentemente. También puede continuar la actividad de deslizamientos basales en vertientes propicias.

En umbrías, por encima del límite de bosque y sobre todo en cotas más altas, todavía hay presencia de placas de viento que pueden ser reactivas por sobrecarga y producir aludes de tamaño pequeño o medio. Estas placas, con el paso de los días, van quedando más restringidas y resultan menos sensibles.

Distribución del manto nivoso

Los espesores a unos 2.200 m son superiores a los normales y rondan los 120-140 cm en el norte de Arán y los 160-200 cm en la Franja Nord Pallaresa y en el sur de Aran, puntualmente superiores.

Tendencia para las próximas 48-72h

El problema de placa de viento se irá minimizando y persistirá el de nieve húmeda. Peligro: en leve DESCENSO.

El próximo boletín será emitido el día 2026-02-24

5 MUY FUERTE	4 FUERTE	3 NOTABLE	2 LIMITADO	1 DÉBIL

EAWS EUROPEAN AVALANCHE WARNING SERVICES

ICGC Institut Cartogràfic i Geològic de Catalunya

Servei Meteorològic de Catalunya

Boletín de peligro de aludes Ribagorçana - Vall Fosca Del 23/02/2026 al 24/02/2026

(Válido fuera pistas de esquí y zonas no controladas)

LIMITADO (2) de mediodía hasta la tarde, DÉBIL (1) el resto

Situación primaria

Nieve húmeda

Distribución

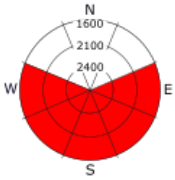

Tamaño

Origen

Tendencia

Situación secundaria

Nieve venteada

Distribución

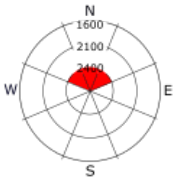

Tamaño

Origen

Tendencia

Estado del manto nivoso

Las altas temperaturas diurnas e intensa insolación humedecen el manto, especialmente a partir de mediodía y en solanas. Por la noche, el manto se encostra superficialmente por el enfriamiento y rehielo nocturno.

Con el paso de las horas, a partir de mediodía y hasta la tarde, es muy probable actividad de aludes de nieve húmeda, especialmente en orientaciones S, E y W. Se esperan caída de bolas, purgas y aludes pequeños, que pueden producirse hasta cota alta, en vertientes soleadas de fuerte pendiente preferentemente. No se descarta puntualmente algún deslizamiento basal sobre sustrato liso o herboso.

En umbrías, en cota alta, todavía se pueden encontrar placas de viento, poco reactivas en general, pero que todavía pueden ceder por sobrecargas y generar aludes de pequeño tamaño. Estas placas, con el paso de los días, van quedando más restringidas y resultan menos sensibles.

Distribución del manto nivoso

Hay nieve en el suelo a 1.500 m. El manto es esquiable por encima de unos 1.600 m. Los espesores alcanzan los 120-150 cm en cotas medias. Estos valores son muy superiores a los normales para la época.

Tendencia para las próximas 48-72h

El problema de placa de viento se irá minimizando y persistirá el de nieve húmeda. Peligro: en leve DESCENSO.

El próximo boletín será emitido el día 2026-02-24

5 MUY FUERTE	4 FUERTE	3 NOTABLE	2 LIMITADO	1 DÉBIL

EAWS EUROPEAN AVALANCHE WARNING SERVICES

ICGC Institut Cartogràfic i Geològic de Catalunya

Servei Meteorològic de Catalunya

Boletín de peligro de aludes Pallaresa
Del 23/02/2026 al 24/02/2026

(Válido fuera pistas de esquí y zonas no controladas)

LIMITADO (2) de mediodía hasta la tarde, DÉBIL (1) el resto

Situación primaria

Nieve húmeda

Distribución

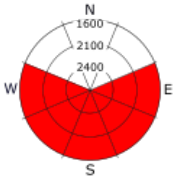

Tamaño

Origen

Tendencia

Situación secundaria

Nieve venteada

Distribución

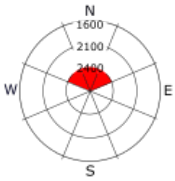

Tamaño

Origen

Tendencia

Estado del manto nivoso

Las altas temperaturas diurnas e intensa insolación humedecen el manto, especialmente a partir de mediodía y en solanas. Por la noche, el manto se encostra superficialmente por el enfriamiento y rehielo nocturno.

Con el paso de las horas, a partir de mediodía y hasta la tarde, es muy probable actividad de aludes de nieve húmeda, especialmente en orientaciones S, E y W. Se esperan caída de bolas, purgas y aludes pequeños, que pueden producirse hasta cota alta, en vertientes soleadas de fuerte pendiente preferentemente. No se descarta puntualmente algún deslizamiento basal sobre sustrato liso o herboso.

En umbrías, en cota alta, todavía se pueden encontrar placas de viento, poco reactivas en general, pero que todavía pueden ceder por sobrecargas y generar aludes de pequeño tamaño. Estas placas, con el paso de los días, van quedando más restringidas y resultan menos sensibles.

Distribución del manto nivoso

Hay nieve en el suelo a 1.500 m. El manto es esquiable por encima de unos 1.600 m. Los espesores alcanzan los 120-150 cm en cotas medias. Estos valores son muy superiores a los normales para la época.

Tendencia para las próximas 48-72h

El problema de placa de viento se irá minimizando y persistirá el de nieve húmeda. Peligro: en leve DESCENSO.

El próximo boletín será emitido el día 2026-02-24

5 MUY FUERTE	4 FUERTE	3 NOTABLE	2 LIMITADO	1 DÉBIL

EAWS EUROPEAN AVALANCHE WARNING SERVICES

ICGC Institut Cartogràfic i Geològic de Catalunya

Servei Meteorològic de Catalunya

Boletín de peligro de aludes Perafita-Puigpedrós Del 23/02/2026 al 24/02/2026

(Válido fuera pistas de esquí y zonas no controladas)

LIMITADO (2) de mediodía hasta la tarde, DÉBIL (1) el resto

Situación primaria

Nieve húmeda

Distribución

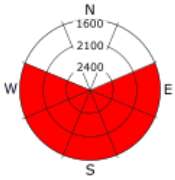

Tamaño

Origen

Tendencia

Situación secundaria

Nieve venteada

Distribución

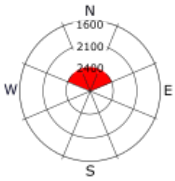

Tamaño

Origen

Tendencia

Estado del manto nivoso

El manto sigue mostrándose muy húmedo en las horas centrales del día y por la tarde en las vertientes solanas, por las altas temperaturas y la intensa radiación. Hasta primeras horas de la mañana, el rehielo nocturno mantiene el manto encostrado superficialmente.

Persiste la probabilidad de aludes de nieve húmeda, en orientaciones S, E y W, hasta cotas altas, más probables desde mediodía hasta la tarde, preferentemente en vertientes de fuerte pendiente y bajo resaltes rocosos. Serán purgas o aludes pequeños, sin descartar muy localmente alguno de tamaño medio.

En cota alta, sobre todo en umbrías, todavía puede existir la presencia de algunas pequeñas placas locales que por sobrecarga puedan ceder y generar aludes de pequeño tamaño. Estas placas, con el paso de los días, van quedando más restringidas y resultan menos sensibles.

Distribución del manto nivoso

Hay nieve en el suelo por encima de unos 1.400-1500 m. Sin embargo, el manto es esquiable por encima de unos 1.600 m en N. Los espesores, aunque irregulares, rondan los 80-120 cm en cotas medias. Son grosores muy por encima de los habituales para la época.

Tendencia para las próximas 48-72h

El problema de placa de viento se irá minimizando y persistirá el de nieve húmeda. Peligro: en leve DESCENSO.

El próximo boletín será emitido el día 2026-02-24

5 MUY FUERTE	4 FUERTE	3 NOTABLE	2 LIMITADO	1 DÉBIL

EAWS EUROPEAN AVALANCHE WARNING SERVICES

ICGC Institut Cartogràfic i Geològic de Catalunya

Servei Meteorològic de Catalunya meteo.cat

Boletín de peligro de aludes Vessant Nord Cadí-Moixeró Del 23/02/2026 al 24/02/2026

(Válido fuera pistas de esquí y zonas no controladas)

LIMITADO (2) de mediodía hasta la tarde, DÉBIL (1) el resto

Situación primaria

Nieve húmeda

Distribución

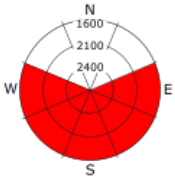

Tamaño

Origen

Tendencia

Situación secundaria

Nieve venteada

Distribución

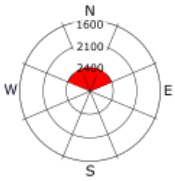

Tamaño

Origen

Tendencia

Estado del manto nivoso

El manto ha entrado en un ciclo fusión-rehielo diurno-nocturno en las vertientes más solanas por la alta radiación y temperaturas elevadas durante el día y el enfriamiento de noche. Con esta dinámica, el manto se encuentra muy húmedo desde mediodía hasta la tarde, sobre todo en solanas.

Con estas condiciones, continúa la probabilidad de aludes de nieve húmeda, en orientaciones S, E y W, hasta cotas altas, en las horas de máximo humedecimiento, preferentemente en laderas de fuerte pendiente y bajo resaltes rocosos. Serán purgas o caída de bolas, y aludes pequeños, sin descartar, muy localmente, alguno de tamaño medio.

En las umbrías de cota alta todavía podemos encontrar pequeñas placas locales que por sobrecarga puedan ceder y generar aludes de pequeño tamaño. Estas placas, con el paso de los días, van quedando más restringidas y resultan menos sensibles.

Distribución del manto nivoso

Hay manto continuo por encima de unos 1.700 m y esquiable por encima de unos 1.800 m. Los espesores están alrededor de 150-170 cm en cotas medias. Estos valores son muy excedentarios para la época del año.

Tendencia para las próximas 48-72h

El problema de placa de viento se irá minimizando y persistirá el de nieve húmeda. Peligro: en leve DESCENSO.

El próximo boletín será emitido el día 2026-02-24

5 MUY FUERTE	4 FUERTE	3 NOTABLE	2 LIMITADO	1 DÉBIL

EAWS EUROPEAN AVALANCHE WARNING SERVICES

ICGC Institut Cartogràfic i Geològic de Catalunya

Servei Meteorològic de Catalunya

Boletín de peligro de aludes Prepirineu
Del 23/02/2026 al 24/02/2026

(Válido fuera pistas de esquí y zonas no controladas)

LIMITADO (2) de mediodía hasta la tarde, DÉBIL (1) el resto

Situación primaria

Nieve húmeda

Distribución

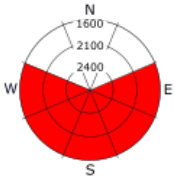

Tamaño

Origen

Tendencia

Situación secundaria

Nieve venteada

Distribución

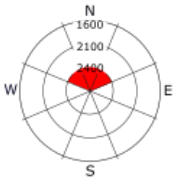

Tamaño

Origen

Tendencia

Estado del manto nivoso

El manto sigue mostrándose muy húmedo en las horas centrales del día y por la tarde, en las vertientes más soleadas, por las altas temperaturas y la intensa radiación. Hasta primeras horas de la mañana, el rehielo nocturno mantiene el manto encostrado superficialmente.

Persiste la probabilidad de aludes de nieve húmeda, en orientaciones S, E y W, hasta cotas altas, más probables desde mediodía hasta la tarde, preferentemente en vertientes de fuerte pendiente y bajo resaltes rocosos. Serán purgas o aludes pequeños, sin descartar muy localmente alguno de tamaño medio.

En cota alta, sobre todo en umbrías, todavía puede existir la presencia de algunas pequeñas placas locales que por sobrecarga puedan ceder y generar aludes de pequeño tamaño. Estas placas, con el paso de los días, van quedando más restringidas y resultan menos sensibles.

Distribución del manto nivoso

Hay nieve desde 1.500 a 1600 m. El manto es esquiable a partir de unos 1700 m. Los grosores están alrededor de 100-120 cm a unos 2.200 m y son superiores a los habituales.

Tendencia para las próximas 48-72h

El problema de placa de viento se irá minimizando y persistirá el de nieve húmeda. Peligro: en leve DESCENSO.

El próximo boletín será emitido el día 2026-02-24

5 MUY FUERTE	4 FUERTE	3 NOTABLE	2 LIMITADO	1 DÉBIL

EAWS EUROPEAN AVALANCHE WARNING SERVICES

ICGC Institut Cartogràfic i Geològic de Catalunya

Servei Meteorològic de Catalunya

Boletín de peligro de aludes Ter-Freser
Del 23/02/2026 al 24/02/2026

(Válido fuera pistas de esquí y zonas no controladas)

LIMITADO (2) de mediodía hasta la tarde, DÉBIL (1) el resto

Situación primaria

Nieve húmeda

Distribución

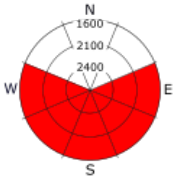

Tamaño

Origen

Tendencia

Situación secundaria

Nieve venteada

Distribución

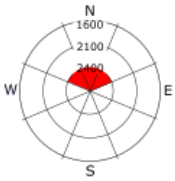

Tamaño

Origen

Tendencia

Estado del manto nivoso

En las últimas jornadas se ha observado actividad de aludes naturales de nieve húmeda y deslizamientos basales. Con la continuidad de las altas temperaturas y fuerte insolación el manto sigue humedeciendose durante las horas diurnas.

Persiste la probabilidad de aludes de nieve húmeda, en orientaciones S, E y W, hasta cotas altas, más probables desde mediodía hasta la tarde, preferentemente en vertientes de fuerte pendiente y bajo resaltes rocosos. Serán purgas o aludes pequeños, o hasta tamaño medio muy puntualmente, e incluso, es posible algún deslizamiento basal en vertientes propicias.

En cota alta, sobre todo en umbrías, todavía puede existir la presencia de algunas pequeñas placas locales que por sobrecarga puedan ceder y generar aludes de pequeño tamaño. Estas placas, con el paso de los días, van quedando más restringidas y resultan menos sensibles.

Distribución del manto nivoso

El manto nivoso presenta grosores muy excedentarios para la época del año. En lugares no afectados por el viento, los espesores oscilan entre 90-130 cm a unos 2.000 m, siendo esquiable a partir de unos 1.600 m.

Tendencia para las próximas 48-72h

El problema de placa de viento se irá minimizando y persistirá el de nieve húmeda. Peligro: en leve DESCENSO.

El próximo boletín será emitido el día 2026-02-24

5 MUY FUERTE	4 FUERTE	3 NOTABLE	2 LIMITADO	1 DÉBIL

EAWS EUROPEAN AVALANCHE WARNING SERVICES