BUTLLETÍ DEL PERILL D'ALLAUS DEL PRINCIPAT D'ANDORRA

Servei meteorològic nacional
Principat d'Andorra

Elaborat el 23/02/2026 16:00
Propera actualització 24/02/2026 a les 16h

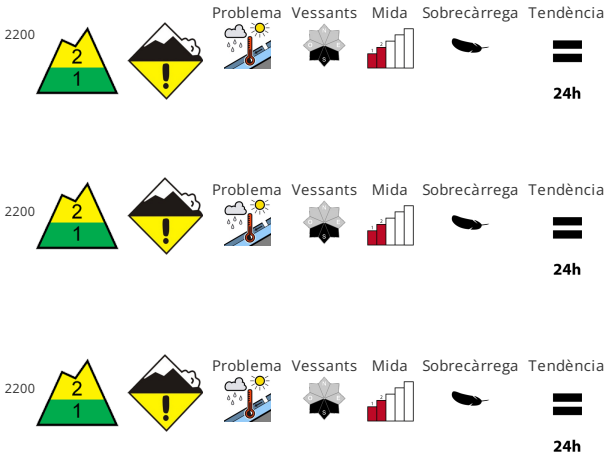

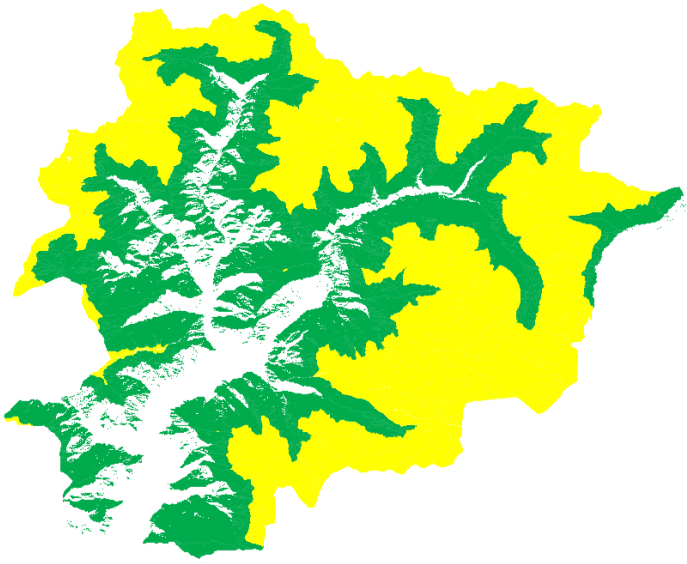

ESTABILITAT DEL MANTELL NIVAL

Després d'una nit serena, al matí les condicions d'allaus són favorables en molts sectors. Amb l'augment de la temperatura diürna i la radiació solar, són probables allaus de placa humida de mida mitjana. A partir del migdia la probabilitat de desencadenament d'allaus humides augmentarà clarament sobretot als vessants assolellats inclinats. Això es dona especialment a la base de parets rocoses, i també en terreny dret i escarpat. A més, són possibles allaus de lliscament basal en qualsevol moment. A causa de la crosta dura hi ha el perill de relliscar i caure als vessants inclinats.

QUALITAT DE LA NEU

Les condicions són primaverals. El refredament nocturn serà bo. La superfície del mantell de neu es regelarà per formar una crosta portant i s'estovarà al llarg del dia. Els gruixos de neu varien molt per sobre dels 2500 m aproximadament per la influència del vent. Evitar les zones amb esquerdes de lliscament basal.

GRUIXOS DEL MANTELL NIVAL FORA DE PISTA

Zona nord		Gruix neu		
Mantell Nival		1500m	2000m	2500m
N	1300 m	30 cm	150 cm	200 cm
S	1800 m	0 cm	100 cm	150 cm

Zona centre		Gruix neu		
Mantell Nival		1500m	2000m	2500m
N	1300 m	20 cm	150 cm	200 cm
S	1800 m	0 cm	100 cm	150 cm

Zona sud		Gruix neu		
Mantell Nival		1500m	2000m	2500m
N	1300 m	20 cm	120 cm	150 cm
S	1800 m	0 cm	60 cm	100 cm

Govern d'Andorra

EAWS
EUROPEAN AVALANCHE WARNING SERVICES

Aquest butlletí ha estat elaborat seguint les normes i recomanacions de l'**European Avalanche Warning Services**, del qual el **Servei meteorològic Nacional** n'és membre

BUTLLETÍ DEL PERILL D'ALLAUS DEL PRINCIPAT D'ANDORRA

Servei meteorològic nacional
Principat d'Andorra

Informació detallada per espais naturals protegits

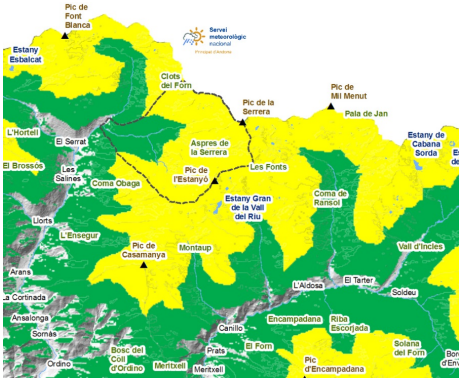

SORTENY

Trobem neu a tots els camins des de Llorts i l´accés amb esquís fins al Refugi es pot fer com feia anys que no es veia durant tantes setmanes seguides. Haurem de seguir les recomanacions de l´estabilitat del mantell nival per evitar posar-nos en perill als vessants sud més inclinats.

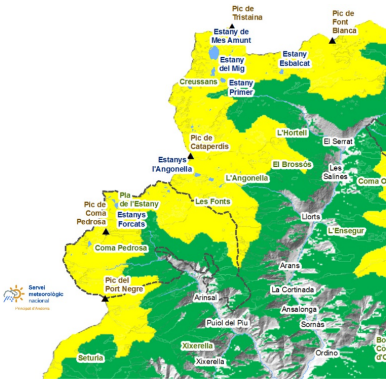

COMAPEDROSA

A cotes baixes la neu s´ha compactat i ha reduït el seu gruix a causa de l´humidificació. Haurem de vigilar a no relliscar a causa de la crosta de regel. La distribució de la neu és molt irregular a causa del vent. Als vessants orientats a est, com pot ser l´accés des d´Arinsal pel Port Negre (Sanfons) haurem d´extremar les precaucions per no desencadenar plaques humides que encara poden baixar formades amb el vent dels darrers episodis.

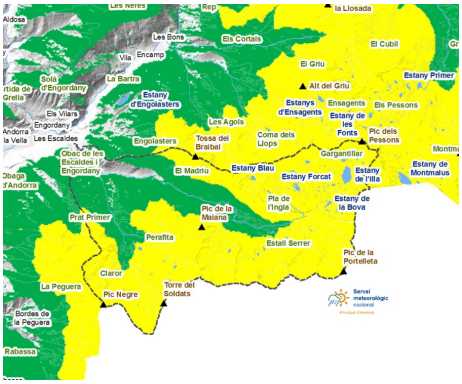

MADRIU-PERAFITA-CLAROR

Als vessants est s´hi ha de circular amb molta cautela, ja que és on hi ha les acumulacions de neu ventada més importants i encara poden baixar en forma de placa humida. A cotes altes els vent va deixar la neu dura al descobert i amb condicions difícils de baixar en algunes ocasions. Als vessants sud i a cotes baixes les condicions són primaverals, neu dura al matí i tova al migdia.

Govern d'Andorra

EAWS
EUROPEAN AVALANCHE WARNING SERVICES

Aquest butlletí ha estat elaborat seguint les normes i recomanacions de l'**European Avalanche Warning Services**, del qual el **Servei meteorològic Nacional** n'és membre

BUTLLETÍ DEL PERILL D'ALLAUS DEL PRINCIPAT D'ANDORRA

Servei meteorològic nacional
Principat d'Andorra

Gruixos de neu nova dels darrers dies (de les últimes 24h mesurat a les 06:00h UTC)

	19/02/2026	20/02/2026	21/02/2026	22/02/2026
FEDA (Central)	0 cm	0 cm	0 cm	0 cm
Engolasters - FEDA	0 cm	0 cm	0 cm	0 cm
Bony de les Neres	4 cm	0 cm	0 cm	0 cm
Sorteny	16 cm	0 cm	0 cm	0 cm
Perafita	9 cm	0 cm	0 cm	0 cm
Tossa Espiolets	0 cm	53 cm	0 cm	0 cm
Grau Roig - FEDA	1 cm	0 cm	0 cm	0 cm
Fontverd	2 cm	0 cm	0 cm	0 cm
Ransol - FEDA	0 cm	0 cm	0 cm	0 cm
Setúria	4 cm	0 cm	0 cm	0 cm
Caborreu	0 cm	0 cm	0 cm	0 cm
La Solana	0 cm	0 cm	0 cm	0 cm
Envalira Antenes	1 cm	0 cm	0 cm	0 cm
Vall del Riu FEDA	19 cm	0 cm	0 cm	0 cm