MINISTERO DELLA DIFESA

meteomont
Servizio Nazionale di previsione neve e valanghe

EAWS EUROPEAN AVALANCHE WARNING SERVICES

CARABINIERI

# ALPI MARITTIME

Bollettino Valanghe N. 354/2026 del 23/02/2026 ore 14.00
Validità 48 ore prossima emissione 24/02/2026

**A cura del Servizio METEOMONT dell'ARMA dei CARABINIERI**
**In collaborazione con Servizio Meteorologico dell'Aeronautica militare**

## SITUAZIONE alle 14:00 del 23/02/2026

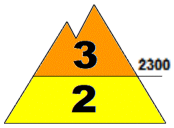


**SITUAZIONE TIPO: neve a debole coesione e vento.**

**SITUAZIONE TIPO: situazione primaverile.**

| Quota neve (mslm) | Nord | Sud |
|---|---|---|
| | 800 - 1000 | 1000 - 1200 |

| Altezza Neve (cm) | Neve al suolo | Neve Fresca | Quota (mslm) |
|---|---|---|---|
| | 138 | 0 | 2305 |
| | 114 | 0 | 1755 |

**VALANGHE OSSERVATE: -.**

## PREVISIONI 24/02/2026

# GRADO DI PERICOLO: MARCATO 3

## SITUAZIONE TIPO: neve a debole coesione e vento.

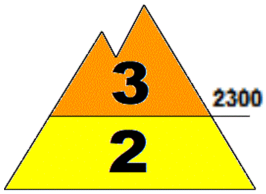


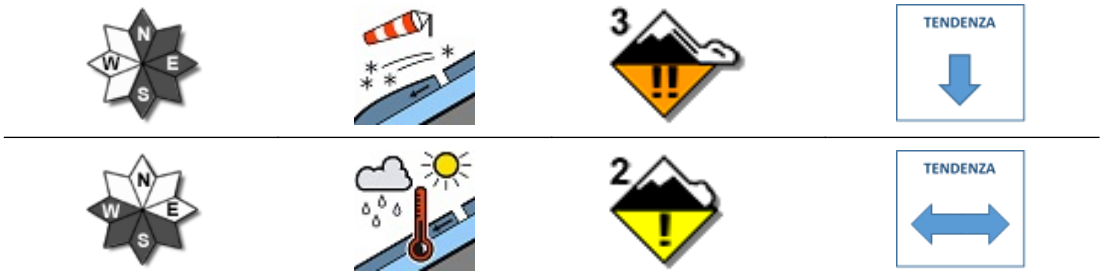


## SITUAZIONE TIPO: situazione primaverile.

**MANTO NEVOSO: La stabilità del manto nevoso è molto scarsa su molti punti (aree) per versanti da nord a sud compresi al di sopra di 2300 mslm, possibili valanghe di dimensioni medie.**
**La stabilità del manto nevoso è scarsa su alcuni punti (aree) per versanti al sole al di sotto di 2300 mslm, possibili valanghe di dimensioni medie.**

## AVVERTENZE

A seguito dell'attività eolica registrata sono da evitare le zone di accumulo, conche, canaloni, cambi di pendenza e pendii sotto vento in genere.

## SCALA EUROPEA DEL GRADO DI PERICOLO VALANGHE

## LEGENDA PROBLEMA

**Bollettino realizzato su scala sinottica-regionale (standard EAWS). La sua valutazione non può escludere in alcun modo la necessità di una seria e capace valutazione locale del pericolo (singolo pendio) che può essere anche sensibilmente diverso. Le previsioni meteorologiche sono relative all'orario UTC (per l'Italia +1 in inverno e +2 in estate).**

MINISTERO DELLA DIFESA

meteomont
Servizio Nazionale di previsione neve e valanghe

EAWS EUROPEAN AVALANCHE WARNING SERVICES

CARABINIERI

AERONAUTICA MILITARE SERVIZIO METEOROLOGICO

# ALPI MARITTIME

## PREVISIONE METEO

| Quota | | 24/02/2026 h6:00 | 24/02/2026 h12:00 | 24/02/2026 h18:00 |
|---|---|---|---|---|
| 1000 | Venti | 01 Nodi da Ovest | 01 Nodi da Ovest | 00 Calma |
| | Temperature | +12 °C | +13 °C | +12 °C |
| | Temp.percepita | 12 °C | 13 °C | 12 °C |
| 2000 | Venti | 03 nodi da N-Ovest | 01 Nodi da Nord | 02 Nodi da Sud |
| | Temperature | +08 °C | +09 °C | +09 °C |
| | Temp.percepita | 7 °C | 9 °C | 9 °C |
| 3000 | Venti | 07 Nodi da Nord | 04 Nodi da Nord | 01 Nodi da Ovest |
| | Temperature | +01 °C | +02 °C | +02 °C |
| | Temp.percepita | -3 °C | -0 °C | 2 °C |
| Zero termico | | 3100-3300 m. | 3100-3300 m. | 3200-3400 m. |
| Fenomeno | | — | — | — |
| Stato del cielo | | | | |

## LEGENDA FENOMENI

— Assenza Fenomeni · Nebbia · Foschia · Pioggia debole · Pioggia moderata · Pioggia forte · Temporali

Nevicata debole · Nevicata moderata · Nevicata forte

## STATO DEL CIELO

Sereno · Poco nuvoloso · Nuvoloso · Molto nuvoloso · Coperto

**(*) Dati meteonivometrici non presenti.**

**L'INFORMAZIONE E' PREVENZIONE - LEGGI L'ATTUALE GRADO DI PERICOLO VALANGHE!**

**IL CAPO DEL CENTRO NAZIONALE METEOMONT**
**(Ten. Col. RFI Emanuela Gini)**
**FIRMA AUTOGRAFA OMESSA AI SENSI**
**DELL'ART.3 DEL D.LGS N.39/1993**

Bollettino realizzato su scala sinottica-regionale (standard EAWS). La sua valutazione non può escludere in alcun modo la necessità di una seria e capace valutazione locale del pericolo (singolo pendio) che può essere anche sensibilmente diverso. Le previsioni meteorologiche sono relative all'orario UTC (per l'Italia +1 in inverno e +2 in estate).