RÉPUBLIQUE FRANÇAISE
Liberté Égalité Fraternité

METEO FRANCE
À VOS CÔTÉS, DANS UN CLIMAT QUI CHANGE

Bulletin d'estimation du risque d'avalanche
(valable en dehors des pistes balisées et ouvertes)

MASSIF : Oisans

Rédigé le lundi 23 février 2026 à 15h

Estimation des risques pour le : MARDI 24 FÉVRIER

DÉSTABILISATION DE LA NEIGE HUMIDE EN MOYENNE MONTAGNE ET STABILISATION DE LA NEIGE SÈCHE EN ALTITUDE.

3

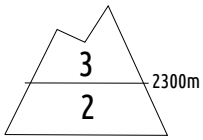

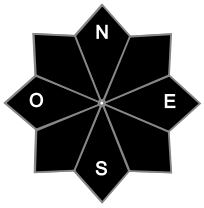

Au-dessus de 2300m indice de risque marqué, plus bas indice limité.

Départs spontanés : Avalanches de glissement sur les pentes herbeuses raides de moyenne montagne.

Déclenchements provoqués : Plaques dures en altitude.

Indices de risque : 5 très fort - 4 fort - 3 marqué - 2 limité - 1 faible -- En noir : les pentes les plus dangereuses

Stabilité du manteau neigeux

Situation avalancheuse typique : avalanches de fond couche fragile persistante

Le soleil et le fort redoux ont humidifié et considérablement densifié le manteau neigeux dans la quasi totalité des pentes de moyenne montagne et dans les versants ensoleillés jusqu'à plus de 2400 m. Par contre, dans les versants ombragés de haute montagne, les conditions restent plus hivernales.
Déclenchements provoqués : le vent de nord a déplacé de grandes quantités de neige meuble et formé de grosses accumulations en altitude. Elles sont devenues plus difficiles à déclencher, mais si une plaque dure vient à céder, notamment en cas de couches fragiles insuffisamment enfouies,, les volumes de neige peuvent être importants avec des cassures de plus d'un mètre.
Départs spontanés : ils concernent surtout les reptations observées depuis plusieurs jours, cédant de manière aléatoire en emportant toute la neige jusqu'au sol. Les versants au soleil en dessous de 2000/2200 m sont les plus propices pour ces avalanches dont l'ampleur ne devrait pas excéder.la taille 2. L'humidification du manteau neigeux gagne en profondeur et le risque d'avalanches de neige humide augmente également au fil des jours.

Qualité de la neige

Qualification de l'enneigement : l'enneigement est bon pour la saison dès 1200 m, puis abondant au dessus de 1500 m environ, notamment dans les combes d'altitude. On trouve des crêtes dégarnies par le vent ou au contraire fortement cornichées.

Limites skiables : vers 1100/1300 m.

Qualité de la neige lundi : Neige lourde au moins jusqu'à 2000/2400 m selon l'orientation, croûtée en début de journée et s'humidifiant dans les versants ensoleillés. Dans les ubacs d'altitude, la neige est souvent soufflée. Dans les combes abritées du vent, on trouve de grosses quantités de neige récente.

Aperçu météo pour le mardi 24 février

	nuit	matin	après-midi	soir
Pluie-Neige				
Iso 0 °C	3 000 m	3 300 m	3 300 m	3 300 m
Vent 2500 m	↓ 25 km/h	↙ 15 km/h	↗ 10 km/h	← 5 km/h
Vent 3500 m	↓ 40 km/h	↓ 20 km/h	→ 15 km/h	↑ 10 km/h

Épaisseur de neige hors-piste

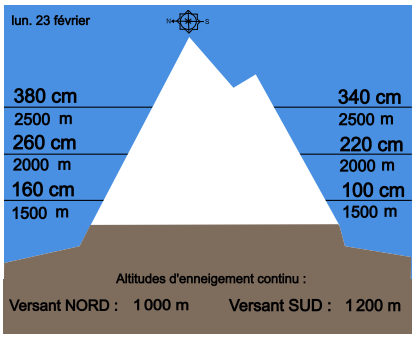

Précipitations à 1800 m

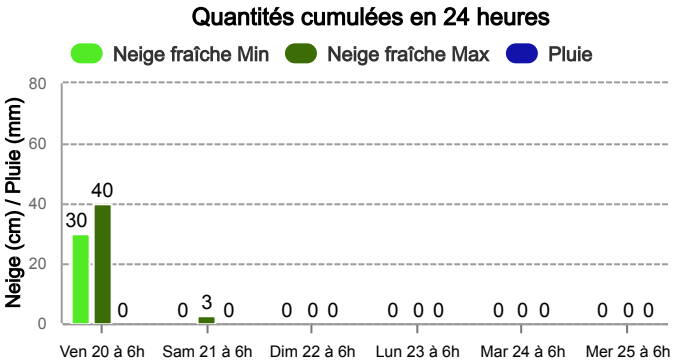

Tendance du mercredi 25 février

Indice de risque limité

Mercredi, temps ensoleillé et très doux, accélérant l'humidification du manteau neigeux en profondeur. Le risque prépondérant restera celui des avalanches de glissement dans les adrets de moyenne montagne et le risque de plaque en haute montagne..

Pour consulter la vigilance en cours, veuillez vous rendre sur le site https://vigilance.meteofrance.fr/fr

Météo-France - 73 avenue de Paris, 94165 Saint-Mandé cedex - Contact : contact@meteo.fr

Rédigé par Météo-France avec la contribution des observateurs du réseau nivo-météorologiques. Partenariat : ANMSM (Maires de Stations de Montagne), DSF (Domaines Skiables de France), ADSP (Directeurs de Pistes et de la Sécurité des Stations de Sports d'Hiver) et autres acteurs de la montagne.

Bulletin neige & avalanches par téléphone au
0 892 68 10 20 Service 0,35 € / min + prix appel

RÉPUBLIQUE FRANÇAISE
Liberté Égalité Fraternité

METEO FRANCE
À VOS CÔTÉS, DANS UN CLIMAT QUI CHANGE

Bulletin d'estimation du risque d'avalanche

(valable en dehors des pistes balisées et ouvertes)

MASSIF : Oisans

Rédigé le lundi 23 février 2026 à 15h

Conditions nivo-météo des 7 derniers jours

	mar. 17/02				mer. 18/02				jeu. 19/02				ven. 20/02				sam. 21/02				dim. 22/02				lun. 23/02			
	03h	09h	15h	21h	03h	09h	15h	21h	03h	09h	15h	21h	03h	09h	15h	21h	03h	09h	15h	21h	03h	09h	15h	21h	03h	09h	15h	21h
Météo																												
Vent (km/h)	120	100	85	50	45	35	30	90	50	40	60	75	85	80	80	80	70	65	65	50	40	35	35	30	35	35	35	25
à 3500m																												
Vent (km/h)	85	75	50	35	30	15	20	65	35	25	35	45	70	70	70	75	55	45	40	35	25	25	20	20	20	20	25	20
à 2500m																												

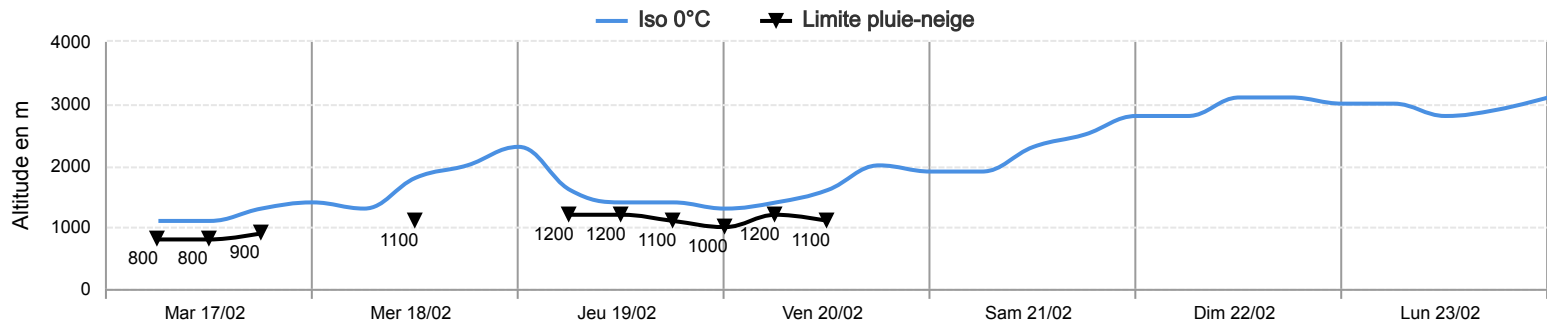

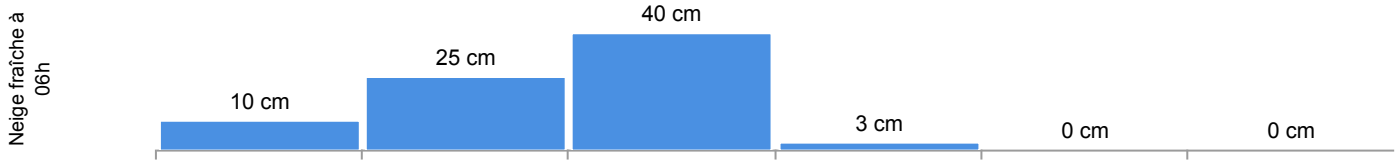

Risque d'avalanche	mar. 17/02	mer. 18/02	jeu. 19/02	ven. 20/02	sam. 21/02	dim. 22/02	lun. 23/02
	4	4	5	5	4	3	3

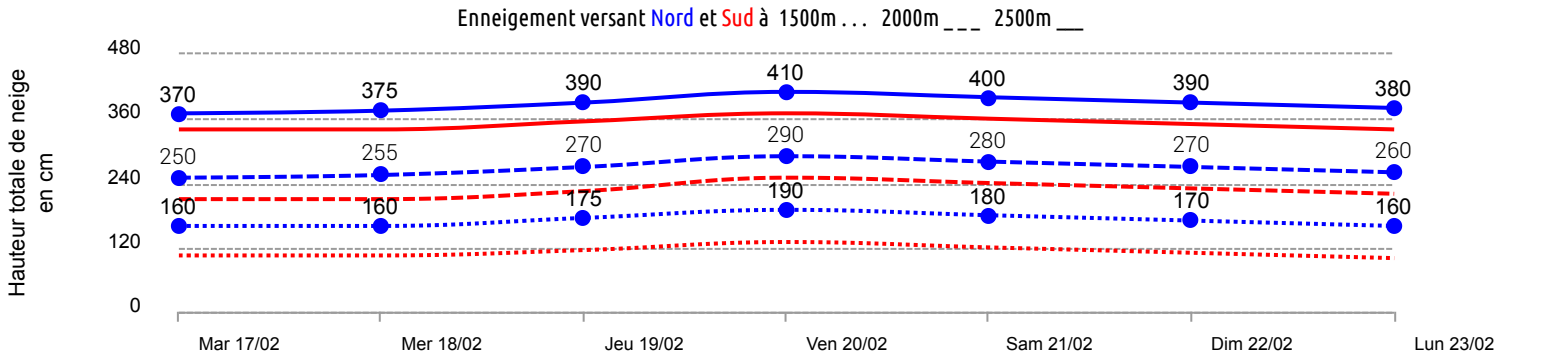

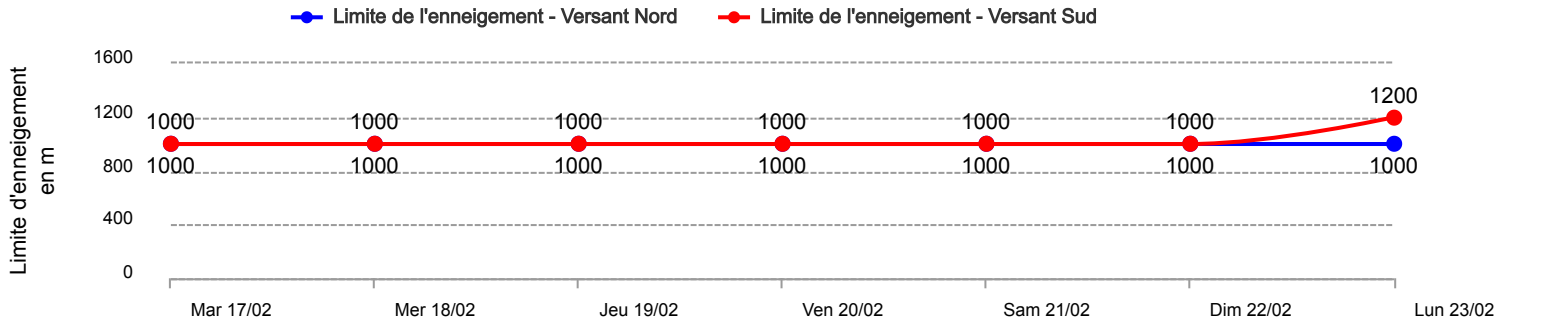

Pour consulter la vigilance en cours, veuillez vous rendre sur le site https://vigilance.meteofrance.fr/fr

Météo-France - 73 avenue de Paris, 94165 Saint-Mandé cedex - Contact : contact@meteo.fr

Rédigé par Météo-France avec la contribution des observateurs du réseau nivo-météorologiques. Partenariat : ANMSM (Maires de Stations de Montagne), DSF (Domaines Skiables de France), ADSP (Directeurs de Pistes et de la Sécurité des Stations de Sports d'Hiver) et autres acteurs de la montagne.

Bulletin neige & avalanches par téléphone au
0 892 68 10 20 Service 0,35 € / min + prix appel