Bulletin d'estimation du risque d'avalanche
(valable en dehors des pistes balisées et ouvertes)

MASSIF : Vercors

Rédigé le lundi 23 février 2026 à 15h

Estimation des risques pour le : MARDI 24 FÉVRIER

MANTEAU NEIGEUX BIEN CONSOLIDÉ DANS DE NOMBREUSES PENTES.

2

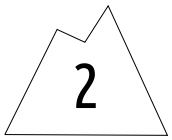

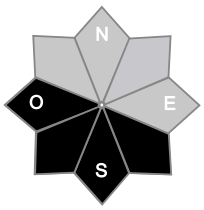

Indice de risque limité.

Départs spontanés : Avalanches de glissement sur les pentes herbeuses raides.

Déclenchements provoqués : En neige lourde.

Indices de risque : 5 très fort - 4 fort - 3 marqué - 2 limité - 1 faible -- En noir : les pentes les plus dangereuses

Stabilité du manteau neigeux

Situation avalancheuse typique : avalanches de fond neige humide

Le soleil et le fort redoux ont humidifié et considérablement densifié le manteau neigeux dans la quasi totalité des pentes.

Départs spontanés : ils concernent surtout les reptations observées ces derniers jours, cédant de manière aléatoire en emportant toute la neige jusqu'au sol. Les versants au soleil sont les plus propices pour ces avalanches dont l'ampleur ne devrait pas excéder.la taille 2. L'humidification du manteau neigeux gagne en profondeur et le risque d'avalanches de neige humide augmente également au fil des jours.

Déclenchements provoqués : le risque de déclenchement de plaque a très nettement diminué. Par contre, il faut se méfier des pentes raides constituées de neige lourde qui pourrait être mise en mouvement au passage d'un skieur en cas d'horaire inadapté.

Qualité de la neige

Qualification de l'enneigement : l'enneigement est bon pour la saison dès 1200 m, puis abondant au dessus de 1500 m environ, notamment dans les combes d'altitude. On trouve des crêtes dégarnies par le vent ou au contraire fortement cornichées.

Limites skiables : vers 1100/1300 m.

Qualité de la neige mardi : neige dense croûtée en début de journée, s'humidifiant dans les versants ensoleillés. Neige bien lourde dans les ubacs.

Aperçu météo pour le mardi 24 février

	nuit	matin	après-midi	soir
Pluie-Neige				
Iso 0 °C	3 100 m	3 200 m	3 300 m	3 300 m
Vent 1500 m	↓ 30 km/h	↙ 20 km/h	↓ 15 km/h	↑ 10 km/h
Vent 2000 m	↓ 35 km/h	↙ 25 km/h	↙ 20 km/h	↓ 10 km/h

Épaisseur de neige hors-piste

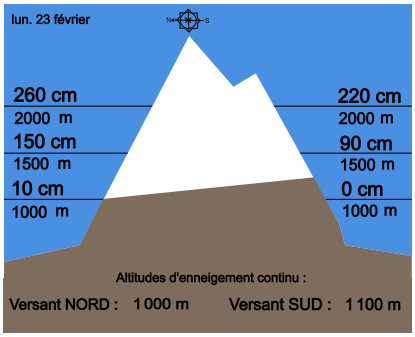

Précipitations à 1800 m

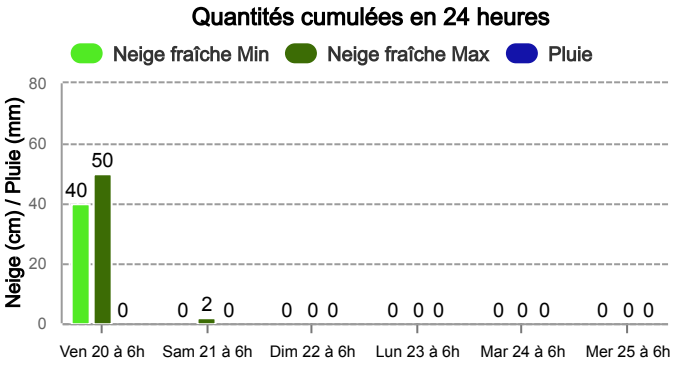

Tendance du mercredi 25 février

2

Indice de risque limité

Mercredi, temps ensoleillé et très doux, accélérant l'humidification du manteau neigeux en profondeur. Le risque prépondérant restera celui des avalanches de glissement.

Pour consulter la vigilance en cours, veuillez vous rendre sur le site https://vigilance.meteofrance.fr/fr

Météo-France - 73 avenue de Paris, 94165 Saint-Mandé cedex - Contact : contact@meteo.fr

Rédigé par Météo-France avec la contribution des observateurs du réseau nivo-météorologiques. Partenariat : ANMSM (Maires de Stations de Montagne), DSF (Domaines Skiables de France), ADSP (Directeurs de Pistes et de la Sécurité des Stations de Sports d'Hiver) et autres acteurs de la montagne.

Bulletin neige & avalanches par téléphone au
0 892 68 10 20 Service 0,35 € / min + prix appel

RÉPUBLIQUE FRANÇAISE
Liberté Égalité Fraternité

METEO FRANCE
À VOS CÔTÉS, DANS UN CLIMAT QUI CHANGE

Bulletin d'estimation du risque d'avalanche

(valable en dehors des pistes balisées et ouvertes)

MASSIF : Vercors

Rédigé le lundi 23 février 2026 à 15h

Conditions nivo-météo des 7 derniers jours

	mar. 17/02				mer. 18/02				jeu. 19/02				ven. 20/02				sam. 21/02				dim. 22/02				lun. 23/02			
	03h	09h	15h	21h	03h	09h	15h	21h	03h	09h	15h	21h	03h	09h	15h	21h	03h	09h	15h	21h	03h	09h	15h	21h	03h	09h	15h	21h
Météo																												
Vent (km/h)	75	65	45	15	45	20	40	90	60	30	50	70	70	60	60	70	60	50	45	40	35	30	30	30	25	30	25	25
à 2000m	↘	↘	↘	↘	↓	↗	↑	↑	↑	↘	↘	↘	↓	↓	↓	↓	↓	↓	↓	↓	↓	↙	↘	↙	↙	↓	↓	↙
Vent (km/h)	60	45	30	15	25	15	30	70	45	25	25	40	40	45	40	45	40	40	35	30	20	20	15	15	15	30	30	25
à 1500m	↘	↘	↘	↓	↓	↘	↑	↑	↗	→	→	↘	→	↓	↓	↓	↓	↓	↓	↙	↓	↖	→	↙	↓	↓	↓	↙

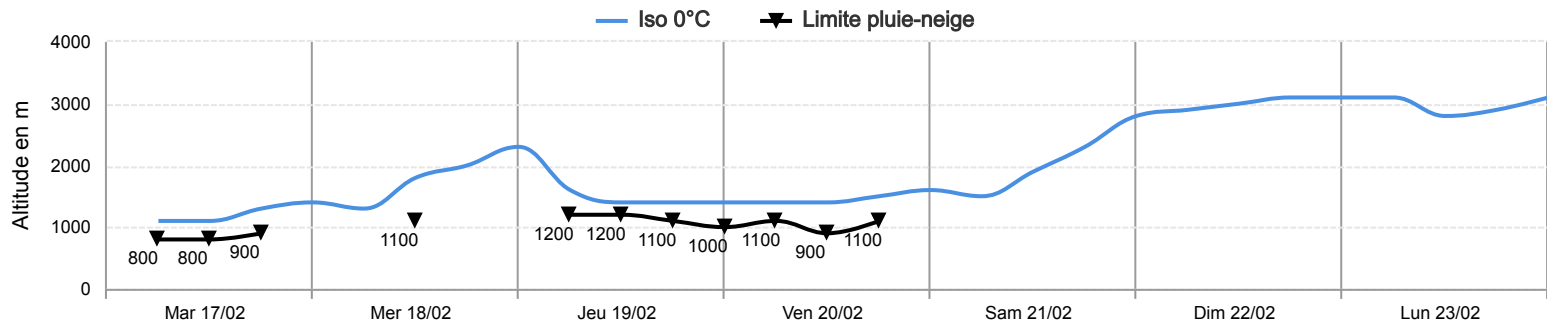

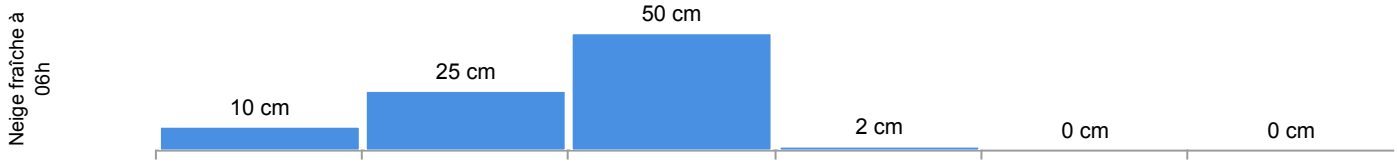

Risque d'avalanche	mar. 17/02	mer. 18/02	jeu. 19/02	ven. 20/02	sam. 21/02	dim. 22/02	lun. 23/02
	3	3	4	4	3	2	2

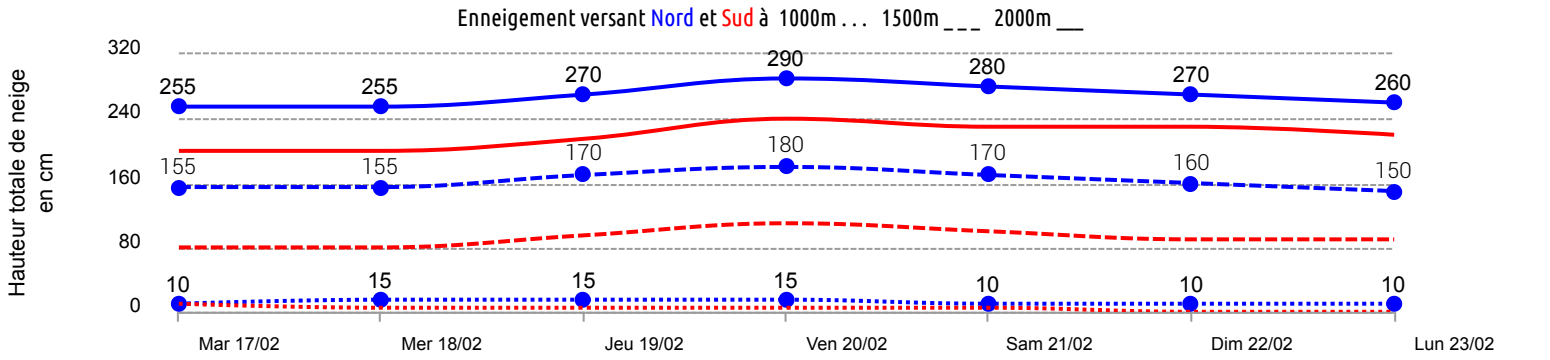

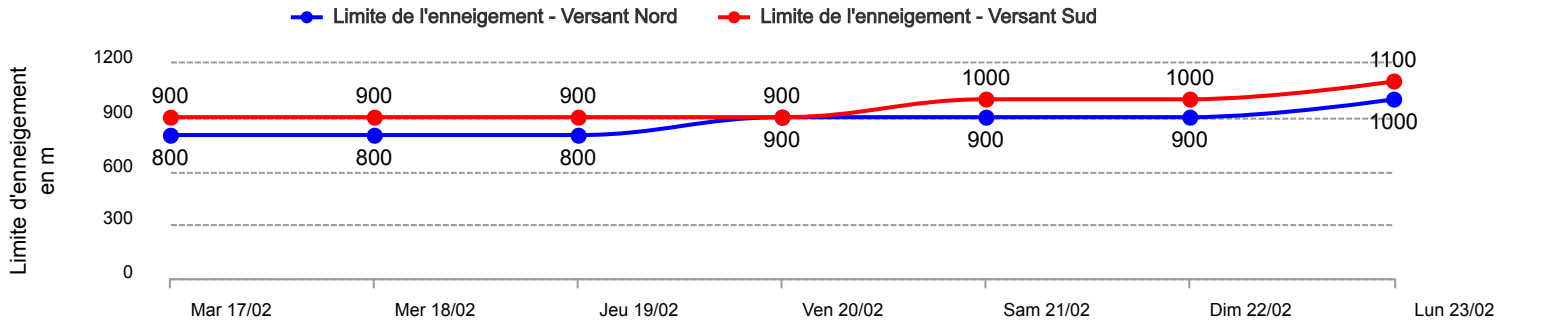

Pour consulter la vigilance en cours, veuillez vous rendre sur le site https://vigilance.meteofrance.fr/fr

Météo-France - 73 avenue de Paris, 94165 Saint-Mandé cedex - Contact : contact@meteo.fr

Rédigé par Météo-France avec la contribution des observateurs du réseau nivo-météorologiques. Partenariat : ANMSM (Maires de Stations de Montagne), DSF (Domaines Skiables de France), ADSP (Directeurs de Pistes et de la Sécurité des Stations de Sports d'Hiver) et autres acteurs de la montagne.

Bulletin neige & avalanches par téléphone au
0 892 68 10 20 Service 0,35 € / min + prix appel