Bulletin d'estimation du risque d'avalanche
(valable en dehors des pistes balisées et ouvertes)

MASSIF : Aure Louron

Rédigé le lundi 23 février 2026 à 16h

Estimation des risques pour le : MARDI 24 FÉVRIER

HUMIDIFICATION PRONONCÉE DANS UN LARGE SECTEUR SUD

2

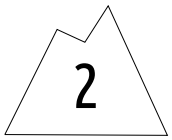

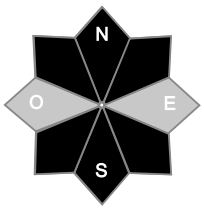

Indice de risque limité.

Départs spontanés : Avalanches de neige humide dans les pentes raides ensoleillées.

Déclenchements provoqués : Peu probable

Indices de risque : 5 très fort - 4 fort - 3 marqué - 2 limité - 1 faible -- En noir : les pentes les plus dangereuses

Stabilité du manteau neigeux

Situation avalancheuse typique : neige humide

Départs spontanés : En pentes raides, avalanches de fond jusqu'à l'herbe dans un large secteur sud.
Avalanche ponctuelle en neige humide de taille petite ou moyenne partant préférentiellement en seconde partie de journée dans les pentes raides sous les rochers.
Les faces sud-ouest jusque-là plutôt épargnées sont concernées elles-aussi à partir du début d'après-midi.
Compte tenu de l'excellent enneigement observé, possibilité d'une avalanche de grande taille descendant dans un vallon en dessous de 1800 m.
Taille plus fréquemment petite ou moyenne.

Déclenchements provoqués : Présence éventuelle de structures de plaques peu épaisses dans une combe nord/nord est plutôt dans la tranche 2200/2500 m.
Observable : neige encore non humidifiée, bruit d'effondrement de sous-couche, fissure se diffusant facilement, accumulation en pentes raides.
Avalanches de taille 1 (petite) , rarement 2 (moyenne).

Autres :
Excellent regel dans la majeure partie des versants, et neige dure et glacée propice aux glissades dans la plupart des versants aux premières heures de la journée, voire jusqu'en début d'après-midi en versants ouest.

Qualité de la neige

Enneigement : Excellent pour la saison au regard de ces dernières années.
Avec le beau temps, fonte très limitée à l'ombre au-delà de 1500 m, plus prononcée dans les versants d'un large secteur sud.
Le manteau neigeux s'amincit très doucement dans les pentes bien ensoleillées.

Limites skiables : à partir de 1300 à 1500 m au petit matin suivant les versants.
État de la neige : Crêtes, cols et sommets pelés en expositions ouest, en neige déjà bien humidifié en profondeur dans un très large secteur Sud à Est (dure le matin, meuble et humide en journée).
Neige sèche ou poudreuse dans les vallons d'un large secteur nord n'ayant pas trop pris le vent durant l'épisode perturbé de jeudi dernier.

Aperçu météo pour le mardi 24 février

	nuit	matin	après-midi	soir

Journée ensoleillée et très douce, 1 ou 2 degrés de plus que la veille.

Pluie-Neige				
Iso 0 °C	3 400 m	3 400 m	3 400 m	3 300 m
Vent 1500 m	↑ 10 km/h	↑ 10 km/h	↑ 10 km/h	↗ 10 km/h
Vent 3000 m	↗ 25 km/h	→ 25 km/h	↗ 20 km/h	↗ 20 km/h

Épaisseur de neige hors-piste

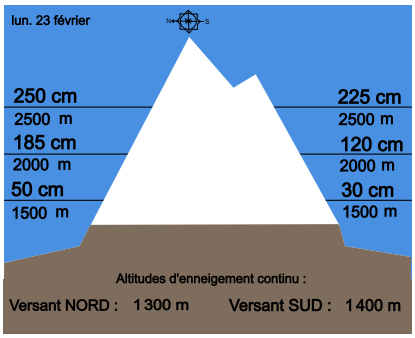

Précipitations à 1800 m

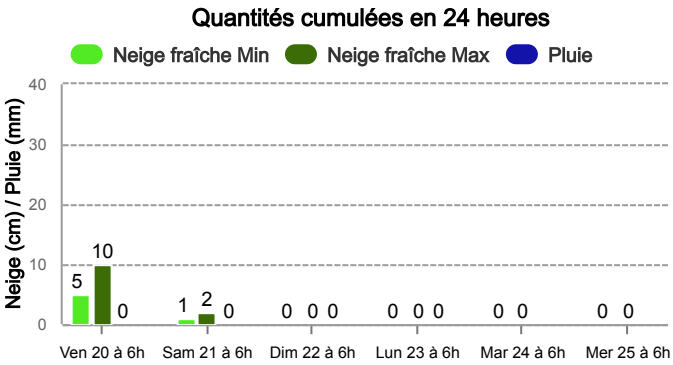

Tendance du mercredi 25 février

2

Indice de risque limité

Risque stationnaire, de même nature.

Pour consulter la vigilance en cours, veuillez vous rendre sur le site https://vigilance.meteofrance.fr/fr

Météo-France - 73 avenue de Paris, 94165 Saint-Mandé cedex - Contact : contact@meteo.fr

Rédigé par Météo-France avec la contribution des observateurs du réseau nivo-météorologiques. Partenariat : ANMSM (Maires de Stations de Montagne), DSF (Domaines Skiables de France), ADSP (Directeurs de Pistes et de la Sécurité des Stations de Sports d'Hiver) et autres acteurs de la montagne.

Bulletin neige & avalanches par téléphone au
0 892 68 10 20 Service 0,35 € / min + prix appel

RÉPUBLIQUE FRANÇAISE
Liberté Égalité Fraternité

METEO FRANCE
À VOS CÔTÉS, DANS UN CLIMAT QUI CHANGE

Bulletin d'estimation du risque d'avalanche

(valable en dehors des pistes balisées et ouvertes)

MASSIF : Aure Louron

Rédigé le lundi 23 février 2026 à 16h

Conditions nivo-météo des 7 derniers jours

	mar. 17/02				mer. 18/02				jeu. 19/02				ven. 20/02				sam. 21/02				dim. 22/02				lun. 23/02			
	03h	09h	15h	21h	03h	09h	15h	21h	03h	09h	15h	21h	03h	09h	15h	21h	03h	09h	15h	21h	03h	09h	15h	21h	03h	09h	15h	21h
Météo																												
Vent (km/h)	60	55	60	55	50	100	100	90	95	90	60	30	30	55	55	35	15	10	15	15	30	25	30	30	30	25	20	20
à 3000m																												
Vent (km/h)	35	15	10	25	15	70	70	30	50	55	30	20	15	15	15	5	5	2	5	5	5	5	10	10	10	10	5	10
à 1500m																												

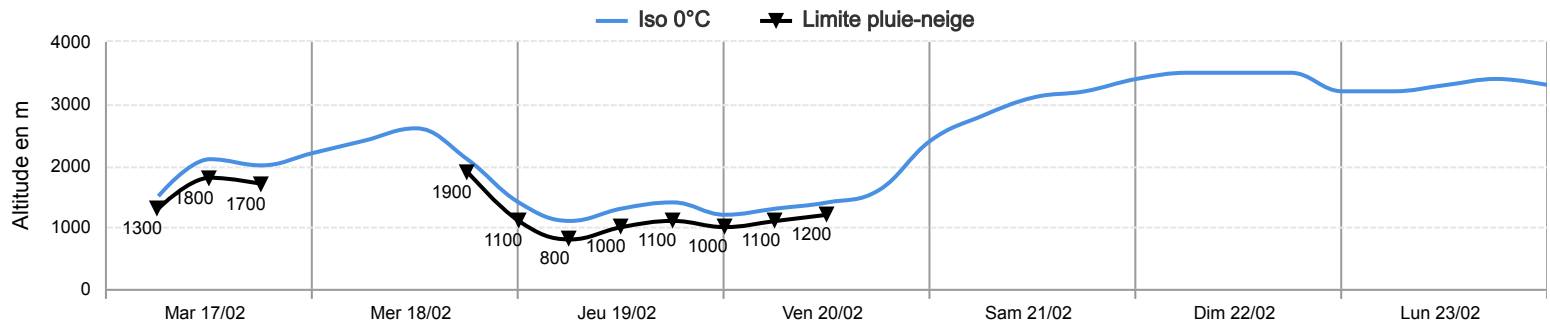

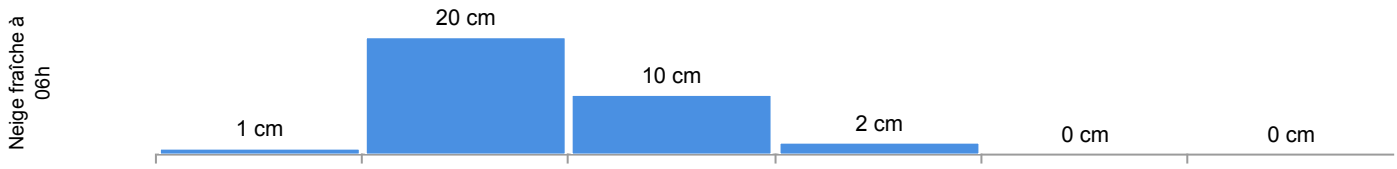

Risque d'avalanche	mar. 17/02	mer. 18/02	jeu. 19/02	ven. 20/02	sam. 21/02	dim. 22/02	lun. 23/02
	4	3	3	3	3	3	3

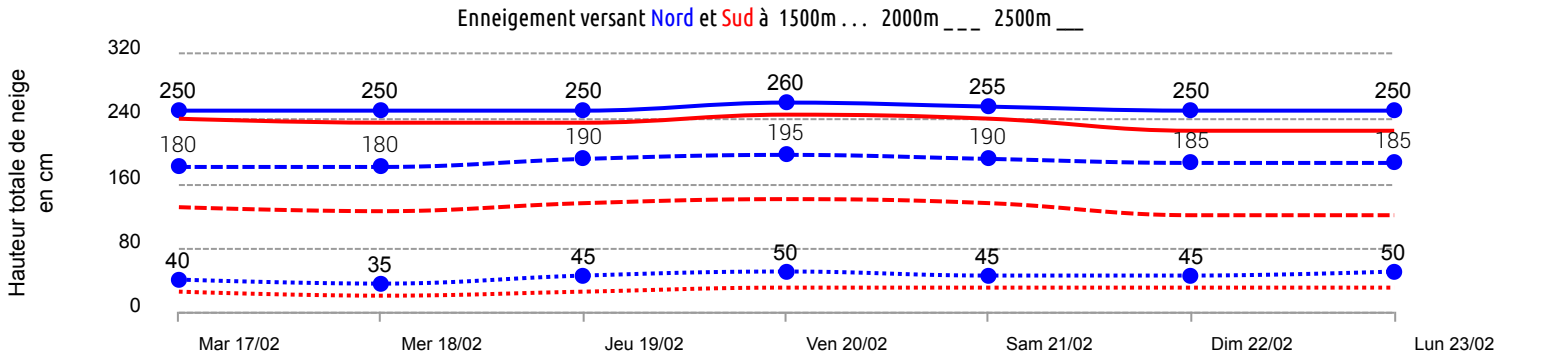

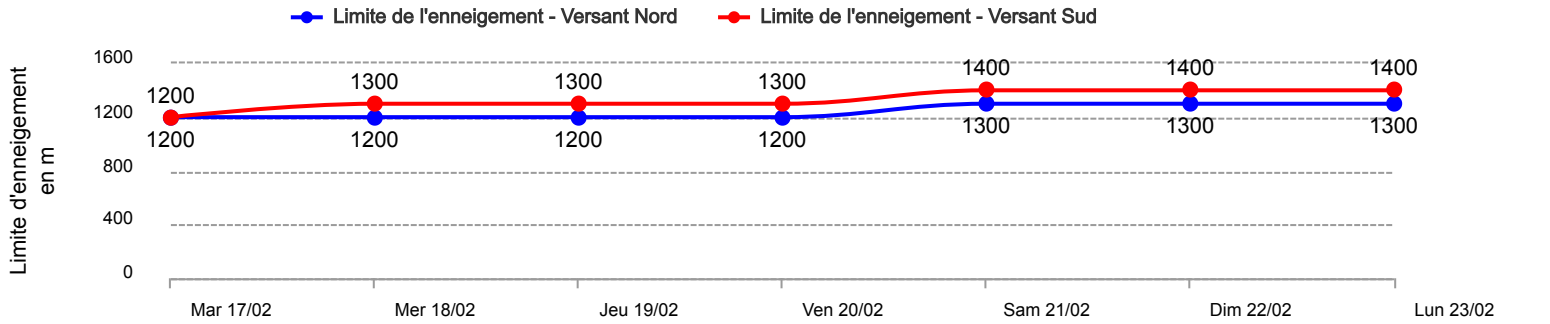

Pour consulter la vigilance en cours, veuillez vous rendre sur le site https://vigilance.meteofrance.fr/fr

Météo-France - 73 avenue de Paris, 94165 Saint-Mandé cedex - Contact : contact@meteo.fr

Rédigé par Météo-France avec la contribution des observateurs du réseau nivo-météorologiques. Partenariat : ANMSM (Maires de Stations de Montagne), DSF (Domaines Skiables de France), ADSP (Directeurs de Pistes et de la Sécurité des Stations de Sports d'Hiver) et autres acteurs de la montagne.

Bulletin neige & avalanches par téléphone au
0 892 68 10 20 Service 0,35 € / min + prix appel