RÉPUBLIQUE FRANÇAISE
Liberté Égalité Fraternité

METEO FRANCE
À VOS CÔTÉS, DANS UN CLIMAT QUI CHANGE

Bulletin d'estimation du risque d'avalanche
(valable en dehors des pistes balisées et ouvertes)

MASSIF : Cerdagne Canigou

Rédigé le lundi 23 février 2026 à 16h

Estimation des risques pour le : MARDI 24 FÉVRIER

HUMIDIFICATION QUI SE POURSUIT EN VERSANT SUD EN GAGNANT EN ALTITUDE

2

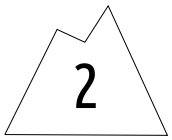

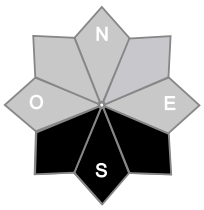

Indice de risque limité.

Départs spontanés : Dans les versants ensoleillés et en neige humide

Déclenchements provoqués : Peu probable ou en neige humide en surface

Indices de risque : 5 très fort - 4 fort - 3 marqué - 2 limité - 1 faible -- En noir : les pentes les plus dangereuses

Stabilité du manteau neigeux

Situation avalancheuse typique : neige humide avalanches de fond

Départs spontanés :
Activité avalancheuse qui devrait augmenter au fil de la journée dans les pentes raides prenant le soleil, et notamment à proximités des rochers. Départs d'avalanches petites à moyennes, plus rarement grandes, avec l'humidification qui se généralise à des altitudes plus élevées. Les pentes raides des versants ensoleillées entre 2100 et 2500 m seront notamment concernées par une humidification plus en profondeur que les jours précédents.
En dessous de 2000 m principalement, des avalanches de fond sont aussi possibles à toute heure, de taille petite à moyenne avec déjà des reptations ou gueules de baleine visibles actuellement.

Déclenchements provoqués :
Peu probable avec les dernières chutes de neige datant de la semaine dernière. Des coulées de neige humide sont tout de même possibles au passage d'un skieur dans une couche de neige profondément humidifiée.

Autre : La neige a pris des allures printanières dans de nombreux secteurs avec un risque accru de glissade sur des croutes parfois dures et épaisses suite au regel nocturne.

Qualité de la neige

Enneigement :
L'enneigement est largement supérieur à celui des cinq dernières années et se situe au plus haut par rapport aux statistiques plus anciennes. Malgré les belles journées qui s'enchaînent et la douceur, la limite d'enneigement skiable n'évolue peu avec le regel nocturne qui permet toujours de chausser les skis dès 1500 m, rarement plus bas dans les conditions les plus favorables.

Qualité de la neige :
Mardi matin, on trouvera en dessous de 2100m une neige croutée plus ou moins portante. En journée avec l'ensoleillement, on trouvera des conditions printanières dans les versants prenant le soleil, avec l'humidification en profondeur du manteau neigeux. L'humidification remonte jusqu'à 2500 m en versant sud avec de la neige lourde et très humide, notamment à basse altitude. Dans les secteurs ombragés d'altitude, on pourra trouver une neige encore froide et sèche, tassée par le vent.
Proche des crêtes et sommet, l'enneigement est très hétérogène avec des secteurs bien soufflés et parfois glacés, particulièrement sur les flancs ouest.

Aperçu météo pour le mardi 24 février

	nuit	matin	après-midi	soir
Beau temps avec un voile de nuages d'altitude et des températures très douces en journée.				
Pluie-Neige				
Iso 0 °C	3 400 m	3 400 m	3 400 m	3 400 m
Vent 2000 m	↗ 10 km/h	↑ 10 km/h	↗ 10 km/h	↑ 15 km/h
Vent 3000 m	↑ 20 km/h	↗ 15 km/h	↗ 20 km/h	↗ 15 km/h

Épaisseur de neige hors-piste

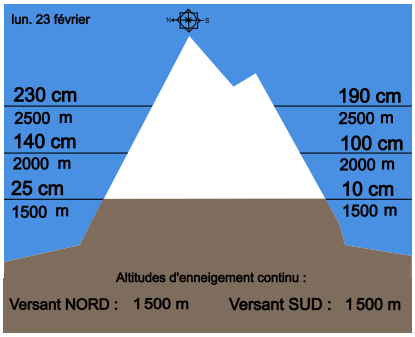

Précipitations à 1800 m

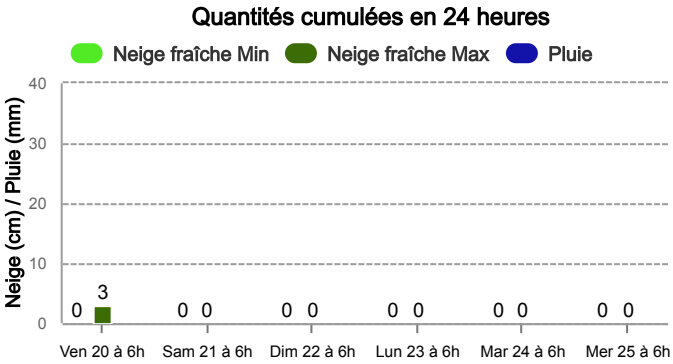

Tendance du mercredi 25 février

2

Indice de risque limité

Sans changement significatif avec les cycles de gel/dégel en cours.

Pour consulter la vigilance en cours, veuillez vous rendre sur le site https://vigilance.meteofrance.fr/fr

Météo-France - 73 avenue de Paris, 94165 Saint-Mandé cedex - Contact : contact@meteo.fr

Rédigé par Météo-France avec la contribution des observateurs du réseau nivo-météorologiques. Partenariat : ANMSM (Maires de Stations de Montagne), DSF (Domaines Skiables de France), ADSP (Directeurs de Pistes et de la Sécurité des Stations de Sports d'Hiver) et autres acteurs de la montagne.

Bulletin neige & avalanches par téléphone au
0 892 68 10 20 Service 0,35 € / min + prix appel

RÉPUBLIQUE FRANÇAISE
Liberté Égalité Fraternité

METEO FRANCE
À VOS CÔTÉS, DANS UN CLIMAT QUI CHANGE

Bulletin d'estimation du risque d'avalanche

(valable en dehors des pistes balisées et ouvertes)

MASSIF : Cerdagne Canigou

Rédigé le lundi 23 février 2026 à 16h

Conditions nivo-météo des 7 derniers jours

	mar. 17/02				mer. 18/02				jeu. 19/02				ven. 20/02				sam. 21/02				dim. 22/02				lun. 23/02			
	03h	09h	15h	21h	03h	09h	15h	21h	03h	09h	15h	21h	03h	09h	15h	21h	03h	09h	15h	21h	03h	09h	15h	21h	03h	09h	15h	21h
Météo																												
Vent (km/h)	120	110	90	75	65	55	70	80	80	70	70	75	65	65	55	50	45	35	30	25	20	15	15	15	20	20	20	15
à 3000m	↘	↘	↘	↘	→	↗	↗	↗	↘	↓	↓	↓	↓	↓	↓	↓	↓	↓	↓	↓	↗	↗	→	→	↘	↘	↘	↘
Vent (km/h)	85	65	50	40	30	25	35	50	75	60	60	65	60	60	40	30	25	20	20	15	10	10	10	10	10	10	10	10
à 2000m	↘	↘	↘	→	→	↗	↗	↗	↘	↓	↓	↓	↓	↓	↓	↓	↓	↓	↓	↓	↗	↗	→	↗	↘	↘	→	↘

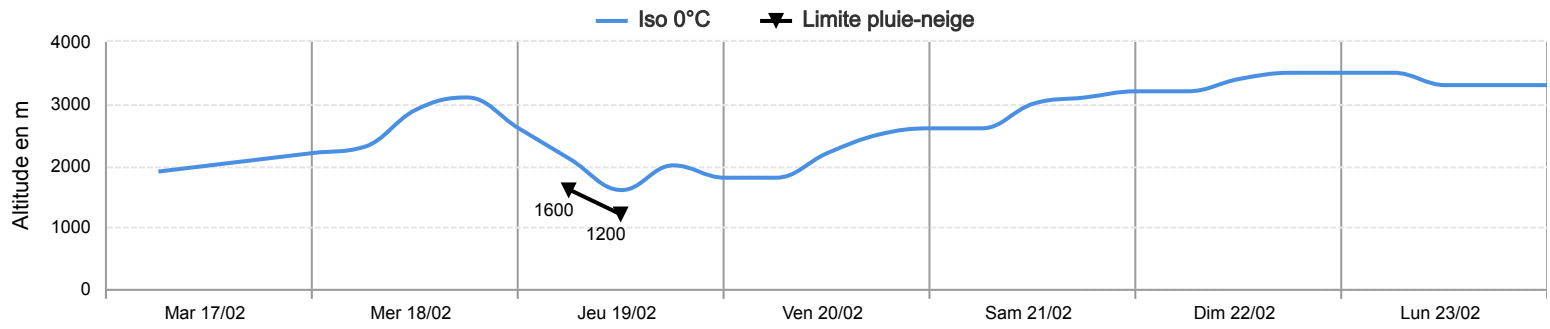

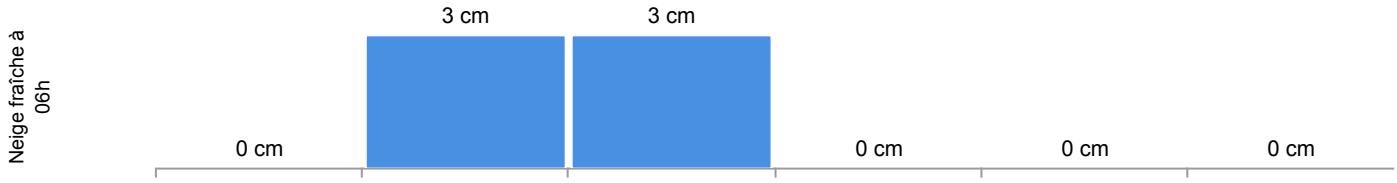

Risque d'avalanche	mar. 17/02	mer. 18/02	jeu. 19/02	ven. 20/02	sam. 21/02	dim. 22/02	lun. 23/02
	3	3	3	3	3	2	2

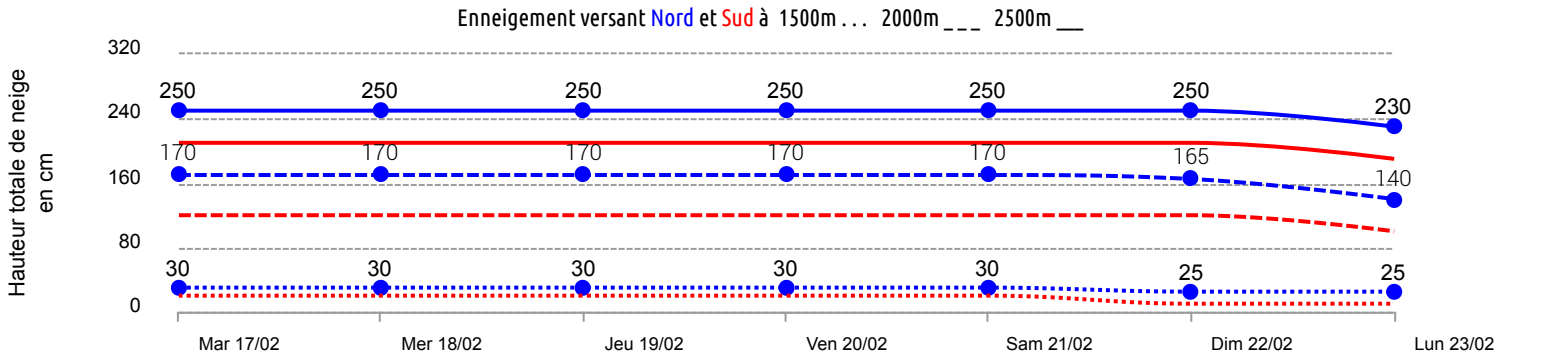

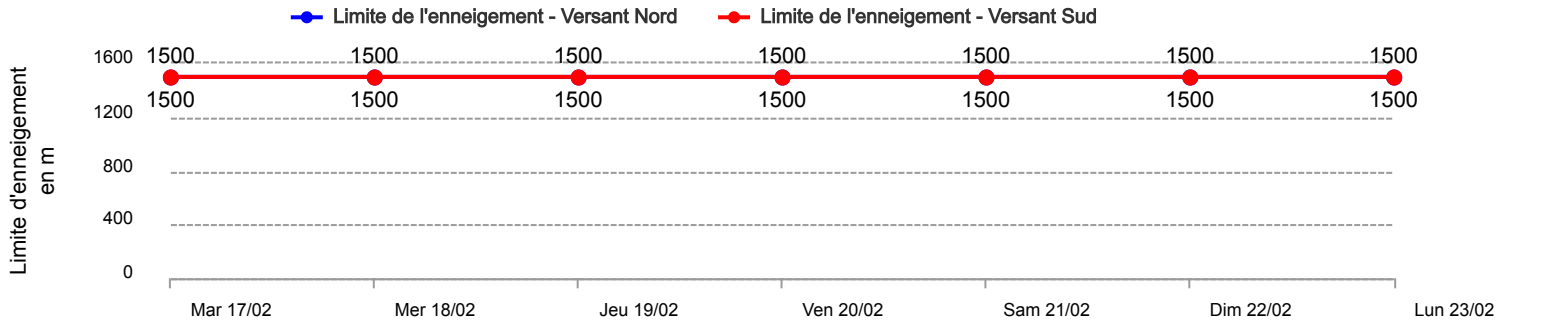

Pour consulter la vigilance en cours, veuillez vous rendre sur le site https://vigilance.meteofrance.fr/fr

Météo-France - 73 avenue de Paris, 94165 Saint-Mandé cedex - Contact : contact@meteo.fr

Rédigé par Météo-France avec la contribution des observateurs du réseau nivo-météorologiques. Partenariat : ANMSM (Maires de Stations de Montagne), DSF (Domaines Skiables de France), ADSP (Directeurs de Pistes et de la Sécurité des Stations de Sports d'Hiver) et autres acteurs de la montagne.

Bulletin neige & avalanches par téléphone au

0 892 68 10 20 Service 0,35 € / min + prix appel