# Bulletin d'estimation du risque d'avalanche
## (valable en dehors des pistes balisées et ouvertes)

# MASSIF : Chablais

Rédigé le lundi 23 février 2026 à 16h

## Estimation des risques pour le : MARDI 24 FÉVRIER

**FORTE HUMIDIFICATION DU MANTEAU NEIGEUX, MARQUÉ EN ADRETS.**

3

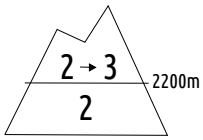


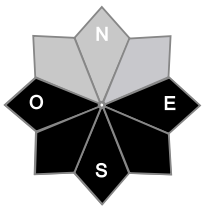


Soleil et chaleur

Au-dessus de 2200m indice de risque limité évoluant en marqué, plus bas indice limité.

**Départs spontanés :** Nombreux départs en neige humide sous les fortes températures. Plaques de fond.

**Déclenchements provoqués :** Encore quelques plaques à vent en altitude.

Indices de risque : 5 très fort - 4 fort - 3 marqué - 2 limité - 1 faible -- En noir : les pentes les plus dangereuses

## Stabilité du manteau neigeux

**Situation avalancheuse typique :** neige humide avalanches de fond

**Départs spontanés :**

* **Nombreuses avalanches de neige humide** attendues sous la forte hausse des températures. Ces avalanches sont plus nombreuses dans les adrets, mais les ubacs bas ne semblent pas être épargnés. **Au fil de la journée, les départs sont de plus en plus probables**. Au-dessus de 2000/2200m, les volumes mobilisables sont importants et ainsi des avalanches de taille 2 à 3 sont possibles. Plus bas, les volumes sont plus faibles, mais les départs potentiellement plus nombreux. Taille 1 à 2.
* Sous 2200m, nombreuses **plaques de fond** en tous versants, avec des départs un peu plus nombreux dans un très large secteur sud (E/S/W). Départs dans les pentes raides et lisses. Taille 2, possiblement 3.

**Déclenchements provoqués :**

* Au-dessus de 2200m, il reste encore des plaques à vent dans la neige restée froide. Ces dernières ont été formées par le vent d'W/NW et sont plus nombreuses en altitude et dans les ubacs. Taille 1 à 2. Temporairement au soleil, ces plaques sont plus sensibles au skieur.
* Dans les versants E/N/W au-dessus de 2200/2400 m, une couche fragile persistante est encore présente (mais très enfouie), et pourrait engendrer en cascade de (très) grandes avalanches.
* Coulées humides sous les skis dans les pentes raides.

**Autres :**

* **Chutes de corniches**, épaisses et volumineuses, **pouvant solliciter de très larges plaques friables.**

## Qualité de la neige

Enneigement : Bon pour la saison à toutes altitudes grâce aux fréquentes chutes de neige du mois de février. On peut chausser les skis vers 1200 m dans tous les versants. L'épaisseur du manteau neigeux varie : nombreuses congères, corniches et accumulations.

Qualité de la neige mardi :

* Sous 1800m, évolution de printemps.
* Entre 1800 et 2200/2400, fine croûte en matinée s'humidifiant rapidement et laissant une neige plutôt mate.
* Au-dessus de 2400/2500 m : Neige récente encore légère. Plus ou moins ventée en fonction de l'exposition au vent de W/SW. Elle se densifie légèrement en cours de journée.

## Aperçu météo pour le mardi 24 février

| nuit | matin | après-midi | soir |
|---|---|---|---|
| | | | |

Grand soleil et forte hausse des températures en journée. Vent de plus en plus faible.

| Pluie-Neige | | | | |
|---|---|---|---|---|
| Iso 0 °C | 2 300 m | 2 800 m | 3 000 m | 3 200 m |
| Vent 2000 m | → 20 km/h | ↓ 15 km/h | ↙ 15 km/h | ← 10 km/h |
| Vent 2500 m | → 30 km/h | ↓ 25 km/h | ↙ 20 km/h | ↙ 20 km/h |

## Épaisseur de neige hors-piste

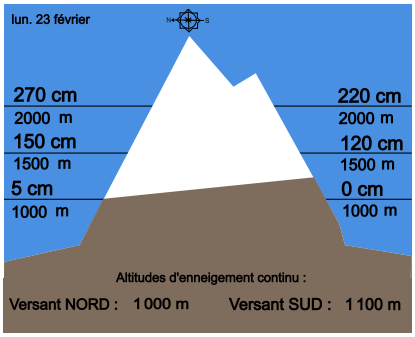


## Précipitations à 1800 m

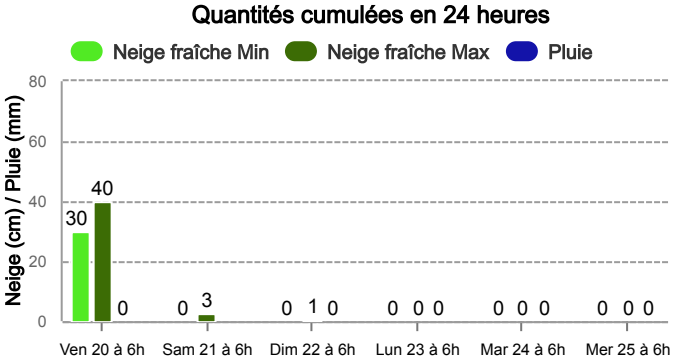


## Tendance du mercredi 25 février

3

**Indice de risque marqué**

Le risque reste marqué en journée de mercredi au vu des températures encore bien chaudes pour la saison.

Pour consulter la vigilance en cours, veuillez vous rendre sur le site https://vigilance.meteofrance.fr/fr

Météo-France - 73 avenue de Paris, 94165 Saint-Mandé cedex - Contact : contact@meteo.fr

Rédigé par Météo-France avec la contribution des observateurs du réseau nivo-météorologiques. Partenariat : ANMSM (Maires de Stations de Montagne), DSF (Domaines Skiables de France), ADSP (Directeurs de Pistes et de la Sécurité des Stations de Sports d'Hiver) et autres acteurs de la montagne.

Bulletin neige & avalanches par téléphone au

**0 892 68 10 20** Service 0,35 € / min + prix appel

RÉPUBLIQUE FRANÇAISE
*Liberté Égalité Fraternité*

METEO FRANCE
À VOS CÔTÉS, DANS UN CLIMAT QUI CHANGE

# Bulletin d'estimation du risque d'avalanche

## (valable en dehors des pistes balisées et ouvertes)

# MASSIF : Chablais

Rédigé le lundi 23 février 2026 à 16h

## Conditions nivo-météo des 7 derniers jours

| | mar. 17/02 | | | | mer. 18/02 | | | | jeu. 19/02 | | | | ven. 20/02 | | | | sam. 21/02 | | | | dim. 22/02 | | | | lun. 23/02 | | | |
|---|---|---|---|---|---|---|---|---|---|---|---|---|---|---|---|---|---|---|---|---|---|---|---|---|---|---|---|---|
| | 03h | 09h | 15h | 21h | 03h | 09h | 15h | 21h | 03h | 09h | 15h | 21h | 03h | 09h | 15h | 21h | 03h | 09h | 15h | 21h | 03h | 09h | 15h | 21h | 03h | 09h | 15h | 21h |
| Météo | | | | | | | | | | | | | | | | | | | | | | | | | | | | |
| Vent (km/h) | 55 | 55 | 50 | 35 | 30 | 55 | 50 | 60 | 50 | 60 | 50 | 50 | 40 | 35 | 35 | 35 | 40 | 40 | 35 | 35 | 35 | 40 | 45 | 45 | 30 | 25 | 25 | 25 |
| à 2500m | ↘ | ↘ | → | → | → | ↗ | ↗ | ↗ | → | ↗ | → | → | ↘ | ↓ | ↘ | ↘ | ↘ | → | → | → | → | ↗ | ↗ | ↗ | → | → | → | ↘ |
| Vent (km/h) | 45 | 40 | 40 | 25 | 20 | 45 | 40 | 50 | 35 | 50 | 40 | 40 | 30 | 20 | 20 | 20 | 20 | 20 | 20 | 20 | 25 | 25 | 25 | 25 | 25 | 15 | 15 | 10 |
| à 2000m | → | → | → | → | ↗ | ↗ | ↗ | ↗ | ↗ | ↗ | ↗ | → | ↘ | ↘ | → | → | ↗ | ↗ | → | ↗ | ↗ | ↗ | ↗ | ↗ | ↗ | → | → | → |

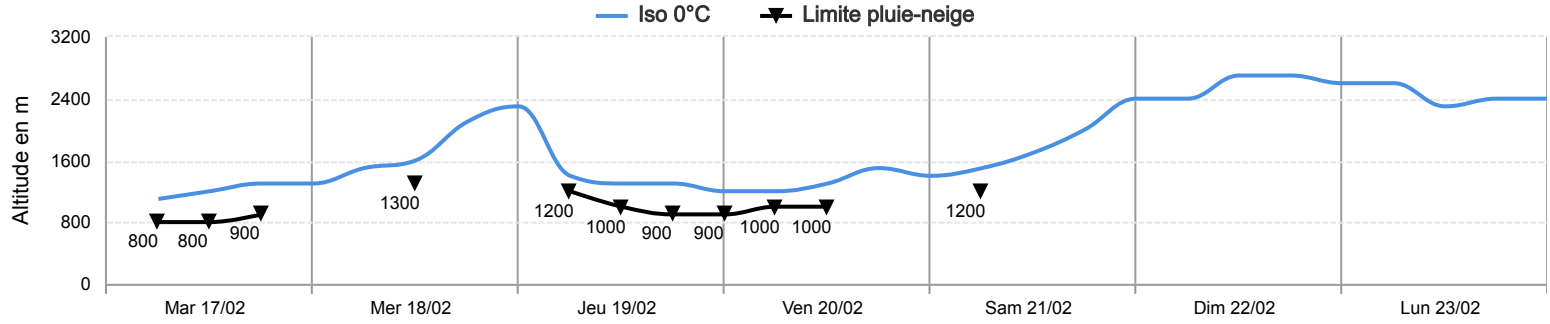


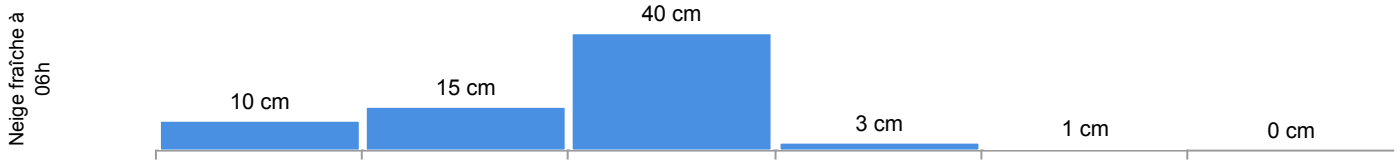


| Risque d'avalanche | mar. 17/02 | mer. 18/02 | jeu. 19/02 | ven. 20/02 | sam. 21/02 | dim. 22/02 | lun. 23/02 |
|---|---|---|---|---|---|---|---|
| | 4 | 4 | 4 | 4 | 4 | 3 | 2 |

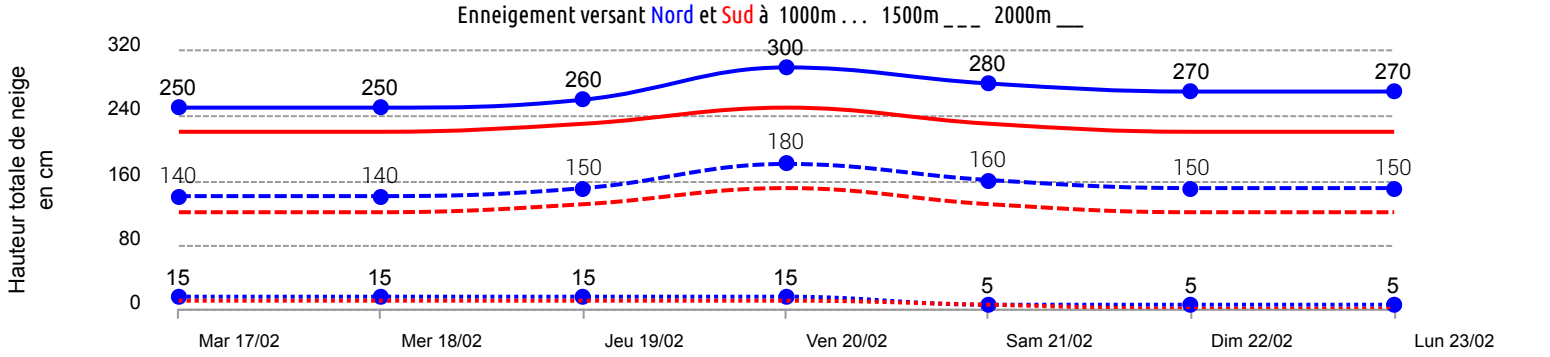


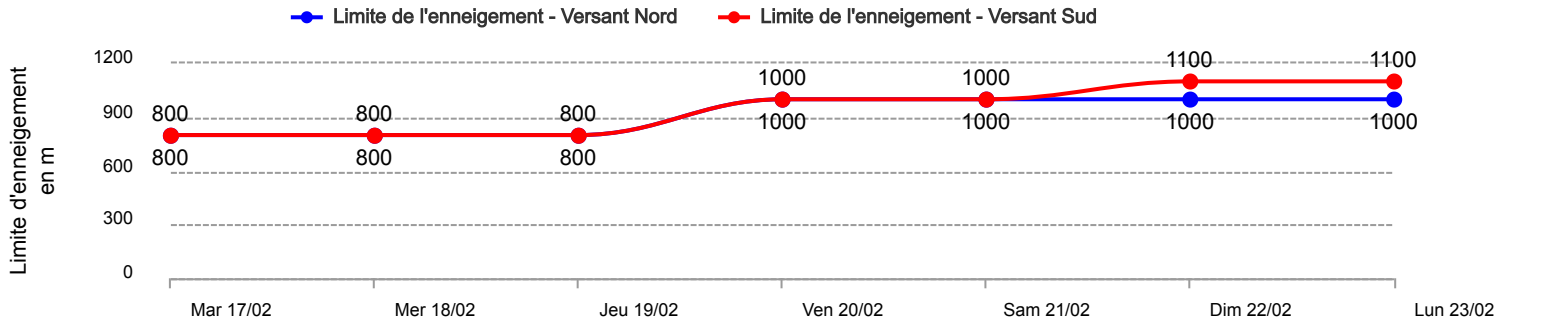


Pour consulter la vigilance en cours, veuillez vous rendre sur le site https://vigilance.meteofrance.fr/fr


Météo-France - 73 avenue de Paris, 94165 Saint-Mandé cedex - Contact : contact@meteo.fr


Bulletin neige & avalanches par téléphone au

**0 892 68 10 20** Service 0,35 € / min + prix appel


Rédigé par Météo-France avec la contribution des observateurs du réseau nivo-météorologiques. Partenariat : ANMSM (Maires de Stations de Montagne), DSF (Domaines Skiables de France), ADSP (Directeurs de Pistes et de la Sécurité des Stations de Sports d'Hiver) et autres acteurs de la montagne.