Bulletin d'estimation du risque d'avalanche
(valable en dehors des pistes balisées et ouvertes)

MASSIF : Devoluy

Rédigé le lundi 23 février 2026 à 16h

Estimation des risques pour le : MARDI 24 FÉVRIER

ACTIVITÉ NATURELLE MARQUÉE AU SOLEIL

3

2 → 3

N O E S

Indice de risque limité évoluant en marqué.

Départs spontanés : au soleil, parfois de grande taille

Déclenchements provoqués : instabilités

Indices de risque : 5 très fort - 4 fort - 3 marqué - 2 limité - 1 faible -- En noir : les pentes les plus dangereuses

Stabilité du manteau neigeux

Situation avalancheuse typique : neige humide — neige ventée

Déclenchements provoqués : instabilités résiduelles en altitude, au-dessus de 2000/2200 m environ. Avalanches déclenchables par un seul skieur et de taille petite à moyenne (taille 1 à 2), plus rarement de grande taille (taille 3).
Les instabilités de surface formées récemment par le vent de nord-ouest se raréfient. Elles sont la plupart d'aspect dur et bien identifiables. Un déclenchement plus large et volumineux (taille 3) n'est pas exclu en large versant nord au-dessus de 2000/2200 m, en cas de sollicitation de couche fragile persistante. Celle-ci est cependant moins présente et moins facilement sollicitable que sur les autres massifs des Hautes-Alpes.

Départs spontanés : peu probables le matin après un bon regel nocturne ; devenant nombreux au soleil, et potentiellement volumineux (taille 2 à 3). Départs ponctuels de neige humide essentiellement près des rochers ou des barres, mais pouvant emporter tout le manteau neigeux humidifié en profondeur en adret raide sous 2000/2200 m. De grandes avalanches atteignant des altitudes relativement basses sont encore possibles. Une première avalanche superficielle en neige humide, ou la chute d'une corniche près des crêtes, peut aussi favoriser un départ linéaire de neige restée sèche, en versant sud-ouest ou sud-est au-dessus de 2000 m. Enfin, avalanches de glissement possibles dans les orientations bien ensoleillées d'altitude, en terrain favorable (dalles lisses, alpages herbeux), de taille 1 à 2.

Qualité de la neige

L'enneigement est très excédentaire pour un mois de février. On observe près de 2m50 de neige à 2000 m à Superdévoluy.

Limite d'enneigement skiable dès 1100 m sur terrain favorable, mais l'enneigement fond rapidement en adret raide et devient un peu juste sous 1600 m.

État de la neige de surface : manteau neigeux fortement travaillé par le vent qui a cartonné ou durci de nombreuses pentes. Enneigement hétérogène près des hautes crêtes avec d'importantes accumulations et corniches qui côtoient des secteurs décapés par le vent.
Manteau neigeux en cycle printanier (croûté le matin, s'humidifiant en journée) en adrets jusqu'à haute altitude, il débute en ubacs sous 1800/2000 m environ.

Aperçu météo pour le mardi 24 février

	nuit	matin	après-midi	soir
Pluie-Neige				
Iso 0 °C	3 300 m	3 300 m	3 200 m	3 200 m
Vent 2000 m	35 km/h	20 km/h	10 km/h	10 km/h
Vent 3000 m	50 km/h	25 km/h	15 km/h	5 km/h

Printanier et rapidement chaud au soleil, vent faible même sur les crêtes. +11°C à 2000 m, +3 à 3000.

Épaisseur de neige hors-piste

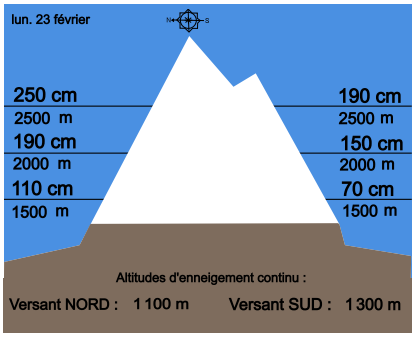

Précipitations à 1800 m

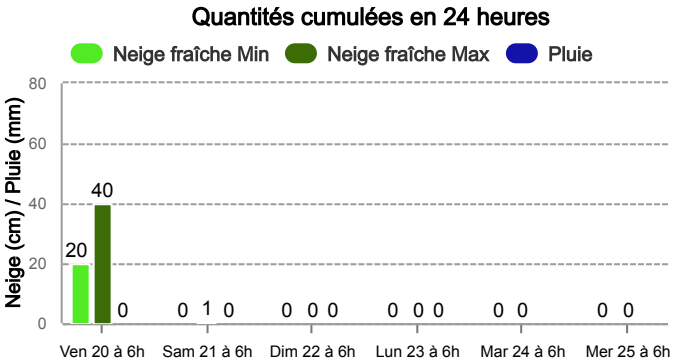

Tendance du mercredi 25 février

3

Indice de risque marqué

Peu d'évolution. Poursuite de l'humidification aux basses altitudes, encore de grandes avalanches de neige humide possibles.

Pour consulter la vigilance en cours, veuillez vous rendre sur le site https://vigilance.meteofrance.fr/fr

Météo-France - 73 avenue de Paris, 94165 Saint-Mandé cedex - Contact : contact@meteo.fr

Rédigé par Météo-France avec la contribution des observateurs du réseau nivo-météorologiques. Partenariat : ANMSM (Maires de Stations de Montagne), DSF (Domaines Skiables de France), ADSP (Directeurs de Pistes et de la Sécurité des Stations de Sports d'Hiver) et autres acteurs de la montagne.

Bulletin neige & avalanches par téléphone au 0 892 68 10 20 Service 0,35 € / min + prix appel

RÉPUBLIQUE FRANÇAISE
Liberté Égalité Fraternité

METEO FRANCE
À VOS CÔTÉS, DANS UN CLIMAT QUI CHANGE

Bulletin d'estimation du risque d'avalanche

(valable en dehors des pistes balisées et ouvertes)

MASSIF : Devoluy

Rédigé le lundi 23 février 2026 à 16h

Conditions nivo-météo des 7 derniers jours

	mar. 17/02				mer. 18/02				jeu. 19/02				ven. 20/02				sam. 21/02				dim. 22/02				lun. 23/02			
	03h	09h	15h	21h	03h	09h	15h	21h	03h	09h	15h	21h	03h	09h	15h	21h	03h	09h	15h	21h	03h	09h	15h	21h	03h	09h	15h	21h
Météo																												
Vent (km/h)	90	80	75	70	50	35	40	65	50	55	70	75	80	90	80	80	80	80	80	60	40	35	35	40	45	50	60	60
à 3000m																												
Vent (km/h)	70	60	55	50	40	20	20	45	45	30	40	55	75	60	60	60	45	60	60	40	25	15	15	15	20	40	40	30
à 2000m																												

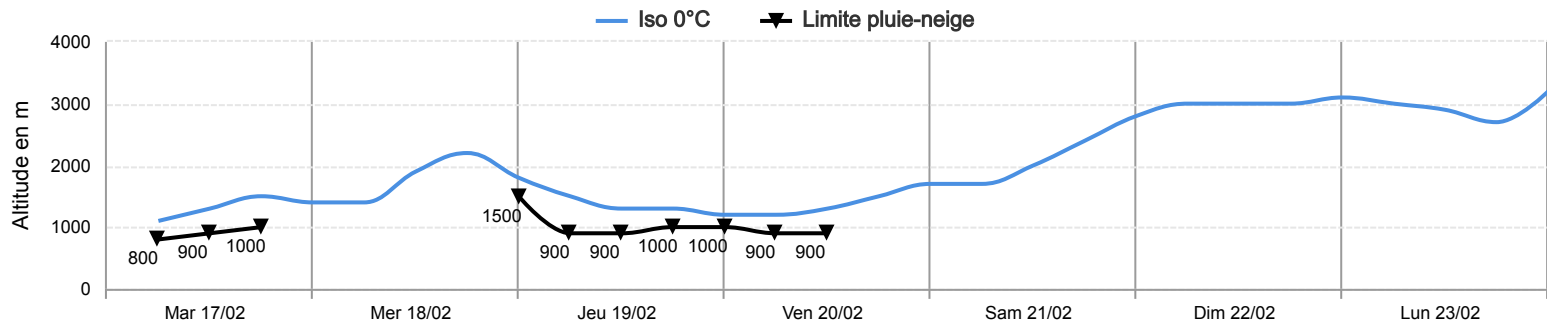

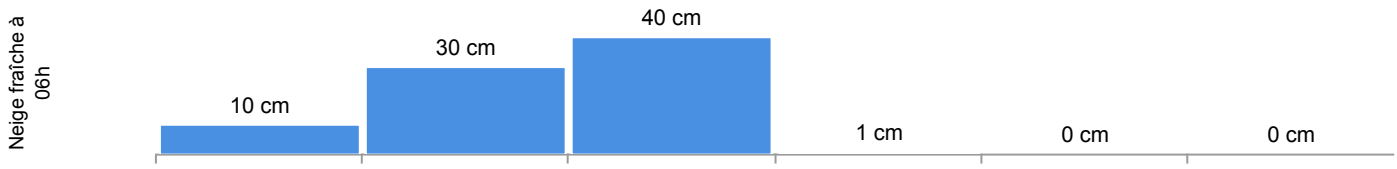

Risque d'avalanche	mar. 17/02	mer. 18/02	jeu. 19/02	ven. 20/02	sam. 21/02	dim. 22/02	lun. 23/02
	4	4	4	4	4	3	3

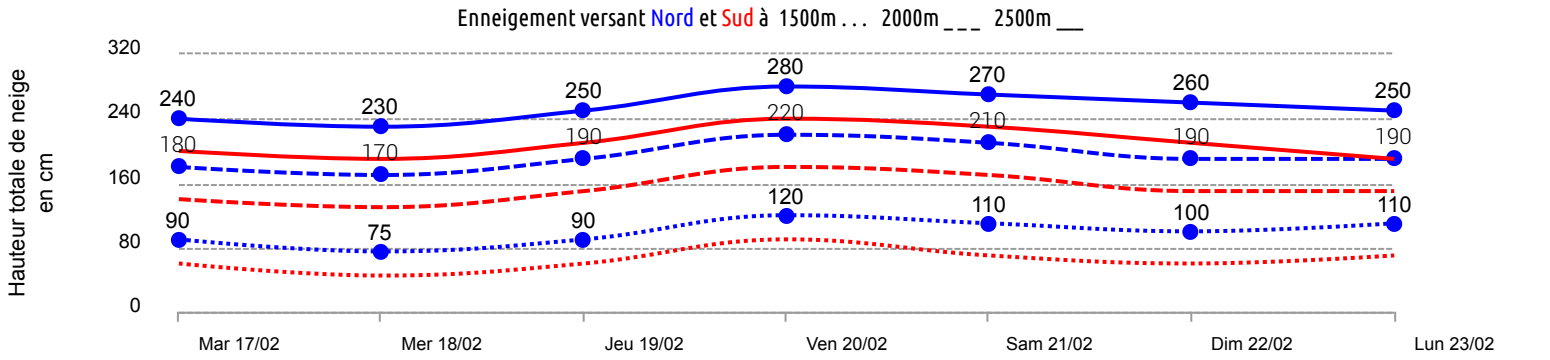

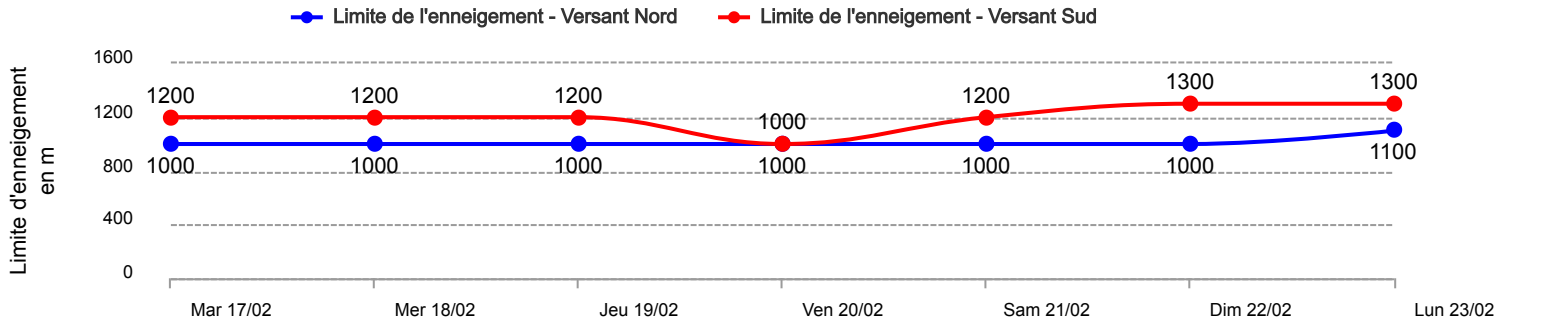

Pour consulter la vigilance en cours, veuillez vous rendre sur le site https://vigilance.meteofrance.fr/fr

Météo-France - 73 avenue de Paris, 94165 Saint-Mandé cedex - Contact : contact@meteo.fr

Rédigé par Météo-France avec la contribution des observateurs du réseau nivo-météorologiques. Partenariat : ANMSM (Maires de Stations de Montagne), DSF (Domaines Skiables de France), ADSP (Directeurs de Pistes et de la Sécurité des Stations de Sports d'Hiver) et autres acteurs de la montagne.

Bulletin neige & avalanches par téléphone au

0 892 68 10 20 Service 0,35 € / min + prix appel