RÉPUBLIQUE FRANÇAISE
Liberté Égalité Fraternité

METEO FRANCE
À VOS CÔTÉS, DANS UN CLIMAT QUI CHANGE

Bulletin d'estimation du risque d'avalanche
(valable en dehors des pistes balisées et ouvertes)

MASSIF : Embrunais Parpaillon

Rédigé le lundi 23 février 2026 à 16h

Estimation des risques pour le : MARDI 24 FÉVRIER

INSTABILITÉS ÉPAISSES DISSÉMINÉES EN ALTITUDE ; ACTIVITÉ NATURELLE LIMITÉE AU SOLEIL

3

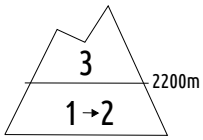

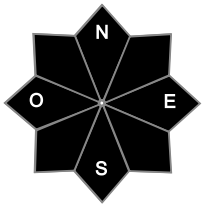

Au-dessus de 2200m indice de risque marqué, plus bas indice faible évoluant en limité.

Départs spontanés : au soleil, parfois linéaires et de grande taille

Déclenchements provoqués : instabilités encore facilement déclenchables en altitude, localement très volumineuses

Indices de risque : 5 très fort - 4 fort - 3 marqué - 2 limité - 1 faible -- En noir : les pentes les plus dangereuses

Stabilité du manteau neigeux

Situation avalancheuse typique : couche fragile persistante neige humide

Déclenchements provoqués : instabilités disséminées dans le manteau neigeux, possibles en toutes orientations au-dessus de 2000/2200 m environ. Avalanches déclenchables par un seul skieur et de taille petite à moyenne (taille 1 à 2), parfois grande (taille 3) notamment en versants froids d'altitude.
Les instabilités de surface formées récemment par le vent de nord-ouest se raréfient. Elles sont la plupart d'aspect dur et bien identifiables, mais reposent localement sur une **couche fragile persistante. Enfouie à la base du manteau neigeux et le plus souvent non observable de la surface, celle-ci pilote largement le danger d'avalanche pour le pratiquant.** Un seul skieur peut déclencher, parfois à distance, **une plaque épaisse et large** (taille 3) ; aléatoires et peu fréquents dans les grandes pentes homogènes, ces déclenchements sont plus probables au niveau des discontinuités de terrain (croupes, proximité des rochers, ruptures de pentes..). Cette couche fragile concerne également certaines orientations ensoleillées d'altitude, mais sa sollicitation est éventuellement retardée par le regel nocturne superficiel.

Départs spontanés : peu probables le matin après un bon regel nocturne ; devenant nombreux au soleil, de taille moyenne. Départs ponctuels de neige humide essentiellement près des rochers ou des barres, mais pouvant emporter tout le manteau neigeux humidifié en profondeur en adret raide sous 2000/2200 m. Une première avalanche superficielle en neige humide, ou la chute d'une corniche près des crêtes, peut aussi favoriser un départ linéaire de neige restée sèche, en versant sud-ouest ou sud-est au-dessus de 2000 m, ou en versant plein sud au-dessus de 2500/2600 m environ. Enfin, avalanches de glissement non exclues dans les orientations bien ensoleillées d'altitude, en terrain favorable (dalles lisses, alpages herbeux), de taille 1 à 2.

Qualité de la neige

L'enneigement est excédentaire pour un mois de février.
Hauteurs de neige observées vers 2500 m : environ 100 cm à la Nivôse du Parpaillon à 2550 m, secteur soufflé par le vent.

Limite d'enneigement skiable vers 1200/1300 m en ubacs, plutôt 1600/1800 m en adrets.

État de la neige de surface : manteau neigeux fortement travaillé par le vent qui a cartonné ou durci de nombreuses pentes. Enneigement hétérogène près des hautes crêtes avec d'importantes accumulations et corniches qui côtoient des secteurs décapés par le vent.
La neige de surface reste localement poudreuse et légère en ubacs d'altitude bien abrités du vent, notamment en forêts.
Manteau neigeux en cycle printanier (croûté le matin, s'humidifiant en journée) en adrets pas trop raides jusqu'à 2500/2600 m environ, il débute en ubacs sous 1800/2000 m environ.

Aperçu météo pour le mardi 24 février

	nuit	matin	après-midi	soir

Printanier et rapidement chaud au soleil, vent faible même sur les crêtes. +11°C à 2000 m, +3 à 3000.

Pluie-Neige				
Iso 0 °C	3 300 m	3 300 m	3 300 m	3 300 m
Vent 2000 m	← 15 km/h	← 20 km/h	↻ 0 km/h	↖ 10 km/h
Vent 3000 m	↘ 25 km/h	↓ 10 km/h	↘ 5 km/h	↑ 5 km/h

Épaisseur de neige hors-piste

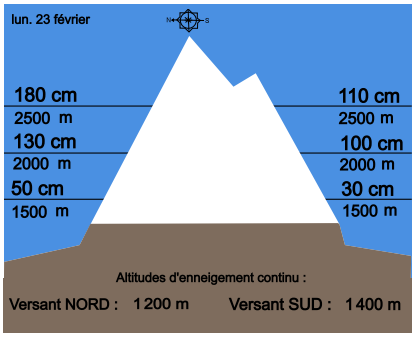

Précipitations à 1800 m

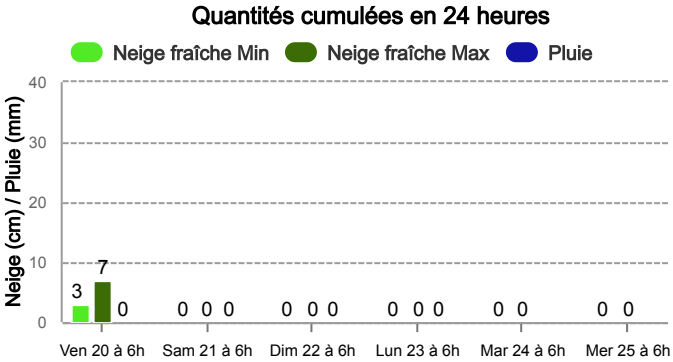

Tendance du mercredi 25 février

3 **Indice de risque marqué**

Peu d'évolution. Maintien d'instabilités dans la neige sèche en altitude. Risque marqué.

Pour consulter la vigilance en cours, veuillez vous rendre sur le site https://vigilance.meteofrance.fr/fr

Météo-France - 73 avenue de Paris, 94165 Saint-Mandé cedex - Contact : contact@meteo.fr

Rédigé par Météo-France avec la contribution des observateurs du réseau nivo-météorologiques. Partenariat : ANMSM (Maires de Stations de Montagne), DSF (Domaines Skiables de France), ADSP (Directeurs de Pistes et de la Sécurité des Stations de Sports d'Hiver) et autres acteurs de la montagne.

Bulletin neige & avalanches par téléphone au
0 892 68 10 20 Service 0,35 € / min + prix appel

RÉPUBLIQUE FRANÇAISE
Liberté Égalité Fraternité

METEO FRANCE
À VOS CÔTÉS, DANS UN CLIMAT QUI CHANGE

Bulletin d'estimation du risque d'avalanche
(valable en dehors des pistes balisées et ouvertes)
MASSIF : Embrunais Parpaillon

Rédigé le lundi 23 février 2026 à 16h

Conditions nivo-météo des 7 derniers jours

	mar. 17/02				mer. 18/02				jeu. 19/02				ven. 20/02				sam. 21/02				dim. 22/02				lun. 23/02			
	03h	09h	15h	21h	03h	09h	15h	21h	03h	09h	15h	21h	03h	09h	15h	21h	03h	09h	15h	21h	03h	09h	15h	21h	03h	09h	15h	21h
Météo																												
Vent (km/h)	95	85	75	70	45	40	35	60	55	50	70	55	70	60	60	60	60	60	70	60	35	30	40	40	40	40	40	35
à 3000m																												
Vent (km/h)	55	40	35	20	15	15	15	20	25	25	35	20	25	50	40	50	40	25	25	45	15	10	10	10	10	10	0	10
à 2000m																												

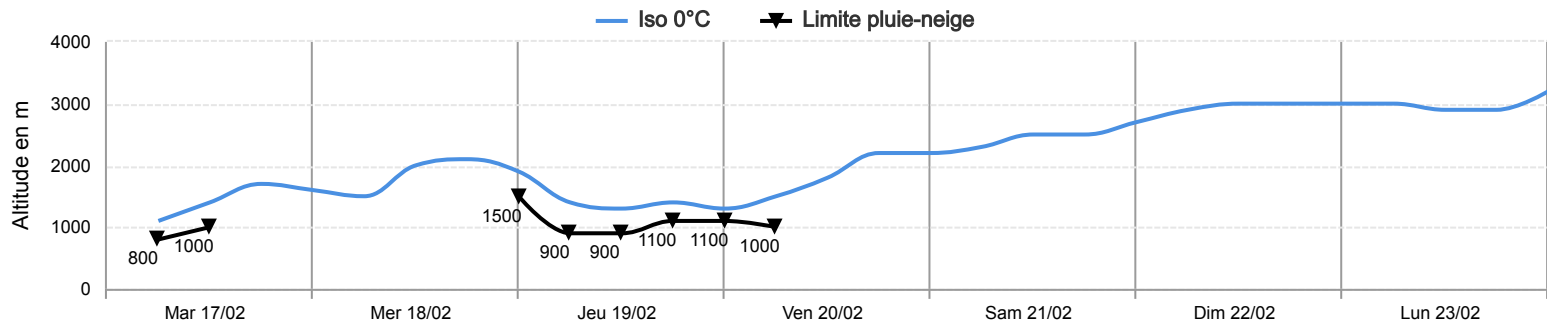

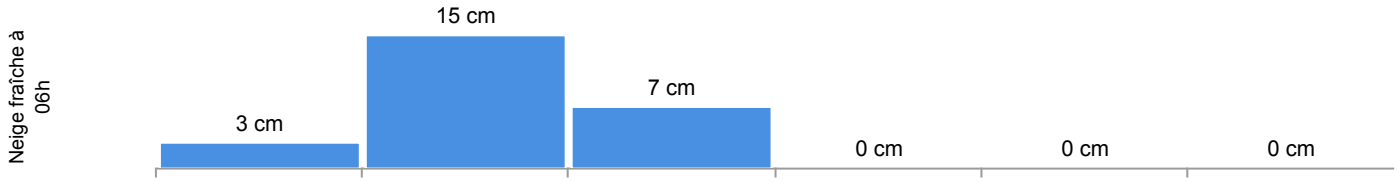

Risque d'avalanche	mar. 17/02	mer. 18/02	jeu. 19/02	ven. 20/02	sam. 21/02	dim. 22/02	lun. 23/02
	3	3	4	3	3	3	3

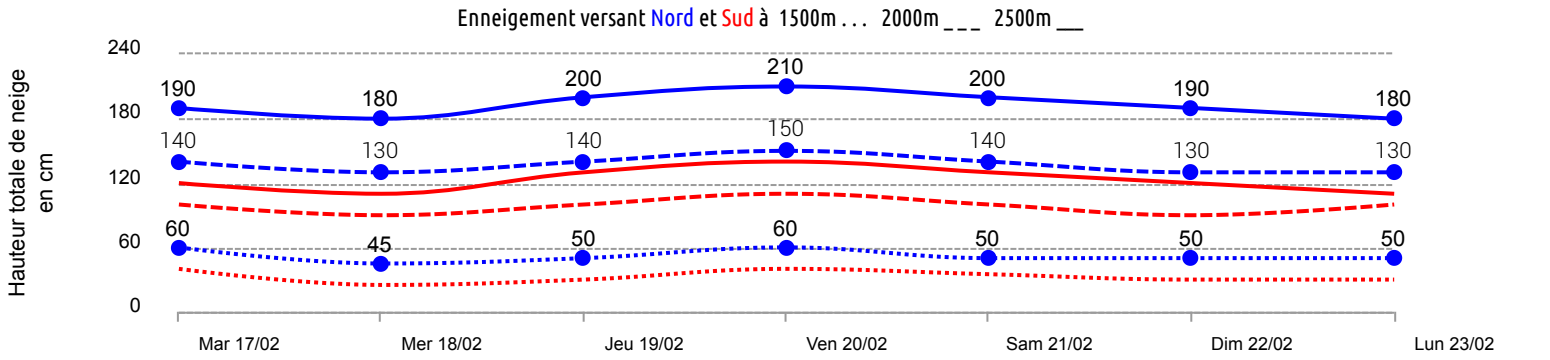

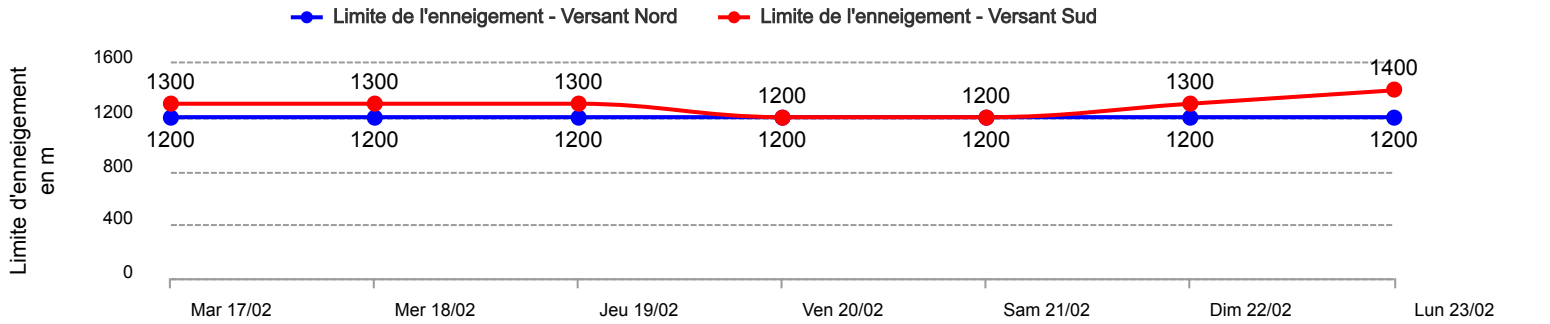

Pour consulter la vigilance en cours, veuillez vous rendre sur le site https://vigilance.meteofrance.fr/fr

Météo-France - 73 avenue de Paris, 94165 Saint-Mandé cedex - Contact : contact@meteo.fr

Rédigé par Météo-France avec la contribution des observateurs du réseau nivo-météorologiques. Partenariat : ANMSM (Maires de Stations de Montagne), DSF (Domaines Skiables de France), ADSP (Directeurs de Pistes et de la Sécurité des Stations de Sports d'Hiver) et autres acteurs de la montagne.

Bulletin neige & avalanches par téléphone au
0 892 68 10 20 Service 0,35 € / min + prix appel