Bulletin d'estimation du risque d'avalanche

(valable en dehors des pistes balisées et ouvertes)

MASSIF : Haut-Var Haut-Verdon

Rédigé le lundi 23 février 2026 à 16h

Estimation des risques pour le : MARDI 24 FÉVRIER

PLAQUES DANS LA NEIGE RÉCENTE VENTÉE, DÉPARTS NATURELS EN NEIGE HUMIDE

3

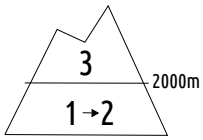

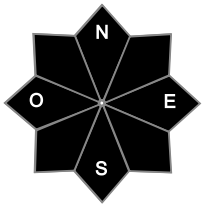

Au-dessus de 2000m indice de risque marqué, plus bas indice faible évoluant en limité.

Départs spontanés : en neige humide, devenant nombreux dans les versants ensoleillés au fil de la journée.

Déclenchements provoqués : instabilités dans la neige récente ventée en altitude.

Indices de risque : 5 très fort - 4 fort - 3 marqué - 2 limité - 1 faible -- En noir : les pentes les plus dangereuses

Stabilité du manteau neigeux

Situation avalancheuse typique : couche fragile persistante neige humide

Déclenchements provoqués :

— Instabilités dans la neige récente ventée, plus fréquentes en versants nord-ouest à sud-est au-dessus de 2000 m environ. Plaques d'aspect variable : en neige durcie par le vent proche des crêtes, parfois encore friables dans les zones plus abritées, voire même en neige humide en surface en versants ensoleillés d'altitude. Ces plaques sont encore faciles à déclencher au passage d'un seul skieur et engendrent des avalanches de taille petite à moyenne (taille 1 à 2), rarement grande (taille 3) dans les zones de forte accumulation.

— Dans le Haut-Verdon en orientations ouest, nord et est d'altitude supérieure à 2000/2200 m environ, une grande, voire très grande avalanche (taille 3 à 4) est possible, par sollicitation d'une couche fragile persistante enfouie à la base du manteau neigeux. Déclenchement difficile au passage d'un skieur, mais possible là où le manteau neigeux est moins épais (croupes, bords de couloirs), ou en cascade après un premier départ en surface.

— Des départs sous les skis de neige fortement humidifiée sont possibles en versant raides ensoleillés en cours de journée. Avalanches de taille petite à moyenne (taille 1 à 2).

Départs spontanés : départs ponctuels par humidification du manteau neigeux : peu probables en début de journée avec le regel, puis devenant fréquents en cours de journée. Ils se produisent en pentes raides ensoleillées à toutes altitudes, notamment près des rochers. Avalanches de taille petite à moyenne (taille 1 à 2), rarement grande (taille 3), en dessous de 2300/2400 m où le manteau neigeux s'est humidifié jusqu'en profondeur. Des avalanches moyennes à grandes sont également possibles en cas de reptations qui sont en cours d'ouverture, ou suite à la rupture d'une corniche. Ces avalanches peuvent atteindre des altitudes relativement basses et atteindre des fonds de vallées ou chemins en contrebas.

Qualité de la neige

Enneigement très excédentaire pour un mois de février.
Données observées : en ubacs, 90/100 cm dès 1700/1800 m, 135 cm vers les Cabanes de Sanguinière (2040 m) et 181cm vers la Maison Forestière de Valdemars à 2020 m d'altitude.

Enneigement skiable dès 1300/1400 m en terrains favorables, 1600 m en adrets.

État de la neige en surface : neige croutée le matin avec un regel moyen, s'humidifiant rapidement en journée au fil de l'ensoleillement. On retrouve de la neige encore poudreuse en Ubacs au-dessus de 1800/2000 m environ, souvent travaillée/durcie par le vent de nord. Zones dégarnies proches des crêtes, alternant avec des corniches parfois épaisses.

Aperçu météo pour le mardi 24 février

nuit	matin	après-midi	soir

Temps majoritairement ensoleillé malgré quelques fins nuages d'altitude, plus denses en soirée et nuit suivante. Vent de nord faiblissant.

Pluie-Neige				
Iso 0 °C	3 400 m	3 400 m	3 300 m	3 200 m
Vent 2000 m	↓ 15 km/h	↓ 10 km/h	↘ 5 km/h	↙ 5 km/h
Vent 3000 m	↘ 35 km/h	↓ 25 km/h	↘ 10 km/h	↓ 10 km/h

Épaisseur de neige hors-piste

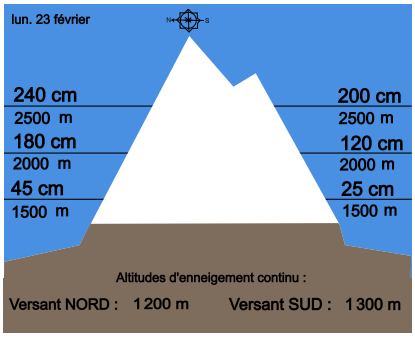

Précipitations à 1800 m

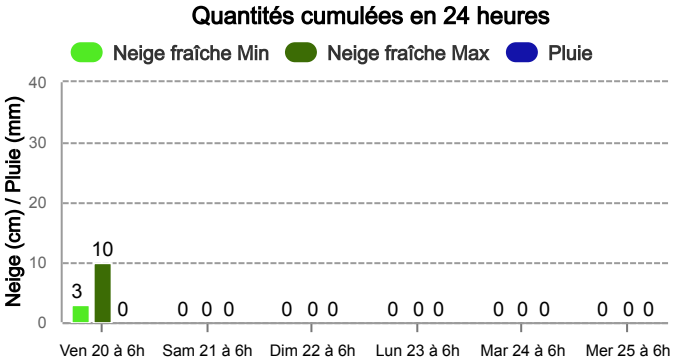

Tendance du mercredi 25 février

3 **Indice de risque marqué**

Maintien d'un risque marqué. Les couches fragiles en place maintiennent la possibilité d'un départ de grande ampleur. Des avalanches de neige humide continuent de se produire au fil de l'ensoleillement.

Pour consulter la vigilance en cours, veuillez vous rendre sur le site https://vigilance.meteofrance.fr/fr

Météo-France - 73 avenue de Paris, 94165 Saint-Mandé cedex - Contact : contact@meteo.fr

Rédigé par Météo-France avec la contribution des observateurs du réseau nivo-météorologiques. Partenariat : ANMSM (Maires de Stations de Montagne), DSF (Domaines Skiables de France), ADSP (Directeurs de Pistes et de la Sécurité des Stations de Sports d'Hiver) et autres acteurs de la montagne.

Bulletin neige & avalanches par téléphone au 0 892 68 10 20 Service 0,35 € / min + prix appel

RÉPUBLIQUE FRANÇAISE
Liberté Égalité Fraternité

METEO FRANCE
À VOS CÔTÉS, DANS UN CLIMAT QUI CHANGE

Bulletin d'estimation du risque d'avalanche

(valable en dehors des pistes balisées et ouvertes)

MASSIF : Haut-Var Haut-Verdon

Rédigé le lundi 23 février 2026 à 16h

Conditions nivo-météo des 7 derniers jours

	mar. 17/02				mer. 18/02				jeu. 19/02				ven. 20/02				sam. 21/02				dim. 22/02				lun. 23/02			
	03h	09h	15h	21h	03h	09h	15h	21h	03h	09h	15h	21h	03h	09h	15h	21h	03h	09h	15h	21h	03h	09h	15h	21h	03h	09h	15h	21h
Météo																												
Vent (km/h)	90	75	70	60	45	40	35	65	50	55	85	85	90	75	50	30	55	60	55	40	40	40	45	50	45	40	30	25
à 3000m																												
Vent (km/h)	65	50	50	40	30	30	15	40	30	45	55	60	50	35	20	20	20	20	25	20	20	25	25	25	30	30	25	15
à 2000m																												

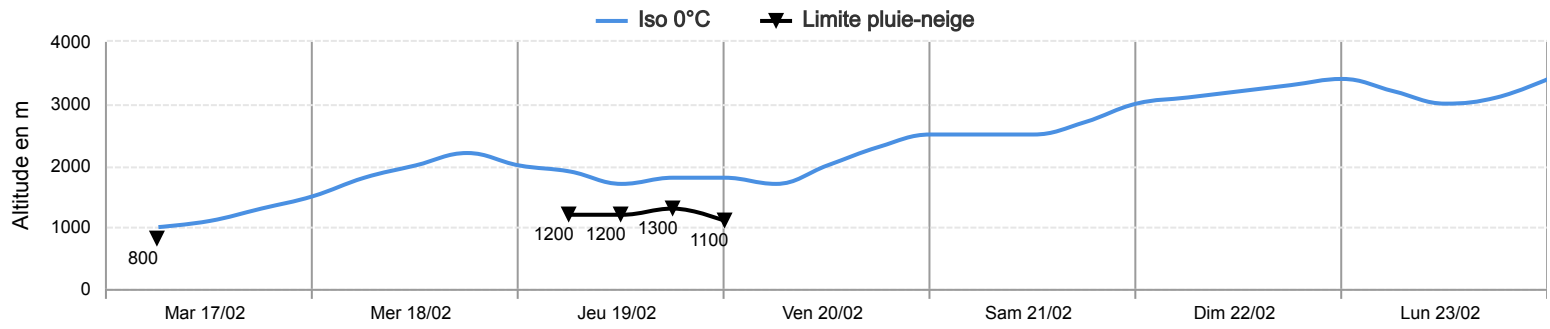

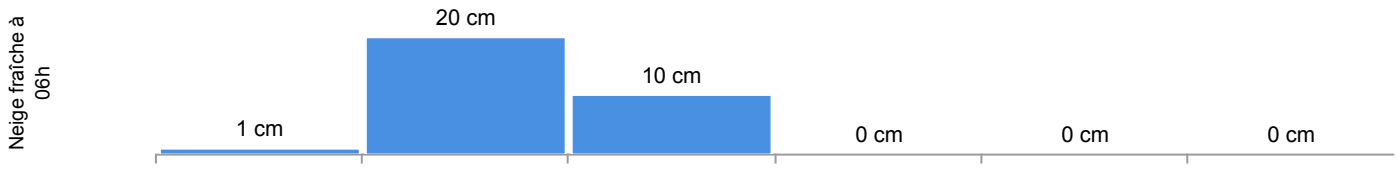

Risque d'avalanche	mar. 17/02	mer. 18/02	jeu. 19/02	ven. 20/02	sam. 21/02	dim. 22/02	lun. 23/02
	3	3	4	3	3	3	3

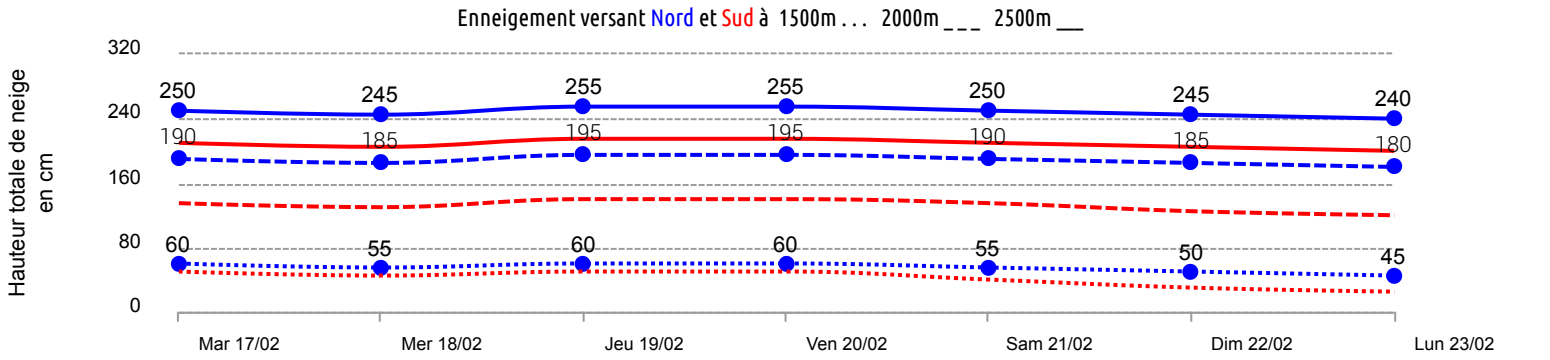

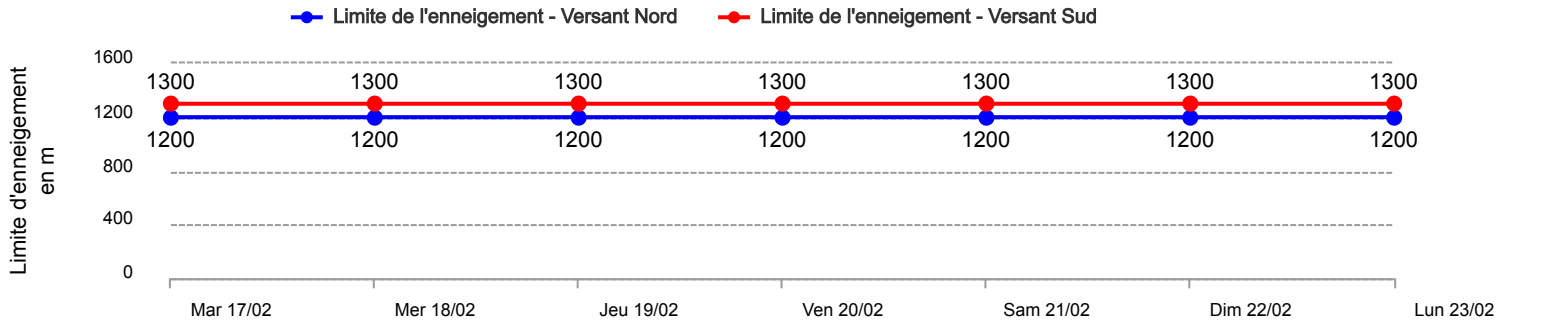

Pour consulter la vigilance en cours, veuillez vous rendre sur le site https://vigilance.meteofrance.fr/fr

Météo-France - 73 avenue de Paris, 94165 Saint-Mandé cedex - Contact : contact@meteo.fr

Rédigé par Météo-France avec la contribution des observateurs du réseau nivo-météorologiques. Partenariat : ANMSM (Maires de Stations de Montagne), DSF (Domaines Skiables de France), ADSP (Directeurs de Pistes et de la Sécurité des Stations de Sports d'Hiver) et autres acteurs de la montagne.

Bulletin neige & avalanches par téléphone au

0 892 68 10 20 Service 0,35 € / min + prix appel