Bulletin d'estimation du risque d'avalanche
(valable en dehors des pistes balisées et ouvertes)

MASSIF : Mercantour

Rédigé le lundi 23 février 2026 à 16h

Estimation des risques pour le : MARDI 24 FÉVRIER

QUELQUES PLAQUES DANS LA NEIGE RÉCENTE VENTÉE, DÉPARTS NATURELS EN NEIGE HUMIDE

2

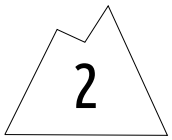

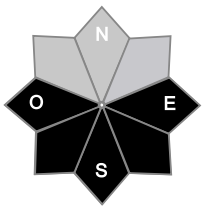

Indice de risque limité.

Départs spontanés : en neige humide, devenant nombreux dans les versants ensoleillés au fil de la journée.

Déclenchements provoqués : quelques petites instabilités dans la neige récente ventée en altitude.

Indices de risque : 5 très fort - 4 fort - 3 marqué - 2 limité - 1 faible -- En noir : les pentes les plus dangereuses

Stabilité du manteau neigeux

Situation avalancheuse typique : neige humide neige ventée

Départs spontanés : départs ponctuels par humidification du manteau neigeux : peu probables en début de journée avec le regel, puis devenant fréquents en cours de journée. Ils se produisent en pentes raides ensoleillées à toutes altitudes, notamment près des rochers. Avalanches de taille petite à moyenne (taille 1 à 2), rarement grande (taille 3), en dessous de 2400/2600 m où le manteau neigeux s'est humidifié jusqu'en profondeur. Des avalanches moyennes à grandes sont également possibles en cas de reptations qui sont en cours d'ouverture, ou suite à la rupture d'une corniche. Ces avalanches peuvent atteindre des altitudes relativement basses et atteindre des fonds de vallées ou chemins en contrebas.

Déclenchements provoqués :

— Quelques instabilités dans la neige récente ventée, principalement en versants nord-ouest à sud-est au-dessus de 2000 m environ. Plaques d'aspect variable : en neige durcie par le vent proche des crêtes, parfois friables dans les zones plus abritées, voire même en neige humide en surface en versants ensoleillés d'altitude. Localement encore facile à déclencher au passage d'un skieur, elles engendrent des avalanches de taille petite à moyenne (taille 1 à 2).

— Des départs sous les skis de neige fortement humidifiée sont possibles en versant raides ensoleillés en cours de journée. Avalanches de taille petite à moyenne (taille 1 à 2)

Qualité de la neige

Enneigement très excédentaire pour un mois de février.
Données observées : 148 cm à la nivôse de Millefonts à 2430 m.

Enneigement skiable dès 1300/1400 m en ubacs en terrains favorables et 1600/1800 m en adrets

État de la neige en surface : neige croutée le matin avec un regel moyen, s'humidifiant rapidement en journée au fil de l'ensoleillement. On retrouve de la neige encore poudreuse en Ubacs au-dessus de 1900/2100 m environ, souvent travaillée/durcie par le vent de nord. Zones dégarnies proches des crêtes, alternant avec des corniches parfois épaisses.

Aperçu météo pour le mardi 24 février

nuit	matin	après-midi	soir

Temps majoritairement ensoleillé malgré quelques fins nuages d'altitude, plus denses en soirée et nuit suivante. Vent de nord faiblissant.

Pluie-Neige				
Iso 0 °C	3 400 m	3 300 m	3 300 m	3 100 m
Vent 2000 m	↘ 15 km/h	↘ 10 km/h	↘ 5 km/h	↓ 10 km/h
Vent 3000 m	↘ 30 km/h	↘ 25 km/h	↑ 10 km/h	→ 10 km/h

Épaisseur de neige hors-piste

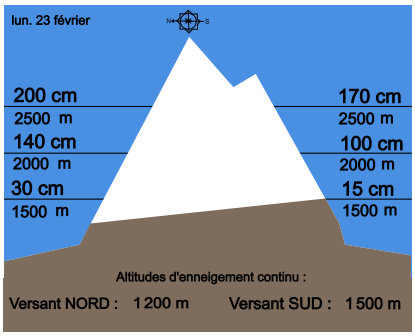

Précipitations à 1800 m

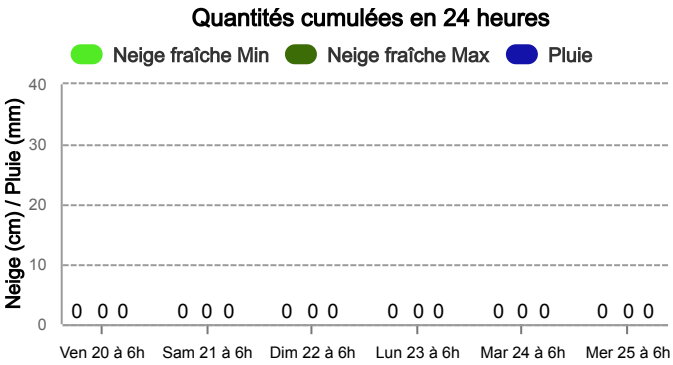

Tendance du mercredi 25 février

2

Indice de risque limité

Maintien d'un risque limité. Des plaques à vent sont toujours en place, mais deviennent rares. Des avalanches de neige humide se produisent au fil de l'ensoleillement.

Pour consulter la vigilance en cours, veuillez vous rendre sur le site https://vigilance.meteofrance.fr/fr

Météo-France - 73 avenue de Paris, 94165 Saint-Mandé cedex - Contact : contact@meteo.fr

Rédigé par Météo-France avec la contribution des observateurs du réseau nivo-météorologiques. Partenariat : ANMSM (Maires de Stations de Montagne), DSF (Domaines Skiables de France), ADSP (Directeurs de Pistes et de la Sécurité des Stations de Sports d'Hiver) et autres acteurs de la montagne.

Bulletin neige & avalanches par téléphone au
0 892 68 10 20 Service 0,35 € / min + prix appel

RÉPUBLIQUE FRANÇAISE
Liberté Égalité Fraternité

METEO FRANCE
À VOS CÔTÉS, DANS UN CLIMAT QUI CHANGE

Bulletin d'estimation du risque d'avalanche
(valable en dehors des pistes balisées et ouvertes)

MASSIF : Mercantour

Rédigé le lundi 23 février 2026 à 16h

Conditions nivo-météo des 7 derniers jours

	mar. 17/02				mer. 18/02				jeu. 19/02				ven. 20/02				sam. 21/02				dim. 22/02				lun. 23/02			
	03h	09h	15h	21h	03h	09h	15h	21h	03h	09h	15h	21h	03h	09h	15h	21h	03h	09h	15h	21h	03h	09h	15h	21h	03h	09h	15h	21h
Météo																												
Vent (km/h)	75	70	50	40	35	25	35	75	55	55	80	80	75	60	50	30	45	50	40	30	30	35	45	50	50	45	25	20
à 3000m																												
Vent (km/h)	60	50	20	20	15	15	20	40	30	35	35	45	45	40	15	15	15	20	15	20	15	15	20	15	25	20	15	15
à 2000m																												

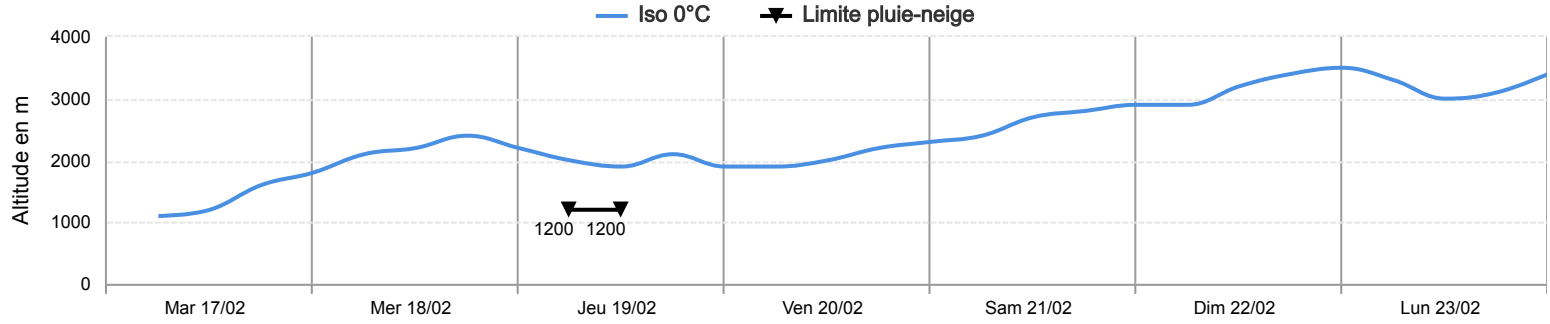

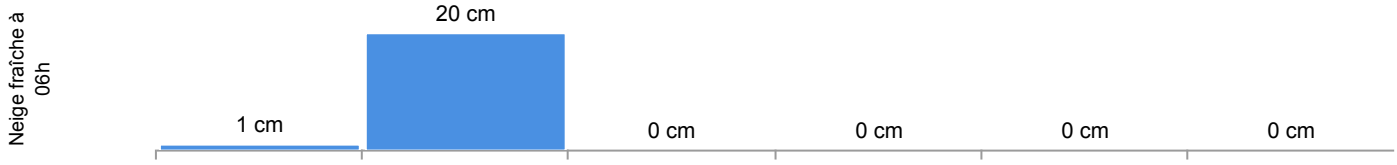

Risque d'avalanche	mar. 17/02	mer. 18/02	jeu. 19/02	ven. 20/02	sam. 21/02	dim. 22/02	lun. 23/02
	3	3	3	3	3	3	3

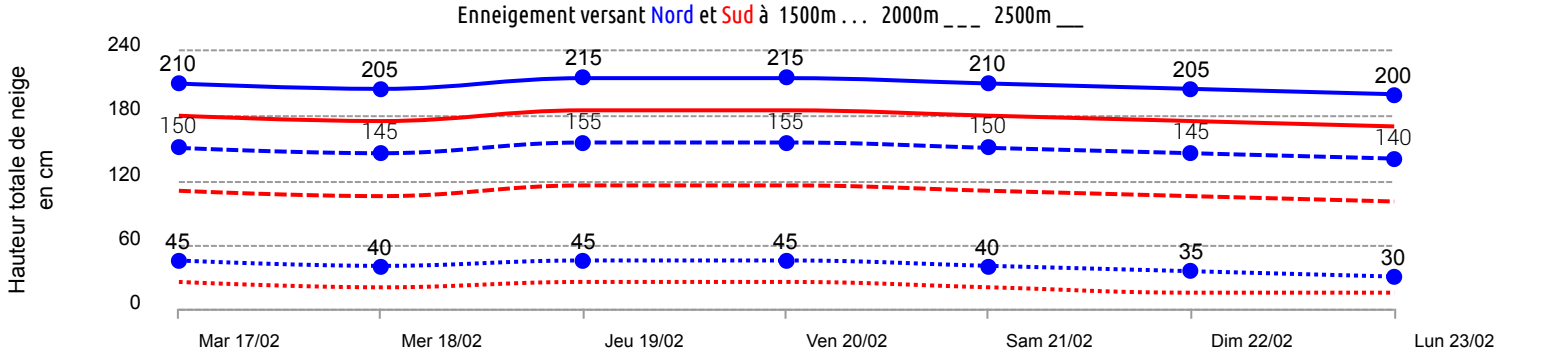

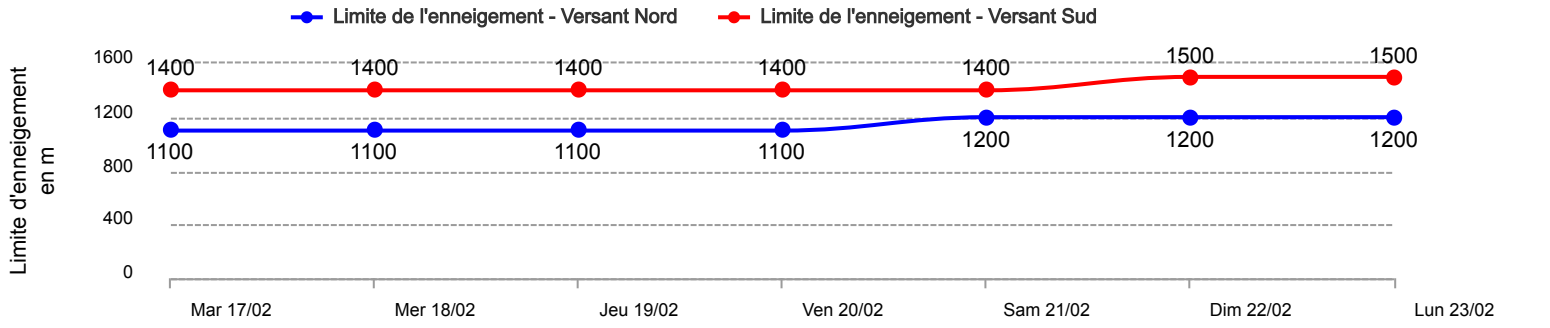

Pour consulter la vigilance en cours, veuillez vous rendre sur le site https://vigilance.meteofrance.fr/fr

Météo-France - 73 avenue de Paris, 94165 Saint-Mandé cedex - Contact : contact@meteo.fr

Rédigé par Météo-France avec la contribution des observateurs du réseau nivo-météorologiques. Partenariat : ANMSM (Maires de Stations de Montagne), DSF (Domaines Skiables de France), ADSP (Directeurs de Pistes et de la Sécurité des Stations de Sports d'Hiver) et autres acteurs de la montagne.

Bulletin neige & avalanches par téléphone au
0 892 68 10 20 Service 0,35 € / min + prix appel