Bulletin d'estimation du risque d'avalanche
(valable en dehors des pistes balisées et ouvertes)

MASSIF : Renoso Incudine

Rédigé le lundi 23 février 2026 à 16h

Estimation des risques pour le : MARDI 24 FÉVRIER

INSTABILITÉS PERSISTANT DANS LA NEIGE VENTÉE EN ALTITUDE, MANTEAU NEIGEUX PRINTANIER EN MOYENNE MONTAGNE

2

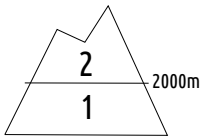

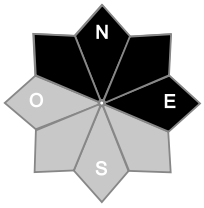

Au-dessus de 2000m indice de risque limité, plus bas indice faible.

Départs spontanés : Coulées de neige récente humidifiée au soleil

Déclenchements provoqués : Quelques plaques persistant dans la neige ventée en altitude, de plus en plus difficiles à solliciter

Indices de risque : 5 très fort - 4 fort - 3 marqué - 2 limité - 1 faible -- En noir : les pentes les plus dangereuses

Stabilité du manteau neigeux

Situation avalancheuse typique : neige ventée neige humide

Déclenchements provoqués : Quelques structures de plaques sont encore présentes dans la neige récente ventée, surtout dans les pentes orientées Nord à Est où persistent des couches fragiles. Ces plaques se stabilisent progressivement ; elles peuvent surtout être déclenchées par une forte surcharge, plus rarement au passage d'un seul skieur ou randonneur. Elles sont plus épaisses et plus dures en altitude, réparties de façon plus hétérogène, avec des accumulations localement importantes. En dessous de 2000 m, le manteau neigeux est généralement bien consolidé.
Départs spontanés : En journée, des coulées ou avalanches de taille petite à moyenne sont possibles par humidification superficielle du manteau neigeux, à plus forte raison dans les pentes raides ensoleillées.
Autres : Risque de glissade sur les nombreuses surfaces en neige dure ou glacée que l'on retrouve fréquemment, surtout aux abords des crêtes et sommets balayés par les vents.

Qualité de la neige

Qualification de l'enneigement : L'enneigement est excellent pour la saison au-dessus de 1600 m. À Ghisoni Capanelle, on relève 1 mètre de neige à la station, 2 mètres au-dessus de 1800 m et plus de 3 mètres dans les combes abritées.
Limite d'enneigement skiable : 1400 à 1500 m selon le versant.
État de la neige : En moyenne montagne et dans les secteurs peu ventés, le manteau neigeux devient printanier : la couche de neige récente est humide et ramollie par le soleil en journée, à peine croûtée la nuit. La neige récente est rarement restée poudreuse, seulement dans quelques combes ou couloirs bien abrités du vent et du soleil au-dessus de 2000 à 2200 m. Plus généralement, là où le vent a soufflé, la neige est dure et inégalement répartie, surtout lorsqu'on se rapproche des crêtes et sommets. Des corniches et accumulations parfois volumineuses sont en place. Aux abords des crêtes les plus ventées, dans les pentes ombragées ou à soleil rasant, les surfaces verglacées peuvent être généralisées.

Aperçu météo pour le mardi 24 février

	nuit	matin	après-midi	soir
			1400 m	1200 m

Grande douceur. Mer de nuages présente en dessous de 1200 à 1400 m.

Pluie-Neige				
Iso 0 °C	3 500 m	3 500 m	3 400 m	3 300 m
Vent 1500 m	40 km/h	30 km/h	20 km/h	5 km/h
Vent 2000 m	50 km/h	40 km/h	30 km/h	10 km/h

Épaisseur de neige hors-piste

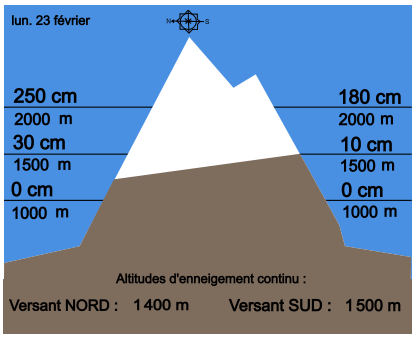

Précipitations à 1800 m

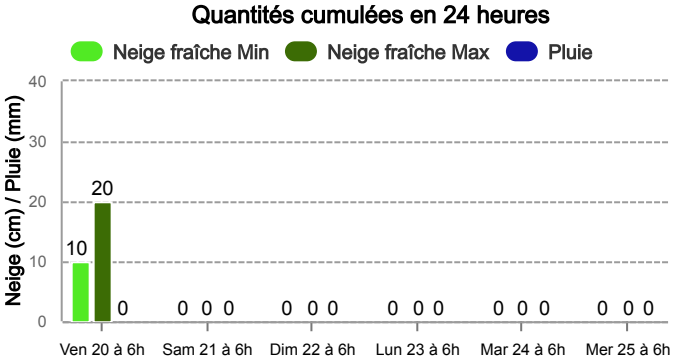

Tendance du mercredi 25 février

2 **Indice de risque limité**

Poursuite d'un temps sec et ensoleillé. La stabilisation des plaques se poursuit. Tendance du risque stationnaire ou en légère baisse.

Pour consulter la vigilance en cours, veuillez vous rendre sur le site https://vigilance.meteofrance.fr/fr

Météo-France - 73 avenue de Paris, 94165 Saint-Mandé cedex - Contact : contact@meteo.fr

Rédigé par Météo-France avec la contribution des observateurs du réseau nivo-météorologiques. Partenariat : ANMSM (Maires de Stations de Montagne), DSF (Domaines Skiables de France), ADSP (Directeurs de Pistes et de la Sécurité des Stations de Sports d'Hiver) et autres acteurs de la montagne.

Bulletin neige & avalanches par téléphone au 0 892 68 10 20 Service 0,35 € / min + prix appel

RÉPUBLIQUE FRANÇAISE
Liberté Égalité Fraternité

METEO FRANCE
À VOS CÔTÉS, DANS UN CLIMAT QUI CHANGE

Bulletin d'estimation du risque d'avalanche

(valable en dehors des pistes balisées et ouvertes)

MASSIF : Renoso Incudine

Rédigé le lundi 23 février 2026 à 16h

Conditions nivo-météo des 7 derniers jours

	mar. 17/02				mer. 18/02				jeu. 19/02				ven. 20/02				sam. 21/02				dim. 22/02				lun. 23/02			
	03h	09h	15h	21h	03h	09h	15h	21h	03h	09h	15h	21h	03h	09h	15h	21h	03h	09h	15h	21h	03h	09h	15h	21h	03h	09h	15h	21h
Météo																												
Vent (km/h)	110	70	60	50	45	55	45	40	60	70	80	100	80	60	60	40	40	40	30	20	20	20	40	60	70	70	70	60
à 2000m	↘	↘	↘	↘	↘	↘	→	↗	↗	→	→	→	↘	↓	↓	↓	↓	↓	↓	↓	↓	↓	↗	→	→	→	↘	↘
Vent (km/h)	100	60	60	50	50	55	50	40	65	80	95	95	90	40	40	25	20	15	15	15	15	10	30	50	60	60	60	50
à 1500m	↘	↘	↘	↘	→	↗	↗	→	↗	→	→	→	→	↓	↓	↙	↓	↘	↘	↓	↙	↓	↗	↗	→	→	↘	↘

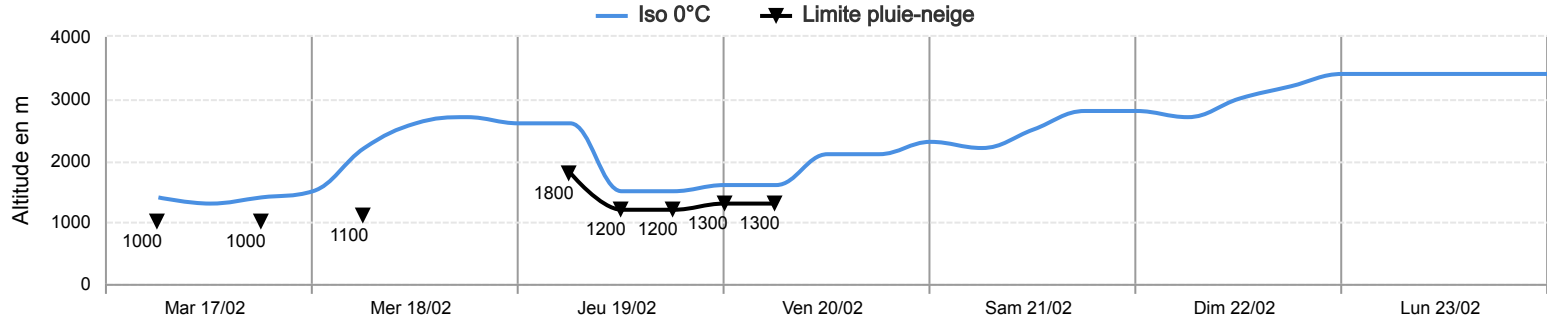

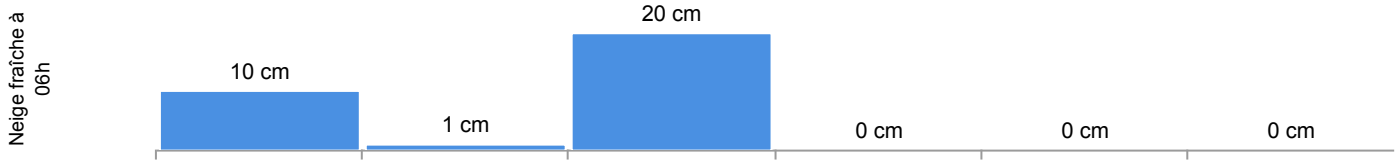

Risque d'avalanche	mar. 17/02	mer. 18/02	jeu. 19/02	ven. 20/02	sam. 21/02	dim. 22/02	lun. 23/02
	3	3	3	3	2	2	2

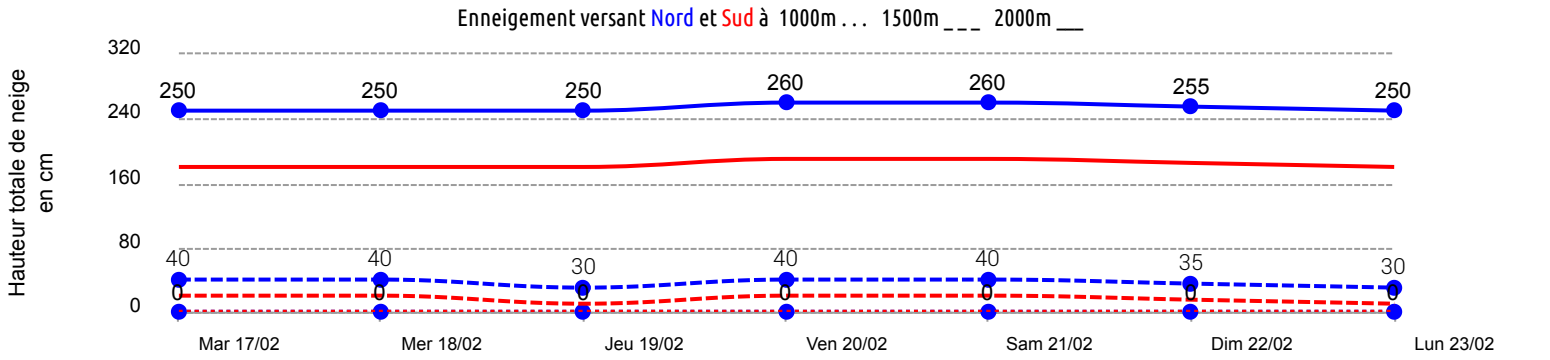

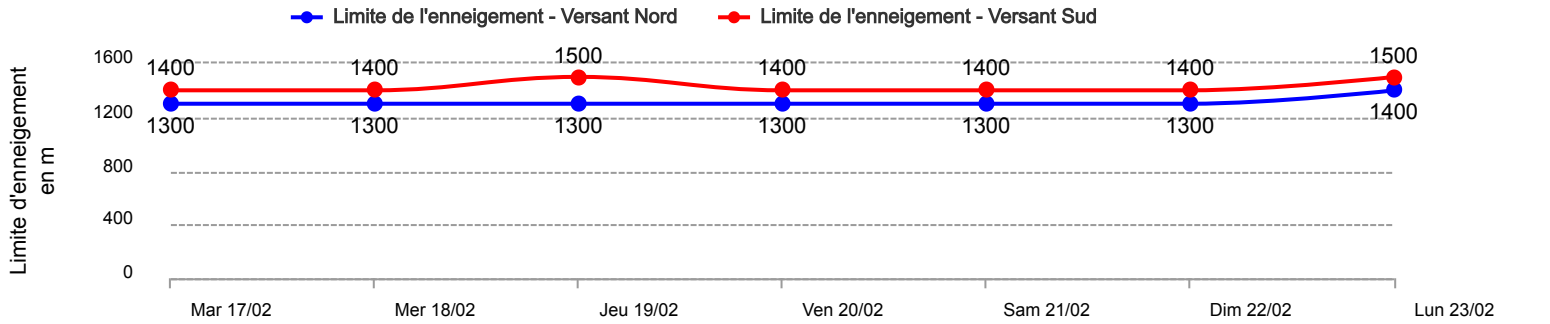

Pour consulter la vigilance en cours, veuillez vous rendre sur le site https://vigilance.meteofrance.fr/fr

Météo-France - 73 avenue de Paris, 94165 Saint-Mandé cedex - Contact : contact@meteo.fr

Rédigé par Météo-France avec la contribution des observateurs du réseau nivo-météorologiques. Partenariat : ANMSM (Maires de Stations de Montagne), DSF (Domaines Skiables de France), ADSP (Directeurs de Pistes et de la Sécurité des Stations de Sports d'Hiver) et autres acteurs de la montagne.

Bulletin neige & avalanches par téléphone au
0 892 68 10 20 Service 0,35 € / min + prix appel