Danger d'avalanche

actualisé le 23.2.2026, 17:00

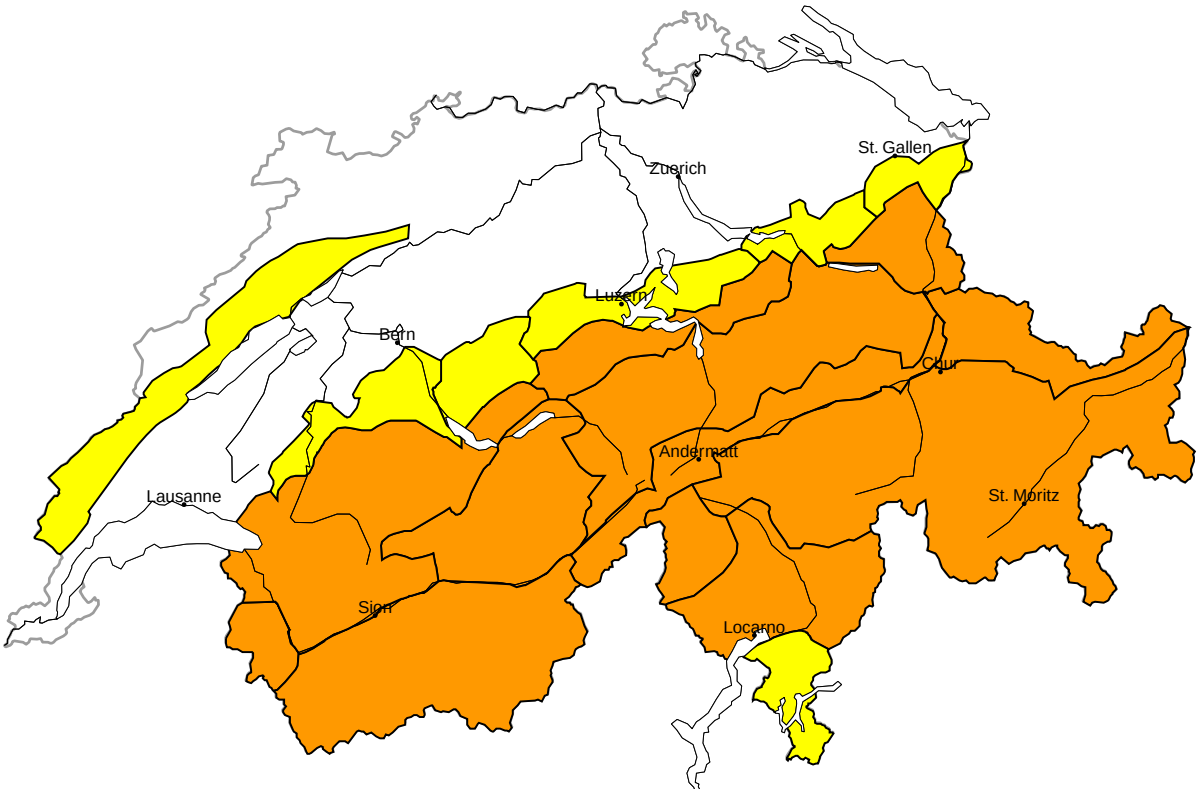

région A

Marqué (3+)

Neige fraîche, Couche fragile persistante

Endroits dangereux

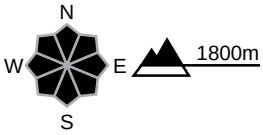

Description des dangers
La neige fraîche et la neige soufflée reposent sur une couche fragile de neige ancienne. Des avalanches peuvent en de nombreux endroits être déclenchées facilement. Elles peuvent se déclencher dans les couches proches du sol et atteindre une grande taille. Des bruits sourds ainsi que des avalanches récentes attirent l'attention sur le danger. Des déclenchements à distance sont à attendre.
Pour des randonnées et descentes hors-piste en dehors des pistes sécurisées les conditions sont critiques.

Limité (2)

Neige humide, Neige glissante

Endroits dangereux

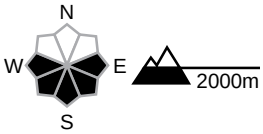

Description des dangers
Sur les pentes raides herbeuses des avalanches de glissement sont à attendre. Celles-ci peuvent atteindre une grande taille de manière isolée. Des glissements sur les talus sont possibles.

Degrés de danger 1 faible 2 limité 3 marqué 4 fort 5 très fort

région B

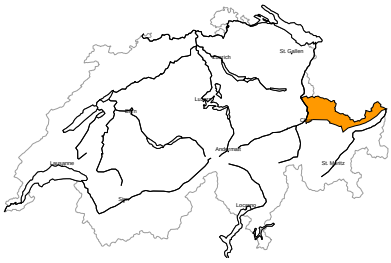

Marqué (3+)

Neige fraîche, Couche fragile persistante

Endroits dangereux

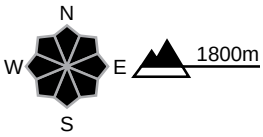

Description des dangers
La neige fraîche et la neige soufflée reposent sur une couche fragile de neige ancienne. Des avalanches peuvent en de nombreux endroits être déclenchées facilement. Elles peuvent se déclencher dans les couches proches du sol et atteindre une grande taille. Des bruits sourds ainsi que des avalanches récentes attirent l'attention sur le danger. Des déclenchements à distance sont à attendre.
Pour des randonnées et descentes hors-piste en dehors des pistes sécurisées les conditions sont critiques.

Marqué (3)

Neige glissante

Endroits dangereux

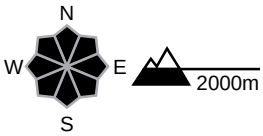

Description des dangers
Avec la pluie de plus en plus nombreuses avalanches de glissement et coulées humides sont à attendre spécialement sur les pentes raides herbeuses. Celles-ci peuvent aussi atteindre une grande taille. Il faut s'attendre à des glissements sur les talus.

région C

Marqué (3+)

Neige fraîche, Couche fragile persistante

Endroits dangereux

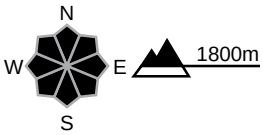

Description des dangers
La neige fraîche et la neige soufflée reposent sur une couche fragile de neige ancienne. Des avalanches peuvent en de nombreux endroits être déclenchées facilement. Elles peuvent se déclencher dans les couches proches du sol et atteindre une grande taille. Des bruits sourds ainsi que des avalanches récentes attirent l'attention sur le danger. Des déclenchements à distance sont à attendre.
Pour des randonnées et descentes hors-piste en dehors des pistes sécurisées les conditions sont critiques.

région D

Marqué (3=)

Neige fraîche, Couche fragile persistante

Endroits dangereux

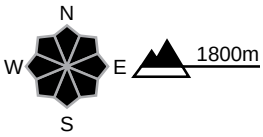

Description des dangers
Des amateurs de sports d'hiver seuls peuvent déclencher des avalanches. Celles-ci peuvent se déclencher dans les couches profondes du manteau neigeux atteindre une très grande taille de manière isolée. Les endroits dangereux sont plutôt rares mais à peine identifiables. Prudence dans les endroits plutôt faiblement enneigés et aux transitions entre les endroits peu enneigés et les endroits très enneigés, notamment à l'entrée des combes et des couloirs.
Pour des randonnées et descentes hors-piste les conditions sont délicates.

Marqué (3)

Neige humide, Neige glissante

Endroits dangereux

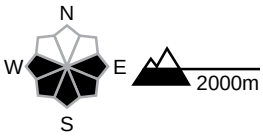

Description des dangers
Avec le réchauffement diurne et le rayonnement solaire des avalanches de neige mouillée et de glissement de plus en plus nombreuses sont à attendre, également de grande taille. Les zones présentant des fissures de glissement doivent être évitées.

région E

Marqué (3=)

Neige fraîche, Couche fragile persistante

Endroits dangereux

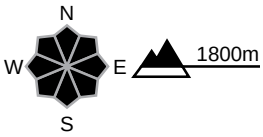

Description des dangers
Des amateurs de sports d'hiver seuls peuvent déclencher des avalanches. Celles-ci peuvent se déclencher dans les couches profondes du manteau neigeux atteindre une très grande taille de manière isolée. Les endroits dangereux sont plutôt rares mais à peine identifiables. Prudence dans les endroits plutôt faiblement enneigés et aux transitions entre les endroits peu enneigés et les endroits très enneigés, notamment à l'entrée des combes et des couloirs.
Pour des randonnées et descentes hors-piste les conditions sont délicates.

Limité (2)

Neige humide, Neige glissante

Endroits dangereux

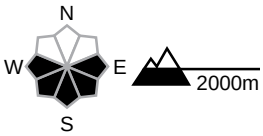

Description des dangers
Sur les pentes raides herbeuses des avalanches de glissement sont à attendre. Celles-ci peuvent atteindre une grande taille de manière isolée. Des glissements sur les talus sont possibles.

région F

Marqué (3=)

Couche fragile persistante

Endroits dangereux

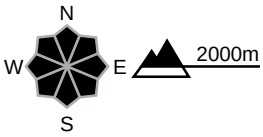

Description des dangers
La neige fraîche et la neige soufflée des derniers jours reposent sur une couche fragile de neige ancienne. Des amateurs de sports d'hiver seuls peuvent facilement déclencher des avalanches. Celles-ci peuvent se déclencher dans les couches profondes du manteau neigeux et atteindre une grande taille. Des déclenchements à distance sont possibles. Prudence dans les endroits plutôt faiblement enneigés comme aux transitions entre les endroits peu enneigés et les endroits très enneigés.
Les randonnées et descentes hors-piste demandent de l' expérience dans l'évaluation du danger d'avalanche et de la retenue.

Marqué (3)

Neige humide, Neige glissante

Endroits dangereux

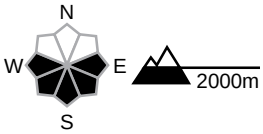

Description des dangers
Avec le réchauffement diurne et le rayonnement solaire des avalanches de neige mouillée et de glissement de plus en plus nombreuses sont à attendre, également de grande taille. Les zones présentant des fissures de glissement doivent être évitées.

région G

Marqué (3=)

Neige fraîche, Couche fragile persistante

Endroits dangereux

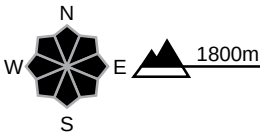

Description des dangers
Des amateurs de sports d'hiver seuls peuvent déclencher des avalanches. Celles-ci peuvent se déclencher dans les couches profondes du manteau neigeux atteindre une très grande taille de manière isolée. Les endroits dangereux sont plutôt rares mais à peine identifiables. Prudence dans les endroits plutôt faiblement enneigés et aux transitions entre les endroits peu enneigés et les endroits très enneigés, notamment à l'entrée des combes et des couloirs.
Pour des randonnées et descentes hors-piste les conditions sont délicates.

Marqué (3)

Neige glissante

Endroits dangereux

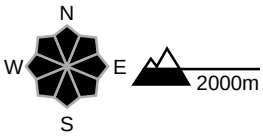

Description des dangers
Avec la pluie de plus en plus nombreuses avalanches de glissement et coulées humides sont à attendre spécialement sur les pentes raides herbeuses. Celles-ci peuvent aussi atteindre une grande taille. Il faut s'attendre à des glissements sur les talus.

région H

Marqué (3=)

Couche fragile persistante

Endroits dangereux

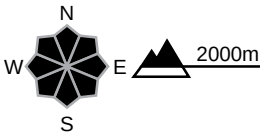

Description des dangers
La neige fraîche et la neige soufflée des derniers jours reposent sur une couche fragile de neige ancienne. Des amateurs de sports d'hiver seuls peuvent facilement déclencher des avalanches. Celles-ci peuvent se déclencher dans les couches profondes du manteau neigeux et atteindre une grande taille. Des déclenchements à distance sont possibles. Prudence dans les endroits plutôt faiblement enneigés comme aux transitions entre les endroits peu enneigés et les endroits très enneigés.
Les randonnées et descentes hors-piste demandent de l' expérience dans l'évaluation du danger d'avalanche et de la retenue.

Limité (2)

Neige humide, Neige glissante

Endroits dangereux

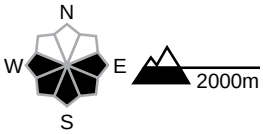

Description des dangers
Sur les pentes raides herbeuses des avalanches de glissement sont à attendre. Celles-ci peuvent atteindre une grande taille de manière isolée. Des glissements sur les talus sont possibles.

région I

Marqué (3=)

Couche fragile persistante

Endroits dangereux

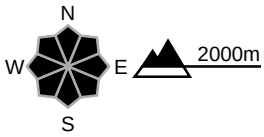

Description des dangers
Dans le manteau neigeux des couches fragiles importantes sont présentes. Des amateurs de sports d'hiver même seuls peuvent déclencher des avalanches. Celles-ci peuvent se déclencher dans les couches profondes du manteau neigeux et atteindre une grande taille. Des bruits sourds peuvent attirer l'attention sur le danger.
Les randonnées et descentes hors-piste demandent une expérience dans l'évaluation du danger d'avalanche.

Limité (2)

Neige humide, Neige glissante

Endroits dangereux

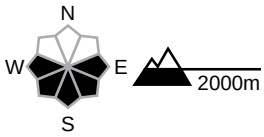

Description des dangers
Sur les pentes raides herbeuses des avalanches de glissement sont à attendre. Celles-ci peuvent atteindre une grande taille de manière isolée. Des glissements sur les talus sont possibles.

région J

Marqué (3=)

Couche fragile persistante

Endroits dangereux

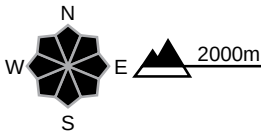

Description des dangers
Dans le manteau neigeux des couches fragiles importantes sont présentes. Des amateurs de sports d'hiver même seuls peuvent déclencher des avalanches. Celles-ci peuvent se déclencher dans les couches profondes du manteau neigeux et atteindre une grande taille. Des bruits sourds peuvent attirer l'attention sur le danger.
Les randonnées et descentes hors-piste demandent une expérience dans l'évaluation du danger d'avalanche.

région K

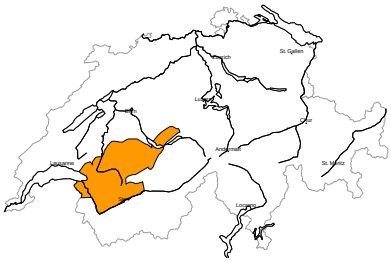

Marqué (3-)

Couche fragile persistante

Endroits dangereux

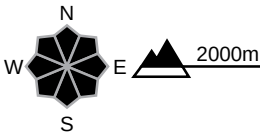

Description des dangers
Des amateurs de sports d'hiver seuls peuvent déclencher des avalanches. Celles-ci peuvent se déclencher dans les couches profondes du manteau neigeux atteindre une très grande taille de manière isolée. Les endroits dangereux sont rares mais à peine identifiables. Prudence dans les endroits plutôt faiblement enneigés comme aux transitions entre les endroits peu enneigés et les endroits très enneigés. Les randonnées et descentes hors-piste demandent un choix très prudent d'itinéraires.

Marqué (3)

Neige humide, Neige glissante

Endroits dangereux

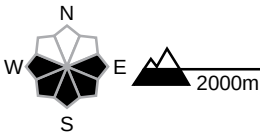

Description des dangers
Avec le réchauffement diurne et le rayonnement solaire des avalanches de neige mouillée et de glissement de plus en plus nombreuses sont à attendre, également de grande taille. Les zones présentant des fissures de glissement doivent être évitées.

région L

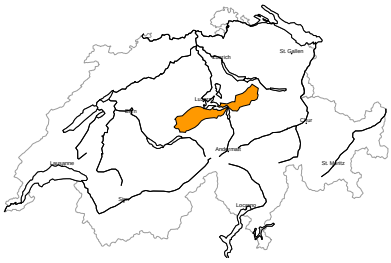

Marqué (3-)

Couche fragile persistante

Endroits dangereux

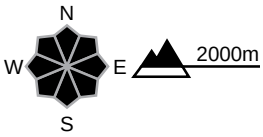

Description des dangers
Des amateurs de sports d'hiver seuls peuvent déclencher des avalanches. Celles-ci peuvent se déclencher dans les couches profondes du manteau neigeux atteindre une très grande taille de manière isolée. Les endroits dangereux sont rares mais à peine identifiables. Prudence dans les endroits plutôt faiblement enneigés comme aux transitions entre les endroits peu enneigés et les endroits très enneigés. Les randonnées et descentes hors-piste demandent un choix très prudent d'itinéraires.

Limité (2)

Neige humide, Neige glissante

Endroits dangereux

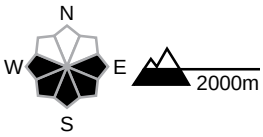

Description des dangers
Sur les pentes raides herbeuses des avalanches de glissement sont à attendre. Celles-ci peuvent atteindre une grande taille de manière isolée. Des glissements sur les talus sont possibles.

région M

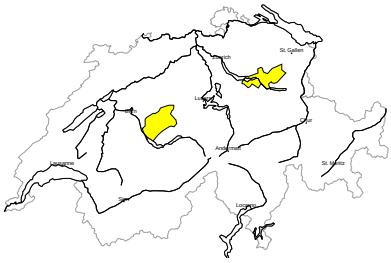

Limité (2=)

Aucune situation avalancheuse typique prédominante

Endroits dangereux

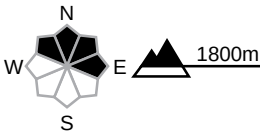

Description des dangers
La neige fraîche et la neige soufflée des derniers jours sont partiellement encore fragiles en altitude. Des amateurs de sports d'hiver peuvent par endroits déclencher des avalanches, pouvant atteindre une taille moyenne.
Un choix prudent des itinéraires est recommandé.

Limité (2)

Neige glissante

Endroits dangereux

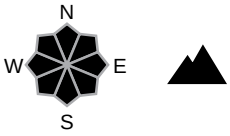

Description des dangers
Sur les pentes raides herbeuses des avalanches de glissement sont à attendre, surtout de taille moyenne. Des glissements sur les talus sont possibles.

région N — Limité (2=)

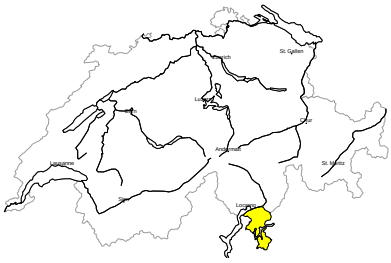

Aucune situation avalancheuse typique prédominante

Endroits dangereux

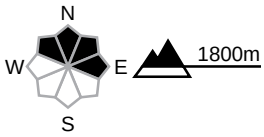

Description des dangers
La neige fraîche et la neige soufflée des derniers jours sont partiellement encore fragiles en altitude. Des amateurs de sports d'hiver peuvent par endroits déclencher des avalanches, pouvant atteindre une taille moyenne.
Un choix prudent des itinéraires est recommandé.

région O — Limité (2)

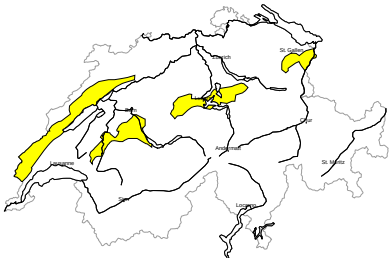

Neige glissante

Endroits dangereux

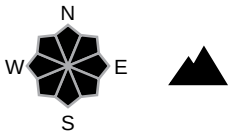

Description des dangers
Sur les pentes raides herbeuses des avalanches de glissement sont à attendre, surtout de taille moyenne. Des glissements sur les talus sont possibles.

Manteau neigeux et météo

actualisé le 23.2.2026, 17:00

Manteau neigeux

Au nord d'une ligne Rhône-Rhin et dans la partie la plus occidentale du Bas-Valais, de 2 à 3,5 m de neige sont tombés au cours des deux dernières semaines. Les couches fragiles du manteau neigeux ancien sont ainsi recouvertes d'une épaisse couche et leur décrochement ne peut être provoqué par des personnes que par endroit. Les avalanches peuvent toutefois devenir très grandes.
Au sud d'une ligne Rhône-Rhin, le problème de la neige ancienne reste marqué. Bien que la neige n'y soit pas aussi abondante, les avalanches peuvent tout de même être grandes, voire très grandes. Dans les Grisons, les endroits dangereux sont toujours aussi fréquents, même déjà dans la zone de la limite de la forêt. Des bruits sourds et des déclenchements à distance sont typiques. Dans le sud du Valais, les couches fragiles marquées dans la partie inférieure du manteau neigeux sont généralement recouvertes d'une couche un peu plus épaisse. Les endroits dangereux où des avalanches peuvent être déclenchées dans la neige ancienne fragile sont donc un peu plus rares et se situent surtout dans les zones plutôt faiblement enneigées.
Avec les températures douces, il faut s'attendre à des avalanches de glissement de taille moyenne ou grande sur les pentes herbeuses raides en dessous de 2000 m environ.

Rétrospective météo de ce lundi

Dans le nord, peu de précipitations sont tombées pendant la nuit, au-dessus d'environ 1600 m sous forme de neige. Pendant la journée, le ciel était très nuageux, mais il faisait essentiellement sec. Dans les régions intra-alpines, le temps était en partie ensoleillé, et il faisait beau dans le sud.

Neige fraîche
Pendant la nuit de dimanche à lundi, il est tombé :
- Le long du centre et de l'est des Préalpes : environ 10 cm
- Ailleurs : moins de neige fraîche ; dans le sud, temps sec

Température
À la mi-journée, à 2000 m, entre +2°C dans le nord et un +5°C doux dans le sud

Vent
Vent modéré à fort de secteur ouest à nord-ouest

Prévisions météorologiques jusqu'à mardi

Dans l'ouest et le sud, le temps sera ensoleillé. Dans l'est, des précipitations tomberont, au-dessus de 1900 m environ sous forme de neige.

Neige fraîche
De lundi à la fin des précipitations, il tombera :
- Prättigau, Silvretta et Samnaun : de 10 à 20 cm
- Centre et est du versant nord des Alpes, autres régions du nord des Grisons et de la Basse-Engadine : jusqu'à 10 cm

Ces quantités de précipitations sont toutefois encore incertaines.

Température
À la mi-journée à 2000 m, entre un +5 °C doux dans le sud-ouest et +1 °C dans le nord-est

Vent
Dans le nord, encore modéré à fort de secteur ouest pendant la nuit, faible pendant la journée
Sur la crête principale des Alpes et au sud de celle-ci, pendant la nuit, vent parfois tempétueux en altitude, sinon modéré à fort de secteur nord-ouest

Tendance jusqu’à jeudi

Les nuits claires seront suivies de journées ensoleillées. Avec une isotherme zéro degré à 3100 m mercredi et 2700 m jeudi, le temps sera particulièrement doux. Le vent, d’abord faible, deviendra modéré jeudi en cours de journée et soufflera de secteur ouest.
Le danger d’avalanches sèches diminuera, mais seulement très lentement dans le sud du Valais, au Tessin et dans les Grisons en raison de la présence de couches fragiles marquées. Il faut toujours s’attendre à des avalanches de glissement, y compris à de grandes avalanches dans l’ouest et le nord.