Bollettino valanghe sino a martedì, 24. febbraio 2026

Pericolo valanghe

aggiornato al 23.2.2026, 17:00

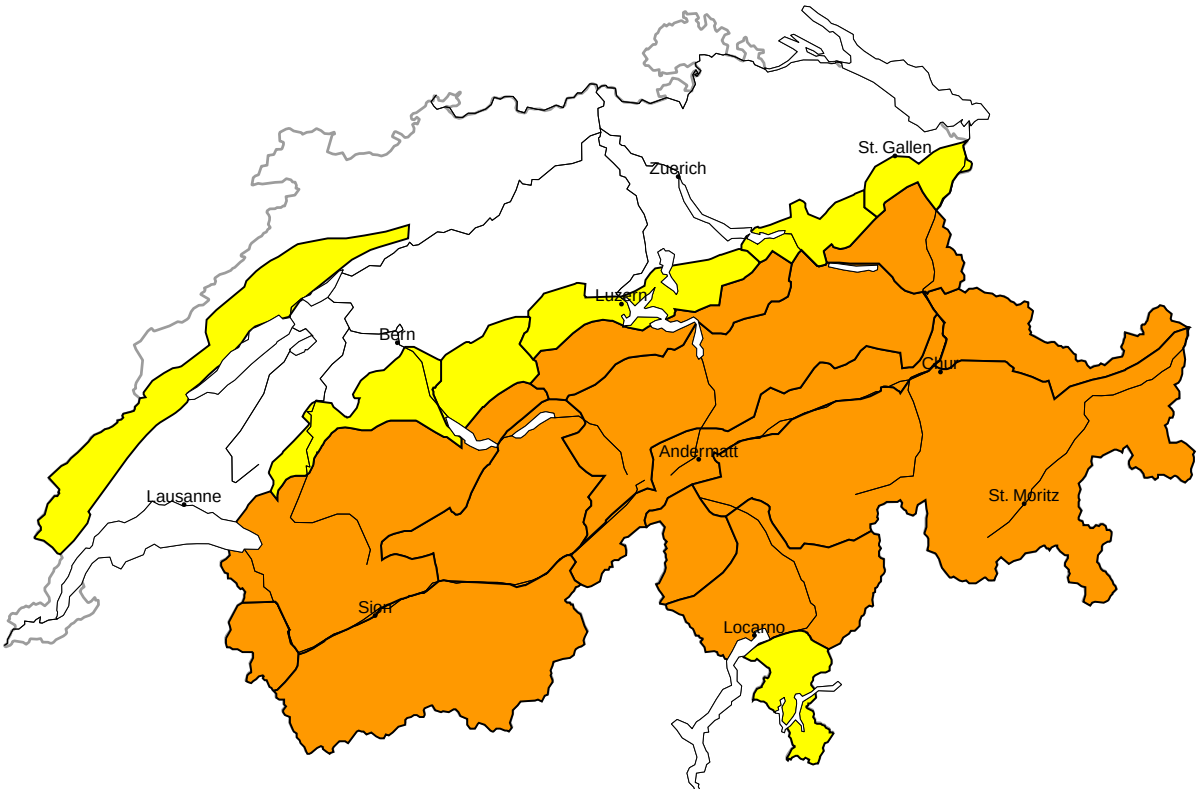

regione A

Marcato (3+)

Neve fresca, Strati deboli persistenti

Punti pericolosi

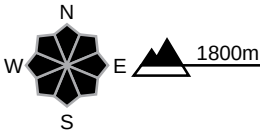

Descrizione del pericolo

La neve fresca e la neve ventata ricoprono un debole manto di neve vecchia. Le valanghe possono in molti punti distaccarsi facilmente. Esse possono staccarsi negli strati basali del manto e raggiungere grandi dimensioni. I rumori di "whum" così come nuove valanghe sono segnali da ricondurre a questo pericolo. Si prevedono distacchi a distanza.
Per le escursioni e le discese fuori pista al di fuori delle piste assicurate, le condizioni sono critiche.

Moderato (2)

Neve bagnata, Valanghe di slittamento

Punti pericolosi

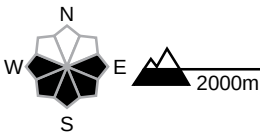

Descrizione del pericolo

Sui pendii erbosi ripidi, sono previste valanghe per scivolamento di neve. Queste possono raggiungere grandi dimensioni a livello isolato. Sono possibili colate dalle scarpate.

Scala del pericolo 1 debole | 2 moderato | 3 marcato | 4 forte | 5 molto forte

regione B

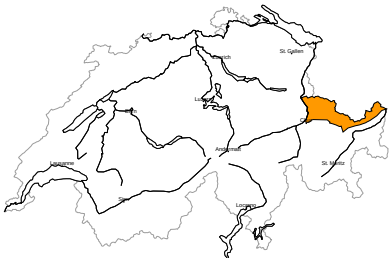

Marcato (3+)

Neve fresca, Strati deboli persistenti

Punti pericolosi

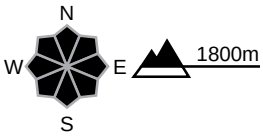

Descrizione del pericolo
La neve fresca e la neve ventata ricoprono un debole manto di neve vecchia. Le valanghe possono in molti punti distaccarsi facilmente. Esse possono staccarsi negli strati basali del manto e raggiungere grandi dimensioni. I rumori di "whum" così come nuove valanghe sono segnali da ricondurre a questo pericolo. Si prevedono distacchi a distanza.
Per le escursioni e le discese fuori pista al di fuori delle piste assicurate, le condizioni sono critiche.

Marcato (3)

Valanghe di slittamento

Punti pericolosi

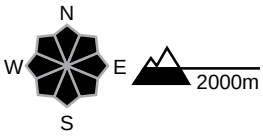

Descrizione del pericolo
Con la pioggia, principalmente sui pendii erbosi ripidi sono previste sempre più numerose valanghe per scivolamento di neve e colate umide. Queste possono anche raggiungere grandi dimensioni. Si prevedono colate dalle scarpate.

regione C

Marcato (3+)

Neve fresca, Strati deboli persistenti

Punti pericolosi

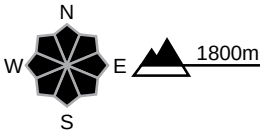

Descrizione del pericolo
La neve fresca e la neve ventata ricoprono un debole manto di neve vecchia. Le valanghe possono in molti punti distaccarsi facilmente. Esse possono staccarsi negli strati basali del manto e raggiungere grandi dimensioni. I rumori di "whum" così come nuove valanghe sono segnali da ricondurre a questo pericolo. Si prevedono distacchi a distanza.
Per le escursioni e le discese fuori pista al di fuori delle piste assicurate, le condizioni sono critiche.

regione D

Marcato (3=)

Neve fresca, Strati deboli persistenti

Punti pericolosi

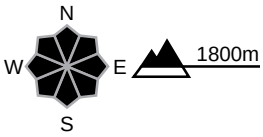

Descrizione del pericolo
Un singolo appassionato di sport invernali può provocare il distacco di valanghe. Queste possono distaccarsi negli strati più profondi raggiungere dimensioni molto grandi a livello isolato. I punti pericolosi sono piuttosto rari ma appena individuabili. Attenzione nelle zone scarsamente innevate e nelle zone di passaggio da poca a molta neve come p.es. all'ingresso di conche e canaloni.
Per le escursioni e le discese fuori pista, le condizioni sono insidiose.

Marcato (3)

Neve bagnata, Valanghe di slittamento

Punti pericolosi

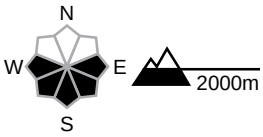

Descrizione del pericolo
Con il rialzo termico e l'irradiazione solare diurni, sono previste sempre più numerose valanghe bagnate e per scivolamento di neve, anche di grandi dimensioni. Evitare le zone con rotture da scivolamento.

regione E

Marcato (3=)

Neve fresca, Strati deboli persistenti

Punti pericolosi

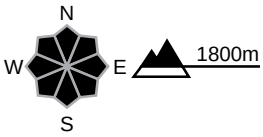

Descrizione del pericolo
Un singolo appassionato di sport invernali può provocare il distacco di valanghe. Queste possono distaccarsi negli strati più profondi raggiungere dimensioni molto grandi a livello isolato. I punti pericolosi sono piuttosto rari ma appena individuabili. Attenzione nelle zone scarsamente innevate e nelle zone di passaggio da poca a molta neve come p.es. all'ingresso di conche e canaloni.
Per le escursioni e le discese fuori pista, le condizioni sono insidiose.

Moderato (2)

Neve bagnata, Valanghe di slittamento

Punti pericolosi

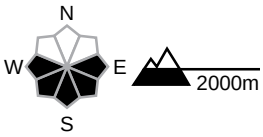

Descrizione del pericolo
Sui pendii erbosi ripidi, sono previste valanghe per scivolamento di neve. Queste possono raggiungere grandi dimensioni a livello isolato. Sono possibili colate dalle scarpate.

regione F

Marcato (3=)

Strati deboli persistenti

Punti pericolosi

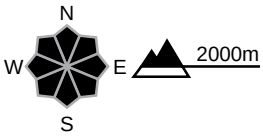

Descrizione del pericolo
La neve fresca e la neve ventata degli ultimi giorni ricoprono un debole manto di neve vecchia. Un singolo appassionato di sport invernali può facilmente provocare il distacco di valanghe. Queste possono distaccarsi negli strati più profondi e raggiungere grandi dimensioni. Sono possibili distacchi a distanza. Attenzione nelle zone scarsamente innevate, come pure nelle zone di passaggio da poca a molta neve. Le escursioni e le discese fuori pista richiedono esperienza nella valutazione del pericolo di valanghe e attenzione.

Marcato (3)

Neve bagnata, Valanghe di slittamento

Punti pericolosi

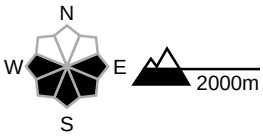

Descrizione del pericolo
Con il rialzo termico e l'irradiazione solare diurni, sono previste sempre più numerose valanghe bagnate e per scivolamento di neve, anche di grandi dimensioni. Evitare le zone con rotture da scivolamento.

regione G

Marcato (3=)

Neve fresca, Strati deboli persistenti

Punti pericolosi

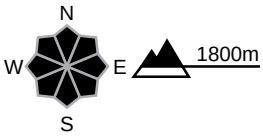

Descrizione del pericolo
Un singolo appassionato di sport invernali può provocare il distacco di valanghe. Queste possono distaccarsi negli strati più profondi raggiungere dimensioni molto grandi a livello isolato. I punti pericolosi sono piuttosto rari ma appena individuabili. Attenzione nelle zone scarsamente innevate e nelle zone di passaggio da poca a molta neve come p.es. all'ingresso di conche e canaloni.
Per le escursioni e le discese fuori pista, le condizioni sono insidiose.

Marcato (3)

Valanghe di slittamento

Punti pericolosi

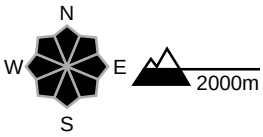

Descrizione del pericolo
Con la pioggia, principalmente sui pendii erbosi ripidi sono previste sempre più numerose valanghe per scivolamento di neve e colate umide. Queste possono anche raggiungere grandi dimensioni. Si prevedono colate dalle scarpate.

Bollettino valanghe sino a martedì, 24. febbraio 2026

regione H

Marcato (3=)

Strati deboli persistenti

Punti pericolosi

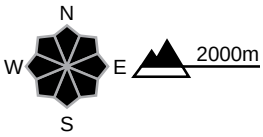

Descrizione del pericolo
La neve fresca e la neve ventata degli ultimi giorni ricoprono un debole manto di neve vecchia. Un singolo appassionato di sport invernali può facilmente provocare il distacco di valanghe. Queste possono distaccarsi negli strati più profondi e raggiungere grandi dimensioni. Sono possibili distacchi a distanza. Attenzione nelle zone scarsamente innevate, come pure nelle zone di passaggio da poca a molta neve. Le escursioni e le discese fuori pista richiedono esperienza nella valutazione del pericolo di valanghe e attenzione.

Moderato (2)

Neve bagnata, Valanghe di slittamento

Punti pericolosi

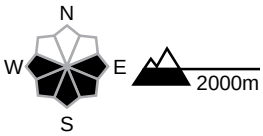

Descrizione del pericolo
Sui pendii erbosi ripidi, sono previste valanghe per scivolamento di neve. Queste possono raggiungere grandi dimensioni a livello isolato. Sono possibili colate dalle scarpate.

regione I

Marcato (3=)

Strati deboli persistenti

Punti pericolosi

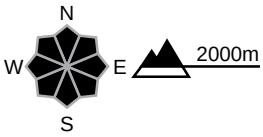

Descrizione del pericolo
All'interno del manto nevoso si trovano pronunciati strati fragili. Già un singolo appassionato di sport invernali può provocare il distacco di valanghe. Queste possono distaccarsi negli strati più profondi e raggiungere grandi dimensioni. I rumori di "whum" sono possibili segnali di pericolo.
Le escursioni e le discese fuori pista richiedono esperienza nella valutazione del pericolo di valanghe.

Moderato (2)

Neve bagnata, Valanghe di slittamento

Punti pericolosi

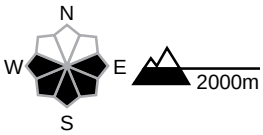

Descrizione del pericolo
Sui pendii erbosi ripidi, sono previste valanghe per scivolamento di neve. Queste possono raggiungere grandi dimensioni a livello isolato. Sono possibili colate dalle scarpate.

regione J

Marcato (3=)

Strati deboli persistenti

Punti pericolosi

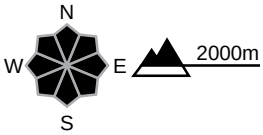

Descrizione del pericolo
All'interno del manto nevoso si trovano pronunciati strati fragili. Già un singolo appassionato di sport invernali può provocare il distacco di valanghe. Queste possono distaccarsi negli strati più profondi e raggiungere grandi dimensioni. I rumori di "whum" sono possibili segnali di pericolo.
Le escursioni e le discese fuori pista richiedono esperienza nella valutazione del pericolo di valanghe.

regione K

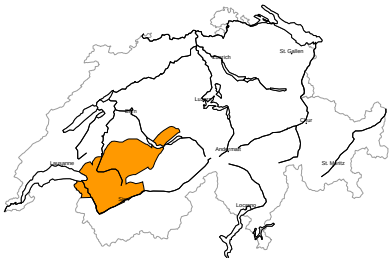

Marcato (3-)

Strati deboli persistenti

Punti pericolosi

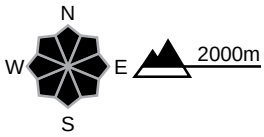

Descrizione del pericolo
Un singolo appassionato di sport invernali può provocare il distacco di valanghe. Queste possono distaccarsi negli strati più profondi raggiungere dimensioni molto grandi a livello isolato. I punti pericolosi sono rari ma appena individuabili. Attenzione nelle zone scarsamente innevate, come pure nelle zone di passaggio da poca a molta neve.
Le escursioni e le discese fuori pista richiedono una prudente scelta dell'itinerario.

Marcato (3)

Neve bagnata, Valanghe di slittamento

Punti pericolosi

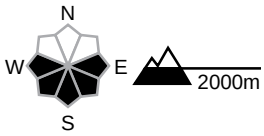

Descrizione del pericolo
Con il rialzo termico e l'irradiazione solare diurni, sono previste sempre più numerose valanghe bagnate e per scivolamento di neve, anche di grandi dimensioni.
Evitare le zone con rotture da scivolamento.

regione L

Marcato (3-)

Strati deboli persistenti

Punti pericolosi

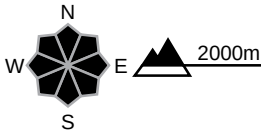

Descrizione del pericolo
Un singolo appassionato di sport invernali può provocare il distacco di valanghe. Queste possono distaccarsi negli strati più profondi raggiungere dimensioni molto grandi a livello isolato. I punti pericolosi sono rari ma appena individuabili. Attenzione nelle zone scarsamente innevate, come pure nelle zone di passaggio da poca a molta neve.
Le escursioni e le discese fuori pista richiedono una prudente scelta dell'itinerario.

Moderato (2)

Neve bagnata, Valanghe di slittamento

Punti pericolosi

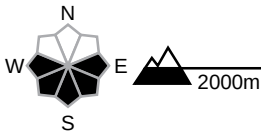

Descrizione del pericolo
Sui pendii erbosi ripidi, sono previste valanghe per scivolamento di neve. Queste possono raggiungere grandi dimensioni a livello isolato. Sono possibili colate dalle scarpate.

Bollettino valanghe sino a martedì, 24. febbraio 2026

regione M

Moderato (2=)

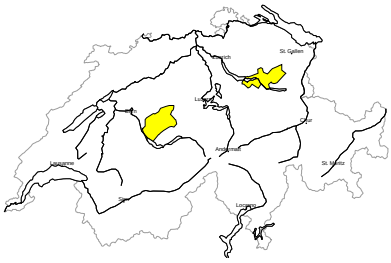

Nessun problema valanghivo evidente

Punti pericolosi

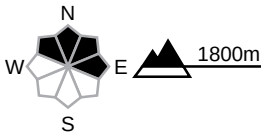

Descrizione del pericolo
La neve fresca e la neve ventata degli ultimi giorni sono in parte ancora instabili in quota. Un appassionato di sport invernali può in alcuni punti provocare il distacco di valanghe, anche di medie dimensioni.
Si raccomanda una prudente scelta dell'itinerario.

Moderato (2)

Valanghe di slittamento

Punti pericolosi

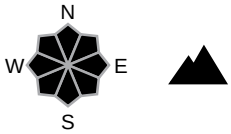

Descrizione del pericolo
Sui pendii erbosi ripidi, sono previste valanghe per scivolamento di neve, soprattutto di medie dimensioni.
Sono possibili colate dalle scarpate.

regione N

Moderato (2=)

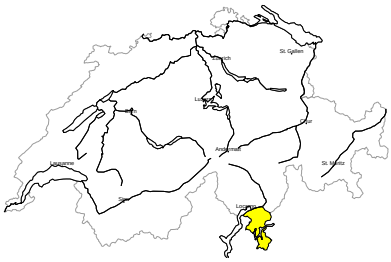

Nessun problema valanghivo evidente

Punti pericolosi

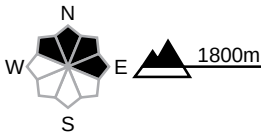

Descrizione del pericolo
La neve fresca e la neve ventata degli ultimi giorni sono in parte ancora instabili in quota. Un appassionato di sport invernali può in alcuni punti provocare il distacco di valanghe, anche di medie dimensioni.
Si raccomanda una prudente scelta dell'itinerario.

regione O

Moderato (2)

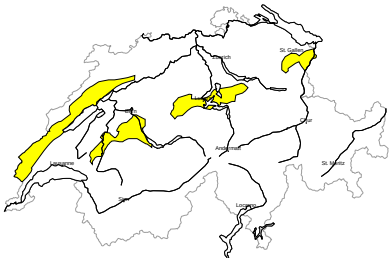

Valanghe di slittamento

Punti pericolosi

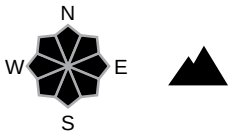

Descrizione del pericolo
Sui pendii erbosi ripidi, sono previste valanghe per scivolamento di neve, soprattutto di medie dimensioni.
Sono possibili colate dalle scarpate.

Manto nevoso e meteo

aggiornato al 23.2.2026, 17:00

Manto nevoso

Nelle ultime due settimane, a nord di una linea Rodano-Reno e nel Basso Vallese occidentale estremo sono caduti dai 2 ai 3,5 m di neve. Gli strati fragili presenti nel manto di neve vecchia sono stati così abbondantemente ricoperti e solo in alcuni punti possono ancora subire un distacco in seguito al passaggio di persone. Le valanghe possono però raggiungere dimensioni molto grandi.
A sud di una linea Rodano-Reno, il problema di neve vecchia è ancora pronunciato. Nonostante qui non sia presente molta neve, le valanghe possono comunque raggiungere dimensioni grandi o addirittura molto grandi. Nei Grigioni i punti pericolosi sono ancora frequenti, anche già nella zona del limite del bosco. I rumori di assestamento e i distacchi a distanza sono segnali tipici. Nel sud del Vallese i pronunciati strati fragili nella parte basale del manto nevoso sono generalmente ricoperti da una quantità di neve un po' più abbondante. I punti pericolosi in cui le valanghe possono subire un distacco nel debole manto di neve vecchia sono pertanto un po' più rari e si trovano soprattutto nelle zone scarsamente innevate.
Con le temperature miti, sui pendii ripidi erbosi situati al di sotto dei 2000 m circa si prevedono valanghe per scivolamento di neve di medie e grandi dimensioni.

Retrospettiva meteo fino a lunedì

Nella notte, nelle regioni settentrionali ci sono state deboli precipitazioni, che hanno assunto carattere nevoso al di sopra dei 1600 m circa. Nel corso della giornata il tempo è stato molto nuvoloso, ma sostanzialmente asciutto. Nelle regioni alpine interne il cielo è stato parzialmente soleggiato, in quelle meridionali c'è stato bel tempo.

Neve fresca
Nella notte fra domenica e lunedì sono cadute le seguenti quantità di neve:
- Lungo le prealpi centrali e orientali: circa 10 cm
- Altrove: meno. Regioni meridionali: tempo asciutto

Temperatura
Sul mezzogiorno a 2000 m compresa tra +2 °C nelle regioni settentrionali e miti +5 °C in quelle meridionali

Vento
Da moderato a forte, proveniente da ovest a nord ovest

Previsioni meteo fino a martedì

Nelle regioni occidentali e meridionali il tempo sarà soleggiato, mentre in quelle orientali ci saranno precipitazioni, a carattere nevoso al di sopra dei 1900 m circa.

Neve fresca
Da lunedì fino al termine delle precipitazioni cadranno le seguenti quantità di neve:
- Prettigovia, Silvretta e Samnaun: dai 10 ai 20 cm
- Versante nordalpino centrale e orientale, restanti regioni del nord dei Grigioni e della Bassa Engadina: fino ai 10 cm

L'entità di queste precipitazioni è tuttavia ancora incerta.

Temperatura
Sul mezzogiorno a 2000 m compresa tra miti +5 °C nelle regioni sud occidentali e +1 °C in quelle nord orientali

Vento
Nelle regioni settentrionali, nella notte ancora da moderato a forte, proveniente da ovest, nel corso della giornata debole
Sulla cresta principale delle Alpi e a sud di essa, a tratti tempestoso in quota nella notte, per il resto da moderato a forte proveniente da nord ovest

Tendenza fino a giovedì

Le notti serene saranno seguite da giornate soleggiate. Con una quota dello zero termico collocata a 3100 m mercoledì e a 2700 m giovedì, le temperature saranno decisamente miti. Il vento proveniente dai quadranti occidentali sarà inizialmente debole, giovedì nel corso della giornata moderato.
Il pericolo di valanghe asciutte diminuirà, ma nel sud del Vallese, in Ticino e nei Grigioni tale calo sarà molto lento a causa dei pronunciati strati deboli. Si prevedono ancora valanghe per scivolamento di neve, che nelle regioni occidentali e settentrionali potranno raggiungere anche grandi dimensioni.