Mittwoch 25.02.2026

Veröffentlicht am 24.02.2026 um 17:00

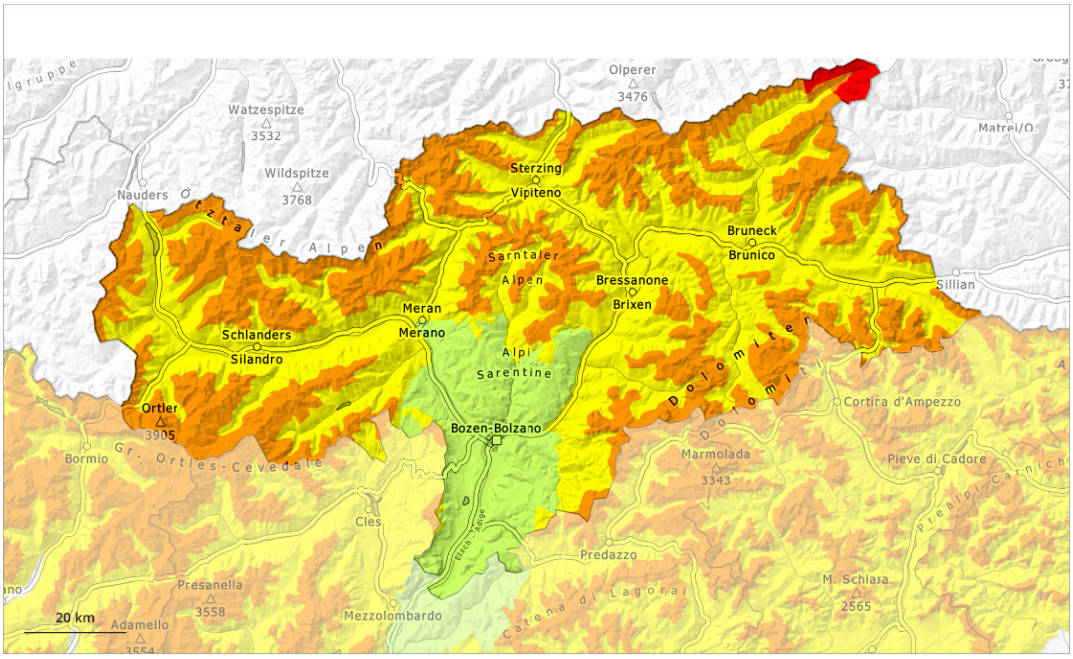

1	2	3	4	5
gering	mäßig	erheblich	groß	sehr groß

Gefahrenstufe 4 - Groß

Waldgrenze

Tendenz: Lawinengefahr bleibt gleich
am Donnerstag, den 26.02.2026

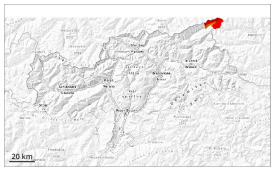

Altschnee

Waldgrenze

Triebschnee

Waldgrenze

Nassschnee

2200m

Mit Neuschnee und Erwärmung weiterhin gefährliche Lawinensituation.

Mit Neuschnee und starkem bis stürmischem Nordwestwind entstanden in Rinnen, Mulden und hinter Geländekanten weitere Triebschneeansammlungen. Neu- und Triebschnee der letzten Tage überlagern eine schwache Altschneedecke. Dies an West-, Nord- und Osthängen. Die Gefahrenstellen sind zahlreich, besonders im Bereich der Waldgrenze sowie oberhalb der Waldgrenze. Wintersportler können leicht Lawinen auslösen, auch große. Spontane Lawinen sind immer noch möglich.

Mit der tageszeitlichen Erwärmung und der Sonneneinstrahlung sind im Tagesverlauf Lockerschneelawinen zu erwarten. Dies vor allem an steilen Sonnenhängen. Die nassen Lawinen können vor allem an steilen, eher schneearmen Ost- und Westhängen bis in tiefe Schichten durchreißen und vereinzelt groß werden.

Zudem sind Gleitschneelawinen möglich. Dies besonders an Böschungen und Grashängen unterhalb von rund 2000 m.

Schneedecke

Gefahrenmuster gm.1: bodennahe schwachschicht | gm.10: frühjahrssituation

Am Dienstag fielen 15 bis 30 cm Schnee, lokal auch mehr. Der Wind blies teils stark bis stürmisch. Der Wind hat den Neuschnee intensiv verfrachtet. Es entstanden weitere Triebschneeansammlungen. Am Mittwoch ist es sehr mild.

Die Schneedecke ist verbreitet störanfällig. Neu- und Triebschnee überlagern eine schwache Altschneedecke. Im unteren Teil der Altschneedecke sind ausgeprägte Schwachschichten vorhanden. Dies vor allem an West-, Nord- und Osthängen im Bereich der Waldgrenze und oberhalb der Waldgrenze.

Der Regen führte in tiefen und mittleren Lagen zu einer Durchnässung der Schneedecke.

Tendenz

Kaum Rückgang der Gefahr von trockenen Lawinen. Allmählicher Anstieg der Gefahr von nassen Lawinen mit der Erwärmung.

Gefahrenstufe 3 - Erheblich

1800m

Tendenz: Lawinengefahr bleibt gleich
am Donnerstag, den 26.02.2026

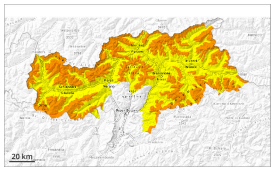

Altschnee

1800m

Triebschnee

2400m

Nassschnee

Vorsicht vor schwachem Altschnee. Vor allem aber nimmt die Gefahr von nassen Lawinen zu.

Lawinen können im Altschnee ausgelöst werden und an West-, Nord- und Osthängen vereinzelt groß werden. Dies durch einzelne Wintersportler. Die Gefahrenstellen liegen vor allem oberhalb von rund 1800 m. In der Sturzbahn können Lawinen den nassen Schnee mitreißen. Dies verlängert die Auslaufstrecken der Lawinen.

Die frischen Triebschneeansammlungen sind vor allem an steilen West-, Nord- und Osthängen in der Höhe störanfällig.

Mit der tageszeitlichen Erwärmung und der Sonneneinstrahlung sind kleine und mittlere nasse Lawinen zu erwarten. Dies vor allem an sehr steilen Sonnenhängen und an Felswandfüßen. Die Auslaufbereiche sollten beachtet werden.

Schneedecke

Gefahrenmuster gm.1: bodennahe schwachschicht | gm.10: frühjahrssituation

In der Altschneedecke sind vor allem an West-, Nord- und Osthängen ausgeprägte Schwachschichten vorhanden.

Die nächtliche Abstrahlung ist zeitweise gut. Die Wetterbedingungen führen im Tagesverlauf zu einer Durchnässung der Schneedecke. Dies besonders an sehr steilen Sonnenhängen unterhalb von rund 2400 m.

Tendenz

> Die Aktivität von nassen Lawinen nimmt mit der Erwärmung und der Sonneneinstrahlung deutlich zu.

Gefahrenstufe 2 - Mäßig

Waldgrenze

Tendenz: Lawinengefahr bleibt gleich
am Donnerstag, den 26.02.2026

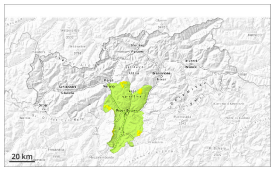

Altschnee

Waldgrenze

Nassschnee

Schwachschichten im Altschnee können vereinzelt ausgelöst werden.

Lawinen können vereinzelt im Altschnee ausgelöst werden und an West-, Nord- und Osthängen mittlere Größe erreichen. Dies durch einzelne Wintersportler. In der Sturzbahn können Lawinen den nassen Schnee mitreißen.

Mit der tageszeitlichen Erwärmung und der Sonneneinstrahlung sind einzelne kleine und mittlere nasse Lawinen zu erwarten.

Schneedecke

Gefahrenmuster gm.1: bodennahe schwachschicht gm.10: frühjahrssituation

In der Altschneedecke sind vor allem an West-, Nord- und Osthängen ausgeprägte Schwachschichten vorhanden.

Die nächtliche Abstrahlung ist verbreitet recht gut. Die Wetterbedingungen führen im Tagesverlauf zu einer Durchnässung der Schneedecke.

Tendenz

Nassschnee beachten.