Mittwoch 25.02.2026

Veröffentlicht am 24.02.2026 um 17:00

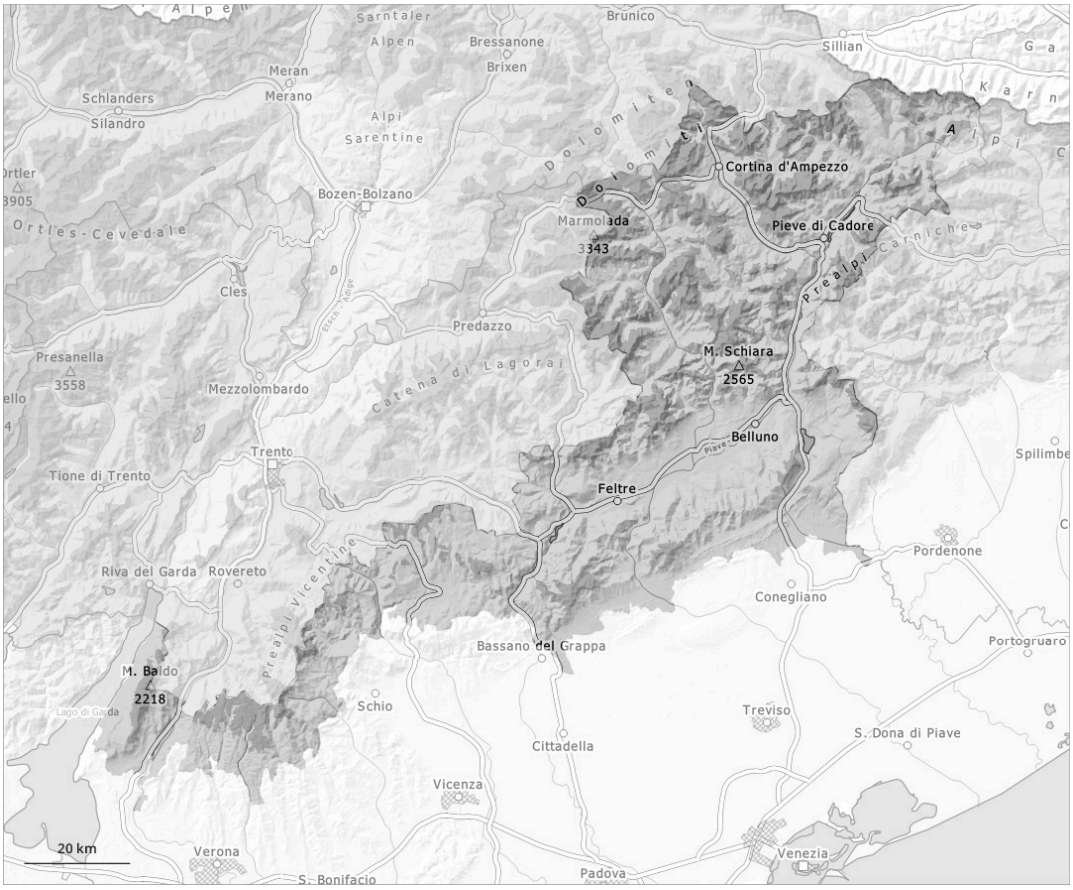

1	2	3	4	5
gering	mäßig	erheblich	groß	sehr groß

Gefahrenstufe 3 - Erheblich

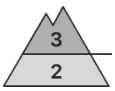

Waldgrenze

Tendenz: Lawinengefahr bleibt gleich
am Donnerstag, den 26.02.2026

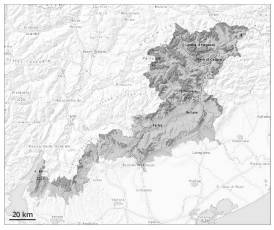

Triebschnee

Waldgrenze

Altschnee

Waldgrenze

Nassschnee

2400m

Vorsicht vor Triebschnee und schwachem Altschnee. Sehr steile Sonnenhänge: Anstieg der Gefahr von nassen Lawinen mit der tageszeitlichen Erwärmung und der Sonneneinstrahlung.

Besonders in Kammlagen, Rinnen und Mulden entstanden flächige Triebschneeansammlungen. Die Gefahrenstellen liegen vor allem an Triebschneehängen aller Expositionen oberhalb von rund 1900 m sowie an Übergängen von wenig zu viel Schnee.
Die Lawinen können an steilen Schattenhängen in tiefen Schichten ausgelöst werden und recht groß werden. Dies durch einzelne Wintersportler. In der Sturzbahn können Lawinen den nassen Schnee mitreißen. Fernauslösungen sind möglich. Wummgeräusche und Risse beim Betreten der Schneedecke sind Alarmzeichen.
Mit der tageszeitlichen Erwärmung steigt die Gefahr von feuchten und nassen Lawinen im Tagesverlauf an. Touren sollten rechtzeitig beendet werden.

Schneedecke

Gefahrenmuster gm.1: bodennahe schwachschicht | gm.10: frühjahrssituation

Vor allem oberhalb von rund 1900 m entstanden gut sichtbare Triebschneeansammlungen.
In der Altschneedecke sind vor allem an steilen Nord-, Ost- und Westhängen Schwachschichten vorhanden.
Die nächtliche Abstrahlung ist zeitweise reduziert. Sonne und Wärme führen im Tagesverlauf vor allem an sehr steilen Sonnenhängen unterhalb von rund 2400 m zu einer raschen Anfeuchtung der Schneedecke.

Tendenz

Die Gefahr von feuchten und nassen Lawinen steigt an.