ICGC Institut Cartogràfic i Geològic de Catalunya

Servei Meteorològic de Catalunya meteo.cat

Boletín de peligro de aludes para el Pirineo de Catalunya
Del 24/02/2026 al 25/02/2026

(Válido fuera pistas de esquí y zonas no controladas)

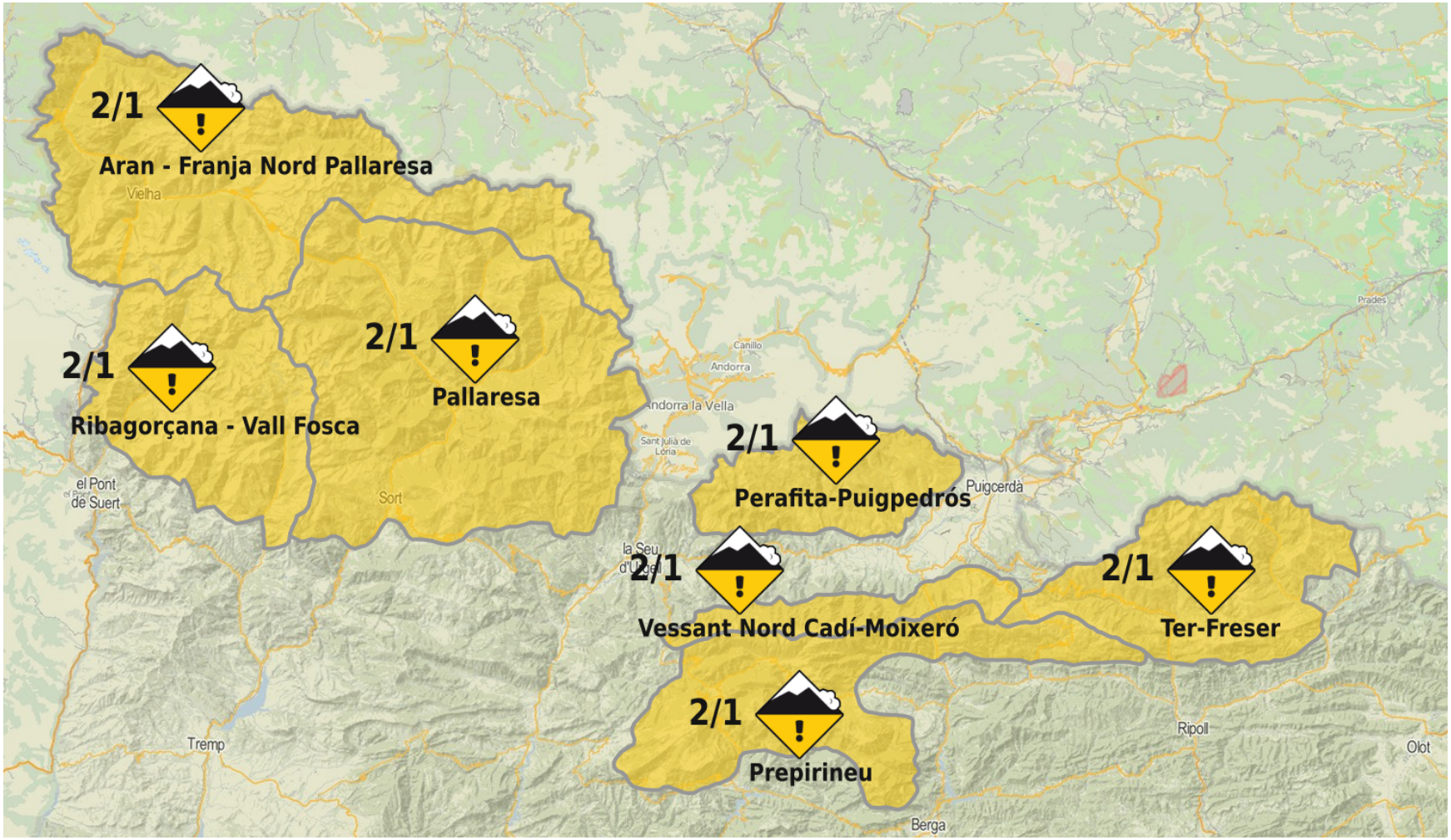

5 MUY FUERTE	4 FUERTE	3 NOTABLE	2 LIMITADO	1 DÉBIL

ICGC Institut Cartogràfic i Geològic de Catalunya

Servei Meteorològic de Catalunya meteo.cat

Boletín de peligro de aludes Aran - Franja Nord Pallaresa Del 24/02/2026 al 25/02/2026

(Válido fuera pistas de esquí y zonas no controladas)

LIMITADO (2) por encima del límite de bosque, DÉBIL (1) por debajo, hasta mediodía.

Situación primaria

Deslizamientos basales **Distribución** **Tamaño** **Origen** **Tendencia**

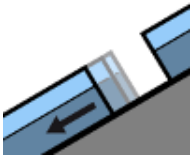

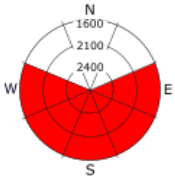

Situación secundaria

Nieve húmeda **Distribución** **Tamaño** **Origen** **Tendencia**

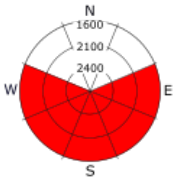

Estado del manto nivoso

La actividad de deslizamientos basales ha continuado y, de forma más ocasional, la de nieve húmeda. La elevada temperatura e insolación diurnas humedecen el manto, especialmente a partir de mediodía y en solanas. A primeras horas de la mañana podemos encontrar el manto encostrado en estas orientaciones. Continuará la actividad de aludes de nieve húmeda, especialmente en orientaciones S, E y W, y del mediodía hasta la tarde. Se esperan caída de bolas, purgas y aludes de tamaño pequeño o medio, que pueden producirse hasta cota alta, en laderas soleadas de fuerte pendiente preferentemente. También puede continuar la actividad de deslizamientos basales en vertientes propicios. De manera muy local, en las umbrías más elevadas encontraremos placas antiguas que se podrían desencadenar al paso de personas por encima de 2.400 m. Serían aludes de tamaño 1.

Distribución del manto nivoso

Hay nieve por encima de unos 1.400 ma umbrías y 1.600 ma solanas. Los espesores a unos 2.200 m son superiores a los normales y rondan los 120-140 cm en el norte de Aran y los 160-200 cm en la Franja Norte Pallaresa y en el sur de Aran, puntualmente superiores.

Tendencia para las próximas 48-72h

Condiciones muy similares al manto nivoso. Predominarán los problemas por nieve húmeda y deslizamientos basales. Peligro ESTACIONARIO.

El próximo boletín será emitido el día 2026-02-25

5 MUY FUERTE	4 FUERTE	3 NOTABLE	2 LIMITADO	1 DÉBIL

EAWS EUROPEAN AVALANCHE WARNING SERVICES

ICGC Institut Cartogràfic i Geològic de Catalunya

Servei Meteorològic de Catalunya

Boletín de peligro de aludes Ribagorçana - Vall Fosca Del 24/02/2026 al 25/02/2026

(Válido fuera pistas de esquí y zonas no controladas)

LIMITADO (2) de media mañana hasta la tarde, DÉBIL (1) el resto

Situación primaria

Nieve húmeda

Distribución

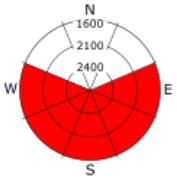

Tamaño

Origen

Tendencia

Situación secundaria

Capas débiles persistentes

Distribución

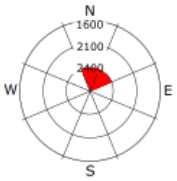

Tamaño

Origen

Tendencia

Estado del manto nivoso

El manto presenta un comportamiento típicamente primaveral en el sector, con fusión superficial a lo largo del día, y enfriamiento y rehielo nocturno. Con el paso de las horas, a partir de media mañana y hasta la tarde, es probable actividad de aludes de nieve húmeda, especialmente en orientaciones este, sur y oeste. Se esperan caída de bolas, purgas y aludes pequeños, que pueden producirse hasta cota alta, en laderas soleadas de fuerte pendiente preferentemente. No se descarta puntualmente algún deslizamiento basal sobre sustrato liso o herboso. En umbrías, en cota alta, todavía se pueden encontrar placas antiguas que descansan sobre niveles de nieve facetada, poco reactivas en general, pero que todavía pueden ceder por sobrecargas y generar aludes de pequeño tamaño. Estas placas, con el paso de los días, van quedando más restringidas y resultan menos sensibles.

Distribución del manto nivoso

Hay nieve en el suelo a 1.500 m en terreno umbrío, y por encima de unos 1.600-1700 m en laderas soleadas. El manto es esquiable por encima de unos 1.600 m en umbrías. Los espesores alcanzan los 120-150 cm en cotas medias. Estos valores son superiores a los normales para la época.

Tendencia para las próximas 48-72h

Las condiciones del manto serán muy similares, con fusión superficial de la nieve a lo largo del día, y placas cada vez menos propicias al desencadenamiento. Peligro ESTACIONARIO.

El próximo boletín será emitido el día 2026-02-25

5 MUY FUERTE	4 FUERTE	3 NOTABLE	2 LIMITADO	1 DÉBIL

EAWS EUROPEAN AVALANCHE WARNING SERVICES

ICGC Institut Cartogràfic i Geològic de Catalunya

Servei Meteorològic de Catalunya

Boletín de peligro de aludes Pallaresa
Del 24/02/2026 al 25/02/2026

(Válido fuera pistas de esquí y zonas no controladas)

LIMITADO (2) de media mañana hasta la tarde, DÉBIL (1) el resto

Situación primaria

Nieve húmeda

Distribución

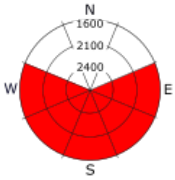

Tamaño

Origen

Tendencia

Situación secundaria

Capas débiles persistentes

Distribución

Tamaño

Origen

Tendencia

Estado del manto nivoso

El manto presenta un comportamiento típicamente primaveral en el sector, con fusión superficial a lo largo del día, y enfriamiento y rehielo nocturno. Con el paso de las horas, a partir de media mañana y hasta la tarde, es probable actividad de aludes de nieve húmeda, especialmente en orientaciones este, sur y oeste. Se esperan caída de bolas, purgas y aludes pequeños, que pueden producirse hasta cota alta, en laderas soleadas de fuerte pendiente preferentemente. No se descarta puntualmente algún deslizamiento basal sobre sustrato liso o herboso. En umbrías, en cota alta, todavía se pueden encontrar placas antiguas que descansan sobre niveles de nieve facetada, poco reactivas en general, pero que todavía pueden ceder por sobrecargas y generar aludes de pequeño tamaño. Estas placas, con el paso de los días, van quedando más restringidas y resultan menos sensibles.

Distribución del manto nivoso

Hay nieve en el suelo a 1.500 m en terreno umbrío, esquiable por encima de unos 1.600 m; en orientaciones soleadas la nieve está presente por encima de unos 1.600-1.700 m. Los espesores alcanzan los 110-150 cm en cotas medias. Estos valores son superiores a los normales para la época.

Tendencia para las próximas 48-72h

Las condiciones del manto serán muy similares, con fusión superficial de la nieve a lo largo del día, y placas cada vez menos propicias al desencadenamiento. Peligro ESTACIONARIO.

El próximo boletín será emitido el día 2026-02-25

5 MUY FUERTE	4 FUERTE	3 NOTABLE	2 LIMITADO	1 DÉBIL

EAWS EUROPEAN AVALANCHE WARNING SERVICES

ICGC Institut Cartogràfic i Geològic de Catalunya

Servei Meteorològic de Catalunya

Boletín de peligro de aludes Perafita-Puigpedrós Del 24/02/2026 al 25/02/2026

(Válido fuera pistas de esquí y zonas no controladas)

LIMITADO (2) de media mañana hasta la tarde, DÉBIL (1) el resto

Situación primaria

Nieve húmeda

Distribución

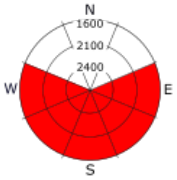

Tamaño

Origen

Tendencia

Situación secundaria

Capas débiles persistentes

Distribución

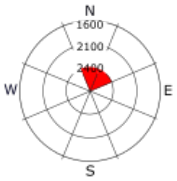

Tamaño

Origen

Tendencia

Estado del manto nivoso

A primera hora encontraremos un manto bien rehelado y estable en buena parte del terreno; con el paso de las horas, con la insolación y las temperaturas elevadas, el manto humedecerá superficialmente. Es probable actividad de aludes de nieve húmeda, especialmente en orientaciones S, E y W. Se esperan caída de bolas, purgas y aludes pequeños, que pueden producirse hasta cota alta, en vertientes soleadas de fuerte pendiente preferentemente. No se descarta puntualmente algún deslizamiento basal sobre sustrato liso o herboso. En umbrías, en cota alta, todavía se pueden encontrar placas antiguas sobre niveles de facetas enterrados, poco sensibles en general, pero que todavía pueden ceder por sobrecargas y generar aludes de pequeño tamaño. Estas placas, con el paso de los días, van quedando más restringidas y resultan menos sensibles.

Distribución del manto nivoso

Hay nieve en el suelo por encima de unos 1.400-1500 m, aunque en las solanas más derechas el manto va retranqueando. El manto es esquiable por encima de unos 1.700 m en N. Los espesores, aunque irregulares, rondan los 80-120 cm en cotas medias, con frecuentes deflaciones en orientaciones norte y oeste por encima del nivel del bosque. Son grosores muy por encima de los habituales por la época.

Tendencia para las próximas 48-72h

Las condiciones serán muy similares, con predominio del humedecimiento diurno y placas que van perdiendo protagonismo. Peligro ESTACIONARIO.

El próximo boletín será emitido el día 2026-02-25

5 MUY FUERTE	4 FUERTE	3 NOTABLE	2 LIMITADO	1 DÉBIL

EAWS EUROPEAN AVALANCHE WARNING SERVICES

ICGC Institut Cartogràfic i Geològic de Catalunya

Servei Meteorològic de Catalunya

Boletín de peligro de aludes Vessant Nord Cadí-Moixeró Del 24/02/2026 al 25/02/2026

(Válido fuera pistas de esquí y zonas no controladas)

LIMITADO (2) de media mañana hasta la tarde, DÉBIL (1) el resto

Situación primaria

Nieve húmeda

Distribución

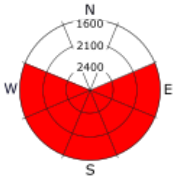

Tamaño

Origen

Tendencia

Situación secundaria

Capas débiles persistentes

Distribución

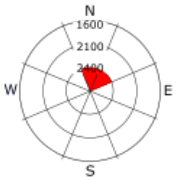

Tamaño

Origen

Tendencia

Estado del manto nivoso

El manto presenta un comportamiento típicamente primaveral. Por la mañana encontraremos un fuerte rehielo superficial, que irá cediendo por el ablandamiento con el sol y las elevadas temperaturas. En las últimas jornadas la actividad de aludes de nieve húmeda no ha sido muy intensa en el sector. Sin embargo, continuará la probabilidad de aludes de nieve húmeda, en orientaciones S, E y W, hasta cotas altas, en las horas de máximo humedecimiento, preferentemente en laderas de fuerte pendiente y bajo resaltes rocosos. Serán purgas o caída de bolas, y aludes pequeños, sin descartar, muy localmente, alguno de tamaño mediano. En las umbrías de cota alta todavía podemos encontrar pequeñas placas locales que por sobrecarga puedan ceder y generar aludes de pequeño tamaño. Estas placas, con el paso de los días, van quedando más restringidas y resultan menos sensibles.

Distribución del manto nivoso

Hay manto continuo por encima de unos 1.700 m y esquiable por encima de unos 1.800 m. Los espesores están alrededor de 140-170 cm en cotas medias. Estos valores son muy excedentarios para la época del año.

Tendencia para las próximas 48-72h

Persistirá el problema de nieve húmeda. Peligro: ESTACIONARIO

El próximo boletín será emitido el día 2026-02-25

5 MUY FUERTE	4 FUERTE	3 NOTABLE	2 LIMITADO	1 DÉBIL

EAWS EUROPEAN AVALANCHE WARNING SERVICES

ICGC Institut Cartogràfic i Geològic de Catalunya

Servei Meteorològic de Catalunya

Boletín de peligro de aludes Prepirineu
Del 24/02/2026 al 25/02/2026

(Válido fuera pistas de esquí y zonas no controladas)

LIMITADO (2) de media mañana hasta la tarde, DÉBIL (1) el resto

Situación primaria

Nieve húmeda

Distribución

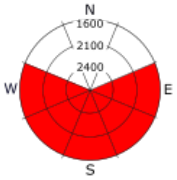

Tamaño

Origen

Tendencia

Estado del manto nivoso

El manto sigue mostrándose muy húmedo en las horas centrales del día y por la tarde en las vertientes más soleadas, por las altas temperaturas y la intensa radiación. Hasta primeras horas de la mañana, el rehielo nocturno mantiene el manto encostrado superficialmente. Persiste la probabilidad de aludes de nieve húmeda, en orientaciones este, sur y oeste, hasta cotas altas, más probables desde media mañana hasta la tarde, preferentemente en laderas de fuerte pendiente y bajo resaltes rocosos. Serán purgas o aludes pequeños, sin descartar muy localmente alguno de tamaño mediano.

Distribución del manto nivoso

Hay nieve desde 1.500 a 1600 m esquiable a partir de unos 1.700 m en orientaciones umbrías. En solanas el manto está presente a partir de unos 1.600-1.700 m. Los grosores están alrededor de 100-120 cm a unos 2.200 my son superiores a los habituales. Aparecen deflaciones por encima del nivel del bosque, sobre todo en lugares bien expuestos al viento de norte y oeste.

Tendencia para las próximas 48-72h

Las condiciones serán muy similares al sector, con predominio del humedecimiento a lo largo del día y probabilidad de purgas húmedas. Peligro ESTACIONARIO.

El próximo boletín será emitido el día 2026-02-25

5 MUY FUERTE	4 FUERTE	3 NOTABLE	2 LIMITADO	1 DÉBIL

EAWS EUROPEAN AVALANCHE WARNING SERVICES

ICGC Institut Cartogràfic i Geològic de Catalunya

Servei Meteorològic de Catalunya

Boletín de peligro de aludes Ter-Freser
Del 24/02/2026 al 25/02/2026

(Válido fuera pistas de esquí y zonas no controladas)

LIMITADO (2) de media mañana hasta la tarde, DÉBIL (1) el resto

Situación primaria

Nieve húmeda

Distribución

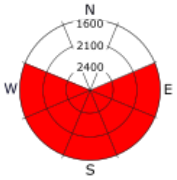

Tamaño

Origen

Tendencia

Situación secundaria

Deslizamientos basales

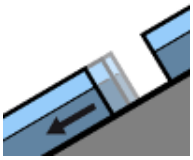

Distribución

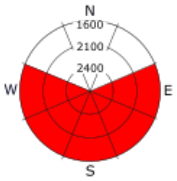

Tamaño

Origen

Tendencia

Estado del manto nivoso

En las últimas jornadas se ha observado actividad de aludes naturales de nieve húmeda y deslizamientos basales. Con la continuidad de las altas temperaturas y fuerte insolación el manto sigue humedeciendo durante las horas diurnas. Encontraremos un manto endurecido por rehielo a primera hora, que irá ablandando por fusión debido al sol y las elevadas temperaturas. Podrá haber purgas, o incluso algún alud de tamaño 2 (suficiente para enterrar a una persona) muy local fuera del terreno más umbrío. Tendrán lugar en laderas de fuerte inclinación que todavía no hayan purgado. Además continuará la actividad de deslizamientos basales con aludes que podrían llegar a tamaño 3, suficiente para enterrar a un grupo de personas. Tendrán lugar en laderas empinadas y herbosas, o bajo resaltes rocosos. Habrá que prestar atención con la aparición de grietas hasta el suelo y evitar terreno similar a donde se hayan detectado estos aludes.

Distribución del manto nivoso

El manto nivoso presenta grosores muy excedentarios para la época del año. En lugares no afectados por el viento, los espesores oscilan entre 90-130 cm a unos 2.000 m, siendo esquiable a partir de unos 1.600 m. Aparecen deflaciones por encima del nivel del bosque, sobre todo en lugares bien expuestos al viento de norte y oeste.

Tendencia para las próximas 48-72h

Las condiciones serán muy similares, con posibles aludes de nieve húmeda y, de forma muy local, probabilidad de deslizamientos basales. Peligro ESTACIONARIO.

El próximo boletín será emitido el día 2026-02-25

5 MUY FUERTE	4 FUERTE	3 NOTABLE	2 LIMITADO	1 DÉBIL

EAWS EUROPEAN AVALANCHE WARNING SERVICES