BUTLLETÍ DEL PERILL D'ALLAUS DEL PRINCIPAT D'ANDORRA

Elaborado el 24/02/2026 16:00
Proxima actualización 25/02/2026 a las 16h

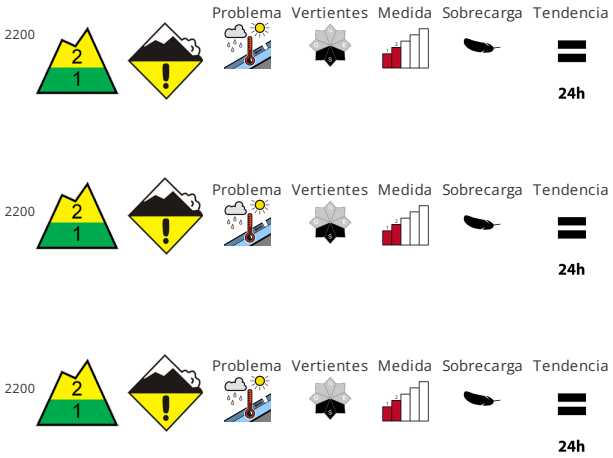

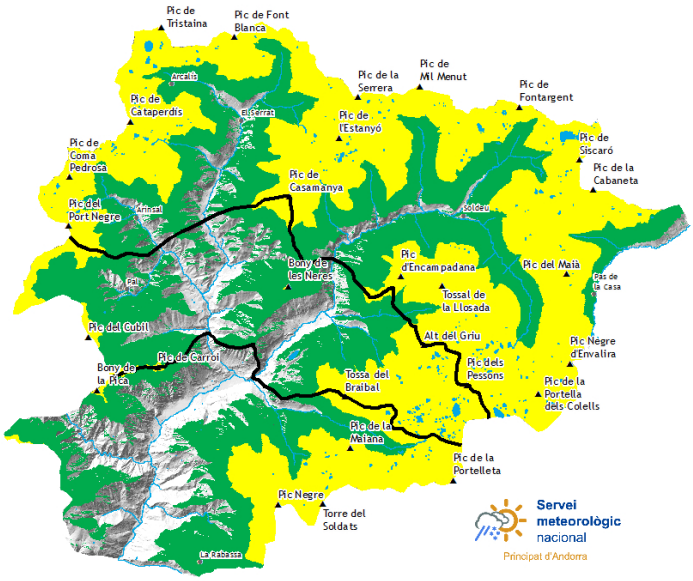

CALIDAD DE LA NIEVE

Luego de una noche serena, por la mañana las condiciones de aludes son favorables en muchos sectores. Con la subida de la temperatura diurna y la radiación solar, son probables solo de manera aislada avalanchas de placa húmeda de tamaño mediano. A partir del mediodía la probabilidad de desencadenamiento de aludes de nieve húmeda aumentará claramente sobre todo en las laderas solanas inclinadas. Esto se da especialmente en la base de las paredes rocosas, y en terreno pendiente y escarpado. Además son posibles aludes de deslizamiento basal en cualquier momento. Debido a la costra dura hay el peligro de resbalar y caer en las laderas inclinadas.

ESTABILIDAD DEL MANTO NIVOSO

Las condiciones son primaverales. El enfriamiento nocturno será bueno. La superficie del manto de nieve se volverá a helar para formar una costra portante y se ablandará durante el día. Los espesores de nieve varían mucho por encima de los 2500 m aproximadamente por la influencia del viento. Evitar las zonas con grietas de deslizamiento basal.

ESPESORES DEL MANTO NIVOSO FUERA DE PISTA

Zona norte		Espesor nieve		
Manto Nival		1500m	2000m	2500m
N	1400 m	30 cm	150 cm	200 cm
S	1800 m	0 cm	100 cm	150 cm

zona centro		Espesor nieve		
Manto Nival		1500m	2000m	2500m
N	1400 m	20 cm	150 cm	200 cm
S	1800 m	0 cm	100 cm	150 cm

Zona sur		Espesor nieve		
Manto Nival		1500m	2000m	2500m
N	1400 m	20 cm	120 cm	150 cm
S	1800 m	0 cm	60 cm	100 cm

Govern d'Andorra

Aquest butlletí ha estat elaborat seguint les normes i recomanacions de l'**European Avalanche Warning Services**, del qual el **Servei meteorològic Nacional** n'és membre

Información detallada por espacios naturales protegidos

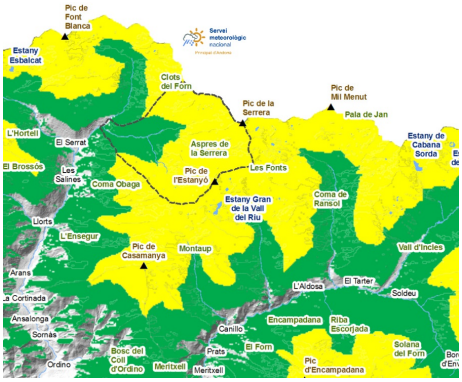

SORTENY

Encontramos nieve en todos los caminos desde Llorts y el acceso en esquís hasta el Refugio se puede hacer como hacía años que no se veía durante tantas semanas seguidas. Deberemos seguir las recomendaciones de la estabilidad del manto nivoso para evitar ponernos en peligro en las vertientes sur más inclinadas.

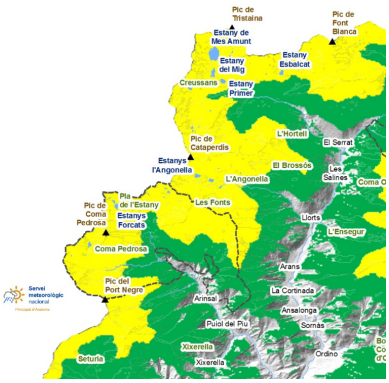

COMAPEDROSA

En cotas bajas la nieve se ha compactado y ha reducido su grosor debido a la humidificación. Deberemos vigilar a no resbalar debido a la corteza de rehielo. La distribución de la nieve es muy irregular a causa del viento. En las vertientes orientadas a este, como puede ser el acceso desde Arinsal por el Port Negre (Sanfons) deberemos extremar las precauciones para no desencadenar placas húmedas que todavía pueden bajar formadas con el viento de los últimos episodios.

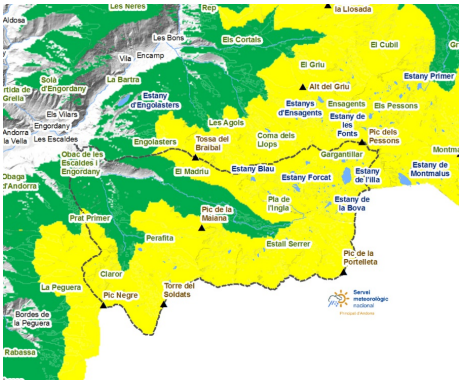

MADRIU-PERAFITA-CLAROR

En las vertientes este se debe circular con más cautela, ya que es donde están las acumulaciones de nieve venteada más importantes y todavía pueden bajar en forma de placa húmeda. En cotas altas los viento dejó la nieve dura al descubierto y con condiciones difíciles de bajar en algunas ocasiones, ya que a menudo está encostrada. En las vertientes sur y en cotas bajas las condiciones son primaverales, nieve dura por la mañana y blanda al mediodía.

BUTLLETÍ DEL PERILL D'ALLAUS DEL PRINCIPAT D'ANDORRA

Servei meteorològic nacional
Principat d'Andorra

Espesores de nieve nueva de los últimos días (de las ultimas 24h mesurado a las 06:00h UTC)

	20/02/2026	21/02/2026	22/02/2026	23/02/2026
FEDA (Central)	0 cm	0 cm	0 cm	0 cm
Engolasters - FEDA	0 cm	0 cm	0 cm	0 cm
Bony de les Neres	0 cm	0 cm	0 cm	0 cm
Sorteny	0 cm	0 cm	0 cm	0 cm
Perafita	0 cm	0 cm	0 cm	0 cm
Tossa Espiolets	0 cm	0 cm	0 cm	0 cm
Grau Roig - FEDA	0 cm	0 cm	0 cm	0 cm
Fontverd	0 cm	0 cm	0 cm	0 cm
Ransol - FEDA	0 cm	0 cm	0 cm	0 cm
Setúria	0 cm	0 cm	0 cm	0 cm
Caborreu	0 cm	0 cm	0 cm	0 cm
La Solana	0 cm	0 cm	0 cm	0 cm
Envalira Antenes	0 cm	0 cm	0 cm	0 cm
Vall del Riu FEDA	0 cm	0 cm	0 cm	0 cm