BUTLLETÍ DEL PERILL D'ALLAUS DEL PRINCIPAT D'ANDORRA

Préparé le 24/02/2026 16:00
Prochaine mise à jour le 25/02/2026 à 16h

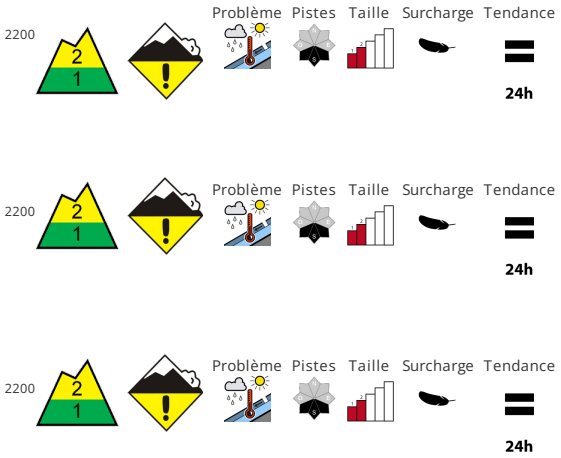

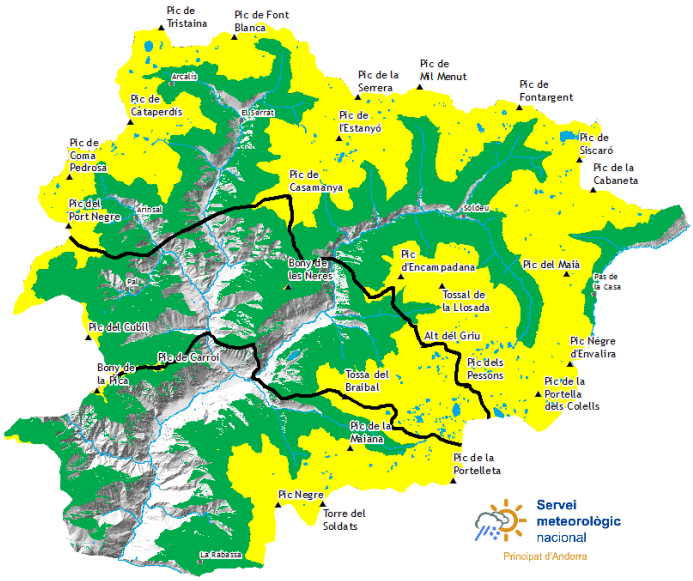

STABILITÉ DU MANTEAU NEIGEUX

Les conditions avalancheuses sont généralement favorables le matin après une nuit claire. Des avalanches de plaque de neige humide seulement encore isolées de moyenne taille sont ils sont à attendre avec le réchauffement diurne et le rayonnement solaire. À partir de midi d'avalanches humides augmente notoirement surtout sur les pentes raides au soleil augmentera. Ceci surtout au pied des parois rocheuses comme en terrain raide rocheux. En outre, des avalanches de glissement sont possibles à tout moment.. Sur la croûte dure il existe en terrain raide un risque de chute..

QUALITÈ DE LA NEIGE

Les conditions sont printanières. Le rayonnement nocturne est bon.. La surface de la neige regèle et devient porteuse et se ramollit en cours de journée.. On trouve suivant l'influence du vent des hauteurs de neiges très différentes au-dessus d'environ 2500 m. Les zones présentant des fissures de glissement doivent être évitées..

EPAISSEUR DE NEIGE HORS PISTE

Zone nord		Epaisseur de neige		
Nival manteau		1500m	2000m	2500m
N	1400 m	30 cm	150 cm	200 cm
S	1800 m	0 cm	100 cm	150 cm

Zone centre		Epaisseur de neige		
Nival manteau		1500m	2000m	2500m
N	1400 m	20 cm	150 cm	200 cm
S	1800 m	0 cm	100 cm	150 cm

Zone sud		Epaisseur de neige		
Nival manteau		1500m	2000m	2500m
N	1400 m	20 cm	120 cm	150 cm
S	1800 m	0 cm	60 cm	100 cm

Govern d'Andorra

EAWS EUROPEAN AVALANCHE WARNING SERVICES

Aquest butlletí ha estat elaborat seguint les normes i recomanacions de l'**European Avalanche Warning Services**, del qual el **Servei meteorològic Nacional** n'és membre

BUTLLETÍ DEL PERILL D'ALLAUS DEL PRINCIPAT D'ANDORRA

Servei meteorològic nacional
Principat d'Andorra

Des informations détaillées par espace naturel protégé

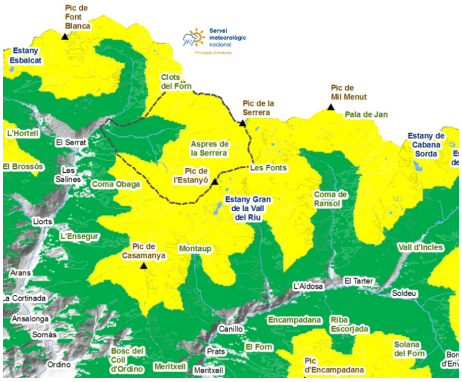

SORTENY

Nous trouvons de la neige sur toutes les routes depuis Llorts et l'accès à skis au Refuge peut se faire car on ne l'a pas vu depuis tant de semaines d'affilée depuis des années. Il faudra suivre les recommandations de stabilité du manteau neigeux pour éviter de se mettre en danger sur les versants sud plus inclinés. , , ,

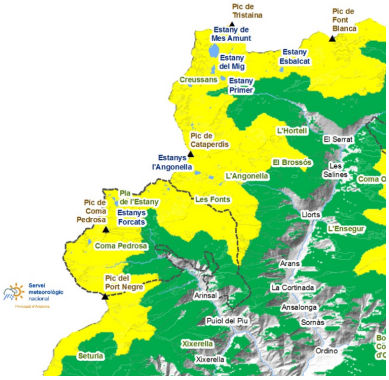

COMAPEDROSA

À basse altitude, la neige s'est compactée et a réduit son épaisseur en raison de l'humidification. Il faudra faire attention à ne pas glisser à cause de la croûte de gel. La répartition de la neige est très irrégulière à cause du vent. Sur les pentes exposées à l'est, comme l'accès d'Arinsal via Port Negre (Sanfons), il faudra prendre d'extrêmes précautions pour ne pas déclencher des zones humides qui pourraient encore descendre formées par le vent des derniers épisodes. , , , , , , ,

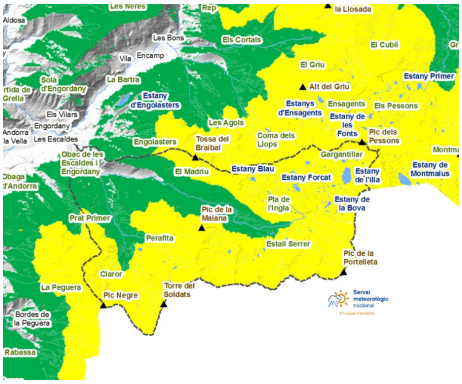

MADRIU-PERAFITA-CLAROR

Sur les pentes orientales, il faut conduire avec plus de prudence, car c'est là que se trouvent les accumulations de neige soufflées par le vent les plus importantes et elles peuvent encore tomber sous forme de plaque humide. À haute altitude, le vent laisse la neige dure exposée et avec des conditions difficiles à descendre, car elle est souvent incrustée. Sur le versant sud et à basse altitude, les conditions sont printanières, neige dure le matin et neige l'après-midi. , , , , ,

Govern d'Andorra

EAWS
EUROPEAN AVALANCHE WARNING SERVICES

Aquest butlletí ha estat elaborat seguint les normes i recomanacions de l'**European Avalanche Warning Services**, del qual el **Servei meteorològic Nacional** n'és membre

BUTLLETÍ DEL PERILL D'ALLAUS DEL PRINCIPAT D'ANDORRA

Servei meteorològic nacional
Principat d'Andorra

Couche de neige fraiche des derniers jours (De 24 h mesurée à 06:00 h UTC)

	20/02/2026	21/02/2026	22/02/2026	23/02/2026
FEDA (Central)	0 cm	0 cm	0 cm	0 cm
Engolasters - FEDA	0 cm	0 cm	0 cm	0 cm
Bony de les Neres	0 cm	0 cm	0 cm	0 cm
Sorteny	0 cm	0 cm	0 cm	0 cm
Perafita	0 cm	0 cm	0 cm	0 cm
Tossa Espiolets	0 cm	0 cm	0 cm	0 cm
Grau Roig - FEDA	0 cm	0 cm	0 cm	0 cm
Fontverd	0 cm	0 cm	0 cm	0 cm
Ransol - FEDA	0 cm	0 cm	0 cm	0 cm
Setúria	0 cm	0 cm	0 cm	0 cm
Caborreu	0 cm	0 cm	0 cm	0 cm
La Solana	0 cm	0 cm	0 cm	0 cm
Envalira Antenes	0 cm	0 cm	0 cm	0 cm
Vall del Riu FEDA	0 cm	0 cm	0 cm	0 cm