MINISTERO DELLA DIFESA

meteomont
Servizio Nazionale di previsione neve e valanghe

EAWS EUROPEAN AVALANCHE WARNING SERVICES

CARABINIERI

ALPI RETICHE

Bollettino Valanghe N. 357/2026 del 24/02/2026 ore 14.00
Validità 48 ore prossima emissione 25/02/2026

A cura del Servizio METEOMONT dell'ARMA dei CARABINIERI
In collaborazione con Servizio Meteorologico dell'Aeronautica militare

SITUAZIONE alle 14:00 del 24/02/2026

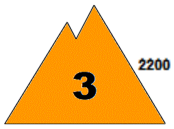

SITUAZIONE TIPO: neve a debole coesione e vento.



SITUAZIONE TIPO: strato debole persistente basale.

Quota neve (mslm)	Nord	Sud
	1100	1400

Altezza Neve (cm)	Neve al suolo	Neve Fresca	Quota (mslm)
	74	0	2150
	83	0	2010

VALANGHE OSSERVATE: Numerose valanghe di medie dimensioni, Valanghe di neve a debole coesione di superficie.

PREVISIONI 25/02/2026

GRADO DI PERICOLO: MARCATO 3

SITUAZIONE TIPO: neve a debole coesione e vento.

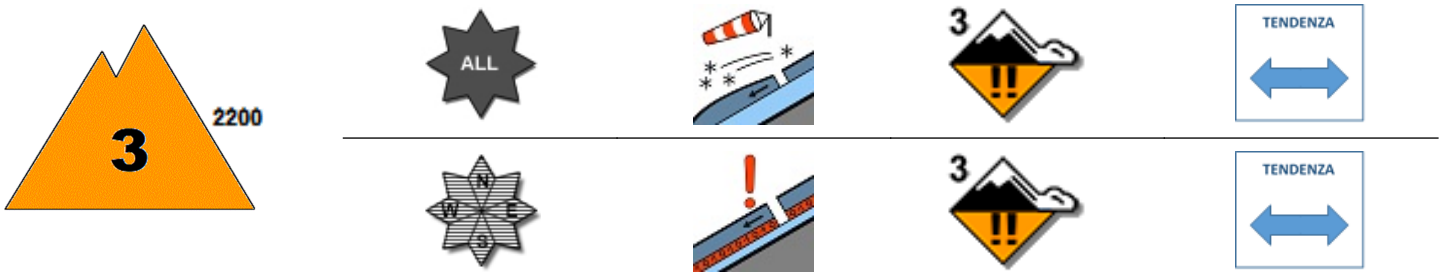

SITUAZIONE TIPO: strato debole persistente basale.

MANTO NEVOSO: La stabilità del manto nevoso è molto scarsa su alcuni punti (aree) per tutte le esposizioni al di sopra di 2200 mslm, possibili valanghe di dimensioni medie.
La stabilità del manto nevoso è scarsa su molti punti (aree) per isolati pendii al di sotto di 2200 mslm, possibili valanghe di dimensioni medie.

AVVERTENZE

A seguito dell'attività eolica registrata sono da evitare le zone di accumulo, conche, canaloni, cambi di pendenza e pendii sotto vento in genere.

SCALA EUROPEA DEL GRADO DI PERICOLO VALANGHE

LEGENDA PROBLEMA

Bollettino realizzato su scala sinottica-regionale (standard EAWS). La sua valutazione non può escludere in alcun modo la necessità di una seria e capace valutazione locale del pericolo (singolo pendio) che può essere anche sensibilmente diverso. Le previsioni meteorologiche sono relative all'orario UTC (per l'Italia +1 in inverno e +2 in estate).

Bollettino sottoposto a processi di: Acquisizione e controllo del C-Sifa e della rete di Osservatori e Esperti - Validazione del Previsore di turno - Certificazione della Sezione Meteomont.

ALPI RETICHE

PREVISIONE METEO

Quota		25/02/2026 h6:00	25/02/2026 h12:00	25/02/2026 h18:00
1000	Venti	02 Nodi da Nord	01 nodi da N-Ovest	00 Calma
	Temperature	+02 °C	+06 °C	+07 °C
	Temp.percepita	2 °C	6 °C	7 °C
2000	Venti	02 Nodi da Nord	01 nodi da N-Ovest	00 Calma
	Temperature	+02 °C	+06 °C	+07 °C
	Temp.percepita	2 °C	6 °C	7 °C
3000	Venti	03 nodi da N-Ovest	02 Nodi da Nord	01 Nodi da S-Est
	Temperature	+01 °C	+02 °C	+03 °C
	Temp.percepita	-1 °C	2 °C	3 °C
Zero termico		3100-3300 m.	3200-3400 m.	3200-3400 m.
Fenomeno		—	—	—
Stato del cielo				

LEGENDA FENOMENI

— Assenza Fenomeni · Nebbia · Foschia · Pioggia debole · Pioggia moderata · Pioggia forte · Temporali

Nevicata debole · Nevicata moderata · Nevicata forte

STATO DEL CIELO

Sereno · Poco nuvoloso · Nuvoloso · Molto nuvoloso · Coperto

Parametri meteonivometrici registrati presso i campi di rilevamento il 24/02/2026.

Località	Comune	Quota (m.s.l.m.)	Altezza neve (cm)	Neve caduta nelle 24 ore (cm)	Temp. Min (°C)	Temp. Max (°C)	Condizioni del tempo
SPONDA	Livigno (SO)	2150	74	Tracce di neve	-5	+4	Pioggia debole intermittente
FUMERO *	Sondalo (SO)	1583	38	0	N.P.	N.P.	Assenza di precipitazioni
VALAR	Valdidentro (SO)	1930	80	0	-6	+8	Assenza di precipitazioni
DOSSO DEL VALLONE	Valfurva (SO)	2582	61	0	-4	+2	Assenza di precipitazioni
ALPE PALU'	Chiesa in Valmalenco (SO)	2010	83	0	N.P.	N.P.	Precipitazioni all'orizzonte (pioggia, neve, grandine, temporali) ma non sulla stazione
COLONIA VIGILI	Ponte di Legno (BS)	1640	60	0	+1	+11	Assenza di precipitazioni
CIMA VERDA *	Tovo di sant'Agata (SO)	2291	103	0	N.P.	N.P.	Precipitazioni all'orizzonte (pioggia, neve, grandine, temporali) ma non sulla stazione

(*) Rilievi fuori campo

L'INFORMAZIONE E' PREVENZIONE - LEGGI L'ATTUALE GRADO DI PERICOLO VALANGHE!

IL CAPO DEL CENTRO NAZIONALE METEOMONT
(Ten. Col. RFI Emanuela Gini)
FIRMA AUTOGRAFA OMESSA AI SENSI
DELL'ART.3 DEL D.LGS N.39/1993

Bollettino realizzato su scala sinottica-regionale (standard EAWS). La sua valutazione non può escludere in alcun modo la necessità di una seria e capace valutazione locale del pericolo (singolo pendio) che può essere anche sensibilmente diverso. Le previsioni meteorologiche sono relative all'orario UTC (per l'Italia +1 in inverno e +2 in estate).