# PREALPI LOMBARDE

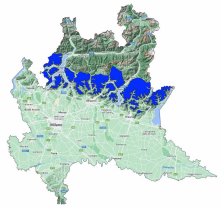

Bollettino Valanghe N. 353/2026 del 23/02/2026 ore 14.00
Validità 48 ore prossima emissione 24/02/2026
**A cura del Servizio METEOMONT dell'ARMA dei CARABINIERI**
**In collaborazione con Servizio Meteorologico dell'Aeronautica militare**

## SITUAZIONE alle 14:00 del 23/02/2026




**SITUAZIONE TIPO: neve a debole coesione e vento.**




**SITUAZIONE TIPO: situazione primaverile.**

| Quota neve (mslm) | Nord | Sud |
|---|---|---|
| | 1400 | 1700 |

| Altezza Neve (cm) | Neve al suolo | Neve Fresca | Quota (mslm) |
|---|---|---|---|
| | 59 | 0 | 1445 |
| | 42 | 0 | 1445 |

**VALANGHE OSSERVATE: Nessuna valanga.**

## PREVISIONI 24/02/2026

## GRADO DI PERICOLO: MODERATO 2

## SITUAZIONE TIPO: neve a debole coesione e vento.

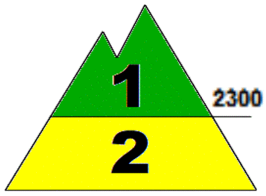


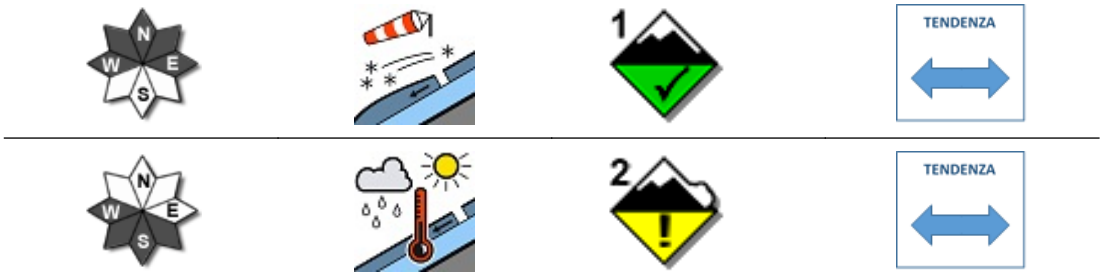


## SITUAZIONE TIPO: situazione primaverile.

**MANTO NEVOSO: La stabilità del manto nevoso è discreta su pochi punti (aree) per versanti da ovest a est al di sopra di 2300 mslm, possibili valanghe di dimensioni medie.**
**La stabilità del manto nevoso è scarsa su pochi punti (aree) per versanti al sole al di sotto di 2300 mslm, possibili valanghe di dimensioni medie.**

## AVVERTENZE

Il rialzo termico diurno richiede un'attenta valutazione temporale dell'escursione che eviti l'attraversamento di pendii ripidi nelle ore più calde della giornata.

## SCALA EUROPEA DEL GRADO DI PERICOLO VALANGHE

## LEGENDA PROBLEMA

**Bollettino realizzato su scala sinottica-regionale (standard EAWS). La sua valutazione non può escludere in alcun modo la necessità di una seria e capace valutazione locale del pericolo (singolo pendio) che può essere anche sensibilmente diverso. Le previsioni meteorologiche sono relative all'orario UTC (per l'Italia +1 in inverno e +2 in estate).**

# PREALPI LOMBARDE

## PREVISIONE METEO

| Quota | | 24/02/2026 h6:00 | 24/02/2026 h12:00 | 24/02/2026 h18:00 |
|---|---|---|---|---|
| 1000 | Venti | 03 Nodi da Nord | 02 nodi da N-Ovest | 03 Nodi da Nord |
| | Temperature | +04 °C | +08 °C | +06 °C |
| | Temp.percepita | 3 °C | 8 °C | 5 °C |
| 2000 | Venti | 07 nodi da N-Ovest | 05 nodi da N-Ovest | 06 Nodi da Nord |
| | Temperature | +04 °C | +05 °C | +06 °C |
| | Temp.percepita | 1 °C | 3 °C | 4 °C |
| 3000 | Venti | 16 nodi da N-Ovest | 14 Nodi da Nord | 11 Nodi da Nord |
| | Temperature | -03 °C | -02 °C | +00 °C |
| | Temp.percepita | -10 °C | -9 °C | -5 °C |
| Zero termico | | 2400-2600 m. | 2600-2800 m. | 3000-3200 m. |
| Fenomeno | | — | — | — |
| Stato del cielo | | | | |

## LEGENDA FENOMENI

— Assenza Fenomeni · Nebbia · Foschia · Pioggia debole · Pioggia moderata · Pioggia forte · Temporali

Nevicata debole · Nevicata moderata · Nevicata forte

## STATO DEL CIELO

Sereno · Poco nuvoloso · Nuvoloso · Molto nuvoloso · Coperto

## Parametri meteonivometrici registrati presso i campi di rilevamento il 23/02/2026.

| Località | Comune | Quota (m.s.l.m.) | Altezza neve (cm) | Neve caduta nelle 24 ore (cm) | Temp. Min (°C) | Temp. Max (°C) | Condizioni del tempo |
|---|---|---|---|---|---|---|---|
| PIANI DI BOBBIO | Barzio (LC) | 1724 | 59 | 0 | N.P. | N.P. | Assenza di precipitazioni |

(*) Rilievi fuori campo

**L'INFORMAZIONE E' PREVENZIONE - LEGGI L'ATTUALE GRADO DI PERICOLO VALANGHE!**

IL CAPO DEL CENTRO NAZIONALE METEOMONT
(Ten. Col. RFI Emanuela Gini)
FIRMA AUTOGRAFA OMESSA AI SENSI
DELL'ART.3 DEL D.LGS N.39/1993

Bollettino realizzato su scala sinottica-regionale (standard EAWS). La sua valutazione non può escludere in alcun modo la necessità di una seria e capace valutazione locale del pericolo (singolo pendio) che può essere anche sensibilmente diverso. Le previsioni meteorologiche sono relative all'orario UTC (per l'Italia +1 in inverno e +2 in estate).