Bulletin d'estimation du risque d'avalanche

(valable en dehors des pistes balisées et ouvertes)

MASSIF : Capcir Puymorens

Rédigé le mardi 24 février 2026 à 14h

Estimation des risques pour le : MERCREDI 25 FÉVRIER

QUELQUES STRUCTURES DE PLAQUES EN NORD D'ALTITUDE; HUMIDIFICATION QUI SE POURSUIT EN SUD.

2

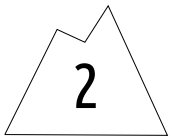

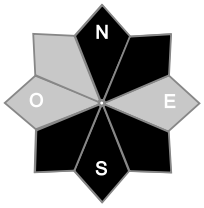

Indice de risque limité.

Départs spontanés : Dans les versants ensoleillés et en neige humide

Déclenchements provoqués : Structures de plaques encore présentes, notamment dans les secteurs proches de l'Ariège

Indices de risque : 5 très fort - 4 fort - 3 marqué - 2 limité - 1 faible -- En noir : les pentes les plus dangereuses

Stabilité du manteau neigeux

Situation avalancheuse typique : neige humide — couche fragile persistante

Départs spontanés :
Activité avalancheuse qui devrait augmenter au fil de la journée dans les pentes raides prenant le soleil, et notamment à proximités des rochers. Départs d'avalanches petites à moyennes, plus rarement grandes, avec l'humidification qui se généralise à des altitudes plus élevées. Les pentes raides des versants ensoleillées entre 2100 et 2500 m seront notamment concernées par une humidification plus en profondeur que les jours précédents.

Déclenchements provoqués :
Quelques avalanches de plaques sont encore possibles au passage d'un skieur, au-dessus de 2100 m, dans les versants Nord-Ouest à Nord-Est, notamment dans les secteurs du Capcir et proche de l'Ariège. Ces plaques sont plutôt en neige durcie par le vent mais pourraient parfois être friables dans des combes abritées. Elles reposent sur une couche fragile formée la semaine dernière et pourraient donner des avalanches de taille petite à moyenne en cas de déclenchement (taille 1 à 2).
Observables : neige travaillée par le vent en surface, effondrements sous les skis, couche de neige sans cohésion à quelques dizaines de cm de la surface.

Autre : La neige a pris des allures printanières dans de nombreux secteurs avec un risque accru de glissade sur des croutes parfois dures et épaisses suite au regel nocturne.

Qualité de la neige

Enneigement :
L'enneigement est excédentaire par rapport aux normales pour la période avec les passages neigeux successifs depuis janvier. Les vallées sont encore bien enneigées avec des quantités de neige importantes dès 1400 m. Malgré les belles journées qui s'enchaînent, la limite d'enneigement skiable n'évolue peu avec le regel nocturne qui permet toujours de chausser les skis dès 1500 m environ, parfois plus bas dans des configurations favorables.

Qualité de la neige :
Mardi matin, en toutes orientations, sous 2100 m, on devrait retrouver une neige dure et croûtée, mais pas toujours portante. En cours de journée, les conditions sont printanières avec l'humidification en profondeur du manteau neigeux qui se généralise jusqu'à 2300/2400 m en versant sud et de la neige devenant lourde et très humide, notamment à basse altitude.
À partir de 2200/2300 m, dans les combes encaissées, on doit tout de même encore pouvoir trouver de la neige sèche et parfois même légère.
Proche des crêtes et sommet, l'enneigement est très hétérogène avec des secteurs bien soufflés et parfois glacés, particulièrement sur les flancs ouest.

Aperçu météo pour le mercredi 25 février

	nuit	matin	après-midi	soir

Toujours du beau temps avec des nuages élevés. Températures encore très douces.

Pluie-Neige				
Iso 0 °C	3 400 m	3 200 m	3 200 m	3 100 m
Vent 2000 m	↗ 10 km/h	↗ 15 km/h	↑ 20 km/h	↗ 20 km/h
Vent 3000 m	→ 20 km/h	↗ 25 km/h	↗ 30 km/h	↗ 30 km/h

Épaisseur de neige hors-piste

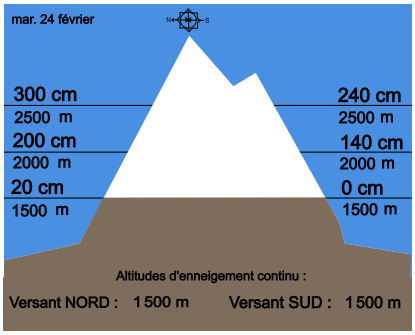

Précipitations à 1800 m

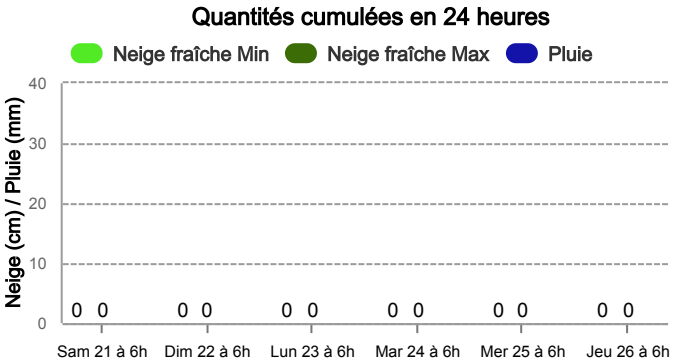

Tendance du jeudi 26 février

2

Indice de risque limité

Sans changement significatif avec les cycles de gel/dégel en cours.

Pour consulter la vigilance en cours, veuillez vous rendre sur le site https://vigilance.meteofrance.fr/fr

Météo-France - 73 avenue de Paris, 94165 Saint-Mandé cedex - Contact : contact@meteo.fr

Rédigé par Météo-France avec la contribution des observateurs du réseau nivo-météorologiques. Partenariat : ANMSM (Maires de Stations de Montagne), DSF (Domaines Skiables de France), ADSP (Directeurs de Pistes et de la Sécurité des Stations de Sports d'Hiver) et autres acteurs de la montagne.

Bulletin neige & avalanches par téléphone au **0 892 68 10 20** Service 0,35 € / min + prix appel

RÉPUBLIQUE FRANÇAISE
Liberté Égalité Fraternité

METEO FRANCE
À VOS CÔTÉS, DANS UN CLIMAT QUI CHANGE

Bulletin d'estimation du risque d'avalanche
(valable en dehors des pistes balisées et ouvertes)
MASSIF : Capcir Puymorens

Rédigé le mardi 24 février 2026 à 14h

Conditions nivo-météo des 7 derniers jours

	mer. 18/02				jeu. 19/02				ven. 20/02				sam. 21/02				dim. 22/02				lun. 23/02				mar. 24/02			
	03h	09h	15h	21h	03h	09h	15h	21h	03h	09h	15h	21h	03h	09h	15h	21h	03h	09h	15h	21h	03h	09h	15h	21h	03h	09h	15h	21h
Météo																												
Vent (km/h)	65	55	70	80	80	70	70	75	65	65	55	50	45	35	30	25	20	15	15	15	25	25	25	20	20	20	20	20
à 3000m	↗	↗	↗	↗	↘	↓	↓	↓	↓	↓	↓	↓	↓	↓	↓	↓	↓	→	→	→	→	↘	→	↓	→	↗	↗	↗
Vent (km/h)	30	25	35	50	75	60	60	65	60	60	40	30	25	20	20	15	10	10	10	10	15	15	15	10	10	10	10	10
à 2000m	→	↗	↗	↗	↘	↓	↓	↓	↓	↓	↓	↓	↓	↓	↓	↓	↘	↗	↘	→	→	↘	↘	→	↗	↗	↗	↑

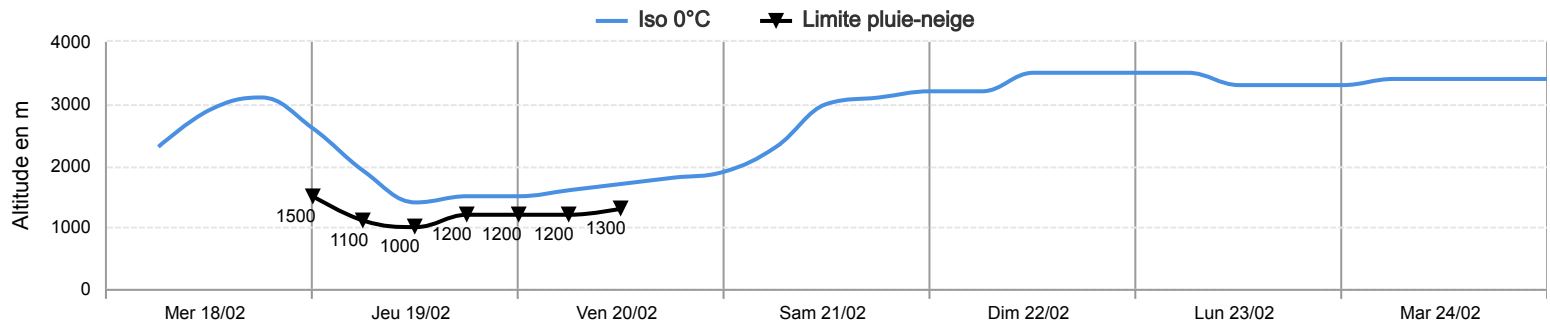

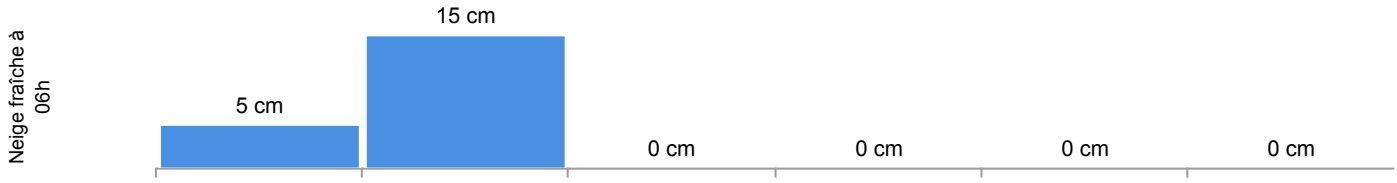

Risque d'avalanche	mer. 18/02	jeu. 19/02	ven. 20/02	sam. 21/02	dim. 22/02	lun. 23/02	mar. 24/02
	3	3	3	3	3	3	2

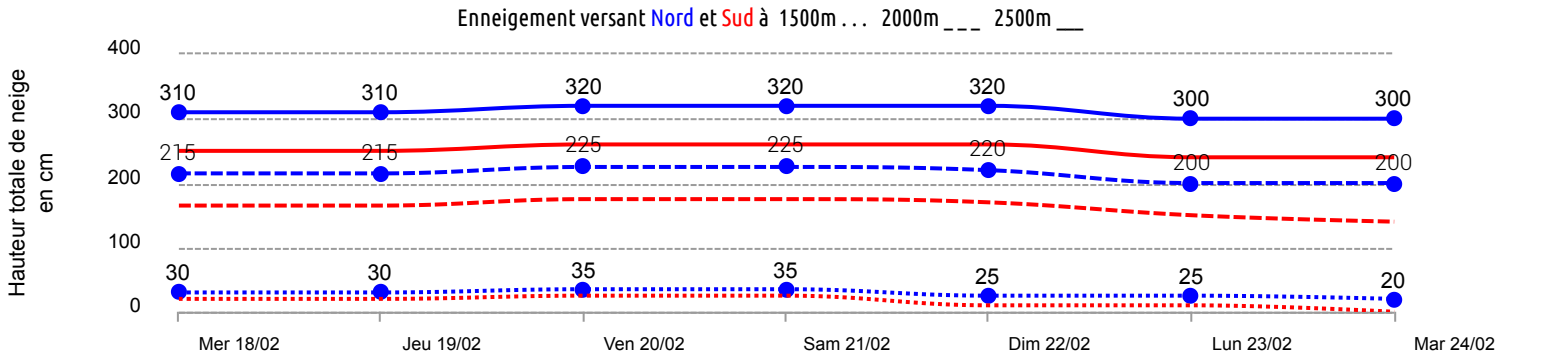

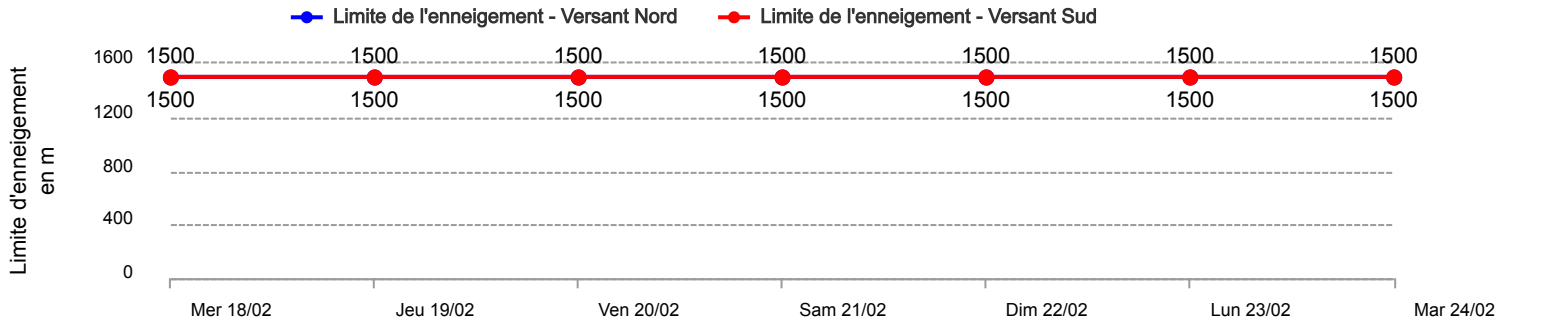

Pour consulter la vigilance en cours, veuillez vous rendre sur le site https://vigilance.meteofrance.fr/fr

Météo-France - 73 avenue de Paris, 94165 Saint-Mandé cedex - Contact : contact@meteo.fr

Rédigé par Météo-France avec la contribution des observateurs du réseau nivo-météorologiques. Partenariat : ANMSM (Maires de Stations de Montagne), DSF (Domaines Skiables de France), ADSP (Directeurs de Pistes et de la Sécurité des Stations de Sports d'Hiver) et autres acteurs de la montagne.

Bulletin neige & avalanches par téléphone au

0 892 68 10 20 Service 0,35 € / min + prix appel