Bulletin d'estimation du risque d'avalanche
(valable en dehors des pistes balisées et ouvertes)

MASSIF : Bauges

Rédigé le mardi 24 février 2026 à 16h

Estimation des risques pour le : MERCREDI 25 FÉVRIER

MANTEAU NEIGEUX RÉACTIF SOUS L'EFFET DE LA DOUCEUR

3

2 → 3

N O E S

Indice de risque limité évoluant en marqué.

Départs spontanés : avalanches de neige humide et plaques de fond

Déclenchements provoqués : coulées humides

Indices de risque : 5 très fort - 4 fort - 3 marqué - 2 limité - 1 faible -- En noir : les pentes les plus dangereuses

Stabilité du manteau neigeux

Situation avalancheuse typique : neige humide — avalanches de fond

Départs spontanés :
* **nombreuses avalanches de neige humide**, dès la fin de matinée, toutes orientations en suivant la course du soleil. La plupart en forme de poire, mais localement pouvant s'élargir nettement voire entraîner une plaque en contrebas. Taille 2 (moyenne), voire 3 (grande) en cas de grande pente qui n'aurait pas encore purgé. Ces avalanches partent spontanément au réchauffement, mais aussi au passage d'un skieur. *Observables :* escargots, départs souvent près des rochers/falaises réchauffés, enfoncement piéton pour estimer le volume mobilisable.
* **plaques de fond**. Surtout l'après-midi, mais possibles à n'importe quelle heure. Sur terrains raides et lisses en herbes, vires, dalles rocheuses. Taille 2 voire 3.

Déclenchements provoqués :
* **coulées ponctuelles de neige humide** sous les skis. Au réchauffement. Pouvant pousser une plaque en contrebas, taille 2.

Autres :
* **chutes de corniches**, épaisses et volumineuses, pouvant entraîner une plaque en contrebas.

Qualité de la neige

Enneigement : bon pour une fin février, à toutes altitudes. On peut chausser les skis vers 1200 m. Épaisseur du manteau neigeux hétérogène : fort tassement sous l'effet de la douceur, grosses corniches et accumulations, crêtes érodées par les forts vents pendant et après les perturbations (de SW puis NW).

Qualité de la neige mercredi :
* neige très dense, croûte cassante le matin, s'humidifiant rapidement. Forte tendance à l'humidification en profondeur.
* Plein N à l'abri du soleil : neige dense, croûtée le matin, puis lourde. Cartonnée près des crêtes exposées au vent de N.

Aperçu météo pour le mercredi 25 février

	nuit	matin	après-midi	soir
Soleil et grande douceur. +8 DG à 2000 m.				
Pluie-Neige				
Iso 0 °C	3 100 m	3 200 m	3 200 m	3 200 m
Vent 1500 m	↑ 10 km/h	↑ 10 km/h	↑ 10 km/h	↑ 10 km/h
Vent 2000 m	↑ 20 km/h	↑ 20 km/h	↗ 20 km/h	↗ 20 km/h

Épaisseur de neige hors-piste

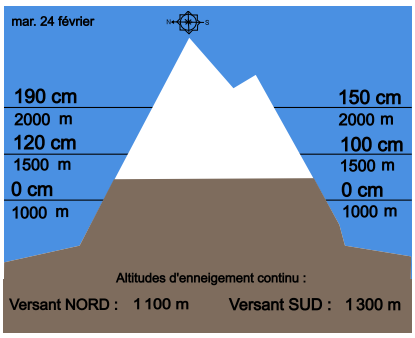

Précipitations à 1800 m

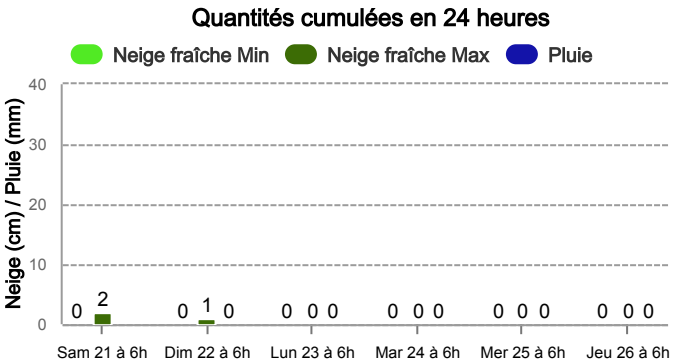

Tendance du jeudi 26 février

3

Indice de risque marqué

Douceur persistante. Encore des avalanches de neige humide, en poire ou en plaques. Risque stationnaire.

Pour consulter la vigilance en cours, veuillez vous rendre sur le site https://vigilance.meteofrance.fr/fr

Météo-France - 73 avenue de Paris, 94165 Saint-Mandé cedex - Contact : contact@meteo.fr

Rédigé par Météo-France avec la contribution des observateurs du réseau nivo-météorologiques. Partenariat : ANMSM (Maires de Stations de Montagne), DSF (Domaines Skiables de France), ADSP (Directeurs de Pistes et de la Sécurité des Stations de Sports d'Hiver) et autres acteurs de la montagne.

Bulletin neige & avalanches par téléphone au 0 892 68 10 20 Service 0,35 € / min + prix appel

Bulletin d'estimation du risque d'avalanche

(valable en dehors des pistes balisées et ouvertes)

MASSIF : Bauges

Rédigé le mardi 24 février 2026 à 16h

Conditions nivo-météo des 7 derniers jours

	mer. 18/02				jeu. 19/02				ven. 20/02				sam. 21/02				dim. 22/02				lun. 23/02				mar. 24/02			
	03h	09h	15h	21h	03h	09h	15h	21h	03h	09h	15h	21h	03h	09h	15h	21h	03h	09h	15h	21h	03h	09h	15h	21h	03h	09h	15h	21h
Météo																												
Vent (km/h)	15	25	25	60	40	40	30	45	55	35	25	25	25	25	30	30	25	25	25	20	25	20	20	30	30	25	20	20
à 2000m																												
Vent (km/h)	10	20	20	40	25	30	25	30	40	25	20	15	20	15	15	10	10	5	15	10	15	10	15	20	20	15	10	10
à 1500m																												

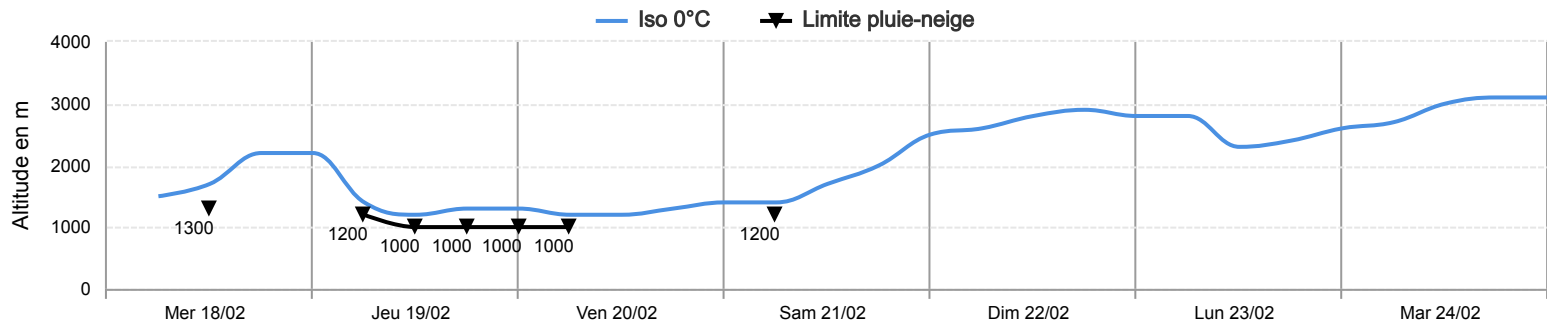

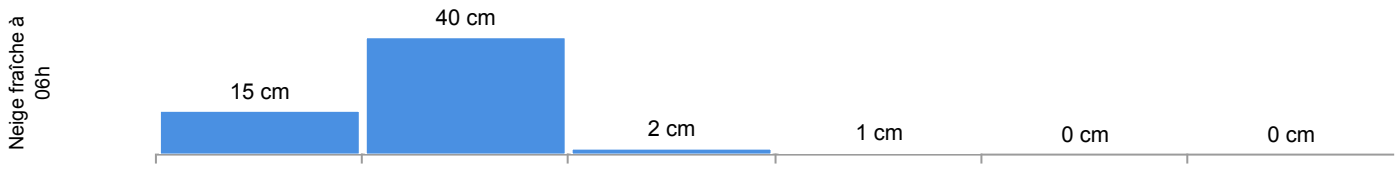

Risque d'avalanche	mer. 18/02	jeu. 19/02	ven. 20/02	sam. 21/02	dim. 22/02	lun. 23/02	mar. 24/02
	4	4	4	4	2	2	2

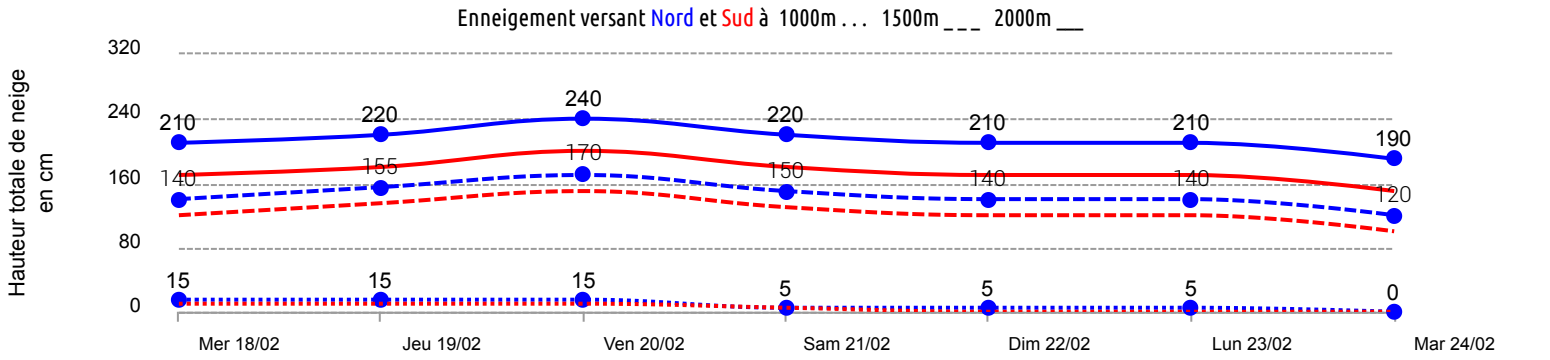

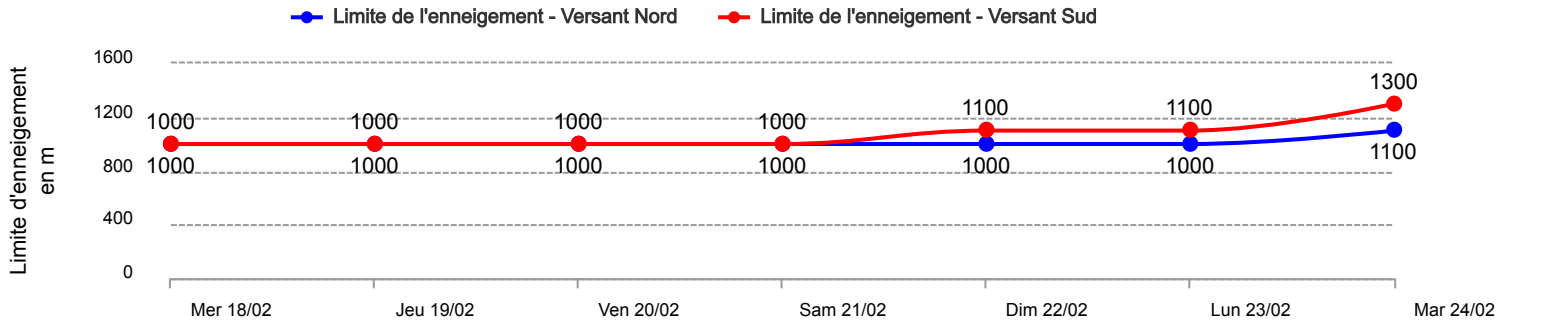

Pour consulter la vigilance en cours, veuillez vous rendre sur le site https://vigilance.meteofrance.fr/fr

Météo-France - 73 avenue de Paris, 94165 Saint-Mandé cedex - Contact : contact@meteo.fr

Bulletin neige & avalanches par téléphone au

0 892 68 10 20 Service 0,35 € / min + prix appel

Rédigé par Météo-France avec la contribution des observateurs du réseau nivo-météorologiques. Partenariat : ANMSM (Maires de Stations de Montagne), DSF (Domaines Skiables de France), ADSP (Directeurs de Pistes et de la Sécurité des Stations de Sports d'Hiver) et autres acteurs de la montagne.