Bulletin d'estimation du risque d'avalanche
(valable en dehors des pistes balisées et ouvertes)

MASSIF : Chablais

Rédigé le mardi 24 février 2026 à 16h

Estimation des risques pour le : MERCREDI 25 FÉVRIER

MANTEAU NEIGEUX RÉACTIF SOUS L'EFFET DE LA DOUCEUR

3

2→3

N O E S

Indice de risque limité évoluant en marqué.

Départs spontanés : avalanches de neige humide et plaques de fond

Déclenchements provoqués : coulée humides + rares anciennes plaques peu réactives mais épaisses

Indices de risque : 5 très fort - 4 fort - 3 marqué - 2 limité - 1 faible -- En noir : les pentes les plus dangereuses

Stabilité du manteau neigeux

Situation avalancheuse typique : neige humide — avalanches de fond

Départs spontanés :

* **nombreuses avalanches de neige humide**, dès la fin de matinée, toutes orientations en suivant la course du soleil. La plupart en forme de poire, mais localement pouvant s'élargir nettement voire entraîner une plaque en contrebas. Taille 2 (moyenne), voire 3 (grande) en cas de grande pente qui n'aurait pas encore purgé. Ces avalanches partent spontanément au réchauffement, mais aussi au passage d'un skieur. *Observables :* escargots, départs souvent près des rochers/falaises réchauffés, enfoncement piéton pour estimer le volume mobilisable.
* **plaques de fond**. Surtout l'après-midi, mais possibles à n'importe quelle heure. Sur terrains raides et lisses en herbes ou dalles rocheuses. Versants S : en dessous de 2200/2400 m. Versants N : en dessous de 2000 m. Taille 2 voire 3.

Déclenchements provoqués :

* **plaques dures sur couche fragile persistante enfouie**. Versants W/N/E, au-dessus de 2000/2200 m. Peu probables, car cette ancienne couche fragile est généralement bien enfouie et hors d'atteinte par un skieur. MAIS une première petite plaque de surface pourrait en déclencher une nettement plus épaisse (60cm/1m). Observables : aucun, sauf tests d'instabilité. Se méfier des ubacs raides qui étaient peu enneigés avant les dernières perturbations.

Autres :

* **Chutes de corniches**, épaisses et volumineuses, pouvant entraîner une plaque en contrebas.

Qualité de la neige

Enneigement : bon pour une fin février, à toutes altitudes. On peut chausser les skis vers 1200 m. Épaisseur du manteau neigeux hétérogène : fort tassement sous l'effet de la douceur, grosses corniches et accumulations, crêtes érodées par les forts vents pendant et après les perturbations (de SW puis NW).

Qualité de la neige mercredi :

* sous 2000/2300 m : neige très dense, fine croûte cassante le matin, s'humidifiant rapidement. Tendance à l'humidification en profondeur.
* au-dessus de 2200/2400 m : variable, neige dense, encore assez froide voire poudreuse plein N. Humidification superficielle en adrets. Cartonnée dans les secteurs qui ont été exposés aux vents de W/NW/N.

Aperçu météo pour le mercredi 25 février

Soleil et grande douceur. Maximales +8 DG à 2000 m.

	nuit	matin	après-midi	soir
Pluie-Neige				
Iso 0 °C	3 000 m	3 000 m	3 000 m	3 000 m
Vent 2000 m	← 5 km/h	↑ 10 km/h	↗ 10 km/h	↗ 10 km/h
Vent 2500 m	← 15 km/h	↑ 15 km/h	↗ 15 km/h	↗ 15 km/h

Épaisseur de neige hors-piste

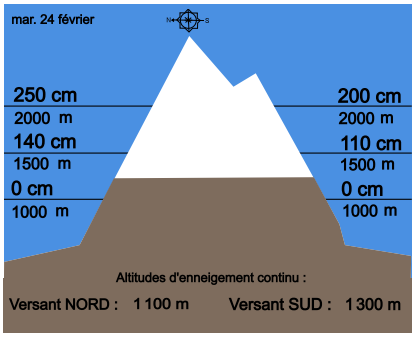

Précipitations à 1800 m

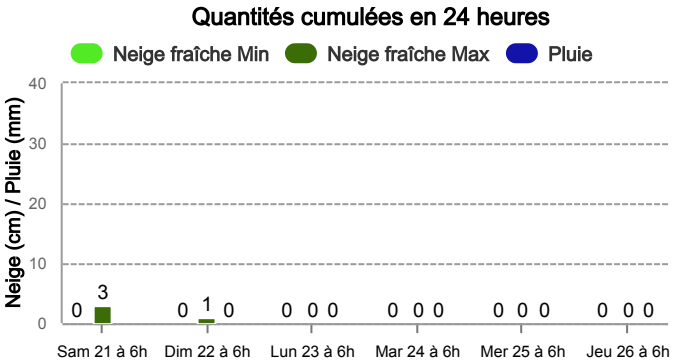

Tendance du jeudi 26 février

3

Indice de risque marqué

Douceur persistante. Encore des avalanches de neige humide, en poire ou en plaques, surtout en fin de matinée et après-midi.

Pour consulter la vigilance en cours, veuillez vous rendre sur le site https://vigilance.meteofrance.fr/fr

Météo-France - 73 avenue de Paris, 94165 Saint-Mandé cedex - Contact : contact@meteo.fr

Rédigé par Météo-France avec la contribution des observateurs du réseau nivo-météorologiques. Partenariat : ANMSM (Maires de Stations de Montagne), DSF (Domaines Skiables de France), ADSP (Directeurs de Pistes et de la Sécurité des Stations de Sports d'Hiver) et autres acteurs de la montagne.

Bulletin neige & avalanches par téléphone au 0 892 68 10 20 Service 0,35 € / min + prix appel

RÉPUBLIQUE FRANÇAISE
Liberté Égalité Fraternité

METEO FRANCE
À VOS CÔTÉS, DANS UN CLIMAT QUI CHANGE

Bulletin d'estimation du risque d'avalanche

(valable en dehors des pistes balisées et ouvertes)

MASSIF : Chablais

Rédigé le mardi 24 février 2026 à 16h

Conditions nivo-météo des 7 derniers jours

	mer. 18/02				jeu. 19/02				ven. 20/02				sam. 21/02				dim. 22/02				lun. 23/02				mar. 24/02			
	03h	09h	15h	21h	03h	09h	15h	21h	03h	09h	15h	21h	03h	09h	15h	21h	03h	09h	15h	21h	03h	09h	15h	21h	03h	09h	15h	21h
Météo																												
Vent (km/h)	30	55	50	60	50	60	50	50	40	35	35	35	40	40	35	35	35	40	45	45	30	25	25	25	30	25	20	20
à 2500m																												
Vent (km/h)	20	45	40	50	35	50	40	40	30	20	20	20	20	20	20	20	25	25	25	25	25	15	15	15	20	15	15	10
à 2000m																												

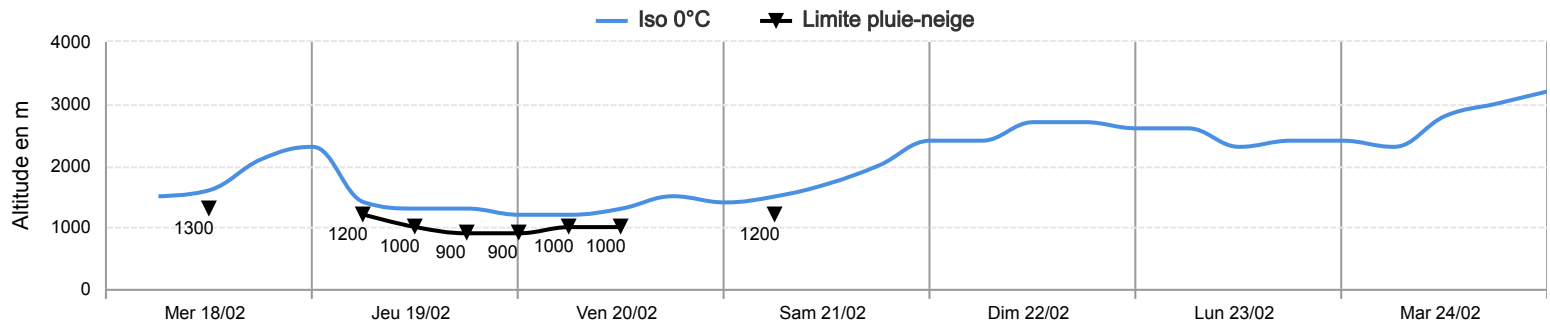

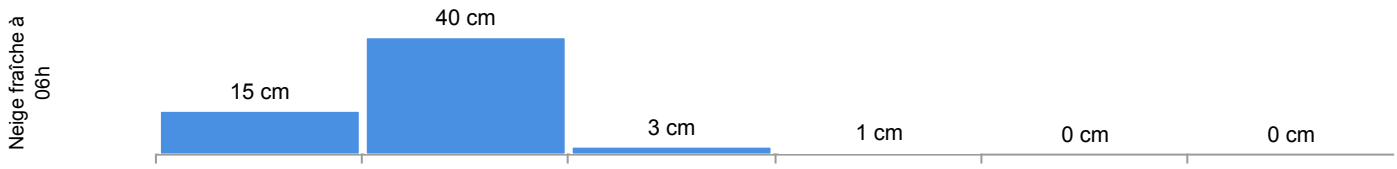

Risque d'avalanche	mer. 18/02	jeu. 19/02	ven. 20/02	sam. 21/02	dim. 22/02	lun. 23/02	mar. 24/02
	4	4	4	4	3	2	3

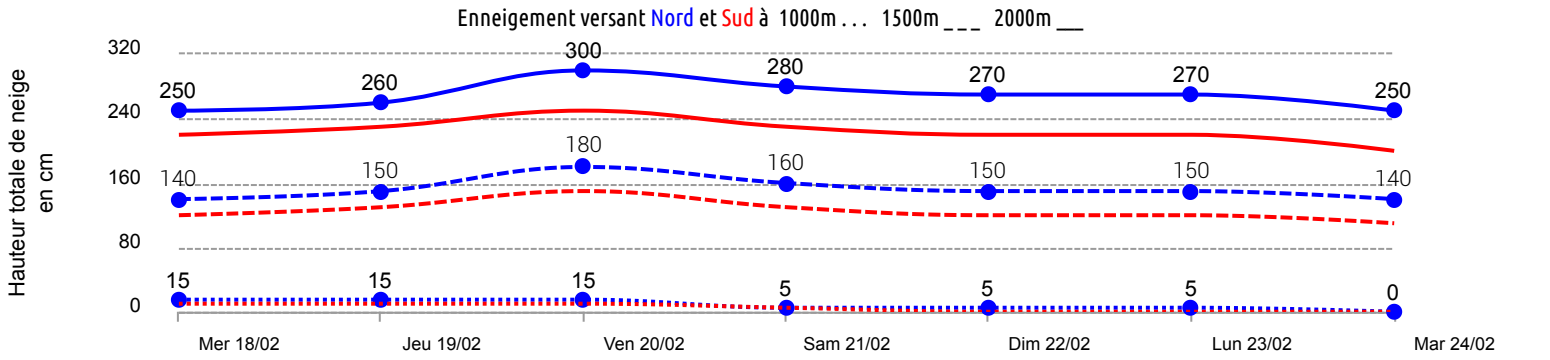

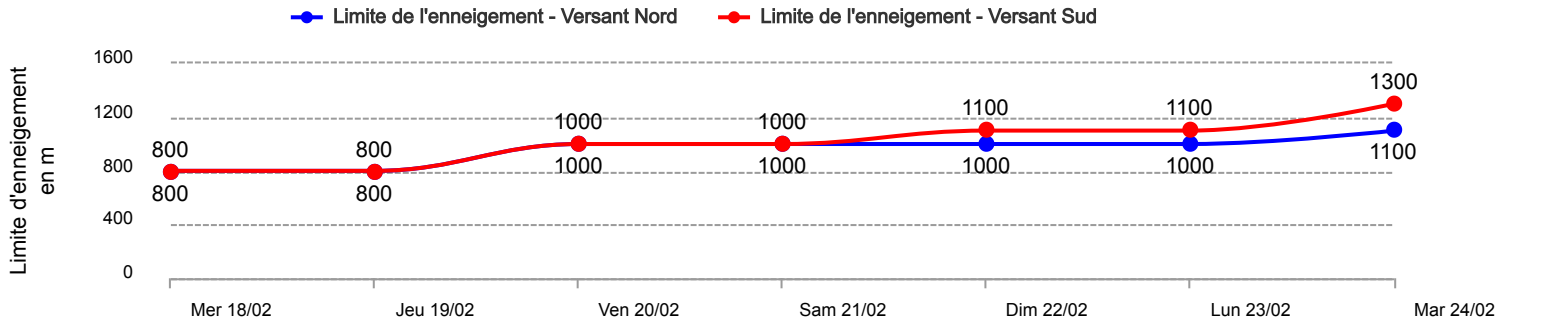

Pour consulter la vigilance en cours, veuillez vous rendre sur le site https://vigilance.meteofrance.fr/fr

Météo-France - 73 avenue de Paris, 94165 Saint-Mandé cedex - Contact : contact@meteo.fr

Bulletin neige & avalanches par téléphone au

0 892 68 10 20 Service 0,35 € / min + prix appel

Rédigé par Météo-France avec la contribution des observateurs du réseau nivo-météorologiques. Partenariat : ANMSM (Maires de Stations de Montagne), DSF (Domaines Skiables de France), ADSP (Directeurs de Pistes et de la Sécurité des Stations de Sports d'Hiver) et autres acteurs de la montagne.