Bulletin d'estimation du risque d'avalanche

(valable en dehors des pistes balisées et ouvertes)

MASSIF : Couserans

Rédigé le mardi 24 Février 2026 à 16h

Estimation des risques pour le : MERCREDI 25 FÉVRIER

JOURNÉE PRINTANIÈRE.

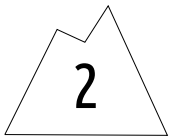

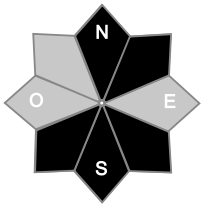

Indice de risque limité.

Départs spontanés : avalanches de neige humide ou avalanches de fond au soleil, taille 1 ou 2, exceptionnellement 3.

Déclenchements provoqués : Rares structures de plaques en nord/nord est au delà de 2100/2200 m.

Indices de risque : 5 très fort - 4 fort - 3 marqué - 2 limité - 1 faible -- En noir : les pentes les plus dangereuses

Stabilité du manteau neigeux

Situation avalancheuse typique : neige humide avalanches de fond

Départs spontanés :
Activité avalancheuse qui devrait augmenter classiquement au fil de la journée dans les pentes raides prenant le soleil, et notamment à proximités des rochers. Départs d'avalanches petites à moyennes, plus rarement grandes, avec l'humidification qui se généralise au soleil à des altitudes élevées.
Coulées ou avalanches pouvant ponctuellement terminer dans un fond de vallon, plutôt dans l'après-midi.
Présence éventuelle de larges fissures dans les pentes au sol lisse, signes avant-coureurs d'une éventuelle avalanche de glissement pouvant en revanche se produire à tout moment.

Déclenchements provoqués :
Au-delà de 2000/2100 m, présence éventuelle de quelques structures de plaques isolées, déclenchables par un skieur dans quelques secteurs ou combes raides orientées nord à nord-est très ombragés, pouvant donner des avalanches de taille petite à moyenne en cas de déclenchement (taille 1 à 2). Observables : neige travaillée par le vent en surface, bruit d'effondrements sous les skis, couche de neige sans cohésion à 20/40 cm de la surface sans croute de regel.

Autre : La neige a pris des allures printanières dans de nombreux secteurs avec un risque accru de glissade sur de la neige dure ou glacée en matinée après un bon regel nocturne, parfois encore plus tardivement en versant ouest.

Qualité de la neige

Enneigement :
L'enneigement est excédentaire par rapport aux normales pour la période avec les passages neigeux successifs depuis janvier. Les vallons ombragés sont encore bien enneigés avec des quantités de neige importantes dès 1400 m, avec une limite d'enneigement skiable évoluant pour le moment assez peu (1200/1300).
Au soleil, le manteau neigeux perd un peu d'épaisseur depuis quelques jours, mais l'enneigement reste exploitable dès 1400/1500 m.

Qualité de la neige :
Mardi matin, en toutes orientations, sous 2100 m, on devrait retrouver une neige bien regelée en surface, éventuellement croutée et non portante en nord en dessous de 2000 m.
En cours de journée, neige plus ou moins lourde et humidifiée en profondeur dans un large secteur sud, encore dure ou glacée sur les crêtes dans un large secteur nord et sur les flancs ouest.
Quelques champs de poudreuse ou neige sèche résistent dans les combes très ombragées.

Aperçu météo pour le mercredi 25 février

	nuit	matin	après-midi	soir
Journée ensoleillée dans une atmosphère très douce.				
Pluie-Neige				
Iso 0 °C	3 300 m	3 200 m	3 100 m	3 100 m
Vent 2000 m	15 km/h	20 km/h	25 km/h	20 km/h
Vent 3000 m	25 km/h	35 km/h	35 km/h	30 km/h

Pour consulter la vigilance en cours, veuillez vous rendre sur le site https://vigilance.meteofrance.fr/fr

Météo-France - 73 avenue de Paris, 94165 Saint-Mandé cedex - Contact : contact@meteo.fr

Rédigé par Météo-France avec la contribution des observateurs du réseau nivo-météorologiques. Partenariat : ANMSM (Maires de Stations de Montagne), DSF (Domaines Skiables de France), ADSP (Directeurs de Pistes et de la Sécurité des Stations de Sports d'Hiver) et autres acteurs de la montagne.

Bulletin neige & avalanches par téléphone au 0 892 68 10 20 Service 0,35 € / min + prix appel

RÉPUBLIQUE FRANÇAISE
Liberté Égalité Fraternité

METEO FRANCE
À VOS CÔTÉS, DANS UN CLIMAT QUI CHANGE

Bulletin d'estimation du risque d'avalanche

(valable en dehors des pistes balisées et ouvertes)

MASSIF : Couserans

Rédigé le mardi 24 février 2026 à 16h

Épaisseur de neige hors-piste

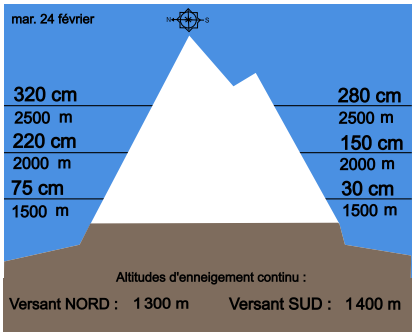

Précipitations à 1800 m

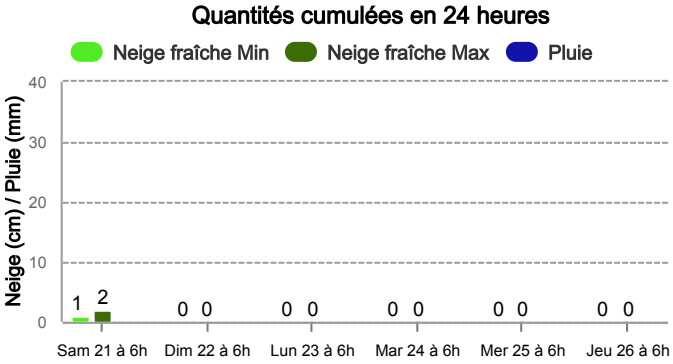

Tendance du jeudi 26 février

Indice de risque limité

Stationnaires.

Pour consulter la vigilance en cours, veuillez vous rendre sur le site https://vigilance.meteofrance.fr/fr

Météo-France - 73 avenue de Paris, 94165 Saint-Mandé cedex - Contact : contact@meteo.fr

Rédigé par Météo-France avec la contribution des observateurs du réseau nivo-météorologiques. Partenariat : ANMSM (Maires de Stations de Montagne), DSF (Domaines Skiables de France), ADSP (Directeurs de Pistes et de la Sécurité des Stations de Sports d'Hiver) et autres acteurs de la montagne.

Bulletin neige & avalanches par téléphone au

0 892 68 10 20 Service 0,35 € / min + prix appel

RÉPUBLIQUE FRANÇAISE
Liberté Égalité Fraternité

METEO FRANCE
À VOS CÔTÉS, DANS UN CLIMAT QUI CHANGE

Bulletin d'estimation du risque d'avalanche

(valable en dehors des pistes balisées et ouvertes)

MASSIF : Couserans

Rédigé le mardi 24 février 2026 à 16h

Conditions nivo-météo des 7 derniers jours

	mer. 18/02				jeu. 19/02				ven. 20/02				sam. 21/02				dim. 22/02				lun. 23/02				mar. 24/02			
	03h	09h	15h	21h	03h	09h	15h	21h	03h	09h	15h	21h	03h	09h	15h	21h	03h	09h	15h	21h	03h	09h	15h	21h	03h	09h	15h	21h
Météo																												
Vent (km/h)	30	55	75	65	80	70	70	75	65	65	55	50	45	35	30	25	15	10	10	15	15	15	15	15	20	20	20	20
à 3000m	↓	↑	↑	→	↘	↓	↓	↓	↓	↓	↓	↓	↓	↓	↓	↓	↑	→	↘	↓	↓	↓	↓	↓	↗	↑	↑	↑
Vent (km/h)	20	25	60	45	50	45	45	40	35	35	30	30	25	20	20	15	10	10	10	10	10	10	10	10	10	10	10	10
à 2000m	→	↑	↗	↘	↘	↓	↓	↓	↓	↓	↓	↓	↓	↓	↓	↓	↑	↑	→	→	↗	→	→	↑	↑	↑	↑	↗

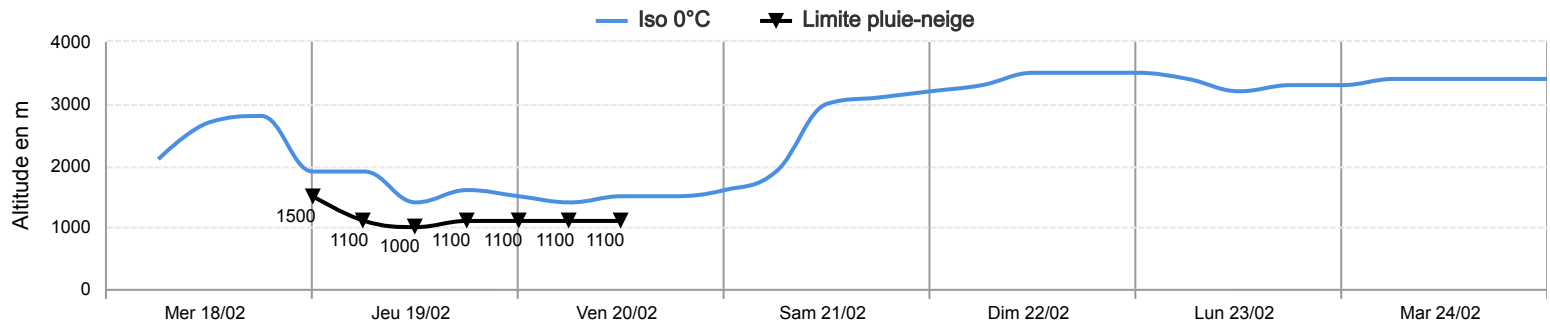

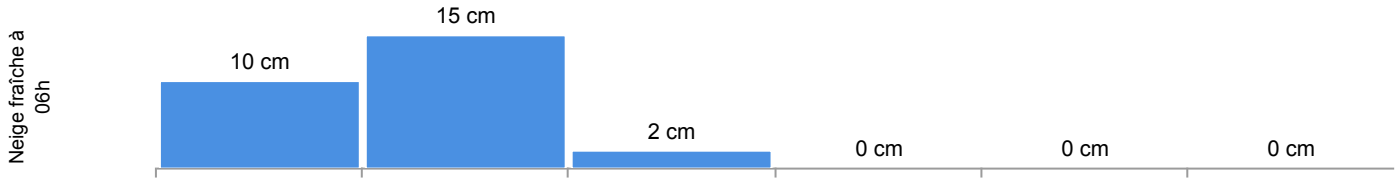

Risque d'avalanche	mer. 18/02	jeu. 19/02	ven. 20/02	sam. 21/02	dim. 22/02	lun. 23/02	mar. 24/02
	3	3	3	3	3	3	2

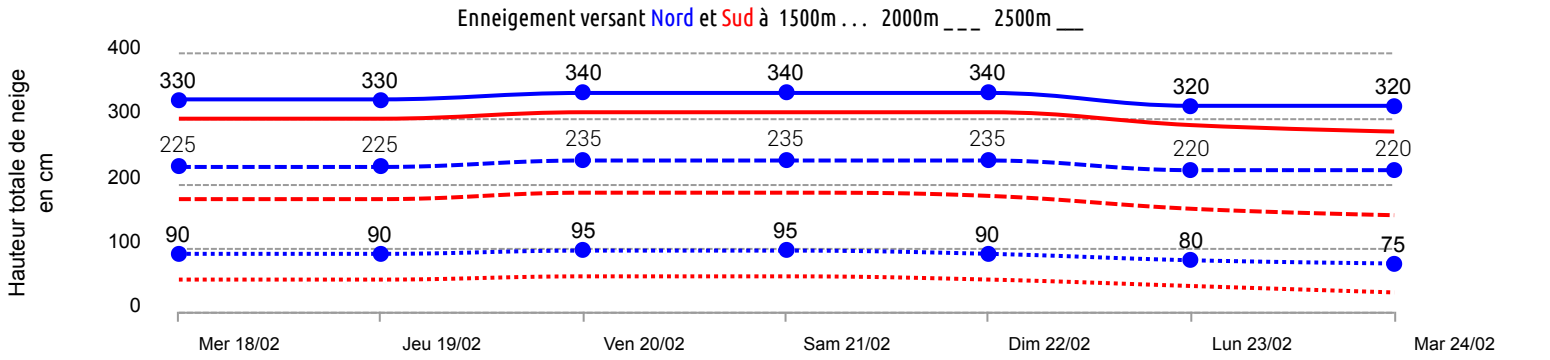

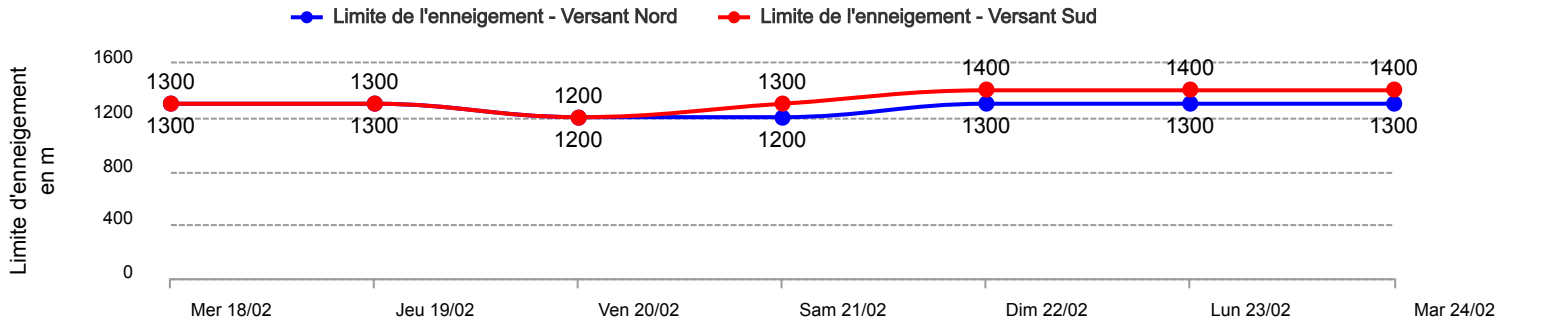

Pour consulter la vigilance en cours, veuillez vous rendre sur le site https://vigilance.meteofrance.fr/fr

Météo-France - 73 avenue de Paris, 94165 Saint-Mandé cedex - Contact : contact@meteo.fr

Rédigé par Météo-France avec la contribution des observateurs du réseau nivo-météorologiques. Partenariat : ANMSM (Maires de Stations de Montagne), DSF (Domaines Skiables de France), ADSP (Directeurs de Pistes et de la Sécurité des Stations de Sports d'Hiver) et autres acteurs de la montagne.

Bulletin neige & avalanches par téléphone au
0 892 68 10 20 Service 0,35 € / min + prix appel