Bulletin d'estimation du risque d'avalanche
(valable en dehors des pistes balisées et ouvertes)

MASSIF : Devoluy

Rédigé le mardi 24 Février 2026 à 16h

Estimation des risques pour le : MERCREDI 25 FÉVRIER

ACTIVITÉ NATURELLE EN NEIGE HUMIDE AU SOLEIL MOBILISANT PARFOIS DE GRANDES QUANTITÉS DE NEIGE - RARES PLAQUES MAIS POTENTIELLEMENT ÉPAISSES

3

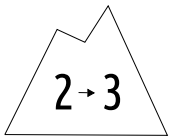

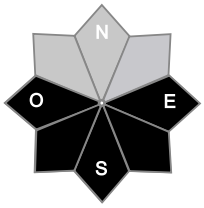

Indice de risque limité évoluant en marqué.

Départs spontanés : avalanches de neige humide, départs ponctuels ou linéaires, parfois volumineux.

Déclenchements provoqués : rares plaques en ubacs d'altitude, mais pouvant être de grandes dimensions.

Indices de risque : 5 très fort - 4 fort - 3 marqué - 2 limité - 1 faible -- En noir : les pentes les plus dangereuses

Stabilité du manteau neigeux

Situation avalancheuse typique : neige humide

Départs spontanés : * Activité naturelle en neige humide en hausse au fil de la journée, influencée par la course du soleil. Départs initiés souvent près des rochers ou des barres, pouvant mobiliser des volumes de neige importants sous 2200/2400 m, en emportant parfois une grande partie du manteau neigeux en place. Avalanches moyennes à grandes (taille 2 à 3), descendant parfois à basse altitude dans les couloirs habituels. Départ linéaire possible.
* Quelques plaques de fond peuvent céder spontanément à toute heure du jour ou de la nuit en terrain favorable (dalles lisses, sols herbeux). Avalanches moyennes à grandes (taille 2 à 3).
* Une première petite avalanche superficielle de neige humide ou la chute d'une corniche peut engendrer un départ de plaque en contrebas.

Déclenchements provoqués : * Les plaques de surfaces formées lors des derniers épisodes de vent sont pour la plupart stabilisées. Déclenchement désormais plus rare et pouvant engendrer une avalanche petite à moyenne (taille 1 à 2).
* Dans les ubacs au-dessus de 2200/2300 m, le déclenchement d'une plaque plus large et plus épaisse ne peut être exclu, en cas de sollicitation de la couche fragile persistante enfouie à la base du manteau neigeux. Probabilité de déclenchement faible en général, concentrée au niveau des discontinuités de terrain (croupes, rochers affleurants, etc.), là où les épaisseurs de neige sont moins importantes et isolent un peu moins la couche fragile enfouie à la base du manteau neigeux.

Qualité de la neige

L'enneigement est très excédentaire pour un mois de février.

Limite d'enneigement skiable dès 1100/1200 m sur terrain favorable, mais la neige fond rapidement en adrets raides et devient un peu juste sous 1600 m.

État de la neige de surface : * En adrets, manteau neigeux désormais bien printanier jusqu'à très haute altitude, petite croûte le matin, puis humidification au soleil l'après-midi, sur une grande épaisseur dans les pentes raides bien exposées.
* En ubacs (nord-ouest à nord-est), croûte de quelques cm le matin sous 2200 m environ sur les zones peu pentues, s'humidifiant en cours de journée. Ailleurs, la neige est soit cartonnée/durcie par les épisodes de vent passés, ou en poudreuse dense dans les combes ou pentes abritées.

Aperçu météo pour le mercredi 25 février

nuit	matin	après-midi	soir

Le printemps est bien installé : soleil, fins voiles nuageux d'altitude et températures très élevées pour une fin février, 12/13 °C à 2000 m l'après-midi.

Pluie-Neige				
Iso 0 °C	3 200 m	3 200 m	3 100 m	3 200 m
Vent 2000 m	↖ 10 km/h	↑ 15 km/h	↑ 20 km/h	↑ 15 km/h
Vent 3000 m	↗ 10 km/h	↑ 10 km/h	↑ 15 km/h	↑ 20 km/h

Épaisseur de neige hors-piste

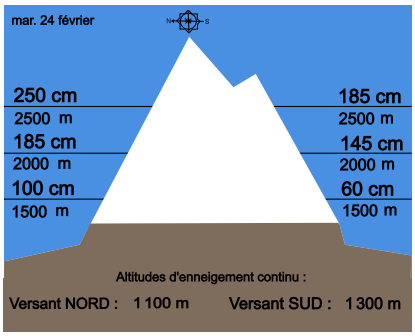

Précipitations à 1800 m

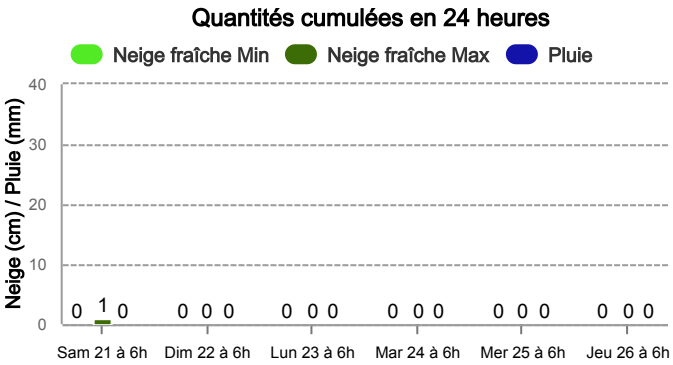

Tendance du jeudi 26 février

3

Indice de risque marqué

L'activité en neige humide est à nouveau en hausse en cours de journée. Avalanches moyennes à grandes attendues. Maintien probable d'un risque marqué.

Pour consulter la vigilance en cours, veuillez vous rendre sur le site https://vigilance.meteofrance.fr/fr

Météo-France - 73 avenue de Paris, 94165 Saint-Mandé cedex - Contact : contact@meteo.fr

Rédigé par Météo-France avec la contribution des observateurs du réseau nivo-météorologiques. Partenariat : ANMSM (Maires de Stations de Montagne), DSF (Domaines Skiables de France), ADSP (Directeurs de Pistes et de la Sécurité des Stations de Sports d'Hiver) et autres acteurs de la montagne.

Bulletin neige & avalanches par téléphone au 0 892 68 10 20 Service 0,35 € / min + prix appel

RÉPUBLIQUE FRANÇAISE
Liberté Égalité Fraternité

METEO FRANCE
À VOS CÔTÉS, DANS UN CLIMAT QUI CHANGE

Bulletin d'estimation du risque d'avalanche

(valable en dehors des pistes balisées et ouvertes)

MASSIF : Devoluy

Rédigé le mardi 24 février 2026 à 16h

Conditions nivo-météo des 7 derniers jours

	mer. 18/02				jeu. 19/02				ven. 20/02				sam. 21/02				dim. 22/02				lun. 23/02				mar. 24/02			
	03h	09h	15h	21h	03h	09h	15h	21h	03h	09h	15h	21h	03h	09h	15h	21h	03h	09h	15h	21h	03h	09h	15h	21h	03h	09h	15h	21h
Météo																												
Vent (km/h)	50	35	40	65	50	55	70	75	80	90	80	80	80	80	80	60	40	35	35	40	45	50	60	60	50	25	15	5
à 3000m																												
Vent (km/h)	40	20	20	45	45	30	40	55	75	60	60	60	45	60	60	40	25	15	15	15	20	40	40	30	35	20	10	10
à 2000m																												

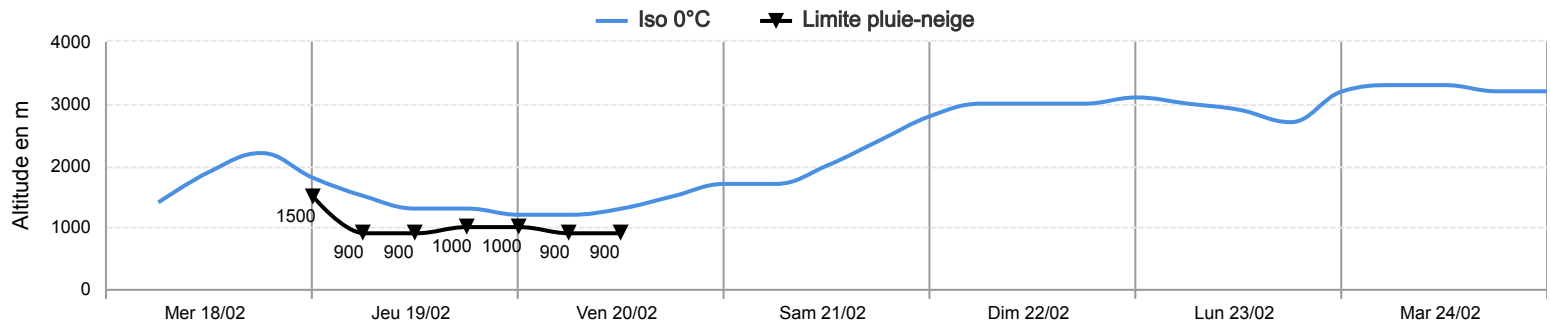

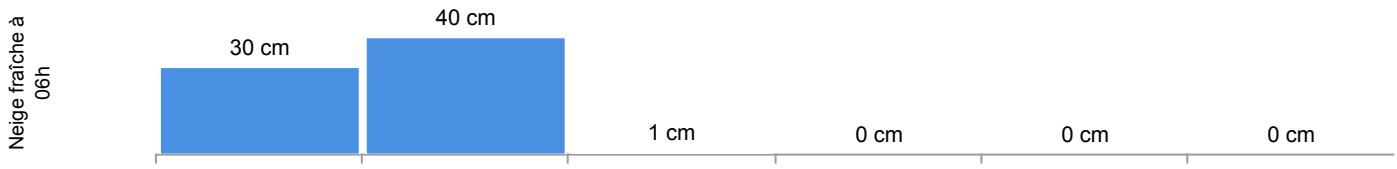

Risque d'avalanche	mer. 18/02	jeu. 19/02	ven. 20/02	sam. 21/02	dim. 22/02	lun. 23/02	mar. 24/02
	4	4	4	4	3	3	3

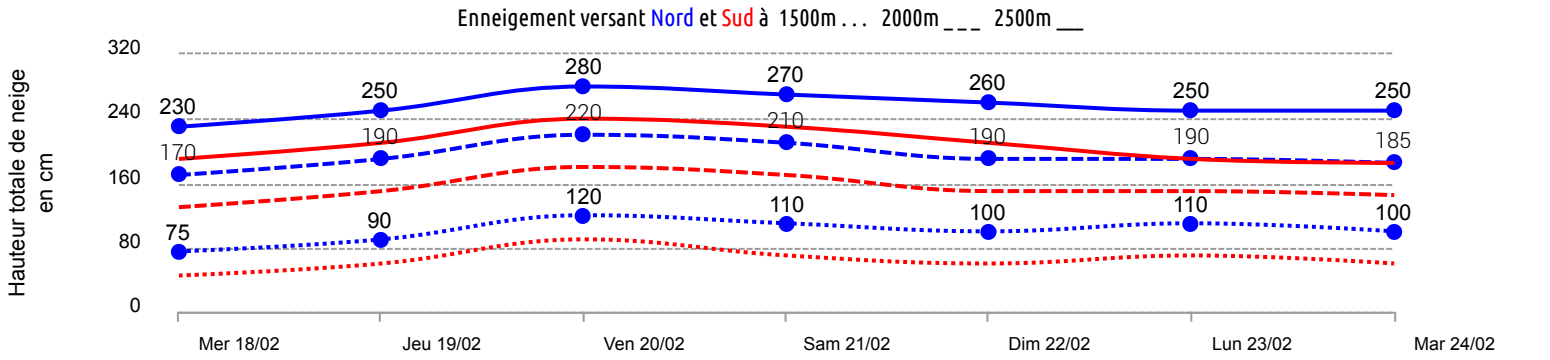

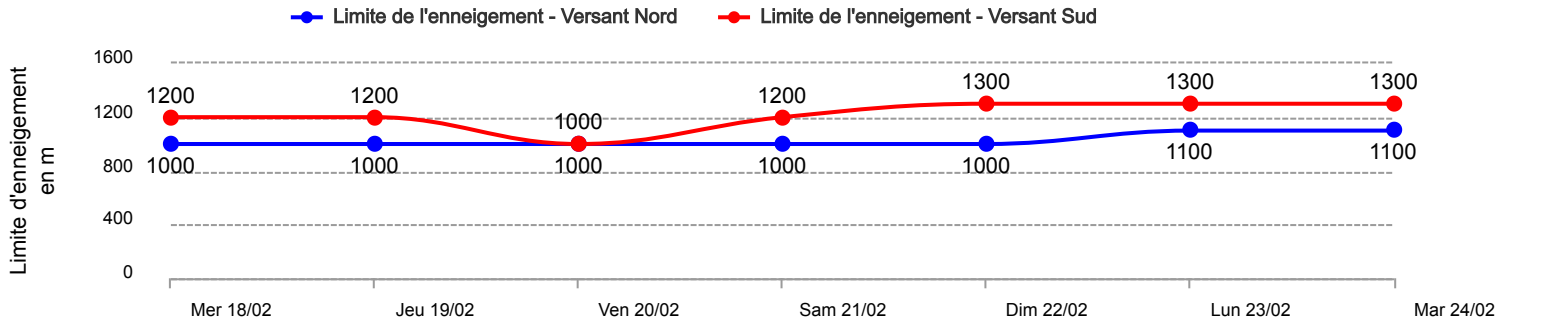

Pour consulter la vigilance en cours, veuillez vous rendre sur le site https://vigilance.meteofrance.fr/fr

Météo-France - 73 avenue de Paris, 94165 Saint-Mandé cedex - Contact : contact@meteo.fr

Bulletin neige & avalanches par téléphone au **0 892 68 10 20** Service 0,35 € / min + prix appel

Rédigé par Météo-France avec la contribution des observateurs du réseau nivo-météorologiques. Partenariat : ANMSM (Maires de Stations de Montagne), DSF (Domaines Skiables de France), ADSP (Directeurs de Pistes et de la Sécurité des Stations de Sports d'Hiver) et autres acteurs de la montagne.