Bulletin d'estimation du risque d'avalanche

(valable en dehors des pistes balisées et ouvertes)

MASSIF : Haut-Var Haut-Verdon

Rédigé le mardi 24 février 2026 à 16h

Estimation des risques pour le : MERCREDI 25 FÉVRIER

DÉPARTS NATURELS EN NEIGE HUMIDE - PLAQUES RÉSIDUELLES DANS LA NEIGE VENTÉE EN ALTITUDE

3

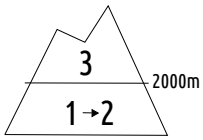

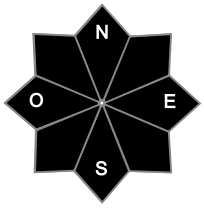

Au-dessus de 2000m indice de risque marqué, plus bas indice faible évoluant en limité.

Départs spontanés : en neige humide, devenant nombreux dans les versants ensoleillés au fil de la journée.

Déclenchements provoqués : instabilités résiduelles dans la neige ventée en altitude.

Indices de risque : 5 très fort - 4 fort - 3 marqué - 2 limité - 1 faible -- En noir : les pentes les plus dangereuses

Stabilité du manteau neigeux

Situation avalancheuse typique : neige humide couche fragile persistante

Départs spontanés : en neige humide. Peu probables en début de journée puis devenant fréquents en cours de journée au fil de l'ensoleillement. Ils se produisent en pentes raides ensoleillées à toutes altitudes, notamment près des rochers. Avalanches de taille petite à moyenne (taille 1 à 2), voire grande (taille 3), jusqu'à 2500/2600 m où le manteau neigeux s'est déjà bien humidifié en profondeur. Des avalanches moyennes à grandes sont également possibles en cas de reptations déjà ouvertes ou suite à la rupture d'une corniche. Ces avalanches sont rares, mais peuvent atteindre des altitudes relativement basses et toucher des fonds de vallées ou chemins en contrebas.

Déclenchements provoqués :
— Instabilités résiduelles dans la neige ventée, plus fréquentes en versants nord-ouest à sud-est au-dessus de 2000 m environ. D'aspect durci par le vent à proximité des crêtes, voire en neige humide, elles sont généralement facilement identifiables. Elles deviennent difficiles à déclencher par un skieur, mais peuvent engendrer des avalanches de taille petite à moyenne (taille 1 à 2).
— Dans le Haut-Verdon en orientations ouest, nord et est d'altitude supérieure à 2000/2200 m environ, une rare grande, voire très grande avalanche (taille 3 à 4) est possible, par sollicitation d'une couche fragile persistante enfouie à la base du manteau neigeux. Déclenchement difficile au passage d'un skieur, mais possible là où le manteau neigeux est moins épais (croupes, bords de couloirs), ou en cascade après un premier départ en surface.
— Des départs sous les skis de neige fortement humidifiée sont possibles en versant raides ensoleillés en cours de journée. Avalanches de taille petite à moyenne (taille 1 à 2).

Qualité de la neige

Enneigement très excédentaire pour un mois de février.
Données observées : en ubacs, 90/100 cm dès 1700/1800 m, 131 cm vers les Cabanes de Sanguinière (2040 m) et 178 vers la Maison Forestière de Valdemars à 2020 m d'altitude.

Enneigement skiable dès 1300/1400 m en terrains favorables, 1600 m en adrets.

État de la neige en surface : neige croutée le matin après un regel nocturne correct, s'humidifiant rapidement en journée au fil de l'ensoleillement. On retrouve de la neige encore poudreuse en Ubacs au-dessus de 1800/2000 m environ, souvent travaillée/durcie par le vent de nord. Zones dégarnies proches des crêtes, alternant avec des corniches parfois épaisses.

Aperçu météo pour le mercredi 25 février

	nuit	matin	après-midi	soir

Temps généralement bien ensoleillé et lumineux malgré quelques passages nuageux de haute altitude.

Pluie-Neige				
Iso 0 °C	3 100 m	3 100 m	3 100 m	3 100 m
Vent 2000 m	← 10 km/h	← 5 km/h	↑ 5 km/h	← 5 km/h
Vent 3000 m	↖ 15 km/h	→ 10 km/h	↖ 10 km/h	→ 10 km/h

Épaisseur de neige hors-piste

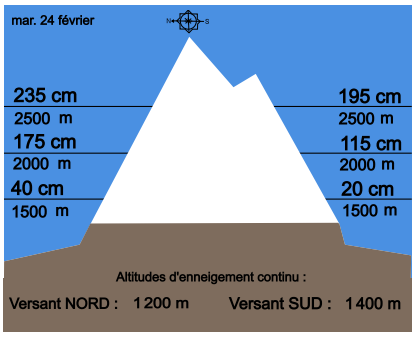

Précipitations à 1800 m

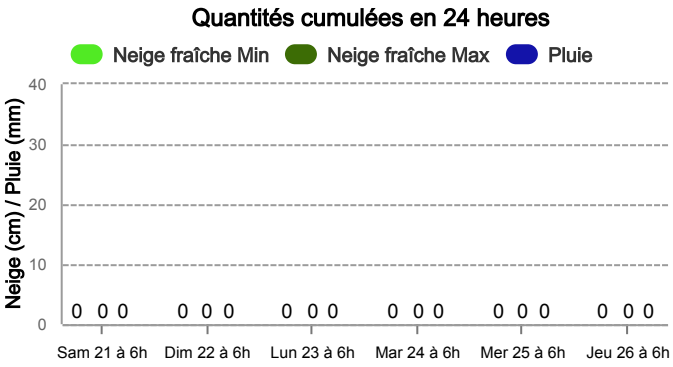

Tendance du jeudi 26 février

3 **Indice de risque marqué**

Maintien d'un risque marqué. La présence de couches fragiles en ubacs maintient la possibilité d'avalanches de grande taille. Poursuite de l'humidification avec toujours des départs spontanés nombreux en cours de journée dans les versants ensoleillés.

Pour consulter la vigilance en cours, veuillez vous rendre sur le site https://vigilance.meteofrance.fr/fr

Météo-France - 73 avenue de Paris, 94165 Saint-Mandé cedex - Contact : contact@meteo.fr

Rédigé par Météo-France avec la contribution des observateurs du réseau nivo-météorologiques. Partenariat : ANMSM (Maires de Stations de Montagne), DSF (Domaines Skiables de France), ADSP (Directeurs de Pistes et de la Sécurité des Stations de Sports d'Hiver) et autres acteurs de la montagne.

Bulletin neige & avalanches par téléphone au **0 892 68 10 20** Service 0,35 € / min + prix appel

RÉPUBLIQUE FRANÇAISE
Liberté Égalité Fraternité

METEO FRANCE
À VOS CÔTÉS, DANS UN CLIMAT QUI CHANGE

Bulletin d'estimation du risque d'avalanche

(valable en dehors des pistes balisées et ouvertes)

MASSIF : Haut-Var Haut-Verdon

Rédigé le mardi 24 février 2026 à 16h

Conditions nivo-météo des 7 derniers jours

	mer. 18/02				jeu. 19/02				ven. 20/02				sam. 21/02				dim. 22/02				lun. 23/02				mar. 24/02			
	03h	09h	15h	21h	03h	09h	15h	21h	03h	09h	15h	21h	03h	09h	15h	21h	03h	09h	15h	21h	03h	09h	15h	21h	03h	09h	15h	21h
Météo																												
Vent (km/h)	45	40	35	65	50	55	85	85	90	75	50	30	55	60	55	40	40	40	45	50	45	40	30	25	35	25	10	10
à 3000m																												
Vent (km/h)	30	30	15	40	30	45	55	60	50	35	20	20	20	20	25	20	20	25	25	25	30	30	25	15	15	10	5	5
à 2000m																												

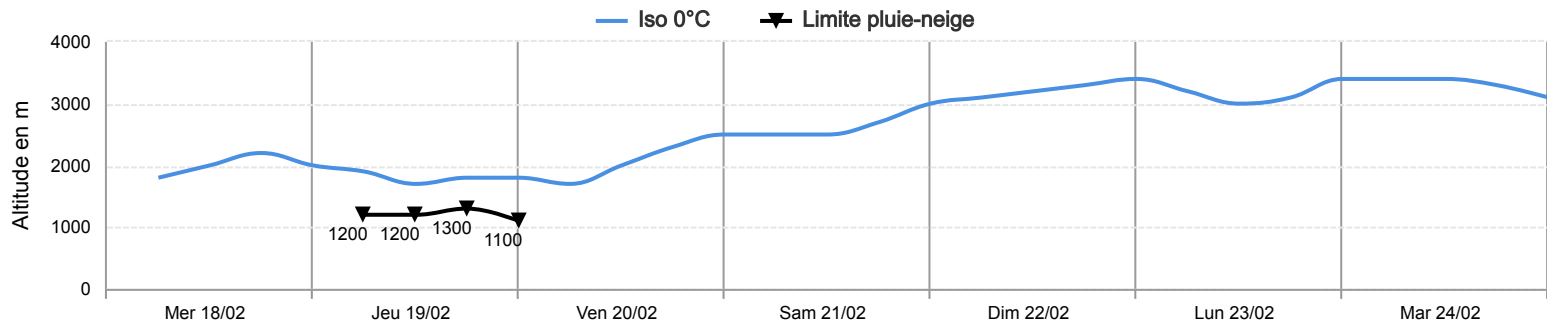

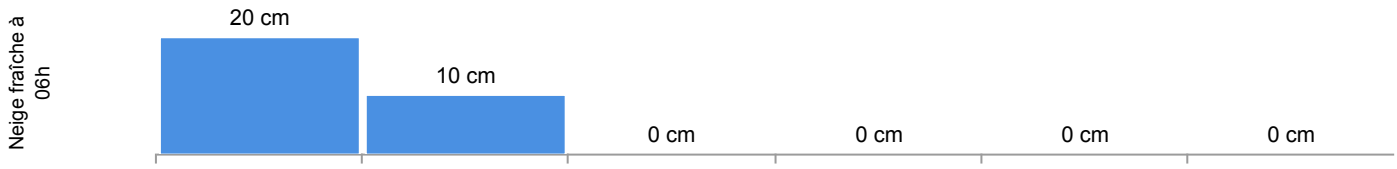

Risque d'avalanche	mer. 18/02	jeu. 19/02	ven. 20/02	sam. 21/02	dim. 22/02	lun. 23/02	mar. 24/02
	3	4	3	3	3	3	3

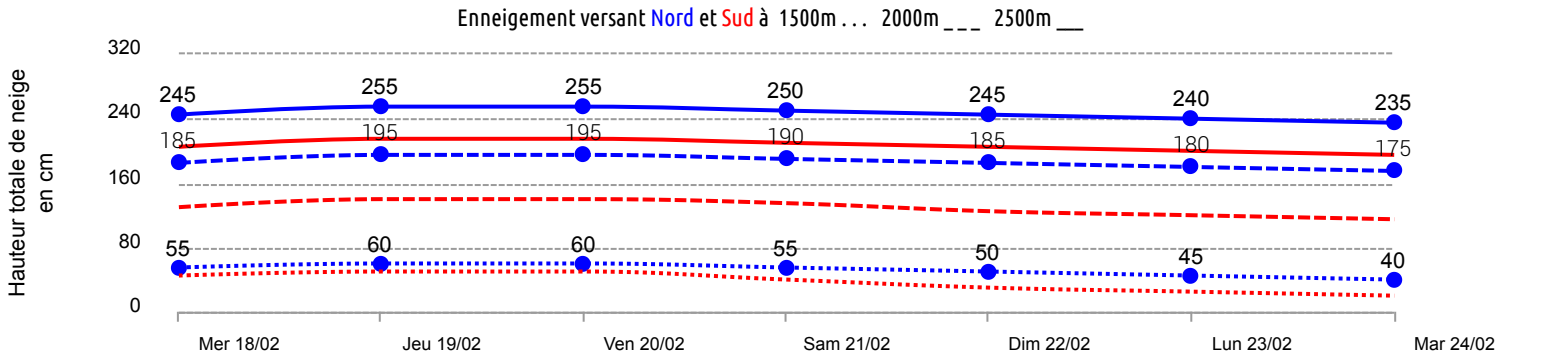

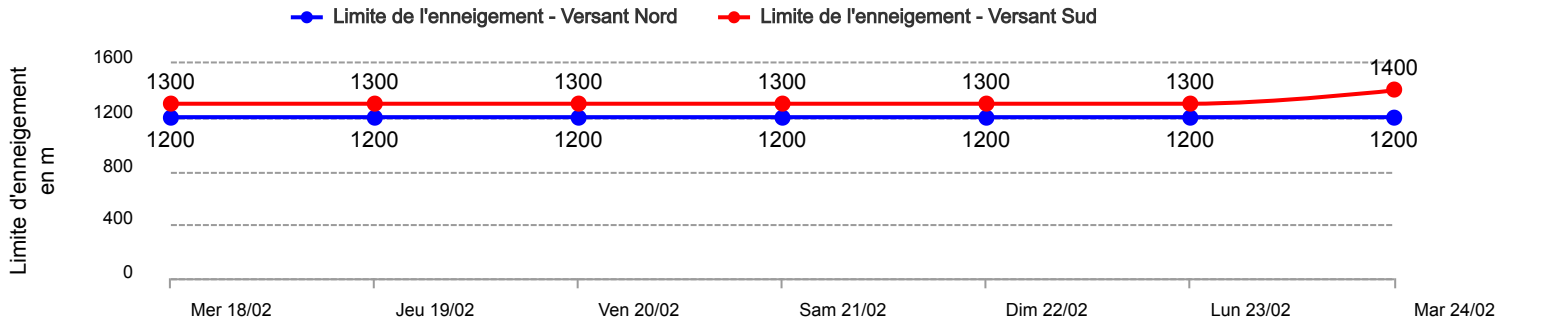

Pour consulter la vigilance en cours, veuillez vous rendre sur le site https://vigilance.meteofrance.fr/fr

Météo-France - 73 avenue de Paris, 94165 Saint-Mandé cedex - Contact : contact@meteo.fr

Rédigé par Météo-France avec la contribution des observateurs du réseau nivo-météorologiques. Partenariat : ANMSM (Maires de Stations de Montagne), DSF (Domaines Skiables de France), ADSP (Directeurs de Pistes et de la Sécurité des Stations de Sports d'Hiver) et autres acteurs de la montagne.

Bulletin neige & avalanches par téléphone au

0 892 68 10 20 Service 0,35 € / min + prix appel