Bulletin d'estimation du risque d'avalanche

(valable en dehors des pistes balisées et ouvertes)

MASSIF : Haute-Bigorre

Rédigé le mardi 24 février 2026 à 16h

Estimation des risques pour le : MERCREDI 25 FÉVRIER

MANTEAU NEIGEUX PRINTANIER DANS UN LARGE SECTEUR SUD, STRUCURES DE PLAQUES A L'OMBRE EN ALTITUDE.

2

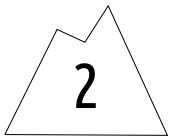

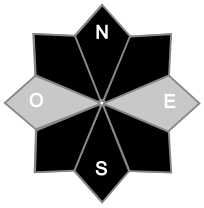

Indice de risque limité.

Départs spontanés : en neige humide au soleil, quelques plaques de fond.

Déclenchements provoqués : au-dessus de 2300m dans les combes raides ombragées.

Indices de risque : 5 très fort - 4 fort - 3 marqué - 2 limité - 1 faible -- En noir : les pentes les plus dangereuses

Stabilité du manteau neigeux

Situation avalancheuse typique : neige ventée neige humide

Déclenchements provoqués : possibles par **sollicitation faible à moyenne des structures de plaques** encore en place **au-dessus de 2300m dans les combes voyant peu le soleil**. Ces structures (souvent **empilements de plaques instables peu épaisses**) reposent en altitude sur des **couches de neige enfouies avec moins de cohésion**, souvent un **mélange de neige fritté et de neige roulée ou de quelques grains anguleux**. Avalanches de **taille 2 possibles dans ces zones d'altitude**.
Déclenchements également faciles au passage d'un skieur ou randonneur de **petites avalanches de neige humide** dans les versants **Sud à Sud-Ouest l'après-midi**.

Observables : en pentes nord raides au-dessus de 2300m voyant peu le soleil, neige encore sèche très travaillée par le vent, quelques accumulations et fissures, zones dégarnies et en neige dure à glacée en Ouest.

Départs spontanés : en **neige humide dans les pentes raides au soleil**. **Départs ponctuels** en général, souvent **près des rochers**, **boulettes et coulées ou petites avalanches en matinée dans les pentes Est à Sud**, avalanches de taille **petite à parfois moyenne en pentes Sud à Sud-Ouest l'après-midi**. Quelques **avalanches de fond,** avec cassure linéaire emportant la totalité du manteau neigeux en place, **possible dans les pentes Sud-Ouest** en partant d'une accumulation persistante en altitude.

Autres : **très bon regel nocturne** du manteau neigeux humidifié dans la journée de mardi, **propice aux glissades en début de journée** sous 2300m en Nord, 2500m en Sud, souvent **persistant dans les pentes raides à l'ombre entre 2000 et 2300m**.

Qualité de la neige

Enneigement : très bon pour la saison au regard de ces derniers hivers. Avec le beau temps, fonte très limitée à l'ombre au-delà de 1500m, plus prononcée dans les versants d'un large secteur Sud. Le manteau neigeux s'amincit très doucement dans les pentes bien ensoleillées.
Limites skiables : à partir de 1300 à 1500m au petit matin suivant les versants.
État de la neige : crêtes, cols et sommets pelés et en neige dure en expositions ouest, en neige déjà bien humidifié en profondeur dans un très large secteur Sud à Est (dure le matin, molle, humide et lourde en journée).
Neige sèche ou poudreuse dans les combes raides d'un large secteur Nord au-dessus de 2300m n'ayant pas trop pris le vent durant l'épisode perturbé de jeudi dernier, restant en l'état en journée malgré la douceur ambiante.

Aperçu météo pour le mercredi 25 février

	nuit	matin	après-midi	soir
Beau temps sec et doux, peu de vent				
Pluie-Neige				
Iso 0 °C	3 100 m	3 100 m	3 000 m	3 000 m
Vent 2000 m	↗ 15 km/h	↑ 15 km/h	↓ 15 km/h	↑ 15 km/h
Vent 3000 m	↗ 20 km/h	↑ 20 km/h	↗ 25 km/h	→ 20 km/h

Épaisseur de neige hors-piste

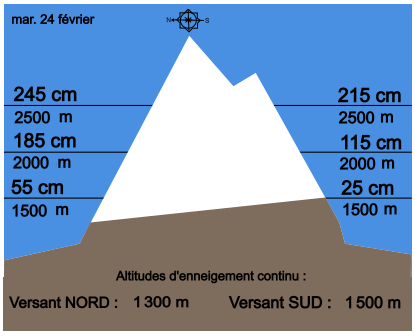

Précipitations à 1800 m

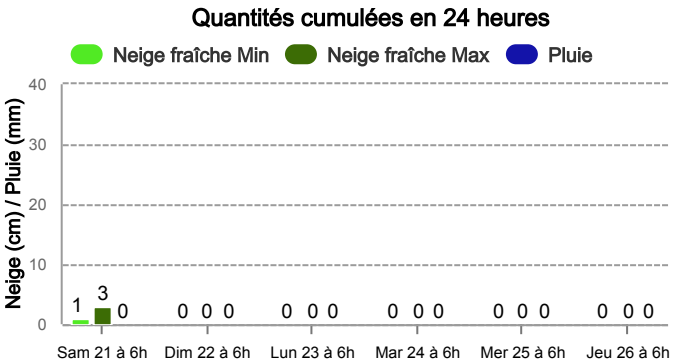

Tendance du jeudi 26 février

2

Indice de risque limité

Sans évolution des conditions météorologiques, le risque reste limité et de même nature sur le massif.

Pour consulter la vigilance en cours, veuillez vous rendre sur le site https://vigilance.meteofrance.fr/fr

Météo-France - 73 avenue de Paris, 94165 Saint-Mandé cedex - Contact : contact@meteo.fr

Rédigé par Météo-France avec la contribution des observateurs du réseau nivo-météorologiques. Partenariat : ANMSM (Maires de Stations de Montagne), DSF (Domaines Skiables de France), ADSP (Directeurs de Pistes et de la Sécurité des Stations de Sports d'Hiver) et autres acteurs de la montagne.

Bulletin neige & avalanches par téléphone au
0 892 68 10 20 Service 0,35 € / min + prix appel

RÉPUBLIQUE FRANÇAISE
Liberté Égalité Fraternité

METEO FRANCE
À VOS CÔTÉS, DANS UN CLIMAT QUI CHANGE

Bulletin d'estimation du risque d'avalanche

(valable en dehors des pistes balisées et ouvertes)

MASSIF : Haute-Bigorre

Rédigé le mardi 24 février 2026 à 16h

Conditions nivo-météo des 7 derniers jours

	mer. 18/02				jeu. 19/02				ven. 20/02				sam. 21/02				dim. 22/02				lun. 23/02				mar. 24/02			
	03h	09h	15h	21h	03h	09h	15h	21h	03h	09h	15h	21h	03h	09h	15h	21h	03h	09h	15h	21h	03h	09h	15h	21h	03h	09h	15h	21h
Météo																												
Vent (km/h)	50	100	110	90	95	90	60	30	30	55	55	35	15	10	15	15	15	15	25	30	25	15	25	20	60	45	25	25
à 3000m																												
Vent (km/h)	25	60	75	45	70	70	45	25	25	10	15	5	2	5	5	5	10	10	10	15	10	5	20	15	15	25	15	20
à 2000m																												

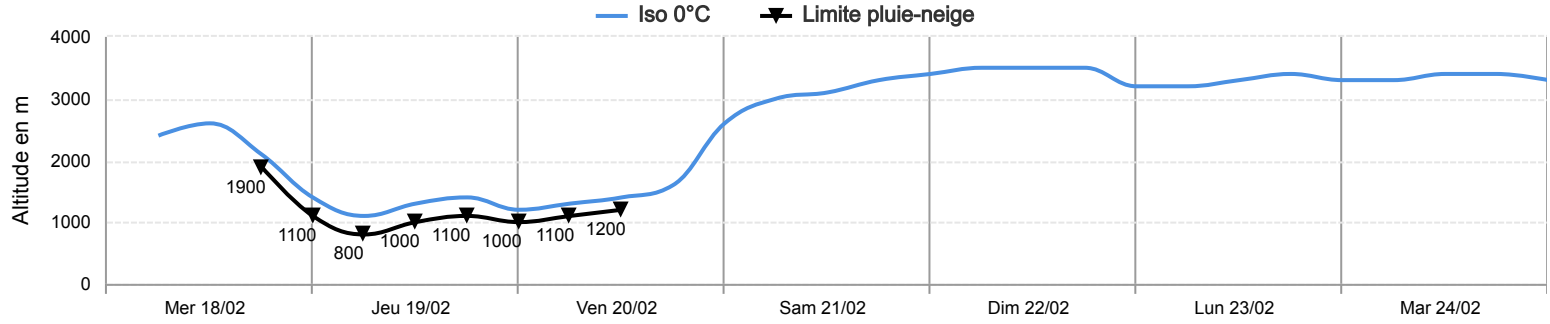

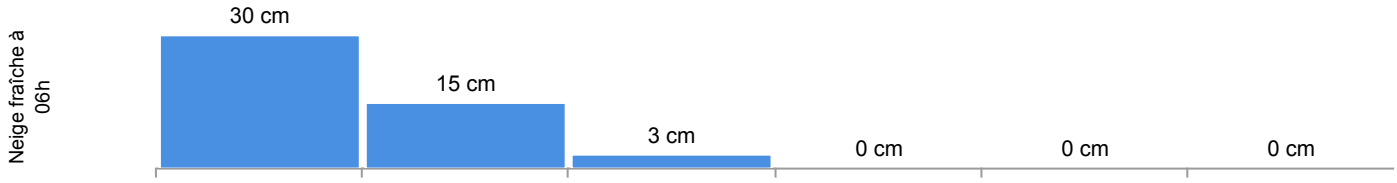

Risque d'avalanche	mer. 18/02	jeu. 19/02	ven. 20/02	sam. 21/02	dim. 22/02	lun. 23/02	mar. 24/02
	3	3	3	3	3	3	2

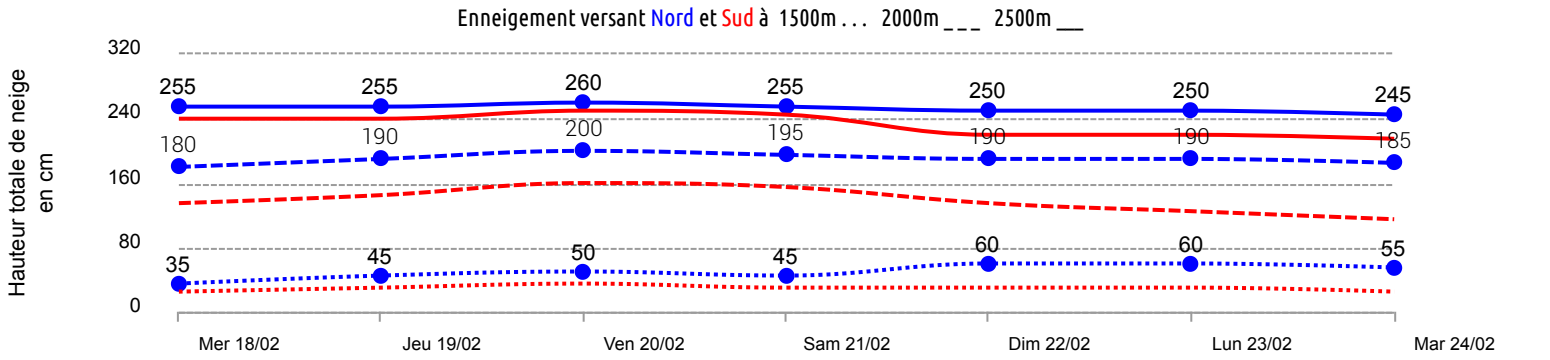

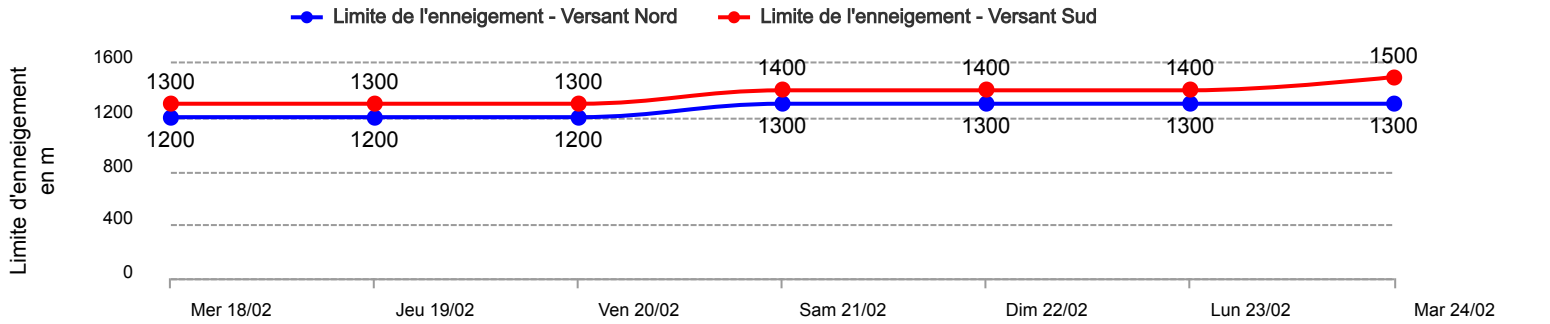

Pour consulter la vigilance en cours, veuillez vous rendre sur le site https://vigilance.meteofrance.fr/fr

Météo-France - 73 avenue de Paris, 94165 Saint-Mandé cedex - Contact : contact@meteo.fr

Rédigé par Météo-France avec la contribution des observateurs du réseau nivo-météorologiques. Partenariat : ANMSM (Maires de Stations de Montagne), DSF (Domaines Skiables de France), ADSP (Directeurs de Pistes et de la Sécurité des Stations de Sports d'Hiver) et autres acteurs de la montagne.

Bulletin neige & avalanches par téléphone au

0 892 68 10 20 Service 0,35 € / min + prix appel