Bulletin d'estimation du risque d'avalanche

(valable en dehors des pistes balisées et ouvertes)

MASSIF : Mercantour

Rédigé le mardi 24 février 2026 à 16h

Estimation des risques pour le : MERCREDI 25 FÉVRIER

DÉPARTS NATURELS EN NEIGE HUMIDE - PLAQUES RÉSIDUELLES DANS LA NEIGE VENTÉE EN ALTITUDE

2

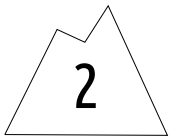

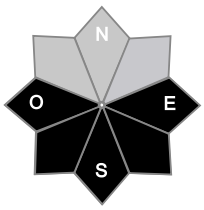

Indice de risque limité.

Départs spontanés : en neige humide, devenant nombreux dans les versants ensoleillés au fil de la journée.

Déclenchements provoqués : petites instabilités résiduelles dans la neige ventée en altitude.

Indices de risque : 5 très fort - 4 fort - 3 marqué - 2 limité - 1 faible -- En noir : les pentes les plus dangereuses

Stabilité du manteau neigeux

Situation avalancheuse typique : neige humide neige ventée

Départs spontanés : en neige humide. Peu probables en début de journée puis devenant fréquents en cours de journée au fil de l'ensoleillement. Ils se produisent en pentes raides ensoleillées à toutes altitudes, notamment près des rochers. Avalanches de taille petite à moyenne (taille 1 à 2), voire grande (taille 3), jusqu'à 2500/2600 m où le manteau neigeux s'est déjà bien humidifié en profondeur. Des avalanches moyennes à grandes sont également possibles en cas de reptations déjà ouvertes ou suite à la rupture d'une corniche. Ces avalanches sont rares, mais peuvent atteindre des altitudes relativement basses et toucher des fonds de vallées ou chemins en contrebas.

Déclenchements provoqués :
— Instabilités résiduelles dans la neige ventée, plus fréquentes en versants nord-ouest à sud-est au-dessus de 2000 m environ. D'aspect durci par le vent à proximité des crêtes, voire en neige humide, elles sont généralement facilement identifiables. Elles deviennent difficiles à déclencher par un skieur, mais peuvent engendrer des avalanches de taille petite à moyenne (taille 1 à 2).
— Des départs sous les skis de neige fortement humidifiée sont possibles en versant raides ensoleillés en cours de journée. Avalanches de taille petite à moyenne (taille 1 à 2)

Qualité de la neige

Enneigement très excédentaire pour un mois de février.
Données observées : 146 cm à la nivôse de Millefonts à 2430 m, 117 cm à Isola 2000.

Enneigement skiable dès 1300/1400 m en ubacs en terrains favorables et 1600/1800 m en adrets

État de la neige en surface : neige finement croutée le matin après un regel nocturne correct, s'humidifiant rapidement en journée au fil de l'ensoleillement. On retrouve de la neige encore poudreuse en Ubacs au-dessus de 1900/2100 m environ, souvent travaillée/durcie par le vent de nord. Zones dégarnies proches des crêtes, alternant avec des corniches parfois épaisses.

Aperçu météo pour le mercredi 25 février

nuit	matin	après-midi	soir

Temps généralement bien ensoleillé et lumineux malgré quelques passages nuageux de haute altitude.

Pluie-Neige				
Iso 0 °C	3 100 m	3 100 m	3 200 m	3 200 m
Vent 2000 m	↓ 10 km/h	↖ 10 km/h	↗ 10 km/h	↗ 10 km/h
Vent 3000 m	→ 15 km/h	→ 15 km/h	→ 15 km/h	→ 15 km/h

Épaisseur de neige hors-piste

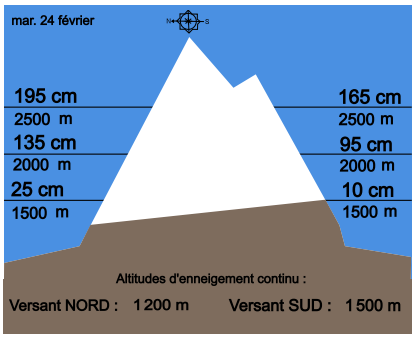

Précipitations à 1800 m

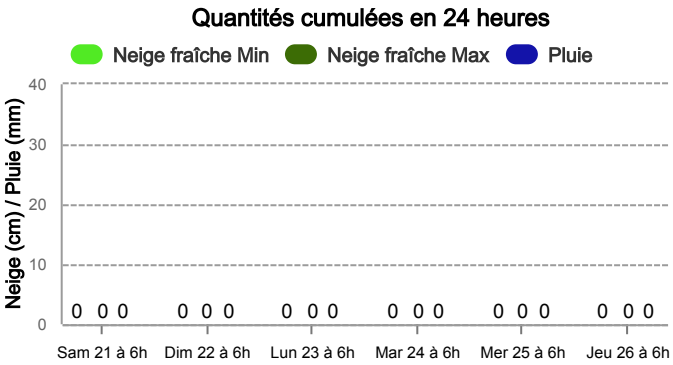

Tendance du jeudi 26 février

2

Indice de risque limité

Maintien d'un risque limité avec toujours des départs spontanés en neige humide, nombreux au fil de l'ensoleillement.

Pour consulter la vigilance en cours, veuillez vous rendre sur le site https://vigilance.meteofrance.fr/fr

Météo-France - 73 avenue de Paris, 94165 Saint-Mandé cedex - Contact : contact@meteo.fr

Rédigé par Météo-France avec la contribution des observateurs du réseau nivo-météorologiques. Partenariat : ANMSM (Maires de Stations de Montagne), DSF (Domaines Skiables de France), ADSP (Directeurs de Pistes et de la Sécurité des Stations de Sports d'Hiver) et autres acteurs de la montagne.

Bulletin neige & avalanches par téléphone au 0 892 68 10 20 Service 0,35 € / min + prix appel

RÉPUBLIQUE FRANÇAISE
Liberté Égalité Fraternité

METEO FRANCE
À VOS CÔTÉS, DANS UN CLIMAT QUI CHANGE

Bulletin d'estimation du risque d'avalanche
(valable en dehors des pistes balisées et ouvertes)

MASSIF : Mercantour

Rédigé le mardi 24 février 2026 à 16h

Conditions nivo-météo des 7 derniers jours

	mer. 18/02				jeu. 19/02				ven. 20/02				sam. 21/02				dim. 22/02				lun. 23/02				mar. 24/02			
	03h	09h	15h	21h	03h	09h	15h	21h	03h	09h	15h	21h	03h	09h	15h	21h	03h	09h	15h	21h	03h	09h	15h	21h	03h	09h	15h	21h
Météo																												
Vent (km/h)	35	25	35	75	55	55	80	80	75	60	50	30	45	50	40	30	30	35	45	50	50	45	25	20	30	25	10	10
à 3000m																												
Vent (km/h)	15	15	20	40	30	35	35	45	45	40	15	15	15	20	15	20	15	15	20	15	25	20	15	15	15	10	5	10
à 2000m																												

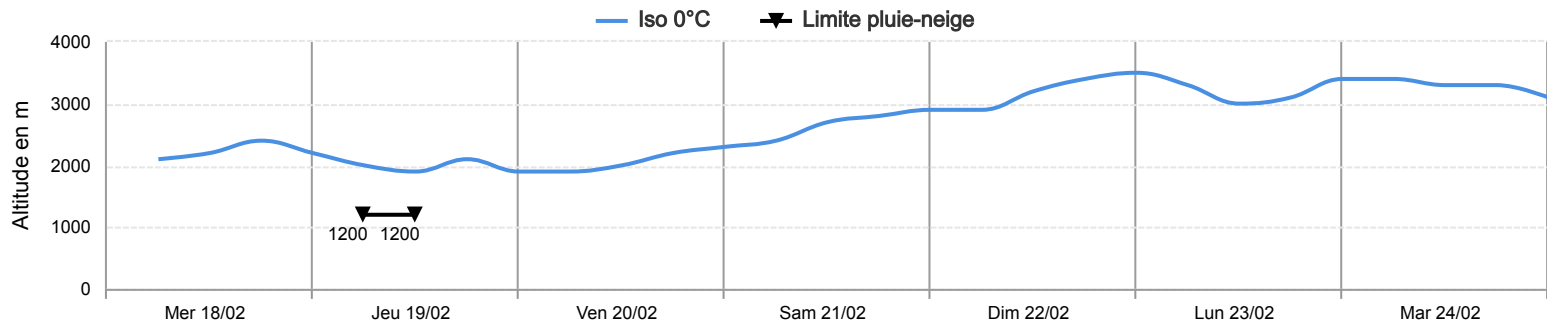

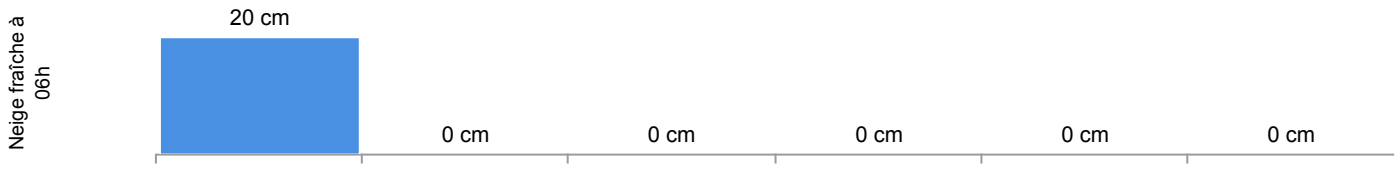

Risque d'avalanche	mer. 18/02	jeu. 19/02	ven. 20/02	sam. 21/02	dim. 22/02	lun. 23/02	mar. 24/02
	3	3	3	3	3	3	2

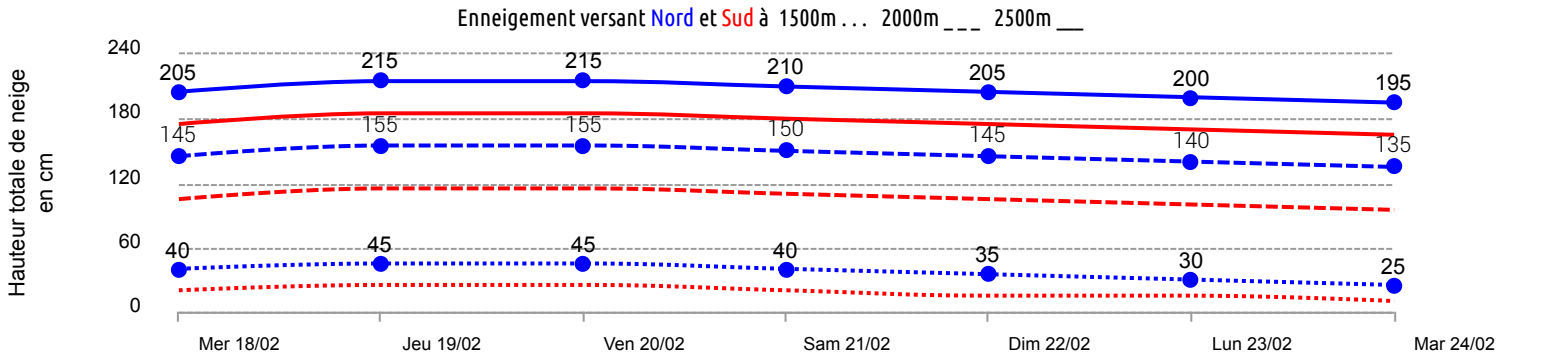

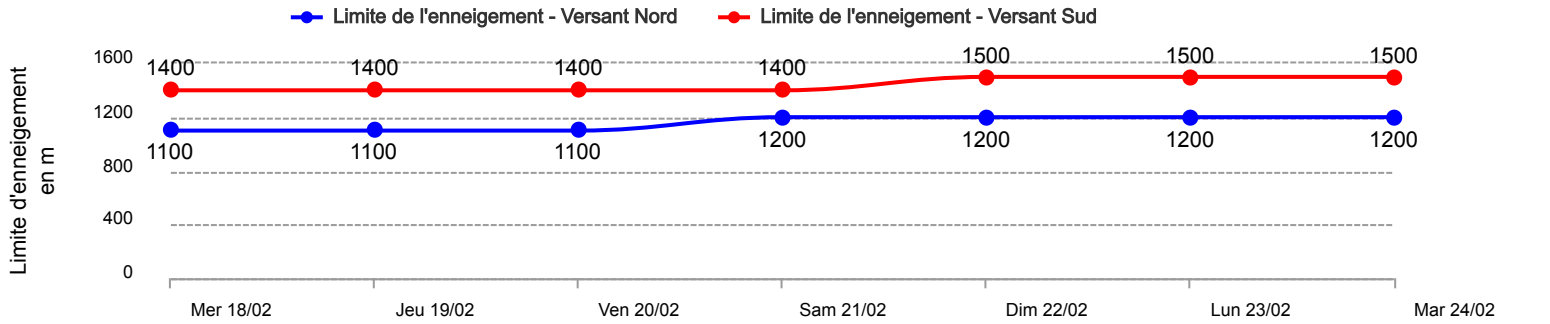

Pour consulter la vigilance en cours, veuillez vous rendre sur le site https://vigilance.meteofrance.fr/fr

Météo-France - 73 avenue de Paris, 94165 Saint-Mandé cedex - Contact : contact@meteo.fr

Rédigé par Météo-France avec la contribution des observateurs du réseau nivo-météorologiques. Partenariat : ANMSM (Maires de Stations de Montagne), DSF (Domaines Skiables de France), ADSP (Directeurs de Pistes et de la Sécurité des Stations de Sports d'Hiver) et autres acteurs de la montagne.

Bulletin neige & avalanches par téléphone au
0 892 68 10 20 Service 0,35 € / min + prix appel