Bulletin d'estimation du risque d'avalanche
(valable en dehors des pistes balisées et ouvertes)

MASSIF : Thabor

Rédigé le mardi 24 février 2026 à 16h

Estimation des risques pour le : MERCREDI 25 FÉVRIER

AVALANCHES DE NEIGE HUMIDE AU SOLEIL, PARFOIS VOLUMINEUSES - PROBABILITÉ TOUJOURS NON NÉGLIGEABLE DE DÉCLENCHER UNE PLAQUE ÉPAISSE EN UBACS

3

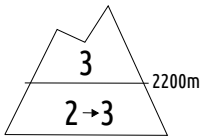

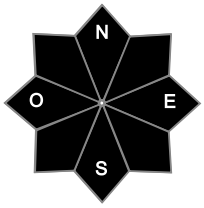

Au-dessus de 2200m indice de risque marqué, plus bas indice limité évoluant en marqué.

Départs spontanés : avalanches de neige humide, départs ponctuels ou linéaires, mobilisant beaucoup de neige.

Déclenchements provoqués : quelques plaques en altitude, souvent de grande taille en cas de départ.

Indices de risque : 5 très fort - 4 fort - 3 marqué - 2 limité - 1 faible -- En noir : les pentes les plus dangereuses

Stabilité du manteau neigeux

Situation avalancheuse typique : neige humide couche fragile persistante

Déclenchements provoqués : * Dans les ubacs au-dessus de 2200/2300 m environ (également non exclu en adrets de haute altitude), **un skieur peut encore déclencher une plaque épaisse et large, emportant la quasi-totalité du manteau neigeux en place** et provoquant une grande avalanche (taille 3). **Danger difficile à appréhender pour le pratiquant**, dépendant notamment de la profondeur d'enfouissement de la couche fragile persistante en chaque point de sa trace. Déclenchements aléatoires et moins fréquents dans les grandes pentes homogènes, mais un peu plus probables au niveau des discontinuités de terrain (croupes, rochers affleurants, etc.), là où les épaisseurs de neige sont moins importantes et isolent moins la couche fragile enfouie à la base du manteau neigeux. Possibilité de déclenchement à distance des grandes pentes encore très chargées, depuis ces zones moins enneigées.
* Les plaques de surface formées par les épisodes de vent fort des jours passés se stabilisent, elles sont désormais difficiles à déclencher.

Départs spontanés : * Activité en neige humide en hausse selon la course du soleil. Départs souvent près des rochers ou des barres, mobilisant des volumes de neige plus conséquents sous 2300/2500 m, en emportant parfois une grande partie du manteau neigeux en place. Avalanches moyennes à grandes (taille 2 à 3), pouvant descendre à basse altitude dans les couloirs habituels. Départs linéaires possibles, mettant en mouvement de grandes quantités de neige.
* Quelques plaques de fond peuvent céder spontanément à toute heure du jour ou de la nuit en terrain favorable (dalles lisses, sols herbeux). Avalanches moyennes à grandes (taille 2 à 3).
* Une première petite avalanche superficielle de neige humide ou la chute d'une corniche peut engendrer un départ de plaque en contrebas.

Qualité de la neige

L'enneigement est excédentaire pour un mois de février.
Hauteurs de neige observées vers 2500 m : 195 cm dans le vallon du Chardonnet, 135 cm à la Nivôse des Rochilles, 90 cm à la Nivôse du Galibier (secteur venté).

Limite d'enneigement skiable en fond de vallées, mais la neige fond rapidement en adrets raides et l'enneigement devient un peu juste sous 1600 m environ.

État de la neige de surface : * En adrets, manteau neigeux désormais bien printanier jusqu'à très haute altitude, petite croûte le matin, puis humidification au soleil l'après-midi, sur une grande épaisseur dans les pentes raides bien exposées.
* En ubacs (nord-ouest à nord-est), croûte de quelques cm le matin sous 2100/2200 m environ sur les zones peu pentues, s'humidifiant en cours de journée. Ailleurs, la neige est soit cartonnée/durcie par les épisodes de vent passés, ou en poudreuse dense dans les combes ou pentes abritées.

Aperçu météo pour le mercredi 25 février

	nuit	matin	après-midi	soir

Le printemps est bien installé : soleil, fins voiles nuageux d'altitude et températures très élevées pour une fin février, 12/13 °C à 2000 m l'après-midi.

Pluie-Neige				
Iso 0 °C	3 200 m	3 100 m	3 100 m	3 100 m
Vent 2000 m	↑ 5 km/h	↑ 5 km/h	↑ 5 km/h	↑ 5 km/h
Vent 3000 m	↓ 15 km/h	↑ 10 km/h	↑ 10 km/h	↑ 10 km/h

Épaisseur de neige hors-piste

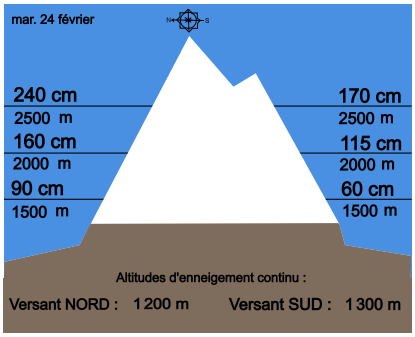

Précipitations à 1800 m

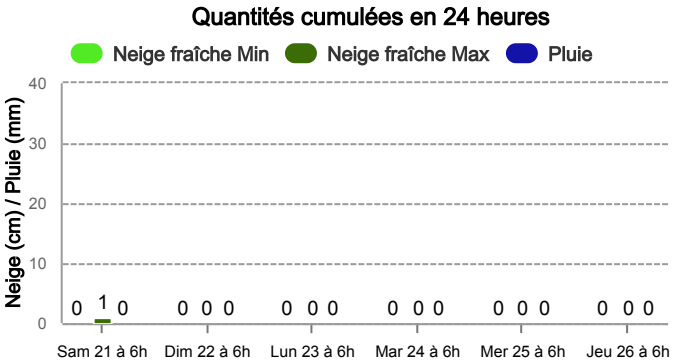

Tendance du jeudi 26 février

3 **Indice de risque marqué**

Maintien probable d'un risque marqué, avec les mêmes problématiques (neige humide et plaques épaisses en ubacs d'altitude).

Pour consulter la vigilance en cours, veuillez vous rendre sur le site https://vigilance.meteofrance.fr/fr

Météo-France - 73 avenue de Paris, 94165 Saint-Mandé cedex - Contact : contact@meteo.fr

Rédigé par Météo-France avec la contribution des observateurs du réseau nivo-météorologiques. Partenariat : ANMSM (Maires de Stations de Montagne), DSF (Domaines Skiables de France), ADSP (Directeurs de Pistes et de la Sécurité des Stations de Sports d'Hiver) et autres acteurs de la montagne.

Bulletin neige & avalanches par téléphone au
0 892 68 10 20 Service 0,35 € / min + prix appel

RÉPUBLIQUE FRANÇAISE
Liberté Égalité Fraternité

METEO FRANCE
À VOS CÔTÉS, DANS UN CLIMAT QUI CHANGE

Bulletin d'estimation du risque d'avalanche

(valable en dehors des pistes balisées et ouvertes)

MASSIF : Thabor

Rédigé le mardi 24 février 2026 à 16h

Conditions nivo-météo des 7 derniers jours

	mer. 18/02				jeu. 19/02				ven. 20/02				sam. 21/02				dim. 22/02				lun. 23/02				mar. 24/02			
	03h	09h	15h	21h	03h	09h	15h	21h	03h	09h	15h	21h	03h	09h	15h	21h	03h	09h	15h	21h	03h	09h	15h	21h	03h	09h	15h	21h
Météo																												
Vent (km/h)	70	35	25	40	45	50	60	60	70	60	60	50	70	80	80	60	50	40	40	45	50	50	50	45	30	15	5	10
à 3000m																												
Vent (km/h)	40	25	20	25	25	30	40	45	35	40	35	30	35	45	45	25	25	20	20	5	10	20	15	15	10	5	0	5
à 2000m																												

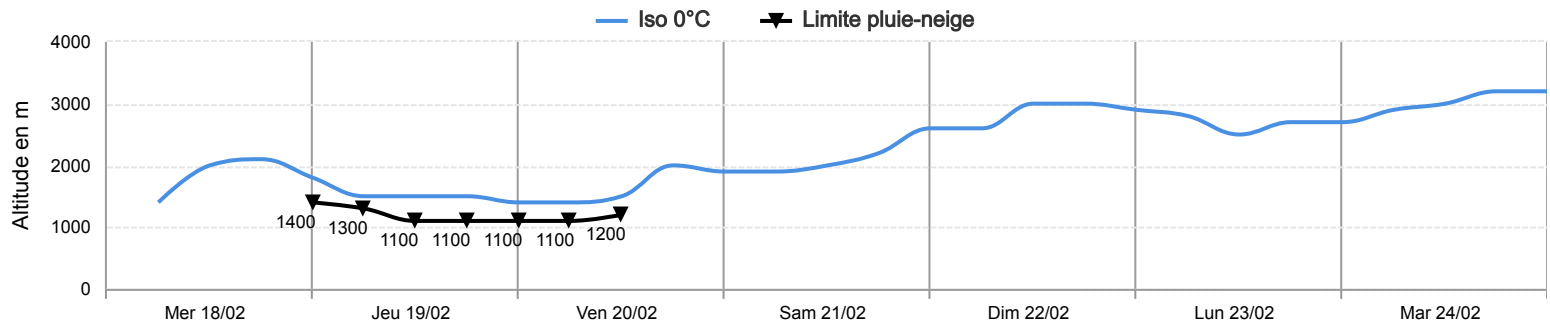

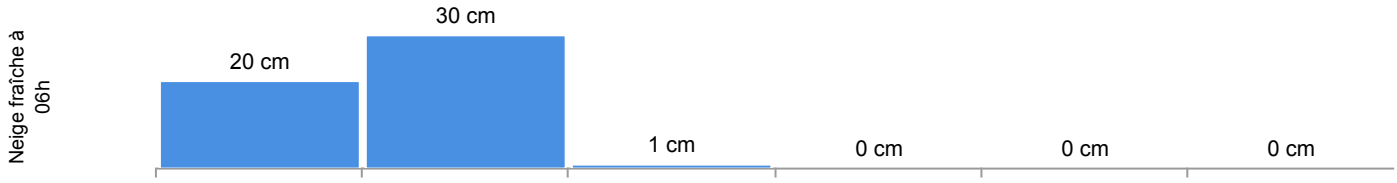

Risque d'avalanche	mer. 18/02	jeu. 19/02	ven. 20/02	sam. 21/02	dim. 22/02	lun. 23/02	mar. 24/02
	4	4	4	4	3	3	3

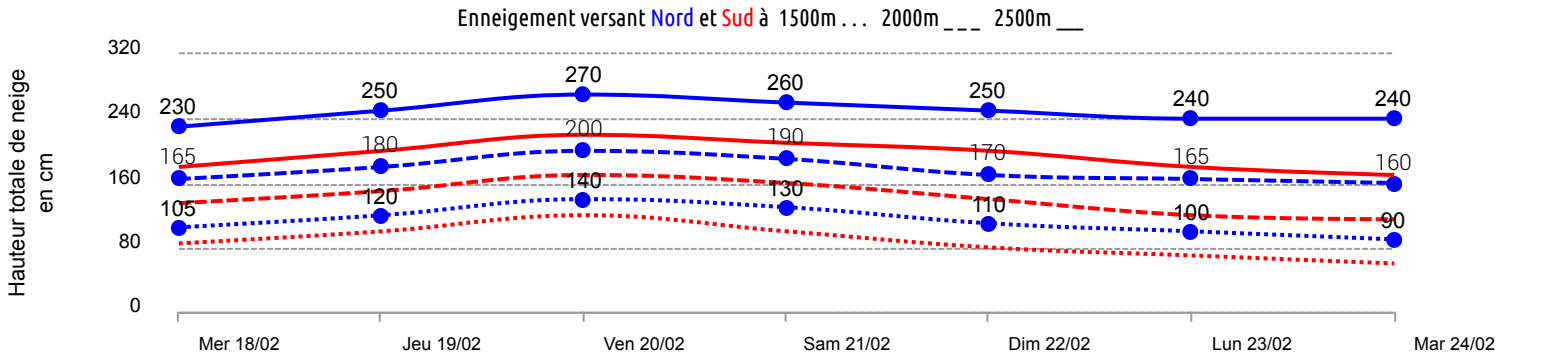

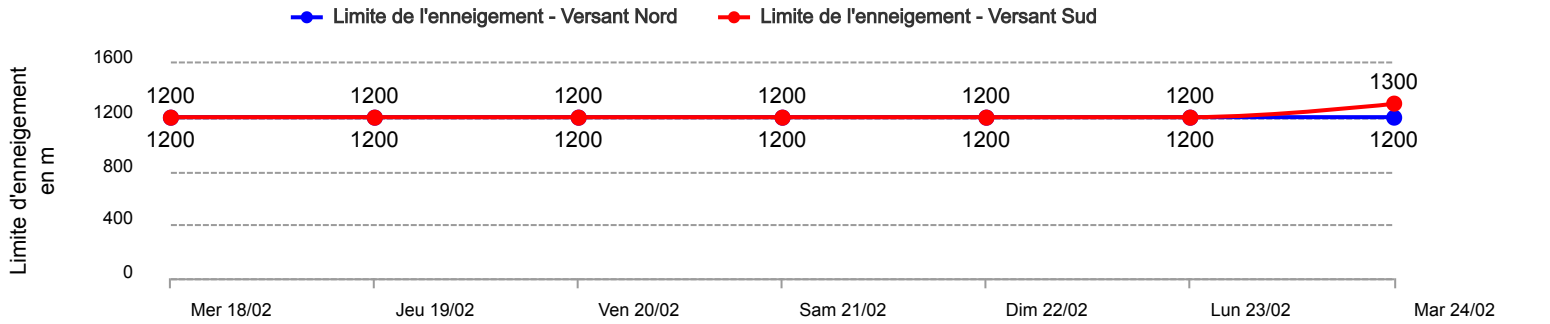

Pour consulter la vigilance en cours, veuillez vous rendre sur le site https://vigilance.meteofrance.fr/fr

Météo-France - 73 avenue de Paris, 94165 Saint-Mandé cedex - Contact : contact@meteo.fr

Rédigé par Météo-France avec la contribution des observateurs du réseau nivo-météorologiques. Partenariat : ANMSM (Maires de Stations de Montagne), DSF (Domaines Skiables de France), ADSP (Directeurs de Pistes et de la Sécurité des Stations de Sports d'Hiver) et autres acteurs de la montagne.

Bulletin neige & avalanches par téléphone au

0 892 68 10 20 Service 0,35 € / min + prix appel