Bulletin d'estimation du risque d'avalanche

(valable en dehors des pistes balisées et ouvertes)

MASSIF : Haute-Maurienne

Rédigé le mardi 24 Février 2026 à 17h

Estimation des risques pour le : MERCREDI 25 FÉVRIER

FORTE ACTIVITE AVALANCHEUSE NATURELLE EN NEIGE HUMIDE (REDOUX). PLAQUES EN ALTITUDE.

3

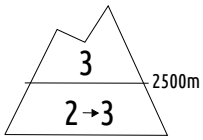

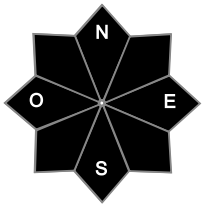

Au-dessus de 2500m indice de risque marqué, plus bas indice limité évoluant en marqué.

Départs spontanés : forte activité en neige humide et plaque de fond.

Déclenchements provoqués : plaques encore réactives dans les secteurs ventés d'altitude.

Indices de risque : 5 très fort - 4 fort - 3 marqué - 2 limité - 1 faible -- En noir : les pentes les plus dangereuses

Stabilité du manteau neigeux

Situation avalancheuse typique : neige humide couche fragile persistante

Départs spontanés : **- Quelques plaques de fond encore possible plutôt sous 2300m à toutes heures et en toutes orientations taille 2 à 3.** Départs surtout dans les pentes raides et herbeuses ou dalles rocheuses, les épaisseurs de neige étant notables, **les volumes mobilisés sont conséquents** et peuvent localement **atteindre fonds des hautes vallées et routes d'altitude.**
- Avec le redoux qui s'accentue encore, **plaques en neige humide devenant possible jusqu'à 2800m en cours de journée en versant sud et ouest surtout** , la plupart en taille2 mais là aussi les volumes mobilisables peuvent engendrer de **rares grandes avalanche de taille 3**

Déclenchements provoqués : **Quelques plaques friables ou dures encore sensibles au passage d'un skieur.** Suite au vent de ces derniers jours on retrouve ces plaques **dans la neige restée froide en poudreuse dense** donc maintenant **plutôt au dessus de 2400/2500 m en Nord et Est,** et beaucoup **plus haut ailleurs (vers 2800m).** Ces plaques restent **sensible surtout là où elles reposent sur des couches fragiles persistantes pas trop profondément enfouies:** donc plutôt dans les vallons les plus soufflées et secteurs moins enneigés comme les abords des crêtes ou croupes ventées. Se méfiez aussi des zones où des départs ont déjà eu lieu et qui ne sont maintenant recouvert que par la dernière chute. Cassures de 5Ocm à largement plus de 1m Taille 2 à 3 .

Qualité de la neige

Enneigement : grâce aux chutes de neige de mi février, l'enneigement est actuellement excédentaire à toutes altitudes. Les températures anormalement douces engendrent une fonte marquée en Sud de moyenne et basse montagne. La limite d'enneigement dans ces pentes va vite remonter. Ailleurs le manteau se tasse considérablement.

Limite skiable : encore skiable ce mardi dès 1000 m dans les prairies orientées Nord, plutôt 1200 m en Sud pas trop raide.

Qualité de la neige :
En Sud, véritable ski de printemps. Croûte portante au réveil qui ramollie rapidement au soleil.
En Nord, neige croutée souvent non portante jusqu'à 2000/2300 qui chauffe doucement là où elle prend le Soleil. Plus haut, la neige est froide, poudreuse dense à l'abri du vent et très hétérogène entre carton et dure dans les secteurs ventés (à l'approche des crêtes).

Aperçu météo pour le mercredi 25 février

	nuit	matin	après-midi	soir
Soleil et "canicule hivernale".				
Pluie-Neige				
Iso 0 °C	3 200 m	3 400 m	3 200 m	3 300 m
Vent 2500 m	5 km/h	5 km/h	5 km/h	5 km/h
Vent 3500 m	20 km/h	20 km/h	20 km/h	20 km/h

Épaisseur de neige hors-piste

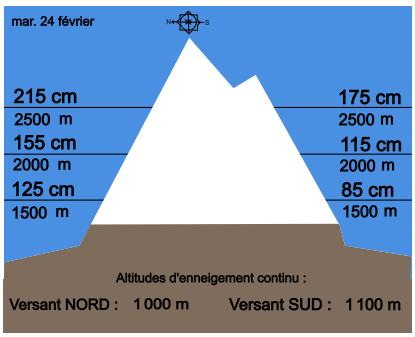

Précipitations à 1800 m

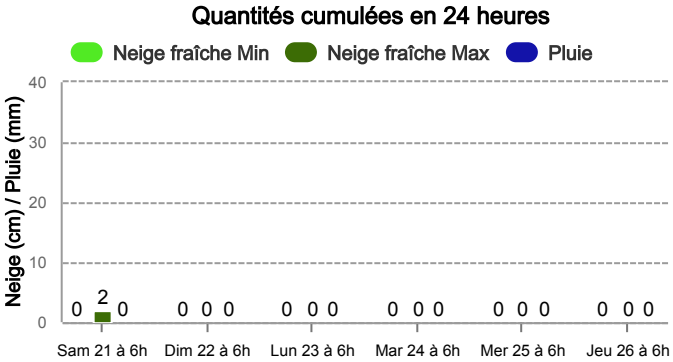

Tendance du jeudi 26 février

3 **Indice de risque marqué**

Poursuite des conditions excessivement douces et de l'activité avalancheuse naturelle associée. Lente stabilisation des plaques en versants froids.

Pour consulter la vigilance en cours, veuillez vous rendre sur le site https://vigilance.meteofrance.fr/fr

Météo-France - 73 avenue de Paris, 94165 Saint-Mandé cedex - Contact : contact@meteo.fr

Rédigé par Météo-France avec la contribution des observateurs du réseau nivo-météorologiques. Partenariat : ANMSM (Maires de Stations de Montagne), DSF (Domaines Skiables de France), ADSP (Directeurs de Pistes et de la Sécurité des Stations de Sports d'Hiver) et autres acteurs de la montagne.

Bulletin neige & avalanches par téléphone au **0 892 68 10 20** Service 0,35 € / min + prix appel

RÉPUBLIQUE FRANÇAISE
Liberté Égalité Fraternité

METEO FRANCE
À VOS CÔTÉS, DANS UN CLIMAT QUI CHANGE

Bulletin d'estimation du risque d'avalanche
(valable en dehors des pistes balisées et ouvertes)
MASSIF : Haute-Maurienne

Rédigé le mardi 24 février 2026 à 17h

Conditions nivo-météo des 7 derniers jours

	mer. 18/02				jeu. 19/02				ven. 20/02				sam. 21/02				dim. 22/02				lun. 23/02				mar. 24/02			
	03h	09h	15h	21h	03h	09h	15h	21h	03h	09h	15h	21h	03h	09h	15h	21h	03h	09h	15h	21h	03h	09h	15h	21h	03h	09h	15h	21h
Météo																												
Vent (km/h)	50	40	30	40	40	50	90	100	100	85	70	60	60	80	80	80	40	50	60	60	65	60	55	45	35	35	30	25
à 3500m																												
Vent (km/h)	45	30	20	30	30	40	65	70	70	65	40	40	40	40	40	30	20	25	40	45	50	45	40	30	20	15	15	10
à 2500m																												

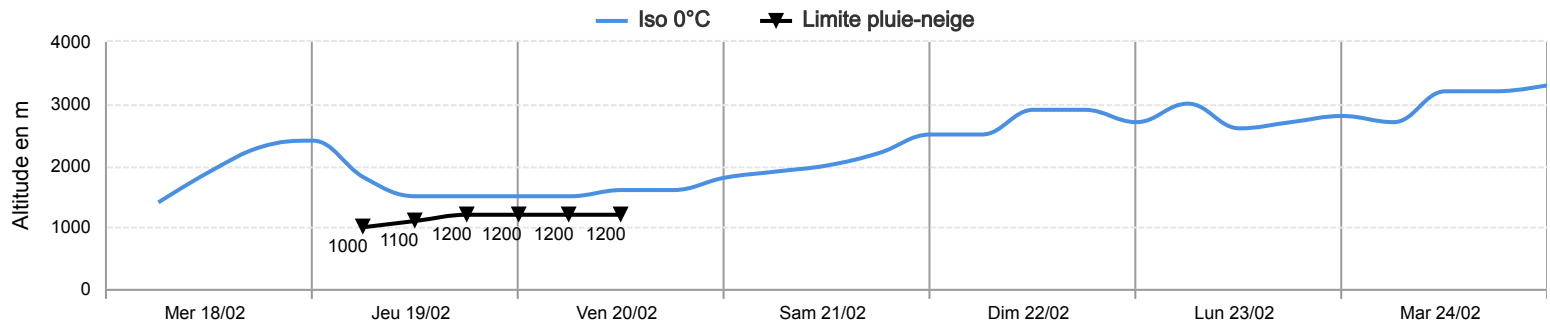

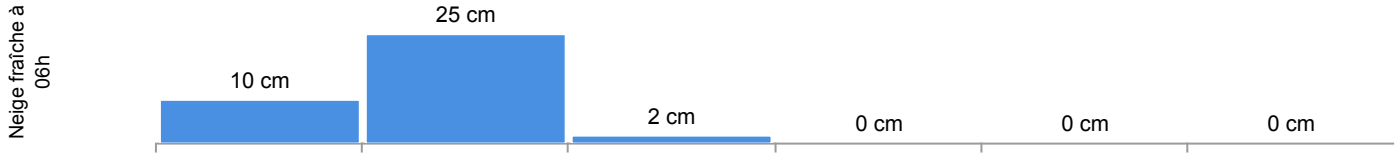

Risque d'avalanche	mer. 18/02	jeu. 19/02	ven. 20/02	sam. 21/02	dim. 22/02	lun. 23/02	mar. 24/02
	4	5	4	4	3	3	3

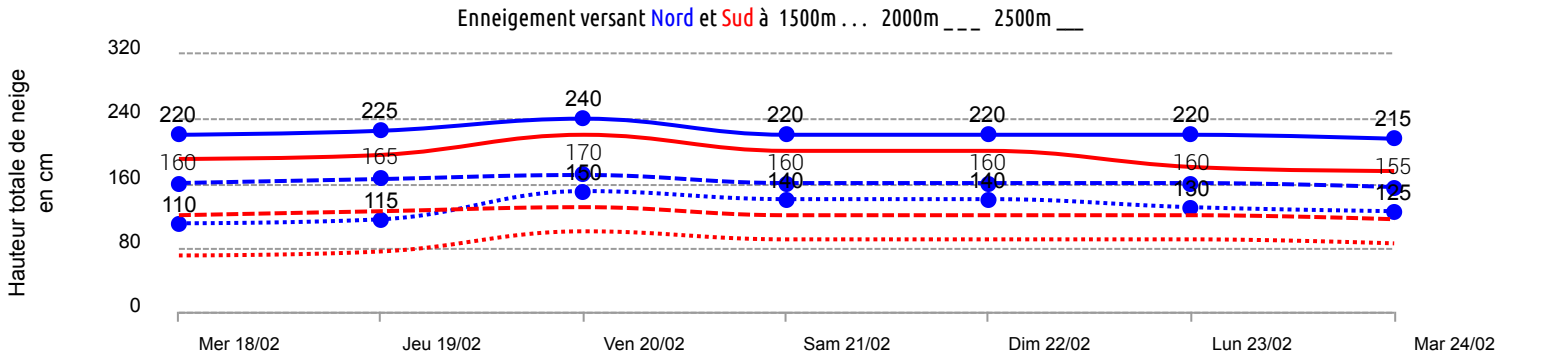

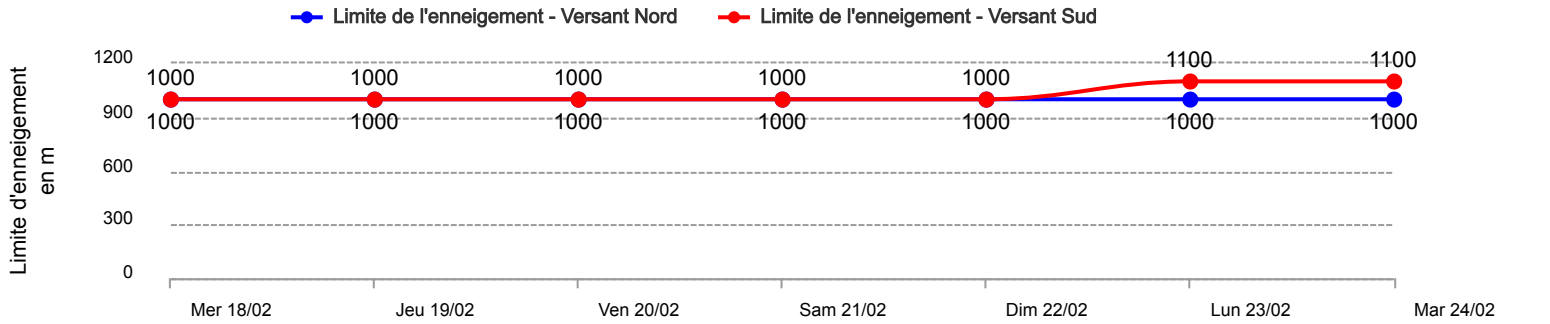

Pour consulter la vigilance en cours, veuillez vous rendre sur le site https://vigilance.meteofrance.fr/fr

Météo-France - 73 avenue de Paris, 94165 Saint-Mandé cedex - Contact : contact@meteo.fr

Rédigé par Météo-France avec la contribution des observateurs du réseau nivo-météorologiques. Partenariat : ANMSM (Maires de Stations de Montagne), DSF (Domaines Skiables de France), ADSP (Directeurs de Pistes et de la Sécurité des Stations de Sports d'Hiver) et autres acteurs de la montagne.

Bulletin neige & avalanches par téléphone au
0 892 68 10 20 Service 0,35 € / min + prix appel