GOBIERNO DE ESPAÑA
VICEPRESIDENCIA TERCERA DEL GOBIERNO
MINISTERIO PARA LA TRANSICIÓN ECOLÓGICA Y EL RETO DEMOGRÁFICO

Boletín de información nivológica y de peligro de aludes

Pirineo Navarro y Aragonés

aemet Agencia Estatal de Meteorología

miércoles, 25 de febrero de 2026

Pronóstico hasta las 24 horas del jueves, día 26 de febrero

(Válido fuera de pistas de esquí balizadas y abiertas)

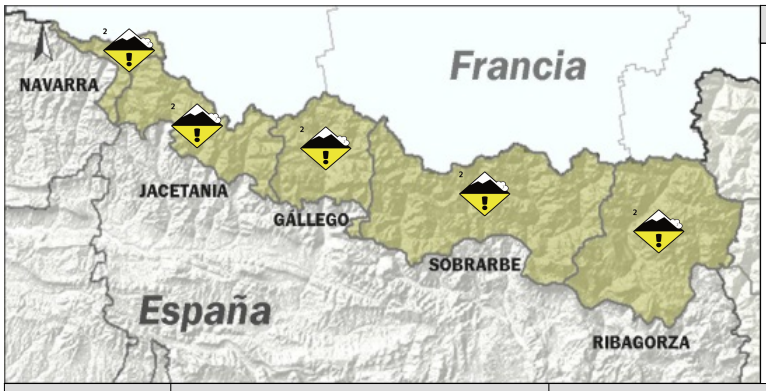

Problemas de aludes

Nieve húmeda

Placas de viento

Macizo	Peligro	Problemas de aludes, cota, orientación, tamaño	Innivación observada (m)
Navarra	2 2 / 1→2 / 2200 Durante el día Limitado	Nieve húmeda Placas de viento	2026-02-25 Cotas bajas
Jacetania	2 2 / 1→2 / 2200 Durante el día Limitado	Nieve húmeda Placas de viento	2026-02-25 Cotas bajas
Gállego	2 2 / 1→2 / 2200 Durante el día Limitado	Nieve húmeda Placas de viento	2026-02-25 Cotas bajas

AEMET. Se autoriza la reproducción de su contenido citando la fuente.

Boletín de información nivológica y de peligro de aludes

Pirineo Navarro y Aragonés

Sobrarbe	**Limitado**	**Nieve húmeda**  **Placas de viento** 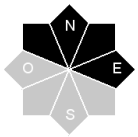 	2026-02-25 Cotas bajas
Ribagorza	**Limitado**	**Nieve húmeda**  **Placas de viento** 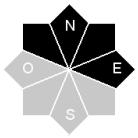 	2026-02-25 Cotas bajas

Estado del manto y observaciones recientes

Durante las últimas jornadas, el ambiente templado con temperaturas anormalmente altas y la abundante insolación han propiciado la humidificación y compactación del manto, a razón de varios centímetros cada día, procesos que van a continuar durante las próximas jornadas. Con todo, el manto es continuo desde fondos de valle, comenzando a unos 1500 metros en solanas y a unos 1300 en umbrías, siendo esquiable desde los 1500-1700 metros aproximadamente. Además, presenta espesores muy por encima de lo que sería habitual a estas alturas de la temporada, superándose fácilmente los 150-200 cm en cotas medias, aún más en ventisqueros, hoyas y otras zonas propensas a la acumulación. Cabe mencionar que la intensa acción del viento de la semana pasada, erosionó ampliamente el manto de orientaciones oeste y norte, resultando así más deficitario en aquellas zonas que hayan sido expuestas a este.

Tanto en cotas medias y bajas, como en solanas de cotas altas, el manto se ha humidificado significativamente, y por lo general amanece encostrado. Sin embargo, el calentamiento diurno y la intensa radiación van ablandando las costras durante la mañana, sometiendo al manto a un ciclo de rehielo-fusión diario. En cotas altas, la acción del viento de días pasados dio lugar a la formación de placas de viento que aún no se han estabilizado por completo, especialmente en umbrías. Además, no se descarta que persista alguna capa débil enterrada que pueda seguir latente.

En las últimas 24 horas se han registrado varias purgas y aludes pequeños de nieve húmeda en solanas de cotas medias, así como alguno de tamaño mediano. También se han observado varios deslizamientos basales en diferentes enclaves, todos ellos de tamaño mediano.

AEMET. Se autoriza la reproducción de su contenido citando la fuente.

Evolución del manto y peligro de aludes para el jueves, día 26

Problema de nieve húmeda y deslizamientos basales. Problema de placas de viento y capas débiles persistentes en umbrías de cotas altas.

Mañana a primeras horas se podrán formar costras de rehielo que aportarán cierta estabilidad al manto, pero que tenderán a desaparecer en el transcurso de la mañana, debido al calentamiento diurno y a la intensa insolación que se espera. Así, con el avance del día, el manto se hará cada vez más inestable, especialmente en solanas, dando lugar a aludes de nieve húmeda en pendientes suficientemente inclinadas, de dimensión 1 (pequeño, riesgo de caída) ó 2 (mediano, capaz de enterrar a una persona). Cabe destacar que en zonas herbosas o de roca lisa son probables los deslizamientos basales, que podrían movilizar una cantidad de nieve considerable y alcanzar localmente el tamaño 3 (grande, capaz de enterrar un vehículo).

En cotas altas, por encima de 2200 metros, aún podemos encontrar placas de viento, principalmente en umbrías, que aunque tienden a estabilizarse, todavía podrían colapsar ante una sobrecarga, ocasionando aludes de dimensión 1 ó 2. Además, no se descarta que se pueda fracturar alguna capa débil persistente en profundidad, que en el peor de los casos podría provocar un alud de mayores dimensiones.

Conviene recordar que las superficies heladas pueden provocar resbalones y caídas con graves consecuencias.

Predicción meteorológica para el jueves, día 26

Poco nuboso o despejado. Ligeros cambios en las temperaturas, generalmente ascensos en las mínimas y descensos en las máximas. Heladas débiles o localmente moderadas, en cumbres y fondos de valles. Viento flojo de componentes sur y oeste, con algunos intervalos de moderado.

Datos en la atmósfera libre:

Altitud de la isoterma de 0 ºC: 3000 m
Altitud de la isoterma de -10 ºC: 4400 m

Viento a 1500 m: S 10 km/h
Viento a 3000 m: NW 10 km/h

Evolución para el viernes día 27

Nivel de peligro con pocos cambios.

(Información elaborada a partir de los datos recibidos de los refugios de Linza, Lizara, Panticosa, Bachimaña, Góriz, Pineta, Estós, Angel Orús, Cap de Llauset y Belagua, de las estaciones de esquí de Candanchú, Formigal y Panticosa (lagos) y de la estación de esquí de fondo de Llanos del Hospital)

Escala europea de peligro de aludes

Débil | Limitado | Notable | Fuerte | Muy Fuerte

Problemas de aludes

Nieve reciente | Placas de viento | Capas débiles persistentes | Nieve húmeda | Deslizamientos basales | Sin problema evidente

AEMET. Se autoriza la reproducción de su contenido citando la fuente.

Nota1: Se recuerda que, siempre que haya nieve, la ausencia total de peligro no existe. Hay que tener presente que en circunstancias desfavorables, con aludes de tamaño 1 (alud pequeño o colada) y tamaño 2 (alud mediano), se pueden sufrir severos daños personales.

Nota2: Los BPA se elaboran en base a información meteorológica así como al estado del manto nivoso a través de sondeos puntuales. Se advierte a los usuarios de la variabilidad de esta información al extrapolarla a zonas extensas de montaña. Por ello, AEMET no se hace responsable de su uso para la toma de decisiones que conciernen a la seguridad personal, ni de los riesgos físicos o materiales de ellas derivadas.

AEMET. Se autoriza la reproducción de su contenido citando la fuente.