Donnerstag 26.02.2026

Veröffentlicht am 25.02.2026 um 17:00

Vormittag

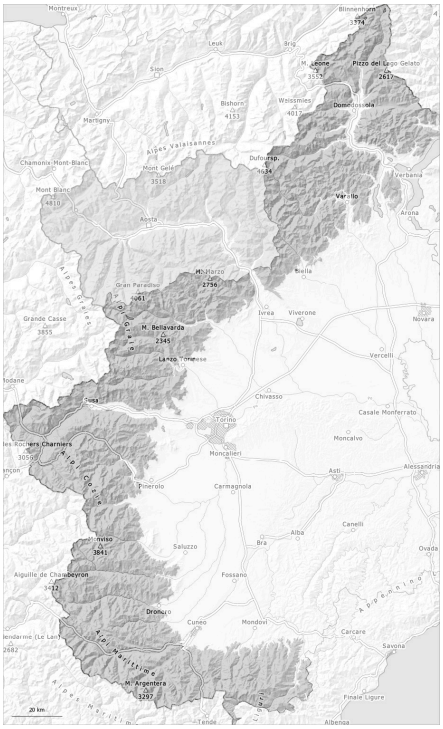

Nachmittag

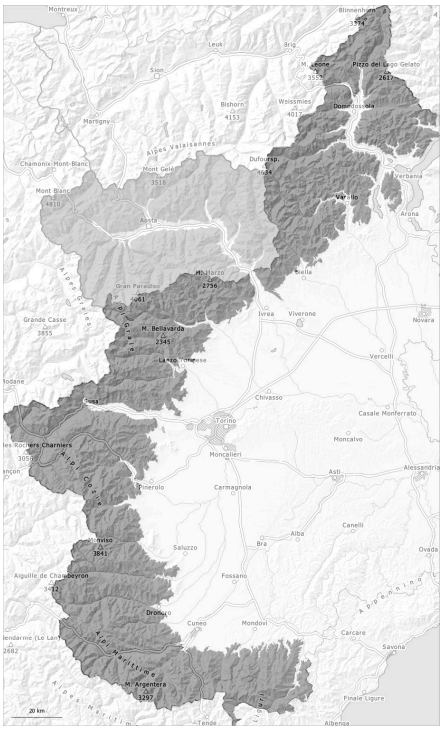

1	2	3	4	5
gering	mäßig	erheblich	groß	sehr groß

Gefahrenstufe 3 - Erheblich

AM:

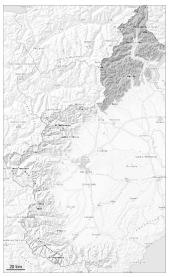

Tendenz: Lawinengefahr bleibt gleich
am Freitag, den 27.02.2026

Nassschnee

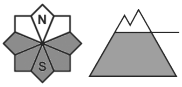

2600m

Triebschnee

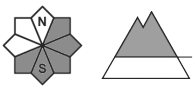

2600m

PM:

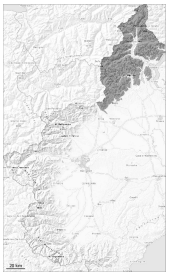

Tendenz: Lawinengefahr bleibt gleich
am Freitag, den 27.02.2026

Nassschnee

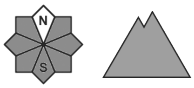

Triebschnee

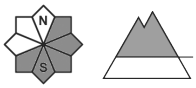

2600m

Es ist sonnig. Die Gefahr von feuchten und nassen Lawinen steigt im Tagesverlauf rasch an.

An Sonnenhängen und in tiefen und mittleren Lagen sind mit der tageszeitlichen Erwärmung und der Sonneneinstrahlung mittlere und vereinzelt große feuchte und nasse Lawinen möglich. Feuchte Lawinen können vor allem unterhalb von rund 2500 m bis in tiefe Schichten durchreißen und recht groß werden.

Hohe Lagen und Hochgebirge: Die Wetterbedingungen begünstigten eine allmähliche Stabilisierung der Triebschneeansammlungen. Dort sind die Lawinen meist mittelgroß und meist noch mit großer Belastung auslösbar. Vorsicht vor allem an sehr steilen Hängen und in Kammlagen, Rinnen und Mulden.

Touren sollten früh gestartet und beendet werden.

Schneedecke

Gefahrenmuster gm.10: frühjahrssituation | gm.2: gleitschnee

In diesen Gebieten liegt weniger Schnee als üblich.
In Gipfellagen liegen je nach Windeinfluss sehr unterschiedliche Schneehöhen.

Die Wetterbedingungen erlauben in der Nacht eine deutliche Verfestigung der oberflächennahen Schneeschichten. Der obere Teil der Schneedecke ist weitgehend stabil, mit einer oft tragfähigen Schmelzharschkruste an der Oberfläche. Auf der harten Schneeoberfläche besteht im Steilgelände Absturzgefahr. Die frühlingshaften Wetterbedingungen führen am Vormittag vor allem an Sonnenhängen unterhalb von rund 2500 m zu einer raschen Anfeuchtung der Schneedecke. Die Schneeoberfläche weicht schneller auf als am Vortag.

Besonders steile Schattenhänge hohe Lagen und Hochgebirge: Verschiedene Triebschneeschichten liegen stellenweise auf grobkörnigem Altschnee.

Gefahrenstufe 3 - Erheblich

AM:

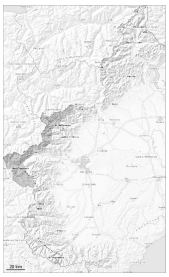

Tendenz: Lawinengefahr bleibt gleich
am Freitag, den 27.02.2026

Nassschnee

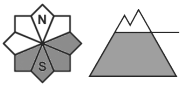

2500m

Altschnee

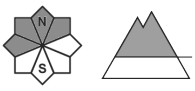

2600m

PM:

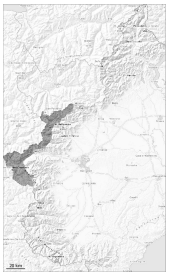

Tendenz: Lawinengefahr bleibt gleich
am Freitag, den 27.02.2026

Nassschnee

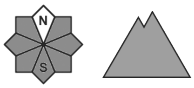

Altschnee

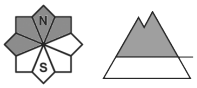

2600m

Anstieg der Lawinengefahr mit der tageszeitlichen Erwärmung und der Sonneneinstrahlung.

Vor allem steile Sonnenhänge und Felswandfüße: In tiefen und mittleren Lagen sind mit der Anfeuchtung mittlere und große feuchte und nasse Lawinen möglich. Feuchte Lawinen können unterhalb von rund 2600 m bis in tiefe Schichten durchreißen.

Besonders steile Schattenhänge hohe Lagen und Hochgebirge: Im mittleren Teil der Schneedecke sind einzelne Schwachschichten vorhanden. Heikel sind Stellen, wo Oberflächenreif eingeschneit wurde. Schwachschichten im Altschnee sind nur schwer erkennbar. Zudem sind die Triebschneeansammlungen der letzten Wochen noch auslösbar.
Dort sind die Lawinen meist mittelgroß und vereinzelt von einzelnen Wintersportlern auslösbar.
Entlang der Grenze zu Frankreich sind die Gefahrenstellen weiter verbreitet.

Touren sollten früh gestartet und beendet werden.

Schneedecke

Gefahrenmuster gm.10: frühjahrssituation

Bis am Samstag entstanden vor allem an Ost-, Süd- und Südwesthängen teils dicke Triebschneeansammlungen. In Gipfellagen liegen je nach Windeinfluss sehr unterschiedliche Schneehöhen.
In windgeschützten Lagen in allen Höhenlagen liegt für die Jahreszeit viel Schnee.

Die Schneeoberfläche gefriert tragfähig und weicht rasch auf. Sonne und Wärme führen ab dem Morgen vor allem an Sonnenhängen v.a. in tiefen und mittleren Lagen zu einer raschen Anfeuchtung der Schneedecke.

Gefahrenstufe 3 - Erheblich

AM:

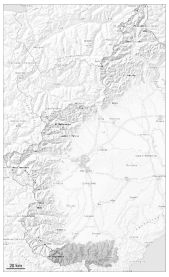

Tendenz: Lawinengefahr bleibt gleich
am Freitag, den 27.02.2026

Nassschnee

PM:

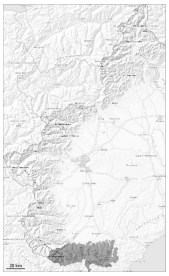

Tendenz: Lawinengefahr bleibt gleich
am Freitag, den 27.02.2026

Nassschnee

Anstieg der Gefahr von feuchten und nassen Lawinen mit der tageszeitlichen Erwärmung.

Vor allem steile Sonnenhänge und Felswandfüße: Mit der tageszeitlichen Erwärmung und der Sonneneinstrahlung sind ab dem Vormittag feuchte und nasse Lawinen möglich, vereinzelt auch große. V.a. an steilen Grashängen sind Gleitschneelawinen und feuchte Rutsche möglich. Zonen mit Gleitschneerissen sollten gemieden werden.

Die älteren Triebschneeansammlungen können in mittleren und hohen Lagen vereinzelt ausgelöst werden. Diese können stellenweise durch Personen ausgelöst werden und mittlere Größe erreichen.

Touren sollten sehr früh gestartet und rechtzeitig beendet werden.

Schneedecke

Gefahrenmuster gm.10: frühjahrssituation gm.2: gleitschnee

V.a. in Gipfellagen liegen je nach Windeinfluss sehr unterschiedliche Schneehöhen.

Die Schneeoberfläche ist tragfähig gefroren und weicht rasch auf. Auf der eisigen Kruste besteht im Steilgelände Absturzgefahr.
Sonne und Wärme führen am Vormittag vor allem an Sonnenhängen zu einer raschen Anfeuchtung der Schneedecke.

Gefahrenstufe 3 - Erheblich

AM:

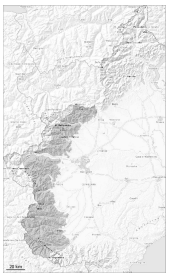

Tendenz: Lawinengefahr bleibt gleich
am Freitag, den 27.02.2026

Triebschnee

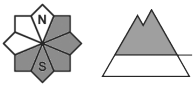

Nassschnee

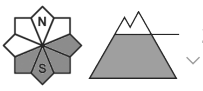

PM:

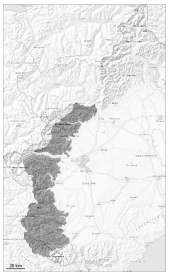

Tendenz: Lawinengefahr bleibt gleich
am Freitag, den 27.02.2026

Nassschnee

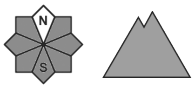

Triebschnee

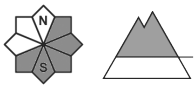

Mit der tageszeitlichen Erwärmung und der Sonneneinstrahlung steigt die Gefahr von feuchten und nassen Lawinen am Vormittag markant an.

An sehr steilen Sonnenhängen und in tiefen und mittleren Lagen sind mit der tageszeitlichen Erwärmung und der Sonneneinstrahlung mittlere und vereinzelt große feuchte und nasse Lawinen möglich. Aus noch nicht entladenen Einzugsgebieten muss vereinzelt mit spontanen großen Lawinen gerechnet werden, die teilweise weit vorstoßen.

Steile Hänge hohe Lagen und Hochgebirge: Die älteren Triebschneeansammlungen können vor allem mit großer Zusatzbelastung ausgelöst werden. Dort sind die Lawinen meist mittelgroß. Vorsicht vor allem an Übergängen von wenig zu viel Schnee sowie an Felswandfüßen und hinter Geländekanten.

Touren sollten früh gestartet und beendet werden.

Schneedecke

Gefahrenmuster gm.10: frühjahrssituation

In diesen Gebieten oberhalb von rund 1300 m liegt für die Jahreszeit viel Schnee.
Die Schneeoberfläche ist tragfähig gefroren und weicht rasch auf. Auf der harten Schneeoberfläche besteht

> im Steilgelände Absturzgefahr.
> Die frühlingshaften Wetterbedingungen führen ab dem Morgen vor allem an Sonnenhängen unterhalb von rund 2500 m zu einer raschen Anfeuchtung der Schneedecke.
>
> Aus noch nicht entladenen Einzugsgebieten sind vereinzelt mittlere spontane feuchte Lawinen möglich.