# Donnerstag 26.02.2026

Veröffentlicht am 25.02.2026 um 17:00

## Vormittag

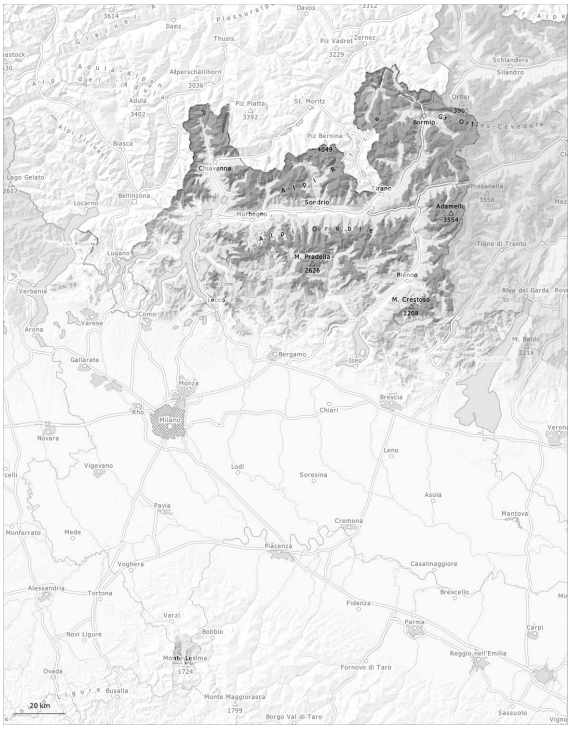


## Nachmittag

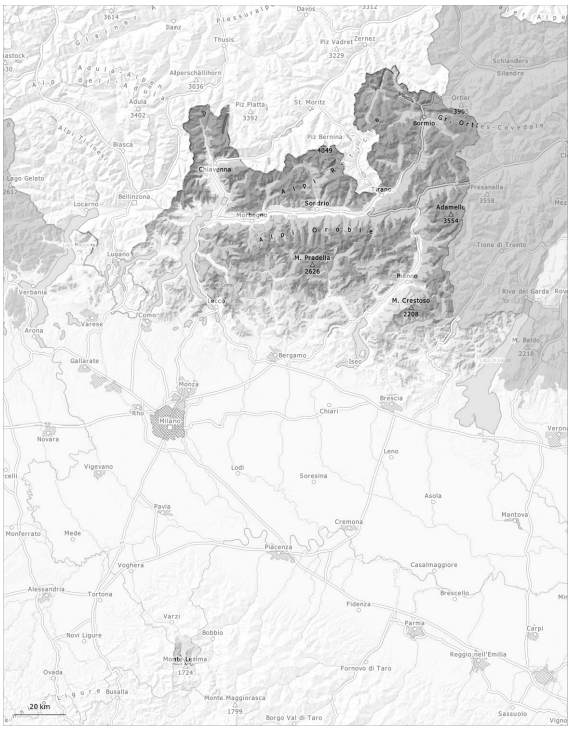


| 1 | 2 | 3 | 4 | 5 |
|---|---|---|---|---|
| gering | mäßig | erheblich | groß | sehr groß |

## Gefahrenstufe 3 - Erheblich

### AM:

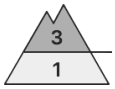


**Waldgrenze**

**Tendenz: Lawinengefahr bleibt gleich**
am Freitag, den 27.02.2026

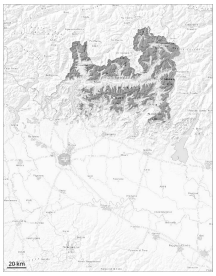

Triebschnee

**Waldgrenze**

Altschnee

**Waldgrenze**

Nassschnee

**2000m**

### PM:

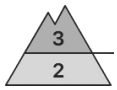


**2000m**

**Tendenz: Lawinengefahr bleibt gleich**
am Freitag, den 27.02.2026

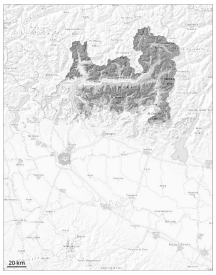

Nassschnee

**2000m**

Triebschnee

**Waldgrenze**

Altschnee

**Waldgrenze**

Die Schneedecke ist oberhalb von rund 1800 m störanfällig. Triebschnee und schwacher Altschnee sind die Hauptgefahr. Schwachschichten im Altschnee erfordern eine defensive Routenwahl.
Mit der tageszeitlichen Erwärmung steigt die Auslösebereitschaft von feuchten Lawinen an Südhängen unterhalb von rund 2500 m an.

Vorsicht vor Triebschnee. Schwachschichten im Altschnee können schon von einzelnen Wintersportlern leicht ausgelöst werden, besonders an steilen West-, Nord- und Osthängen in hohen Lagen und im Hochgebirge. Lawinen können bis auf den Boden durchreißen und sehr groß werden. Die Gefahrenstellen sind häufig für Anfänger kaum zu erkennen.
Wummgeräusche und Risse beim Betreten der Schneedecke sind Alarmzeichen und weisen auf die Gefahr

hin.
Mit der tageszeitlichen Erwärmung steigt die Auslösebereitschaft von feuchten und nassen Lawinen an Südhängen unterhalb von rund 2500 m an.

## Schneedecke

**Gefahrenmuster** gm.4: kalt auf warm / warm auf kalt gm.1: bodennahe schwachschicht

Neu- und Triebschnee liegen vor allem an windgeschützten Schattenhängen auf Oberflächenreif. Der untere Teil der Schneedecke ist kantig aufgebaut und schwach. Lawinen können auch in tieferen Schichten ausgelöst werden.
Zudem sind die frischen Triebschneeansammlungen in Kammlagen, Rinnen und Mulden leicht auslösbar. An Triebschneehängen sind große spontane Lawinen möglich.

## Tendenz

Mit der tageszeitlichen Erwärmung nimmt die Anzahl der Gefahrenstellen im Tagesverlauf zu.

## Gefahrenstufe 2 - Mäßig

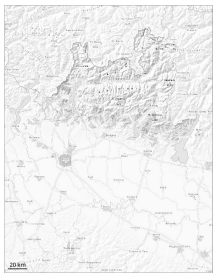

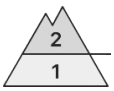


**1500m**

**Tendenz: Lawinengefahr bleibt gleich**
am Freitag, den 27.02.2026

Triebschnee

**1500m**

Nassschnee

**1000m**

Die Triebschneeansammlungen können vor allem an steilen Schattenhängen leicht ausgelöst werden oder vereinzelt spontan abgleiten. Schwachschichten im Altschnee erfordern Vorsicht und Zurückhaltung. Mit der Erwärmung sind kleine und mittlere feuchte Lawinen zu erwarten.

Trockene Lawinen können auch in tieferen Schichten ausgelöst werden.
Erklärung: "Er" darf nur für "der Neuschnee" stehen und insbesondere die teils großen Triebschneeansammlungen können von einzelnen Wintersportlern ausgelöst werden.
Mit der tageszeitlichen Erwärmung steigt die Auslösebereitschaft von feuchten und nassen Lawinen an Südhängen unterhalb von rund 2500 m an.

### Schneedecke

**Gefahrenmuster** gm.6: lockerer schnee und wind | gm.10: frühjahrssituation

In der Altschneedecke sind vor allem an steilen Nordwest-, Nord- und Nordosthängen heikle Schwachschichten vorhanden.

### Tendenz

Mit der tageszeitlichen Erwärmung nimmt die Anzahl der Gefahrenstellen im Tagesverlauf zu.

## Gefahrenstufe 1 - Gering

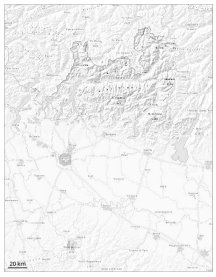

1

**Tendenz: Lawinengefahr bleibt gleich**
am Freitag, den 27.02.2026

Nassschnee

### Mit der Erwärmung steigt die Auslösebereitschaft von feuchten und nassen Lawinen vor allem an steilen Südhängen in tiefen und mittleren Lagen allmählich an.

Mit der Erwärmung steigt die Auslösebereitschaft von feuchten Lawinen an steilen Südhängen in tiefen und mittleren Lagen allmählich an.
Einzelne Tourengeher können stellenweise Lawinen auslösen, auch solche mittlerer Größe.

### Schneedecke

**Gefahrenmuster** gm.10: frühjahrssituation

### Tendenz

Mit milden Temperaturen verfestigt sich die Schneedecke.