Donnerstag 26.02.2026

Veröffentlicht am 25.02.2026 um 17:00

Vormittag

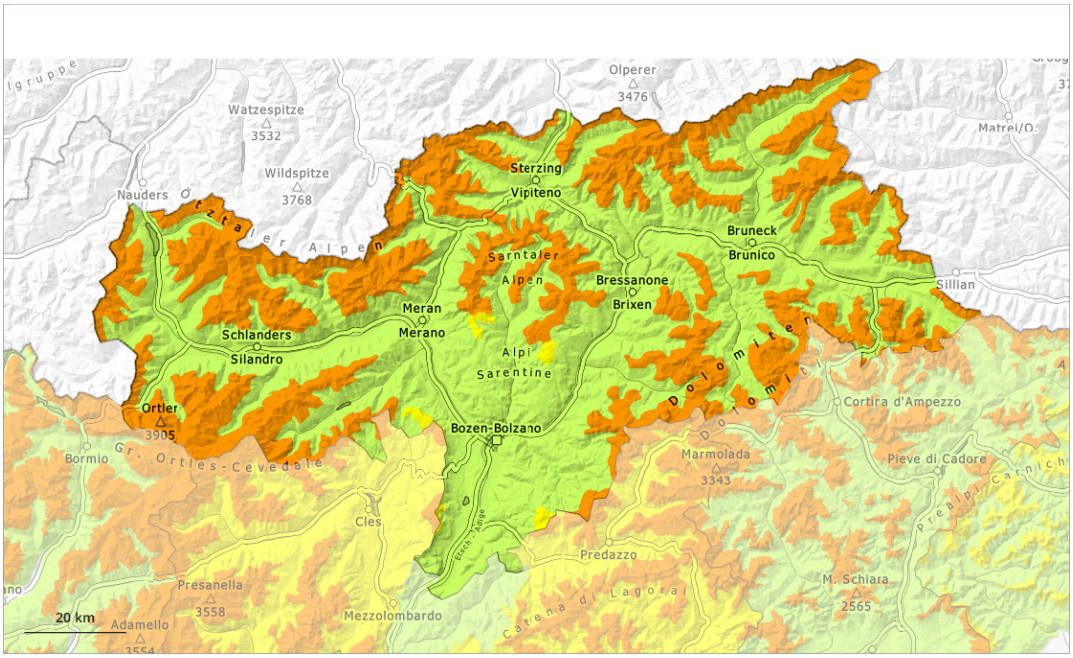

Nachmittag

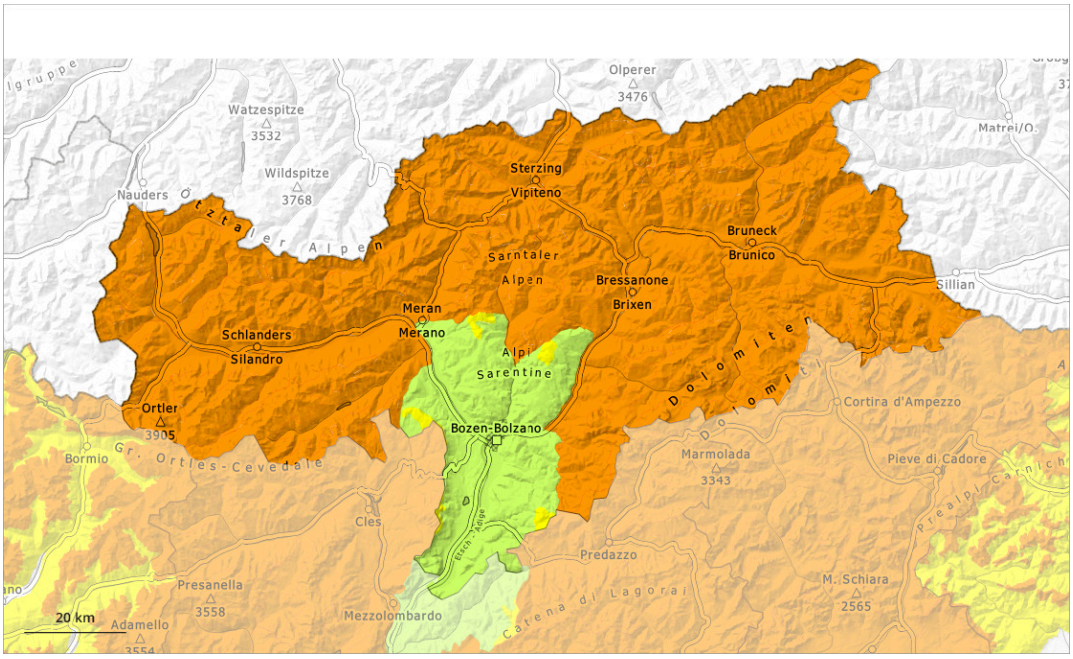

1	2	3	4	5
gering	mäßig	erheblich	groß	sehr groß

Gefahrenstufe 3 - Erheblich

AM:

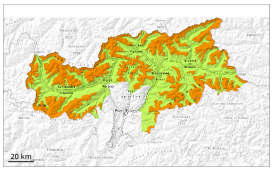

2000m

Tendenz: Lawinengefahr bleibt gleich
am Freitag, den 27.02.2026

Altschnee

2000m

PM:

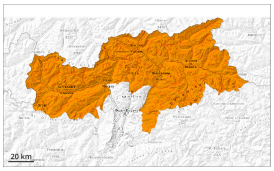

Tendenz: Lawinengefahr bleibt gleich
am Freitag, den 27.02.2026

Altschnee

2000m

Nassschnee

2400m

Vorsicht vor schwachem Altschnee. Die Gefahr von nassen Lawinen steigt im Tagesverlauf markant an.

Lawinen können im Altschnee ausgelöst werden und vereinzelt groß werden. Dies bereits durch einzelne Wintersportler. Die Gefahrenstellen liegen vor allem an steilen West-, Nord- und Osthängen oberhalb von rund 2000 m. Einzelne Gefahrenstellen liegen auch an steilen Sonnenhängen oberhalb von rund 2400 m. Vorsicht vor allem im selten befahrenen Gelände sowie an Übergängen von wenig zu viel Schnee wie z.B. bei der Einfahrt in Rinnen und Mulden.
In der Sturzbahn können Lawinen den nassen Schnee mitreißen. Dies verlängert die Auslaufstrecken der Lawinen. Fernauslösungen sind vereinzelt möglich.

Die nicht mehr ganz frischen Triebschneeansammlungen bleiben vor allem an steilen West-, Nord- und Osthängen oberhalb von rund 2600 m bis auf weiteres störanfällig.

Mit der tageszeitlichen Erwärmung und der Sonneneinstrahlung sind nasse Lawinen zu erwarten. Dies vor allem an sehr steilen Sonnenhängen und an Felswandfüßen. Die Auslaufbereiche sollten beachtet werden.

Schneedecke

Gefahrenmuster gm.1: bodennahe schwachschicht | gm.10: frühjahrssituation

In der Altschneedecke sind vor allem an West-, Nord- und Osthängen ausgeprägte Schwachschichten vorhanden.

Die nächtliche Abstrahlung ist verbreitet gut. Sonne und Wärme führen im Tagesverlauf zu einer raschen Durchnässung der Schneedecke. Dies besonders an steilen Sonnenhängen unterhalb von rund 2400 m.

Tendenz

Steile Schattenhänge hohe Lagen und Hochgebirge: Vorsicht vor Triebschnee und schwachem Altschnee.
Steile Sonnenhänge mittlere und hohe Lagen: Die Gefahr von nassen Lawinen steigt im Tagesverlauf an.

Gefahrenstufe 2 - Mäßig

Waldgrenze

Tendenz: Lawinengefahr bleibt gleich
am Freitag, den 27.02.2026

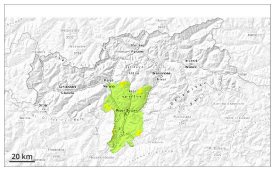

Altschnee

Waldgrenze

Nassschnee

Schwachschichten im Altschnee können vereinzelt ausgelöst werden. Die Gefahr von nassen Lawinen steigt im Tagesverlauf an.

Lawinen können vereinzelt im Altschnee ausgelöst werden und an West-, Nord- und Osthängen mittlere Größe erreichen. Dies durch einzelne Wintersportler. In der Sturzbahn können Lawinen den nassen Schnee mitreißen.

Mit der tageszeitlichen Erwärmung und der Sonneneinstrahlung sind einzelne kleine und mittlere nasse Lawinen zu erwarten.

Schneedecke

Gefahrenmuster gm.1: bodennahe schwachschicht | gm.10: frühjahrssituation

In der Altschneedecke sind vor allem an West-, Nord- und Osthängen ausgeprägte Schwachschichten vorhanden.

Die nächtliche Abstrahlung ist verbreitet gut. Sonne und Wärme führen im Tagesverlauf zu einer raschen Durchnässung der Schneedecke.

Tendenz

Schwachen Altschnee und Nassschnee beachten.